MÅL

Målet är att ni ska ta era första steg mot att kunna:

- läsa en karta
- använda karta och kompass i terrängen

SYFTE

Syftet är för att ni ska kunna

- orientera er på en karta
- orientera er i terrängen med hjälp av en karta.

KRAV

Kravet är att ni ska känna till och ha viss förståelse i ATT:

- kartor har en kartskala (ex 1:50 000)
- kartor har fyra grundriktningar (ex NORR) och
- kartor har symboler (ex väg).

Ni ska med hjälp "tumregeln" kunna ta er från en punkt (ex 1) till en annan (ex 2) i terrängen med hjälp av karta och kompass.

Kartskalor

En enkel tumregel vid omvandling av skalan:
Stryk de två sista siffrorna i skalan. Du får då centimeter på kartan översatt till meter i terrängen.
Till exempel 1:50 0~~00~~ (1 cm = 500 m)

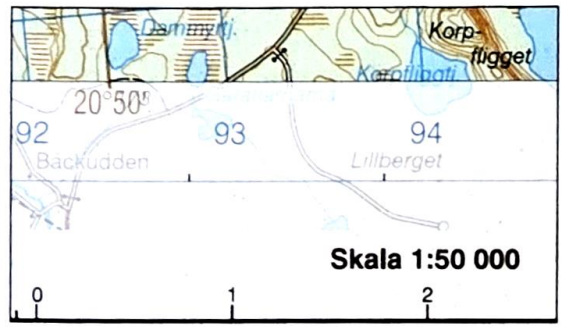

Höjdkurvor

Ekvidistans (*eng Contour*) är nivåskillnader i meter mellan två höjdkurvor på kartan. NMK50 har 5 meters ekvidistans.

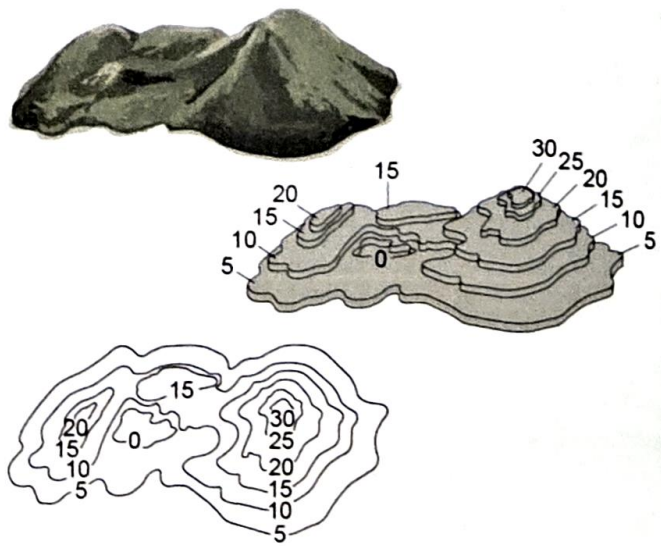

Skissritning och fotografier

Exempel på skiss

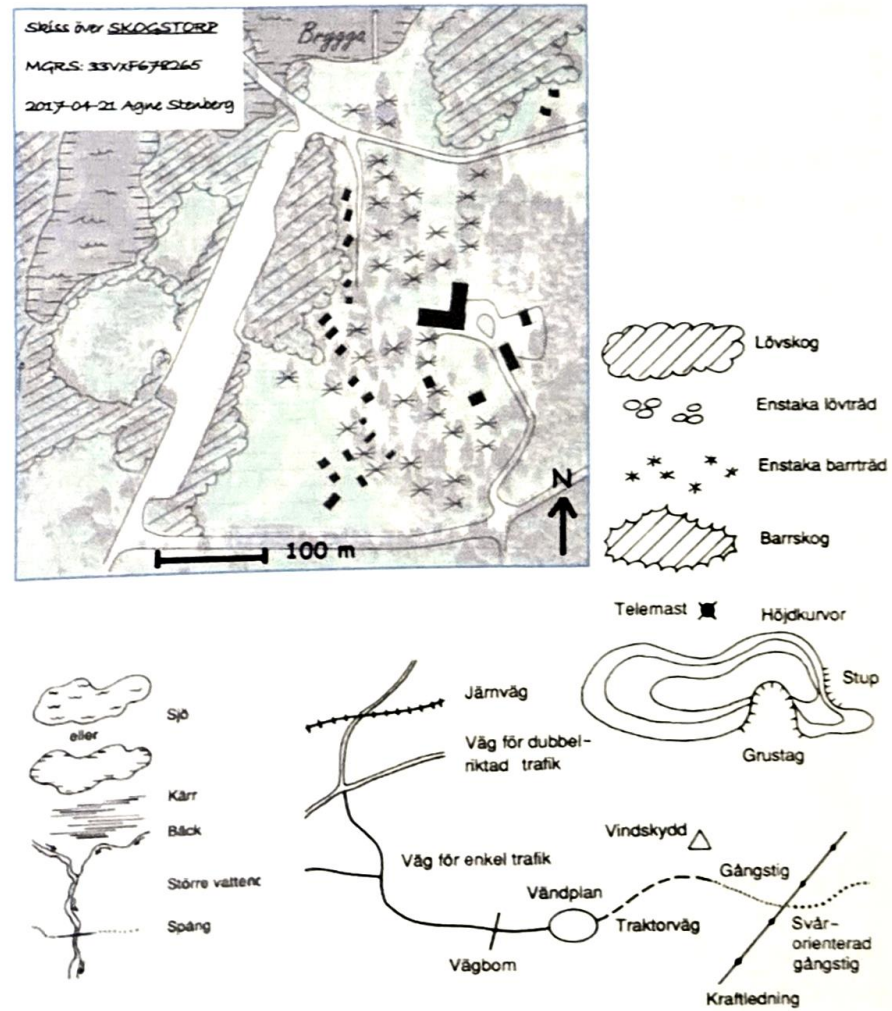

Notera. Bilder och ortofoton (flygbilder) är komplement och/eller alternativ till kartor. De är även bra underlag för skisser.

Kartläsning

Passa kartan – orientera kartan mot norr

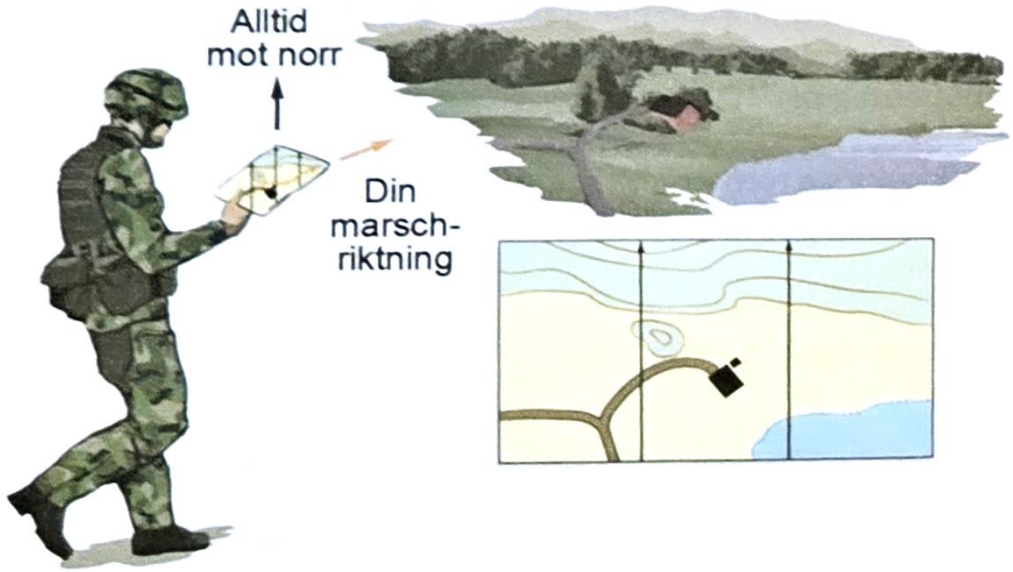

Fakta!
Kartans texter är alltid rättvända relativt kartans norr.

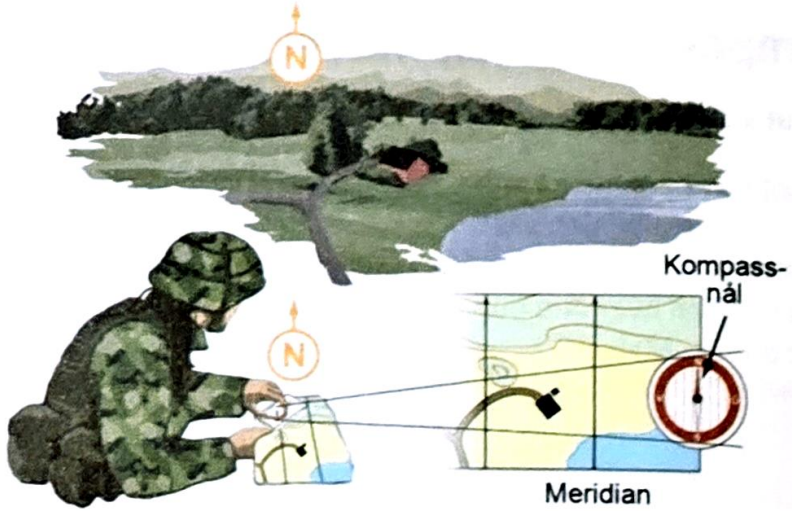

Kartan är passad med hjälp av kompassnålen.

Tumgreppet

Med hjälp av tumgreppet markerar du var på kartan du befinner dig. Tumgreppet används för att underlätta kartläsning under förflyttning.

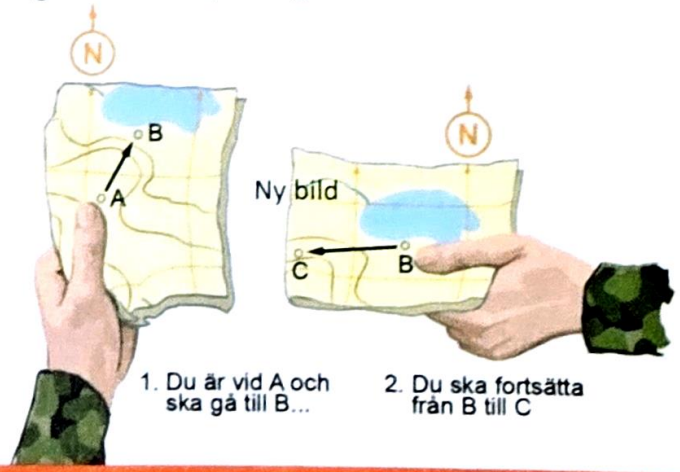

Observera!
Vrid inte på kartan! Håll kartan mot norr och flytta dig själv i förhållande till kartan i stället.

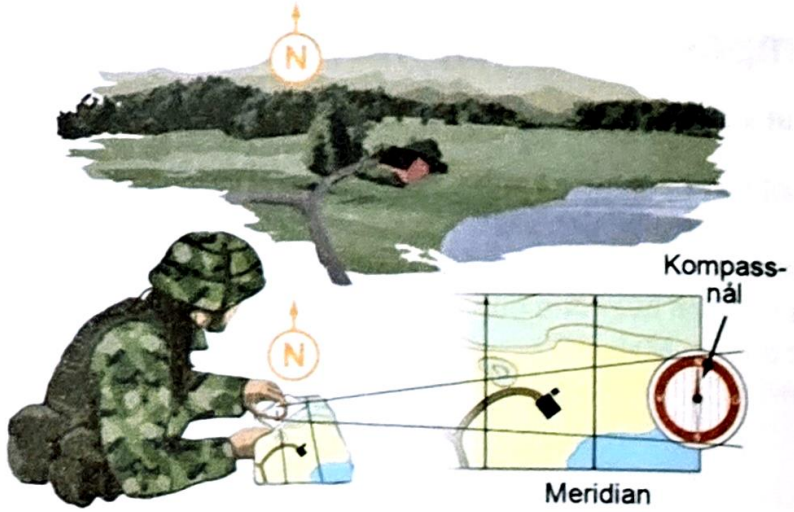

Kartan är passad med hjälp av kompassnålen.

Tumgreppet

Med hjälp av tumgreppet markerar du var på kartan du befinner dig. Tumgreppet används för att underlätta kartläsning under förflyttning.

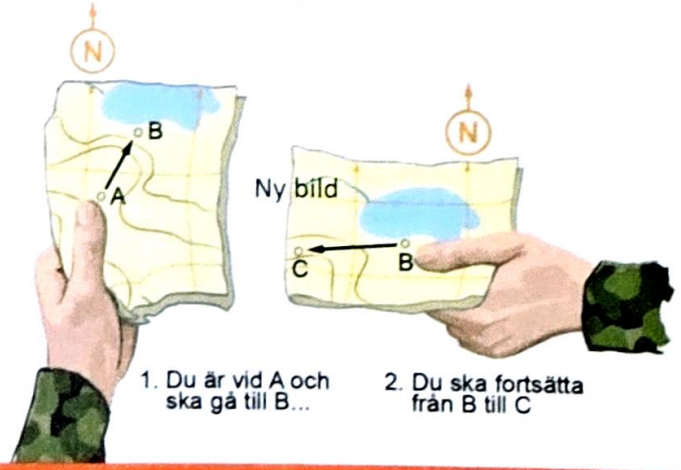

1. Du är vid A och ska gå till B...

2. Du ska fortsätta från B till C

Observera!
Vrid inte på kartan! Håll kartan mot norr och flytta dig själv i förhållande till kartan i stället.

JAG VISAR



Kompassen – hjälpmedel för kartläsning

Ta ut kompassriktning

1. Lägg kompassen på kartan med ena hjälplinjen eller kanten över den punkt där du står och över den punkt dit du ska. Marsch-riktningspilen ska peka åt det håll du ska förflytta dig.

2. Vrid kompasshuset så att N pekar mot kartans norr. Kompasshusets hjälplinjer blir då parallella med meridianerna.

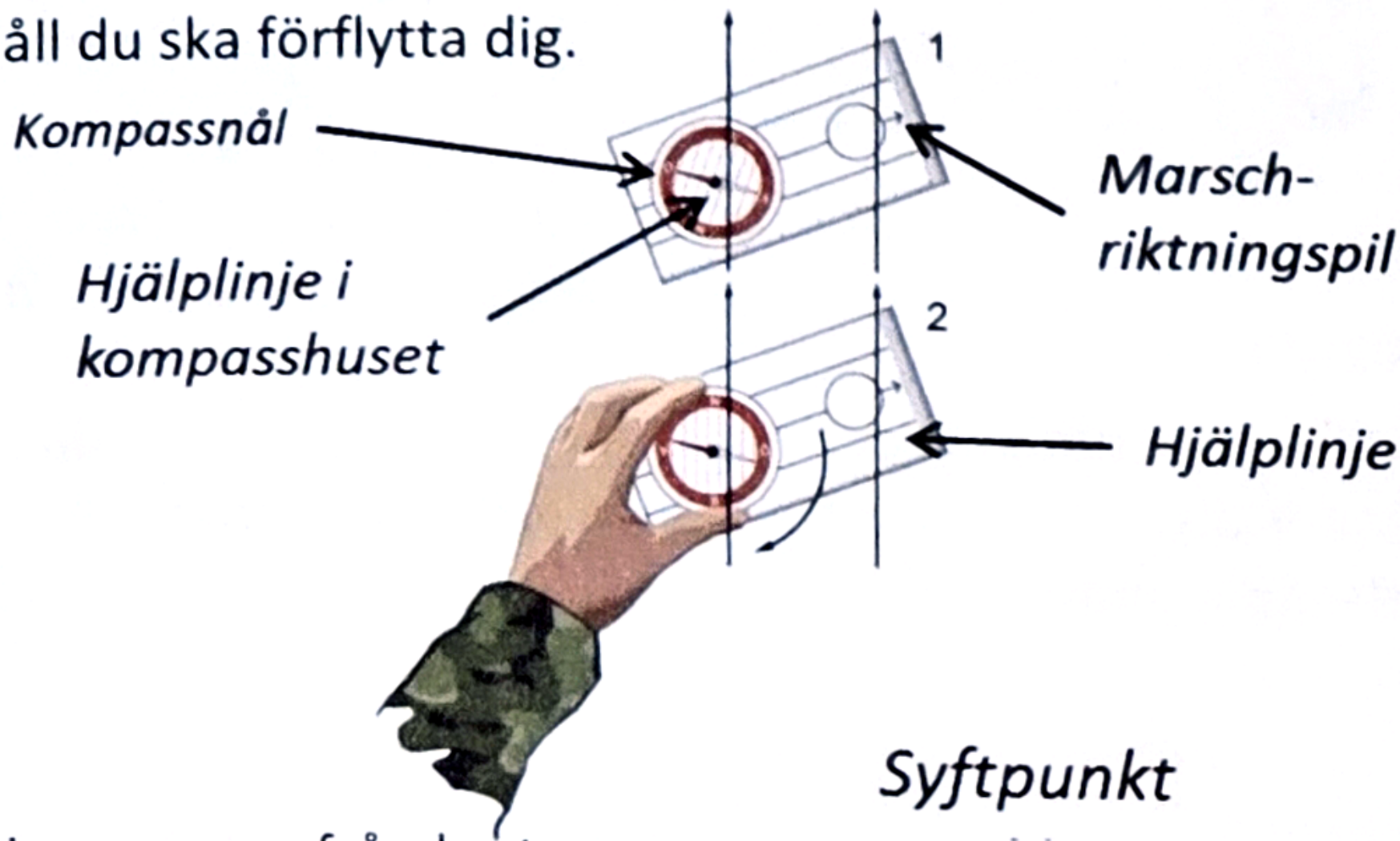

3. Lyft kompassen från kartan och håll den vågrätt framför dig. Vrid kompassen så nålen pekar mot N på kompasshuset.

4. Välj en syftpunkt i terrängen i linje med marschriktnings-pilen. Förflytta dig till den punkten och välj sedan ny syftpunkt på samma sätt.

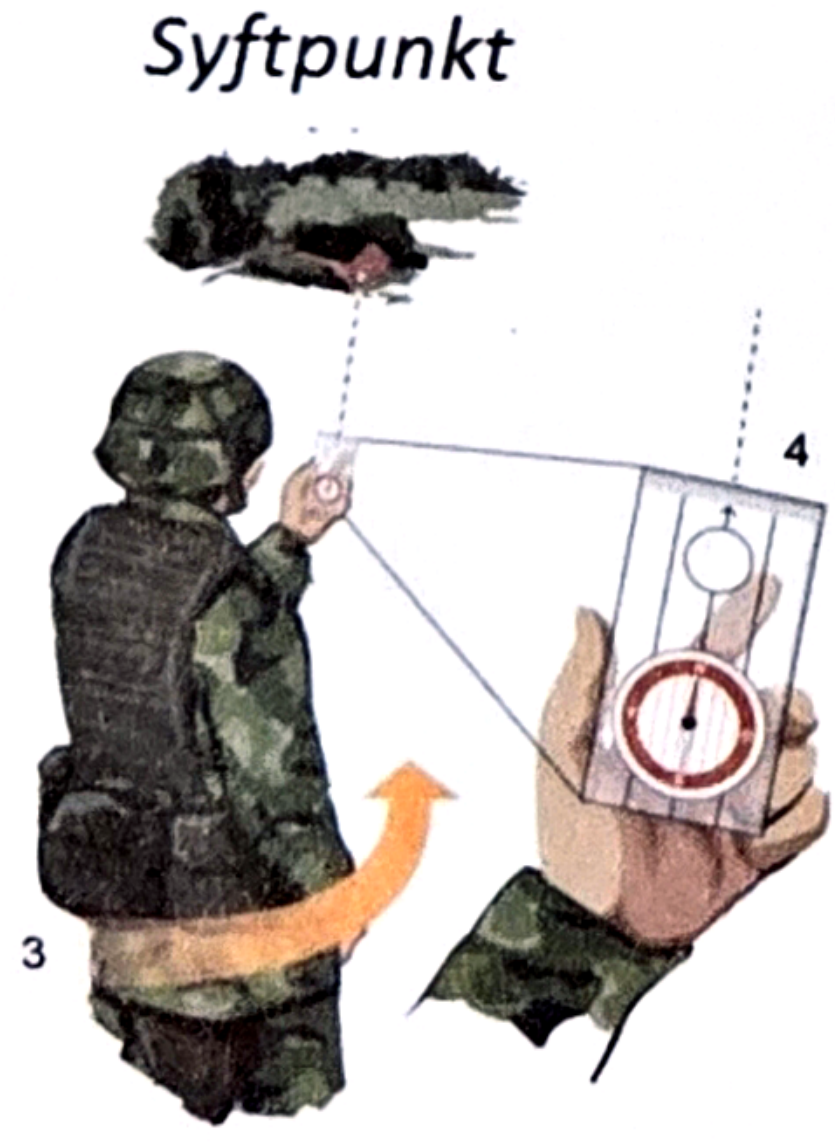

Har vi tid att gå ut?

- Dela in er i par
- Kanske någon blir själv

- Välj ut att ta er mellan två punkter på kartan
- Använd er av tumregeln samt kompass
- Tänk på att alltid rikta kartans norr mot det riktiga norr
- Snurra er själva runt kartan

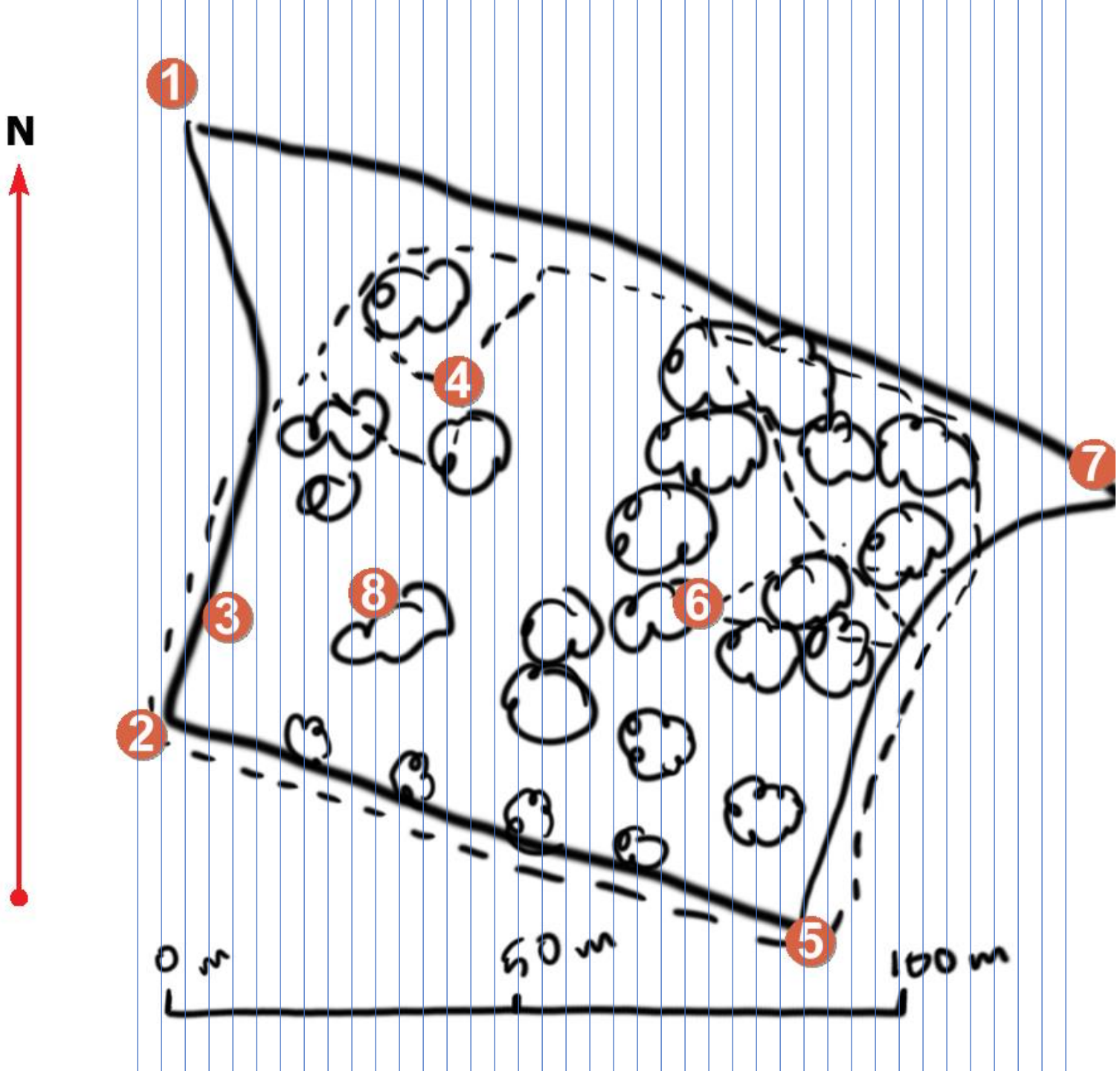
N
1
2
3
4
5
6
7
8
0 m
50 m
100 m