Datum
2025-12-08

[redacted]

Current Operations

Figur 7 Gränssnitt för Current Operations.

Plans & Orders

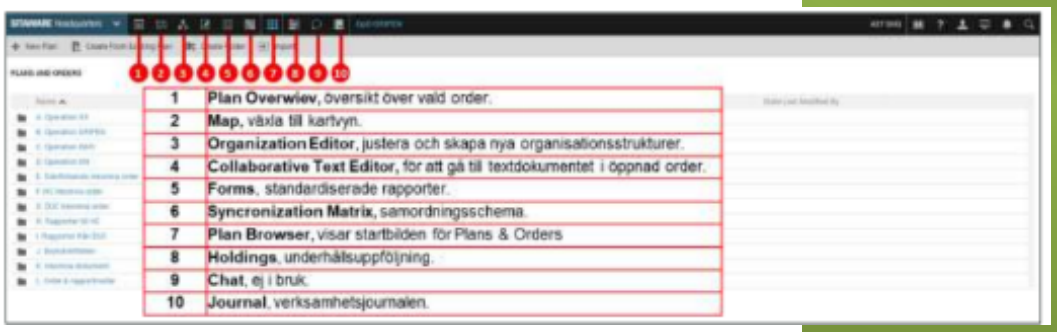

Ronnie Heidenborn

Syfte och omfattning av dokumentet

Syftet med detta dokument är att skapa en ledstång vid utbildning av stabsmedlemmar i staber som nyttjar SitaWare (ver 6.x). Dokumentet innehåller de vanligast förekommande SitaWare HQ åtgärder som en stabsmedlem behöver kunna bemästra.

Dokumentet kan nyttjas vid lärarledd utbildning eller vid självstudier i tillämpliga delar.

Innehåll

Syfte och omfattning av dokumentet 1
1. Förberedelser 2
1.1. Allmänt 2
1.2. Utbildningsmiljö 2
1.3. Elevförberedelser 3
2. Övningsmoment 4
2.1. Navigera i gränssnittet Current Operations 4
2.2. Navigera i gränssnittet Plans & Orders 5
2.3. Personliga inställningar 6
2.4. Grundläggande karthantering 6
2.5. Lägesbild 7
2.6. Geo Tools 8
2.7. Journal 9
2.8. Plans & Orders 10
2.9. Sökfunktion 12
2.10. Bookmarks 12
2.11. Forms 13
2.12. Presentation 14
2.13. ORBAT 15
2.14. Övrigt avancerat 15
3. Gränssnitts test 17

1. Förberedelser

1.1. Allmänt

Momenten görs i nummerordning då vissa moment bygger på tidigare genomförda moment.

Efter genomgången utbildning behöver den kompletteras med tillämpning för aktuell stab. Det vill säga styrningar ur stående stabsorder för hur lägesbilden, orderarbete, meddelandehantering, rapportering et cetera skall hanteras inom staben samt informationsutbytet med andra staber.

1.2. Utbildningsmiljö

Utbildningsmiljön bör omfatta följande:

- Inläst grunddata från LedInfoSE (Layers, Pictures, Bookmarks, ORBAT, Symbol Toolbox, etc).
- Konfigurerat Sitaware HQ avseende *Plans & Orders* folders, X: med filträd, *Journalen* med Taggar, etc.
- En grund *Bookmark* som ger en start bild omfattande lämplig karta och Pictures med layers.
- En folder i *Plans & Orders* som heter **[eget namn]** och som innehåller en OpO med ett huvuddokument, ett antal plan-layers samt ett exceldokument.
- En dokumentfolder *Självstudie*, därunder man skapa en egen folder som heter **[eget namn].**

1.3. Elevförberedelser

Under utbildningen nyttjas anropssignaler med befattningsnummer enl FAL-A enligt nedan:

Nr	Funktion/Befattning	Nr	Funktion/Befattning
1	Chef	**40**	**Underhåll/Logistik**
2	Ställföreträdande chef	41	Chef/kvartersmästare
3	Stabschef	48	Teknisk chef
4	Förvaltare	42-47,49	Underhålls/logistikbefattningar
5-9	Gemensamma befattningar	**50**	**Fältarbeten**
10	**Personal**	51	Chef
11	Personalchef	52-54	Fältarbetsbefattningar
12-19	Personalbefattningar	**55**	**Luft**
20	**Underrättelse- och säkerhet**	56	Chef
21	Chef	57-59	Luftbefattningar
22-29	Underrättelse- och säkerhetsbefattningar	**60**	**Samband/ledningssystem**
30	**Stridsledning**	61	Chef
31	Chef	65	Signalskyddschef
32-34	Stridsledningsbefattningar	62-64, 66-69	Sambands/ledningssystemsbefattningar
35	**Bekämpning**	**70-79**	**Nätdrift**
36	Chef	**80-89**	**Sjukvårdsledning**
37-39	Bekämpningsbefattningar	**90-99**	**Reserv**

Börja med att logga in i systemet och starta Sitaware HQ. Gå till *Bookmarks* och öppna BB. GRUND BG01 Strastbild. Stäng därefter appen *Bookmark* så att hela kartan syns.

Momenten inleds med en referens till Imstruktion SitaWare HQ 6.9 . I de fallen att ingen relevant anvisning finns hänvisas till den inbyggda hjälpfunktionen alternativt *SitaWare Headquarters User Manual*.

Öppna hjälpfunktionen (*Help*). Den öppnas som en separat flik.

Alla stabsmedlemmar bör genomföra övningsmoment 2.1 till och med 2.13 samt avsluta med övningsmoment 3.

Administratörer/IMO bör också genomföra övningsmoment 2.14 och 2.15

Öppna *Current Operations* och genomför övningsmomenten.

2. Övningsmoment

2.1. Navigera i gränssnittet Current Operations

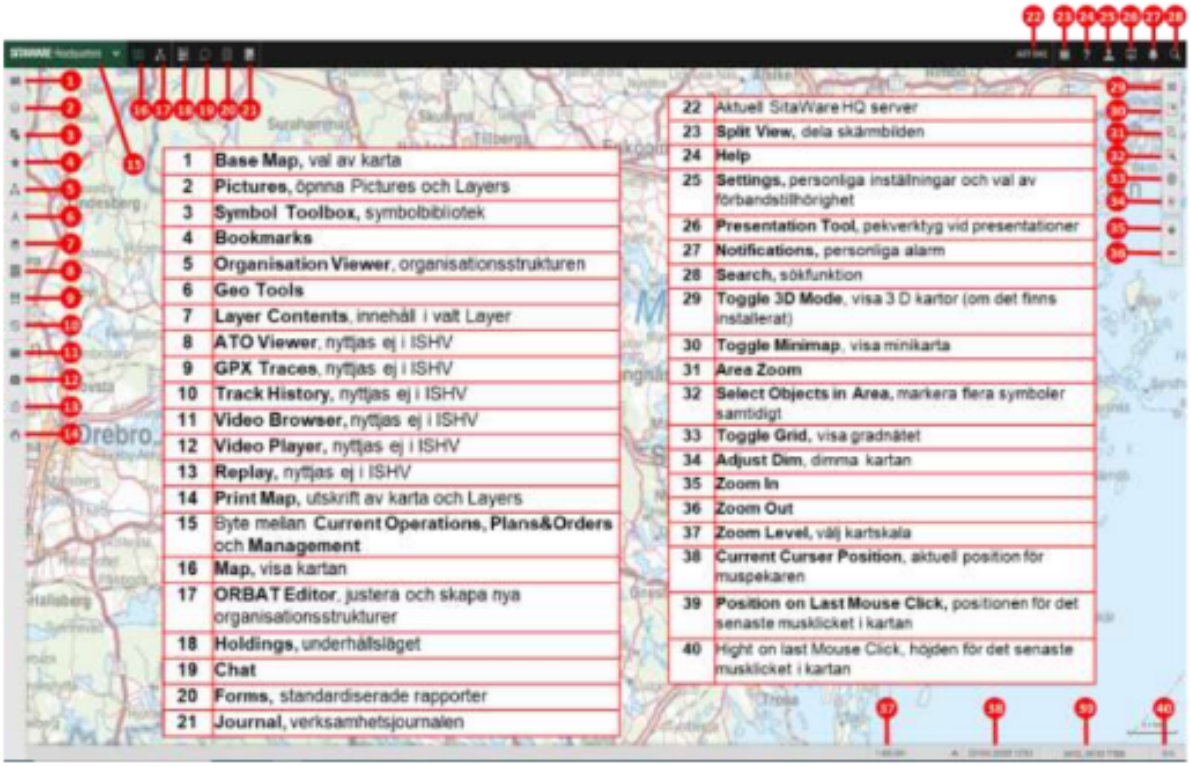

Navigera runt i gränssnittet genom att föra muspekaren över respektive app för att identifiera var olika appar återfinns i *Current Operations*. Avsluta med att stänga alla appar så att endast kartbilden syns.

2.2. Navigera i gränssnittet Plans & Orders

Byt från *Current Operations* till *Plans & Orders*.

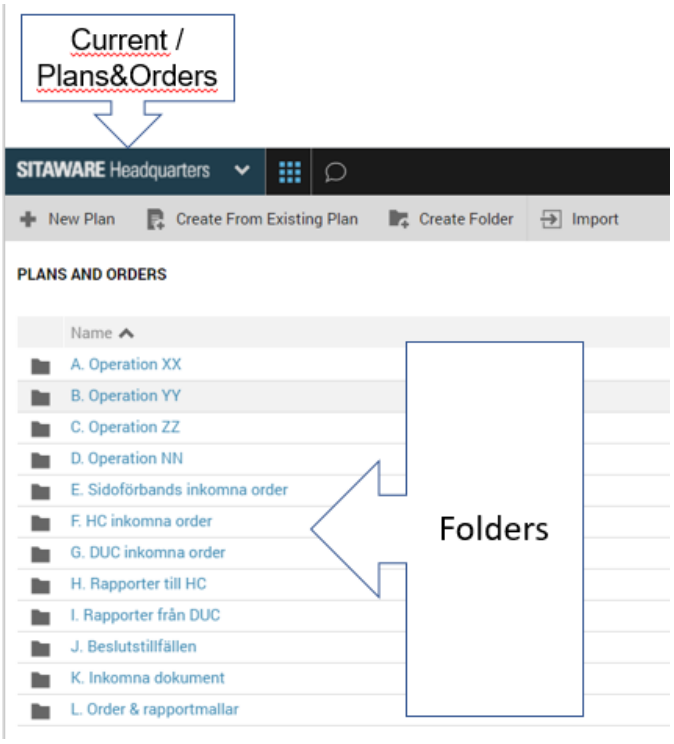

Navigera runt i foldrarna, avsluta med att öppna folder **[eget namn],** skapa en OpO med huvuddokument, lager för Målbild, GFI, Gränser och SLO.

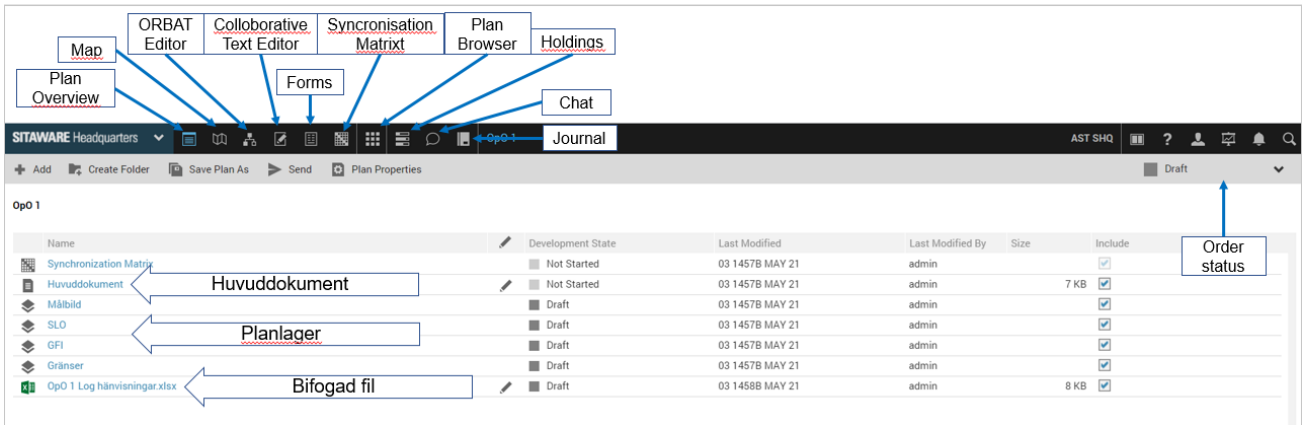

Navigera runt i gränssnittet genom att föra muspekaren över respektive app för att identifiera var olika funktioner återfinns i *Plans & Orders*. Avsluta med att gå tillbaka till *Plan Browser* för att se samtliga delar i OpO.

Gå till *Current Operations* och genomför kommande övningsmoment.

2.3. Personliga inställningar

Anvisning	Instruktion ISHv SitaWare HQ

Mom	Verksamhet	Klart
1	Öppna appen *Settings* / *User Settings*	
2	Kontrollera i *General* att positionsformatet är MGRS.	
3	Kontrollera i *General* att *Browser Navigation* är *Use existing browser tab.*	
4	I *Symbols* ställ in *Size on map* och skala 1:2500 000 samt bocka ur *Always expand Report Dialog.*	
5	I *Labels* ställ in *Label Size* och skala 1:2500 000.	
6	Avsluta med att välja *Save* för att spara inställningarna.	

2.4. Grundläggande karthantering

Anvisning	Help-funktionen/ Instruktion ISHv SitaWare HQ

Mom	Verksamhet	Klart
1	Kontrollera vilka kartor som finns i systemet. Vid behov byt karta. **Tips:** Detta görs i appen *Base Map*.	
2	Justera kartan genom att:	
	a. Zooma in och ut ur kartan (både med mus och med *Mini Map* verktygen).	
	b. Ändra skalan till 1:250 000. **Tips:** Görs längs ner i gränssnittet i *Location Tool*.	
	c. Tänd och släck rutnätet. **Tips:** Görs vid *Mini Map Panel.*	
	d. Justera ljusstyrkan för kartan. **Tips:** Görs vid *Mini Map Panel.*	
3	Ange vad som finns på koordinaten: 33V XF 15601 83641. Zooma in till ca 1:10 000. **Tips:** Skriv in koordinaterna i koordinatfönstret längs ner till höger i gränssnittet, tryck *Enter* för att centrera kartan på angivna koordinater.	
4	Ange koordinaterna för egen stabsplats. **Tips:** Klicka på platsen i kartan och kopiera koordinaterna från koordinatfönstret längs ner till höger i gränssnittet. Kan göras med	

	CTRL+C och sedan kan man klistra in koordinaterna i ett dokument med CTRL+V.	
5	Ange längden på Ölandsbron, i meter, från brofästet Svinö till brofästet Öland. **Tips:** Använd *Geo Tools* / *Range Tool* för att mäta längden.	

2.5. Lägesbild

Anvisning	Help-funktionen/ Instruktion ISHv SitaWare HQ

Mom	Verksamhet	Klart
1	Skapa en egen mapp i *SitaWare HQ/Current/Pictures* i arbetsmappen som finns i din funktions *Picture* **Tips:** Högerklicka på arbetsmappen och välja *Create Picture*. Döp mappen till ditt namn. I mappen skapas egna lager (totalt 5 st enligt nedan) för de uppgifter som behöver detta.	
2	Skapa en lägesbild för en bataljon med fyra kompanier i din arbetsmapp bestående av följande:	
	a. Ett lager **Gränser** med yttre (bataljon) och inre (kompani) förbandsgränser. **Tips:** Högerklicka på egen mapp och välj *Create Layer*. Hämta förbandsgränser från *Symbol Toolbox* flik 06.Linjer.	
	b. Ett lager **DUC** med förbandssymboler (från ORBAT) ner tom kompani. Fyll i en stridsuppgift i kompanisymbolerna. **Tips:** Högerklicka på egen mapp och välj *Create Layer*. Hämta förbandssymbolerna från *Organization Viewer*. Klicka på aktuell förbandssymbol, för in muspekaren på kartan och klicka en gång för att lägga in symbolen. I den öppnade förbandsrapporten fyll i en uppgift i det övre fältet *Enter Additional Info….* Klicka på *Save* och upprepa förfarandet tills alla förband är utlagda i kartan. Behöver ett förband flyttas i kartan så klicka på förbandet så att det får en röd ram, dra därefter förbandet till ny plats med musen.	
	c. Ett lager **UPK** med minst 5 st UPK-er. **Tips:** Högerklicka på egen mapp och välj *Create Layer*. Hämta UPK från *Symbol Toolbox* flik 11.Punkter.	

	d. Ett lager **SLO** med minst 5 st samordningslinjer. **Tips:** Högerklicka på egen mapp och välj *Create Layer*. Hämta samordningslinjer från *Symbol Toolbox* flik 06.Linjer.	
	e. Ett lager **Målbild** med en målbild omfattande frihandsritnings pilar, områden och textrutor. **Tips:** Högerklicka på egen mapp och välj *Create Layer*. Hämta symboler och minst en textruta från *Symbol Toolbox* flik 01.Ritverktyg.	
3	Spara ner lägesbilden i X: som PDF, med alla lager tända. **Tips:** Tänd alla 5 lagren, justera kartan och välj *Print Map* och *Poster mode* (2x2). Fyll i fälten i *Decorations* och avsluta med *Save*. Sparad lägesbild finns nu i *Downloads* och kan flyttas till X:	
4	Kontrollera innehållet i eget lager DUC med *Layer Contents*. Växla mellan olika kolumner. **Tips:** Högerklicka på lagret och välj *Layer Contents*. Byt kolumner via åtgärdsprickarna på höger sida i fönstret (*Select Columns*). Avsluta med att stänga fönstret *Layer Contents*.	

2.6. Geo Tools

Anvisning	Help-funktionen/ Instruktion ISHv SitaWare HQ

Mom	Verksamhet	Klart
1	Använd appen *Geo Tools*: **Tips:** Vid alla mätningar undvik att mäta i skala större än 1:50 000 då mätningen riskerar att ta lång tid att genomföra.	
	a. Välj skala 1: 5000 och mät högsta punkten inom ett område. Radera mätningen.	
	b. Välj skala 1:10 000 och mät siktlinjen för en observatör på 3 m höjd och för ett mål som är 4 m högt. Radera mätningen.	
	c. Välj skala 1:50 000 och skapa räckviddscirklar för 500m, 1000m, 1500m och 2000m. Välj olika färger för resp cirkel.	
	d. Flytta centrum på räckviddscirklarna till ny plats i kartan.	
	e. Dölj räckviddscirklarna (skall ej raderas).	

2.7. Journal

Anvisning	Help-funktionen/ Instruktion ISHv SitaWare HQ

Mom	Verksamhet	Klart
1	Öppna Journalen.	
2	Skapa en civil händelse omfattande en brand i hamnen Oxelösund. Informationen kommer från Lsty Sörmland. **Tips:** Fyll i direkt i fälten och välj *Create*. När händelsen är skapad, öppna den och sätt *Tag 06.HÄNDELSE CIVIL* och välj *Save*.	
3	Skapa en händelse om att stabens dagliga förbandsrapport är skickad till HC. Gör på samma sätt som i moment 2 men välj lämplig *Tag*.	
4	Uppdatera att branden i hamnen Oxelösund nu är släckt. **Tips:** Öppna händelsen genom att dubbelklick på den och uppdatera den och välj *Save*.	
5	Gruppera alla händelser efter tid. **Tips:** Detta görs i kolumnrubrik *Time* och väljer *Group by Time*.	
6	Skriv ut (spara som PDF) alla civila händelser. **Tips:** Markera *Tag 06.HÄNDELSE CIVIL* och klicka på *Print*. Klicka på *Print Preview* och välj PDF och spara filen på X:.	
7	Ändra kategori (*Tag*) för händelsen om branden i hamnen Oxelösund till *99.Arkiv*. **Tips:** Öppna händelsen och byt *Tag*. Klicka på *Save*.	
8	Öppna Journalen och chatten i ett delat fönster. **Tips:** Öppna *Journalen* och därefter välj appen *Split View*. Välj *Chat* i *Split View* fönstret. Stäng *Split View* genom att klicka på appen *Split View*.	

2.8. Plans & Orders

Anvisning	Help-funktionen/ Instruktion ISHv SitaWare HQ

Mom	Verksamhet	Klart
1	Öppna *Plans & Orders*.	
2	Öppna din existerande *Folder* **[eget namn]** i *Plans&Orders.*	
3	Skapa en ny oporder från 5.punktsordern. **Tips:** Välj *Create From Existing Plan* och hämta mallen från mapp *L. Order & Rapport mallar*. Välj med interna bilagor.	
4	Döp din order till din befattning.	
5	~~Säkerställ rätt orderegenskaper (*Properties*) och spara den i egen *Folder*.~~	
6	Fyll i något kort i minst 5 st rubriker/underrubriker i *Huvuddokument* och klarmarkera dessa genom att ändra status till *Approved* (grön). Inga bilagor skall användas.	
7	Lägg till 5 st planlager, döp dessa till **Målbild**, **Gränser**, **GFI**, **UPK** och **SLO**. **Tips:** Görs i *Plan Overview* och ~~via *Add* och där väljs *Layer*.~~	
8	Kopiera symbolerna från de fem lägesbildslagren till respektive planlager. **Tips:** Gå till *Current Operations*. Expandera egen arbetsmapp så att alla egna lager syns. Gå till *Open Picture* och välj *Plans & Orders Pictures*. Välj där din order och klicka på *Open*. Att kopiera symboler mellan lager görs enligt följande: 1. Aktivera lagret som man skall kopiera till genom att dubbelklicka på lagret så ett det får **fetstil** alternativt högerklicka på lagret och välj *Set Active Layer*. Tänd inte lagret, dvs klicka inte i rutan till vänster om lagret. 2. Tänd lagret som man vill kopiera från dvs klicka i rutan till vänster om lagret. Ha endast det lagret tänt. 3. Skall man kopiera en enskild symbol, högerklicka på aktuell symbol och välj *Copy symbol to active layers xxxx*. Kontrollera att det är rätt mål lager som är aktiverat dvs ***xxxx***. 4. Då man kopierar en enskild symbol kommer *Unit Report* att öppnas, välj *Save*. 5. Släck lagret som man kopierat från. Kontrollera att symbolen är kopierad till eget lager	

	6. Skall man kopiera flera symboler samtidigt, använd verktyget *Select objects in area* som finns i *Mini Map* panelen. Markera de symboler som skall kopieras och högerklicka på en av symbolerna och välj *Copy all symbol to active layers xxxx*. Kontrollera att det är rätt mål lager som är aktiverat dvs *xxxx*. 7. Släck lagret som man kopierat från. Kontrollera att symbolerna är kopierad till eget lager. Gå tillbaka till *Plans & Orders* och egen order (*Plan Overview*).	
9	Lägg till ett exceldokument till ordern. **Tips:** Görs i *Plan Overview* och via *Add* och där väljs *File*.	
10	Gör ordern klar för godkännande genom att ändra status på orderpunkter och order delar till *Complete*/gul. (*approved*/grön)	
11	Gör ordern klar för fastställande genom att ändra status på orderpunkter och order delar till A*pproved*/grön.	
12	Fastställ order. Säkerställ att alla orderpunkter och ordern har rätt status (*approved*/grön) innan du fastställer ordern i orderfönstret övre högra hörnet (*Issue Order*).	
13	Skriv ut huvuddokumentet som PDF och spara det i X:. **Tips:** I *Plan Overview* öppna huvuddokumentet och välj *Save as PDF*. Dokumentet hamnar i *Downloads* i utforskaren och kan nu flyttas till X:	
14	Kopiera en inkommen order från *K.Inkommande dokument* till egen *Folder*. **Tips:** Högerklicka på vald order och välj *Copy*. Välj därefter den mapp dit order skall kopieras och välj *Save*.	

2.9. Sökfunktion

Anvisning	Help-funktionen/ Instruktion ISHv SitaWare HQ
	Samtliga moment genomförs i appen *Search.*

Mom	Verksamhet	Klart
1	Sök efter egen stabs hemort och centrera på svaret. **Tips:** Dubbelklicka på svaret för att centrera.	
2	Sök efter ett av dina utlagda förband och centrera på förbandet. **Tips:** Dubbelklicka på svaret för att centrera.	
3	Sök efter din tidigare skapade oporder.	
4	Gå tillbaka till *Current Operations*.	

2.10. Bookmarks

Anvisning	HHA: 6.21, 6.22

Mom	Verksamhet	Klart
1	Skapa en *Bookmark folder*, döp den till eget namn. **Tips:** Klicka på åtgärdsprickarna och välj *Create Bookmark Folder*.	
2	Skapa en *Bookmark* för varje lager (dvs 5 st) från lägesbilden. Döp varje *Bookmark* till samma namn som lagret. **Tips:** Börja med att i *Pictures* släcka alla andra lager och tända eget lager **Gränser**. Zooma in lämpligt område och ev dimma kartan. Gå till *Bookmarks* och öppna egen *Bookmark Folder* och klicka på ikonen *Create Bookmark*. Döp din Bookmark till **Gränser** och klicka på *Create*. Gör om förfarandet för övriga lager.	
3	Spara en PPT från din *Bookmark Folder*. **Tips:** I egen Folder klicka på åtgärdsprickarna och välj *Export to PowerPoint*. Öppna bildspelet samt spara på X:	

4	Skapa en *Bookmark* Oporder med den egna orderns alla lager. **Tips:** Börja med att i *Pictures* släcka alla tända lager och därefter gå till *Open Picture* och välj *Plans & Orders Pictures*. Välj där din order och klicka på *Open*. Tänd alla plan-lager i ordern, zooma in lämpligt område och ev dimma kartan. Gå till *Bookmarks* och öppna egen *Bookmark Folder* och klicka på ikonen *Create Bookmark*. Döp din Bookmark till **Opo** och klicka på *Create*.	
5	Öppna *Bookmark* **Gränser** kontrollera i *Pictures* vilka lager som är tända. Öppna därefter egen *Bookmark* **OpO** och kontrollera i *Pictures* vilka lager som är tända.	
6	Uppdatera *Bookmark* Oporder genom att ta bort **Målbild** och byta karta. **Tips:** Börja med att i *Pictures* släcka lager **Målbild** och därefter byta karta i *Base Map* för att slutligen gå till *Bookmark* **OpO** och högerklicka och välja *Update*.	

2.11. Forms

Anvisning	Help-funktionen/ Instruktion ISHv SitaWare HQ

Mom	Verksamhet	Klart
1	Skapa en *Forms*-rapport (*Own sitrep*) från eget lager **DUC**. **Tips:** Detta görs genom att i *Pictures* högerklicka på eget lager **DUC** och välj *Export to Structured Message*. Välj *OWNSITREP* och klicka på *OK*.	
2	Byt *Reporting Unit* till egen anropssignal och spara rapporten på X: **Tips:** Byt status till *Edit*. Gå till fält *3 Reporting Unit*, skriv in din anropssignal. Klicka på *Validate* för att kontrollera att rapporten är rätt ifylld. Byt status till *Read* samt klicka på *Save As* och välj *Save As Local File*. Filen finns nu i *Download*s och kan flyttas till X:	
3	Skapa ett lager **egen anropssignal +Lägesrapport** (exvis AA60 *Lägesrapport*) i egen mapp i *Pictures*. **Tips:** Gå till *Current Operations* öppna *Pictures* och tidigare skapad mapp. Högerklicka på egen mapp och välj *Create Layer*.	

4	Öppna egen *Forms*-rapport från X: **Tips:** Öppna *Forms* och välj *Open* och *Open Local File*. Markera egen fil från X:.	
5	Importera Forms-rapporten till eget lager **egen anropssignal +Lägesrapport**. **Tips:** När egen forms-rapport är öppnad välj *Import to Map*. Scrolla i *Select Target Layer* och välj eget lager och klicka *OK*.	
6	Kontrollera att förbandssymbolerna nu finns i eget lager **egen anropssignal +Lägesrapport**. **Tips:** I *Pictures* släcks alla andra lager utom eget lager.	
7	Skapa en daglig förbandsrapport i *Forms* från mallen *Unit Report*. **Tips:** I *Forms* gå till *New* och välj *Unit Report*. För att snabbt hitta mallen skriv *Unit Report* i sökfältet. Fyll i rubrik 1 och 2.1. Validera därefter rapporten. Scrolla igenom validerings-kommentarerna.	
8	Spara utkastet till daglig förbandsrapport (*Unit Report*) på X: **Tips:** Gå till *Save As* och välj *Save As Local File*. Filen finns nu i *Download*s och kan flyttas till X:	
9	Anmäl klart i stabens gemensamma chattrum.	

2.12. Presentation

Anvisning	Help-funktionen

Mom	Verksamhet	Klart
1	Förbered en presentation med stöd av *Presentation Tool*:	
	a. Välj en stor gul cirkel.	
	b. Välj en tjock röd linje med 20 s varaktighet.	
2	Prova att nyttja valda inställningar, kontrollera att linjen försvinner.	
3	Anmäl klart i stabens gemensamma chattrum.	

2.13. ORBAT

Anvisning	HHA: 2.2.11

Mom	Verksamhet	Klart
1	Öppna *ORBAT Editor*	
2	Gör en ORBAT för 2.div och döp den till egen anropssignal. Hämta förband från ORBAT FM. Minst två bataljoner och tre st fristående kompanier. **Tips:** Clicka på *Create* och namnge ORBAT och klicka *Create*. Öppna aktuell blå ORBAT i det vänstra fönstret (*ORBAT*). Ha båda fönstren öppna (*ORBAT* och *ORBAT Editor*) hela tiden. I *ORBAT Editor*-fönstret klicka på *Create Unit*, döp symbolen till 2.div, gör den till *unit*, storlek *Division* och *Headquarters Staff* och avsluta med *Create*. Nyttja ”*drag and drop”* för att dra förbanden från *ORBAT*-fönstret till symbolen för 2.div i *ORBAT Editor*-fönstret. Ha tålamod, det tar en stund innan de syns i *ORBAT Editor*-fönstret.	
4	Klicka på *Map* (alternativt *Current Operations*) för att öppna och kontrollera egen ORBAT i *Organisation Viewer*.	
5	Anmäl klart i stabens gemensamma chattrum.	

2.14. Övrigt avancerat

Anvisning	Help-funktionen/ Instruktion ISHv SitaWare HQ Nyttja Help.

Mom	Verksamhet	Klart
1	Skapa ett *Smart Layer* och döp det till dit namn:	
	a. Välj dina egna lager som källa	
	b. Välj att lagret bara skall visa egna bataljonssymboler	
2	Aggregera egna förband enligt följande:	
	a. Skapa ett nytt lager och döp det till **egen anropssignal + Aggregering** (exvis AA 60 Aggregering)	
	b. Kopiera en av brigadsymbolerna från eget DUC lager till aggregeringslagret.	
	c. Aggregera den brigadens alla bataljonssymboler från eget DUC lager till brigadsymbolen i aggregeringslagret.	
	d. Flytta bataljonssymbolerna i eget DUC lager och kontrollera att brigadsymbolen i aggregeringslagret flyttar sig.	

3	Korrelera motståndarförband enligt följande:	
	a. Skapa ett nytt lager och döp det till **egen anropssignal + Korrelering** (exvis AA 60 Aggregering)	
	b. Lägg in fyra st motståndarförband inom ett begränsat område.	
	c. Välj ett av dessa förband och välj att korrelera övriga förband till detta förband.	
	d. Kontrollera vilka korreleringsverktyg som finns i tabellen.	

3. Gränssnitts test

1. Fyll i rätt nummer i tabellen för respektive app.

Nr	App
	GEO-TOOLS
	ORGANISATION VIEWER
	LAYER CONTENTS
	GPX-TRACES
	PRINT MAP
	BASE MAP
	SYMBOL TOOLBOX
	BOOKMARKS
	TRACK HISTORY
	PICTURES
	VIDEO BROWSER
	VIDEO PLAYER
	REPLAY
	ATO VIEWER



Nr	App
	TOGGLE 3D MODE
	ZOOM OUT
	ADJUST DIM
	AREA ZOOM
	TOGGLE MINI MAP
	ZOOM IN
	SELECT OBJECTS IN AREA
	TOGGLE GRID

Nr	App
	SEARCH
	SPLIT VIEW
	SETTINGS
	HELP
	NOTIFICATIONS
	PRESENTATION TOOL

Nr	App
	ORBAT EDITOR
	FORMS
	HOLDINGS
	MAP
	CHAT
	JOURNAL

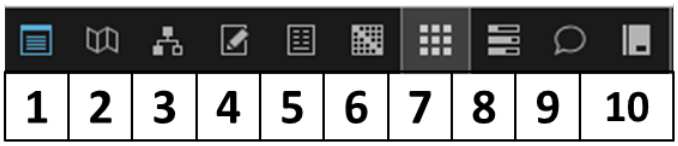

Nr	App
	PLAN BROWSER
	JOURNAL
	MAP
	CHAT
	ORGANISATION EDITOR
	COLLABORATIVE TEXT EDITOR
	PLAN OVERVIEW
	HOLDINGS
	SYNCRONISATION MATRIX
	FORMS