INSTRUKTION ISHV SITAWARE 6.9 2025

INTRODUKTION

Denna instruktion beskriver det praktiska användandet av stabsapplikation SitaWare HQ som finns i ISHv på bataljonsnivån och militärregion. Målgruppen är stabsmedlemmar vid en hemvärnsbataljonstab och militärregionsstab.

Instruktionen är en del av en serie instruktioner som HvSS tagit fram för att stödja militärregionerna samt hemvärnskompani- och bataljonsstaber i nyttjandet av ISHv.

Då innehållet kan komma att påverkas av systemuppdateringar av ISHv programvara ges dessa texter ut som instruktioner. Notera att instruktion inte är en publikationstyp och att instruktionerna därmed inte kommer ha en förrådsbeteckning eller att tryckas. Vid behov kan de skrivas ut från egen skrivare.

Eftersom innehållet är föränderligt är det viktigt att säkerställa att den senaste versionen används. De senaste versionerna av instruktionerna kommer att finnas tillgängliga i VIDAR och på HvSS/UtvE samarbetsyta:
samarbetsytor.emilia.swedi.mil.se/samarbetsytor/hvssutveckling.

Instruktionen gäller i fred och hela konfliktskalan.

Innehållet i denna instruktion omfattas inte av sekretess.

Ändringar

Instruktion Nummer	Ändring nr	Version Programvara	Gäller från	Vidarhandling för beslut	Anmärkning
1.0	0	6.9	2025-02-01	FM2023-15396:3	

Förslag på ändringar och förtydliganden insänds till hvss-utv@mil.se.

ANDRA HJÄLPMEDEL FÖR ISHV-ANVÄNDARE

Denna instruktion kompletteras av följande dokument:

- **Handbok ISHv Stabstjänst 2025** innehåller anvisningar med förklaringar och beskrivningar avseende hur ledningsstödsystemet ISHv kan nyttjas för att stödja stabsarbete. Alla stabsmedlemmar i en Hemvärnsbataljonsstab och militärregionalstab samt hemvärnskompanichefer med kompaniledningar behöver läsa den handboken för att förstå hur handhavandet ska tillämpas kopplat till stabstjänstmetoderna.

- **Instruktion ISHv Gemensamma funktioner 2025** beskriver användandet av de stabsstödsfunktioner som är gemensamma för militärregion, bataljons- och kompaninivå. Alla i kompaniledningen såväl stabsmedlemmar i militärregionstab och bataljonsstab bör läsa denna för att få en komplett förståelse för det egna stabsstödssystemets applikationer.

- **Instruktion ISHv Frontline 2025** beskriver det praktiska användandet av kompaninivåns stabsapplikation Frontline. Målgruppen är i första hand kompanichefer med kompaniledning.

- Instruktionerna och handboken är komplement till i systemet medföljande **systemböcker ISHv (I-bok och R-bok).**

Läsanvisning

Instruktionen är indelad i 15 kapitel och två bilagor.

Kapitel **ett** innehåller grunder ISHv och hur man **startar** SitaWare HQ.

Kapitel **två** beskriver **grunderna** för användandet av funktionerna i applikationen SitaWare HQ.

Kapitel **tre** till och med kapitel **femton** beskriver hur man **praktiskt** kan använda ISHv funktionerna i SitaWare HQ.

Bilaga 1. I SitaWare HQ är funktioner och menyer på engelska. I instruktionen används de engelska namnen och skrivs ut med kursiv stil, exempelvis *Staff Comments*. För att undvika missförstånd används i första hand de engelska namnen. I bilagan finns en översättningstabell som visar de svenska uttrycken för de viktigaste engelska namnen i SitaWare HQ. Denna bilaga kan användas i de fall då det inte är lämpligt eller möjligt att använda de engelska namnen.

Bilaga 2. Bilagan innehåller ett antal övningsuppgifter och ett test av funktionerna i gränssnitten för *Current Operations* och för *Plans & Orders*. Bilagan kan användas vid interna utbildningar eller vid självstudier då man har tillgång till ett upprättat ISHv.

Beskrivning av användandet av **alla** funktioner i SitaWare HQ återfinns i hjälpfunktionen.

Varje användande som beskrivs i denna instruktion är anpassat efter de metoder som är fastställda för Hemvärnet och följer den utbildning som är framtagen av Hemvärnets Stridsskola.

Innehållsförteckning

1 ISHv 8
1.1 Grunder 8
1.2 Start av SitaWare HQ 8
2 SitaWare HQ grunder 9
2.1 Allmänt 9
2.2 Användarmanual 10
2.3 Gränssnitt SitaWare HQ 10
2.3.1 Current Operations 10
2.3.2 Plans & Orders 11
2.4 Behörigheter 12
2.5 Säkerhetskopiering av information 12
3 Personliga inställningar 13
3.1 Settings 13
3.1.1 User Settings 13
3.2 Organisations Settings 17
4 Kartunderlag 18
4.1 Allmänt 18
4.2 Kartunderlag till Frontline 18
5 Layers och Pictures 24
5.1 Layers 24
5.1.1 Allmänt 24
5.1.2 Operational Information Groups 25
5.1.3 Olika former av *Layers* 27
5.2 Pictures 28
5.2.1 Allmänt 28
5.2.2 Hantering av Pictures 29
5.3 Hantering av Layers 32
5.3.1 Allmänt 32
5.3.2 Öppna ett Layer 32
5.3.3 Skapa ett nytt Layer 34
5.4 *Layers* innehåll 35

5.5 Skapa arbets-*Layers* 37
5.6 Skapa privata *Layers* 37
6 Kartsymboler och förband 38
6.1 Allmänt 38
6.2 Egna förband 38
6.3 Övriga kartsymboler 43
6.4 Flytta symboler som redan finns på lägeskartan 45
6.5 Flytta förband med koordinat 47
6.6 Kopiera symboler mellan Layers 48
6.7 ORBAT Editor 49
6.8 Korrelera rapporter 56
7 Bookmarks 60
7.1 Allmänt 60
7.2 Att spara presentationen efter en stabsorintering 60
8 Utskrifter från lägeskartan 62
8.1 Allmänt 62
8.2 Enkel utskrift från SitaWare HQ 62
8.3 Spara karta som PDF 63
8.4 Spara karta som en bild 63
8.5 Flersidig utskrift 64
8.6 Skriva ut oleat 64
9 Dela lägesbild med andra staber 67
9.1 Allmänt 67
9.2 Exportera Layers 67
9.3 Importera Layers 70
10 Verksamhetsjournal 71
10.1 Allmänt 71
10.2 Verksamhetsjournalens innehåll 72
10.3 Utskrift av verksamhetsjournal 73
10.4 Sortera informationen i verksamhetsjournalen 74
10.5 Gruppera informationen i verksamhetsjournalen 75
10.6 Lägga till och ta bort kolumner 76
10.7 Archive 76

11 Underhållsläget (Holdings) 77
11.1 Allmänt 77
11.2 Holdings kopplade till ORBAT 77
11.3 Inställningar för eget förband och resurser 78
11.4 Tilldela resurser till egna förband 80
11.5 Underhållsläget inom bataljonen 82
11.6 Status i relation till mängd 83
11.7 Förenklat underhållsläge på lägeskartan 84
11.8 Exportera underhållsläget till Excel 85
11.9 Flödesschema Holdings 86
12 Stridsvärdesrapport (Unit Status) 88
12.1 Allmänt 88
12.2 Statusområden 89
13 Planer och orderverk 90
13.1 Allmänt 90
13.2 Skapa en order utifrån en befintlig mall 90
13.3 Lägga till *Layers* 94
13.4 Filer kopplade till en order 95
13.5 Statushantering 96
13.6 Exportera order 99
13.7 Importera order 99
13.8 Hantera lägesrapporter från kompani 100
14 IRIS FORMS 103
14.1 Allmänt 103
14.2 Skapa FORMS rapport 103
14.3 Ta emot FORMS rapport 110
14.4 FORMS rapport från ett Layer 110
14.4.1 Skapa rapport från ett Layer 110
14.4.2 Öppna rapport i kartvyn 111
14.5 Instruktion för import av FMMK i IRIS Forms 112
15 Övriga verktyg och stöd 115
15.1 Geografiska analysverktyg 115
15.2 Söka koordinater och konvertera koordinater 115

15.3 Söka efter platser eller kartsymboler 116
15.4 Flera fönster 118
15.5 Presentationsverktyg 119
15.6 Smart Layers 120
15.6.1 Skapa ett Smart Layer, förändringar. 121
15.6.2 Skapa Smart Layers, område 125
Bilaga 1 Översättningstabell 129
Bilaga 2 Övningsuppgifter och test 131
Övning 2: Navigera i gränssnittet Plans & Orders 132
Övning 3: Personliga inställningar 134
Övning 4: Grundläggande karthantering 134
Övning 5: Lägesbild 135
Övning 6: Geo Tools 137
Övning 7: Journal 137
Övning 8: Plans & Orders 138
Övning 9: Sökfunktion 140
Övning 10: Bookmarks 140
Övning 11: Presentation 141
Övning 12: ORBAT 142
Övning 13: Forms 142
Övning 14: Övrigt avancerat 144
Gränssnittstest 145
Begrepp 147
Redaktionell information 149
Bildförteckning 150
Tabellförteckning 155
Källförteckning 156

1 ISHv

1.1 Grunder

ISHv är ett informationssystem anpassat för Hemvärnets behov och syftar till att öka Hemvärnets ledningsförmåga på bataljons- och kompaninivå.

Skillnaden mellan bataljonsnivån och kompaninivån är att bataljonsnivån nyttjar stabsstödsapplikationen SitaWare HQ och att kompaninivån nyttjar stabsstödsapplikationen Frontline. Dessa två stabsstödsapplikationer kan med hjälp av import/export funktioner utbyta geografisk lägesinformation, planer och order. Därutöver skiljer det sig på antalet klienter och serverlösning. Båda nivåer har en presentationsutrustning som kan stödja vid ordergivningar, föredragningar, orienteringar, et cetera.

ISHv är ackrediterat upp till begränsat hemligt (BH), ingen information med högre klassning får föras in i systemet. Öppen information och annan information som omfattas av annan sekretess enligt Offentlighet- och sekretesslagen (OSL) får hanteras i systemet.

1.2 Start av SitaWare HQ

Logga in med TEID-kort och kontrollera att status för de tre servrarna lyser grönt.

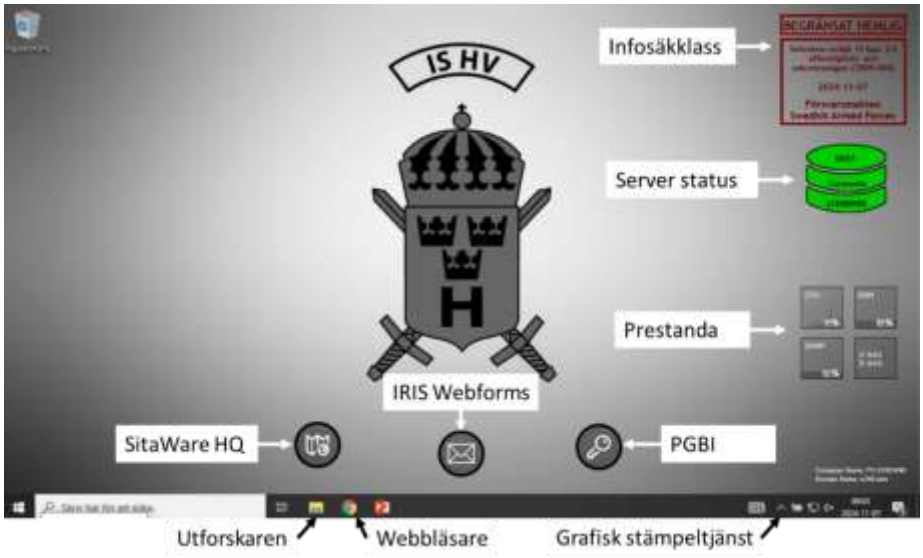

Figur 1 Startsida ISHv.

För att starta SitaWare HQ
Tryck på symbolen SitaWare HQ som är den första från vänster till höger av de tre aktiva ikoner som finns på skrivbordet.

2 SitaWare HQ grunder

2.1 Allmänt

SitaWare HQ är ett webbläsarbaserat informationssystem som stödjer staben i dess planering och genomförandet av uppgifter.

SitaWare HQ erbjuder tjänster som kan grupperas inom följande områden:

1. Geografiskt Information System (GIS) med stöd för militär symbolstandard, taktisk grafik samt geoanalysverktyg.
2. Aktuell lägesbild och dess administration.
3. Verksamhetsjournal där samtliga kan arbeta och se aktuellt läge.
4. Aktuellt logistik- och personalläge.
5. Planering och hantering av orderverk och grafik.
6. Delning av lägesbilder planer och orderverk genom import/export.

SitaWare HQ har tre lägen:

- *Current Operations* – Nuvarande läge (ljusgrön flik)

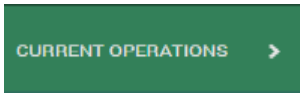

Figur 2 Flik för Current Operations.

- *Plans & Orders* – Planeringsläge (blå flik)

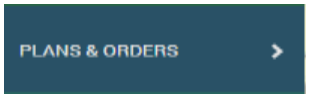

Figur 3 Flik för Plans & Orders.

- *Management*–Administration (grön flik)



Figur 4 Flik för Management.

Management är endast tillgänglig för ISHv administratör/tekniker.

Vissa applikationer är identiska i *Current Operations* och i *Plans & Orders*, såsom *Chat*, *Journal*, *Forms* och *User Settings*. Även karthanteringen är tillgänglig i båda delarna. Hanteringen av *Layers* fungerar i stort sett likadant i både *Current* och *Plans & Orders*.

2.2 Användarmanual

I SitaWare HQ finns en hjälpfunktion. Den nås via frågetecken-knappen (?) uppe till höger i verktygsfältet.

Figur 5 Aktiverande av hjälpfunktionen.

Välj *Help* och användarmanualen öppnas i en ny flik i webbläsaren. I användarmanualen kan man söka eller bläddra efter önskad information. Hjälpmenyn öppnar det kapitel som motsvarar det fönster eller den funktion som är öppen när man klickar på frågetecknet.

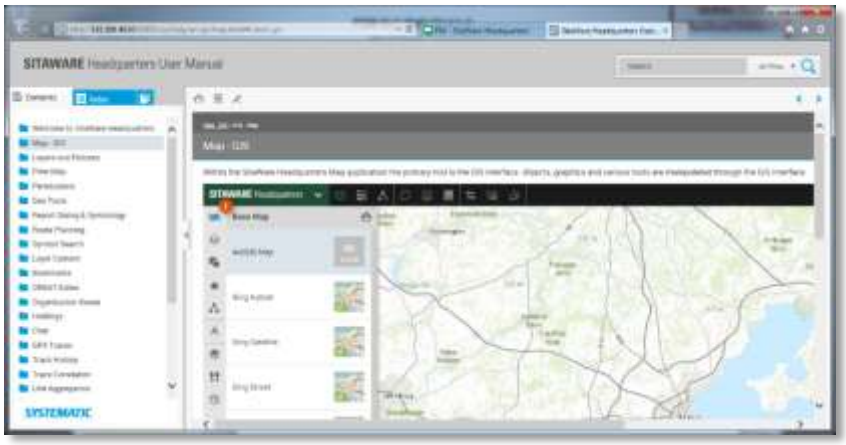

Figur 6 Hjälpfunktionen.

2.3 Gränssnitt SitaWare HQ

2.3.1 Current Operations

Current Operations används för ledning och uppföljning av egna förband, egen verksamhet, motståndarens förband och verksamhet, övrig gemensam verksamhet eller anläggningar. Viktiga funktioner är lägeskartan, stridsvärdesuppföljning samt rapportering.

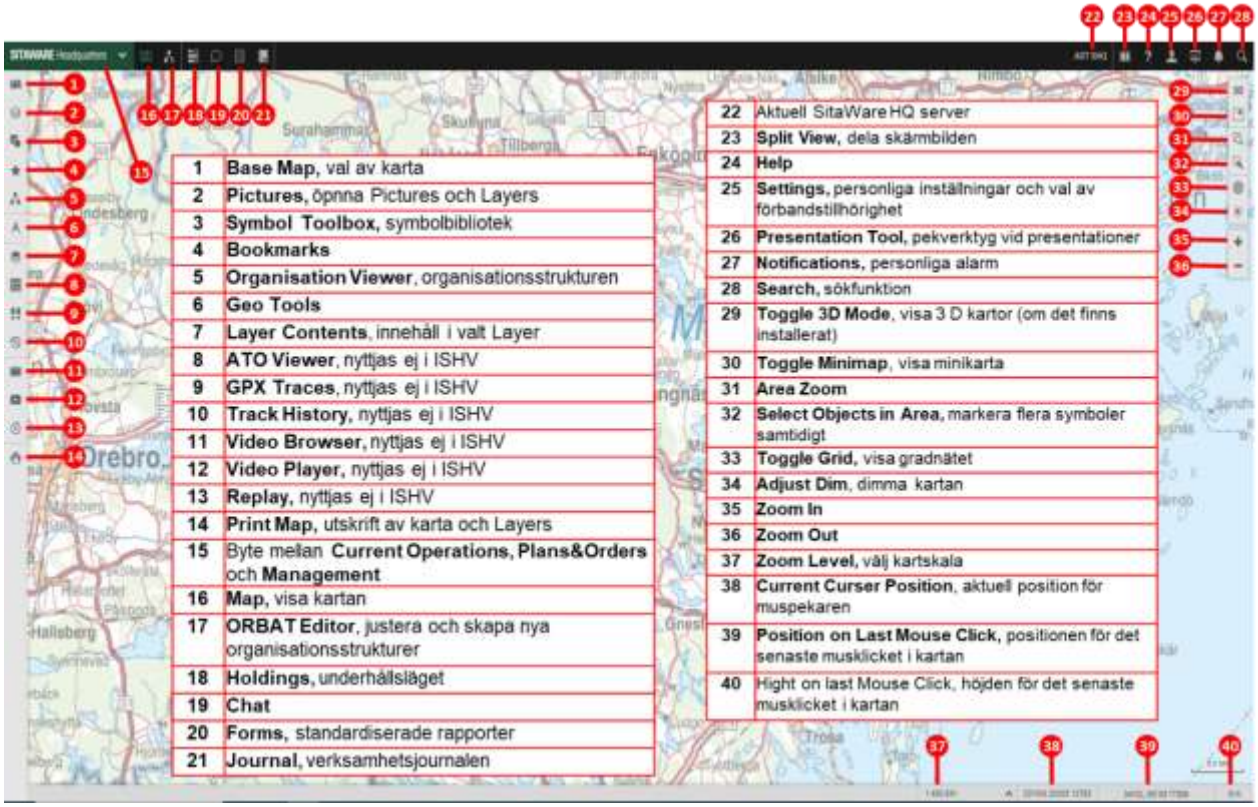

Figur 7 Gränssnitt för Current Operations.

2.3.2 Plans & Orders

Plans & Orders används av staben för att skapa planer och orderverk för förbandet. I planer och orderverk öppnas färdiga mallar som kan användas som stöd i planeringen eller framtagning av en order. Mallarna fylls sedan på med innehåll såsom order, funktionsstyrningar, grafiska *Layers* med mera.

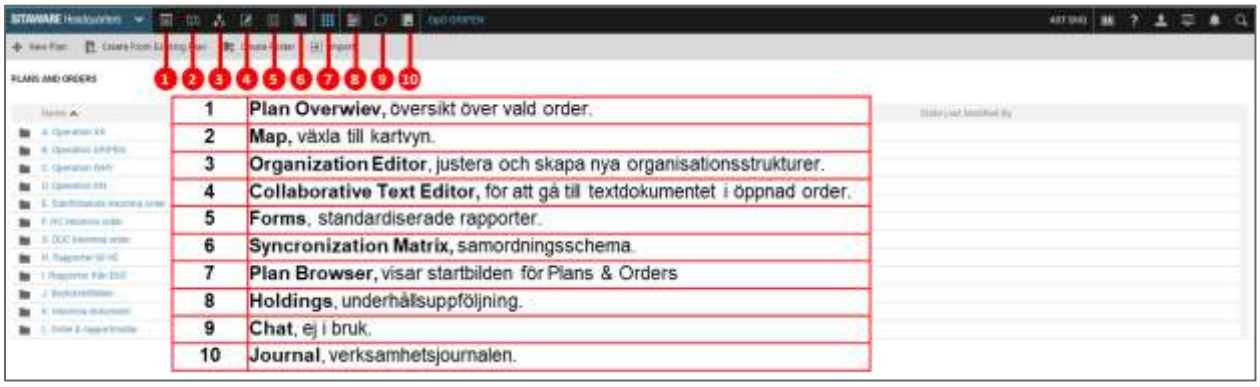

Figur 8 Gränssnitt för Plans & Orders.

2.4 Behörigheter

I SitaWare HQ används inbyggda behörigheter för att styra vilka som har rätt att läsa och/eller att förändra informationen. Dessa kan konfigureras av en administratör så att olika befattningar och roller ges olika behörigheter beroende på ansvar och uppgifter.

I grundkonfigureringen återfinns tre behörighetsnivåer:

- *SitaWare Admin*
- *SitaWare User*
- *SitaWare Viewer*.

För för *Layers*, *Pictures* och *Bookmark Folders* samt för planer/order i *Plans & Order* kan även följande behörigheter ställas in (*Permissions*):

Only me
- Endast den användare som skapat *Layer/Picture/Bookmark Folder* har läs- och skrivrättigheter.

Everyone
- Alla användare på aktuell SitaWare HQ server har läs- och skrivrättigheter.

Specific
- Endast användare i vald grupp(er) har läs och skrivrättigheter.
- Läs och skrivrättigheterna kan sättas för:
  - Läsa (*View*)
  - Skriva (*Edit*)
  - Äga (*Owner*)

2.5 Säkerhetskopiering av information

För att säkerställa att information som finns i SitaWare HQ inte försvinner bör information sparas med jämna mellanrum, beroende på operationens intensitet. Spara informationen lokalt på servern var tredje timme och på ett extern medium minst en gång per dygn.

Via MANAGEMENT-exportfunktion kan man få ut den mesta av informationen från SitaWare HQ, såsom, alla *Layers*, all information i *Plans & Orders*, *ORBAT*, *Holdings*, *Pictures* och *Bookmarks*.

Informationen i verksamhetsjournalen bör också sparas manuellt. Spara genom att välja en vy där informationen som ska sparas är synlig, klicka på *Print* och spara i PDF-format.

3 Personliga inställningar

3.1 Settings

Under *Settings* finns tre val: logga ut från SitaWare HQ, val av personliga inställningar samt val av organisationstillhörighet.

SitaWare HQ behöver inte loggas ut separat utan kan stängas ner med krysset uppe i högra hörnet innan man loggar ut från klienten.

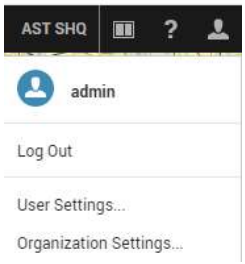

Figur 9 Val under Settings.

3.1.1 User Settings

I *User Settings* kan personliga inställningar ställas in, dessa bara påverkar det kontot som är inloggat. Inställningarna sparas även efter SitaWare HQ har stängts ner och klienten har loggats ut.

I nedanstående bilder visas rekommenderade inställningar. Observera att det inte finns inställningar för *Chat* då SitaWare HQ chat inte används.

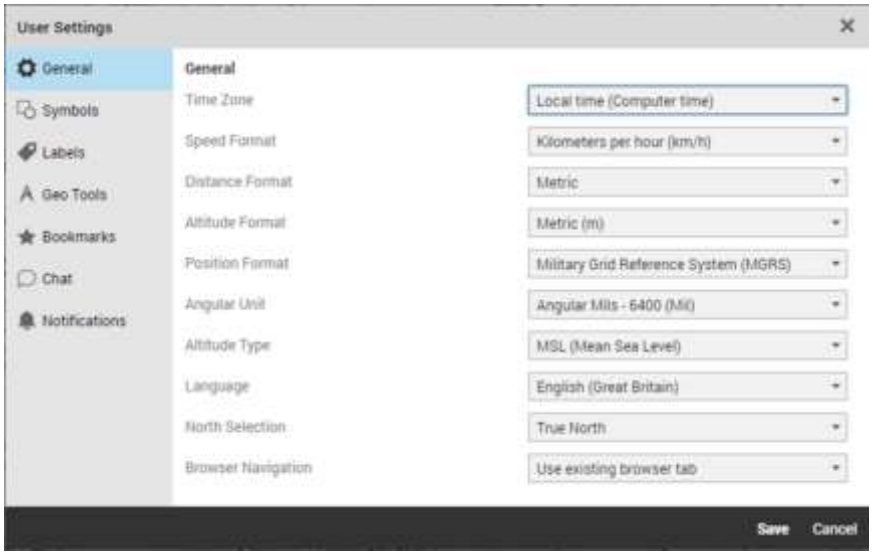

Figur 10 Rekommenderade inställningar för General.

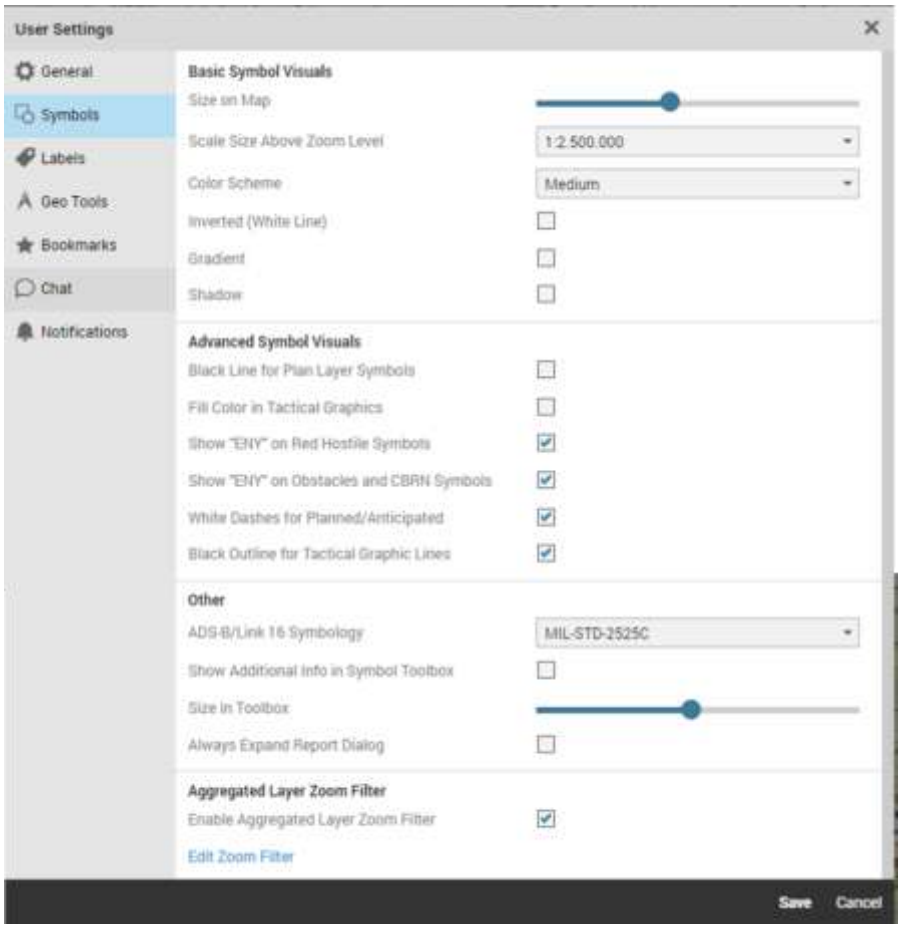

Figur 11 Rekommenderade inställningar för Symbols.

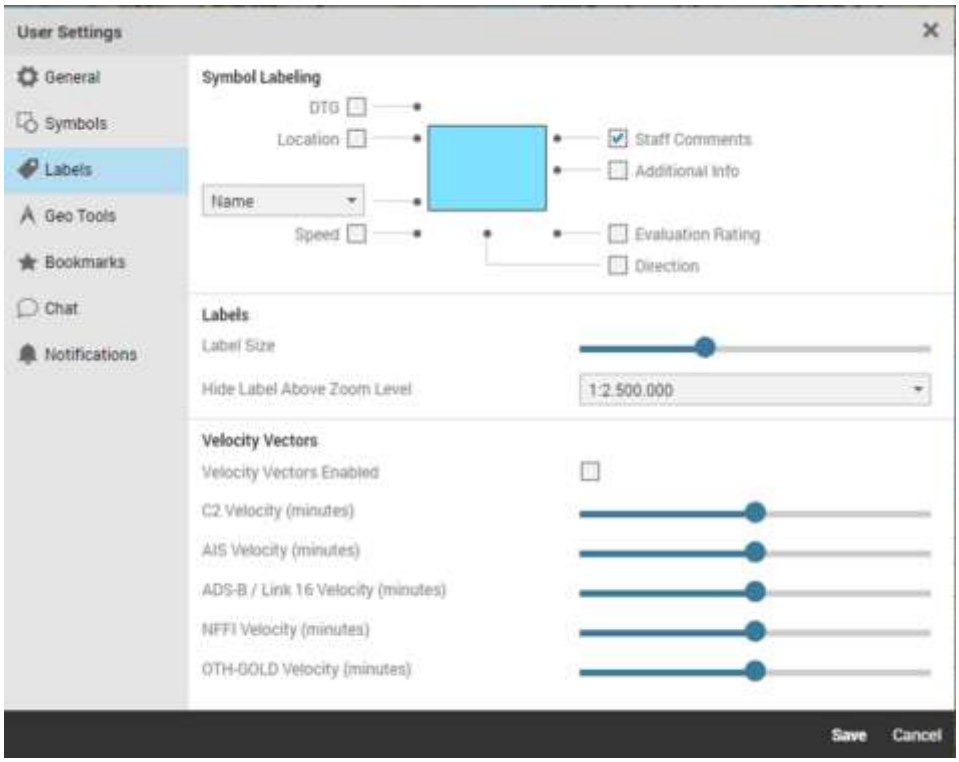

Figur 12 Rekommenderade inställningar för Labels.

Observera att det under rullisten *Name* går att välja att istället visa *Alternative Name*, vilket är förbandets anropssignal.

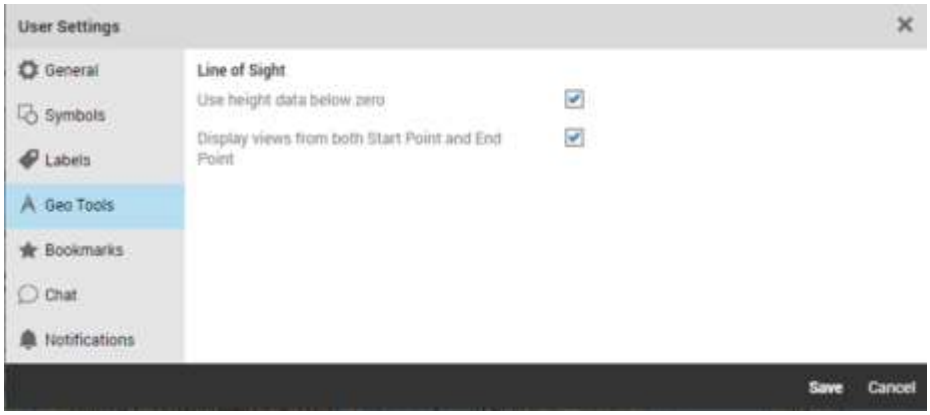

Figur 13 Rekommenderade inställningar för Geo Tools.

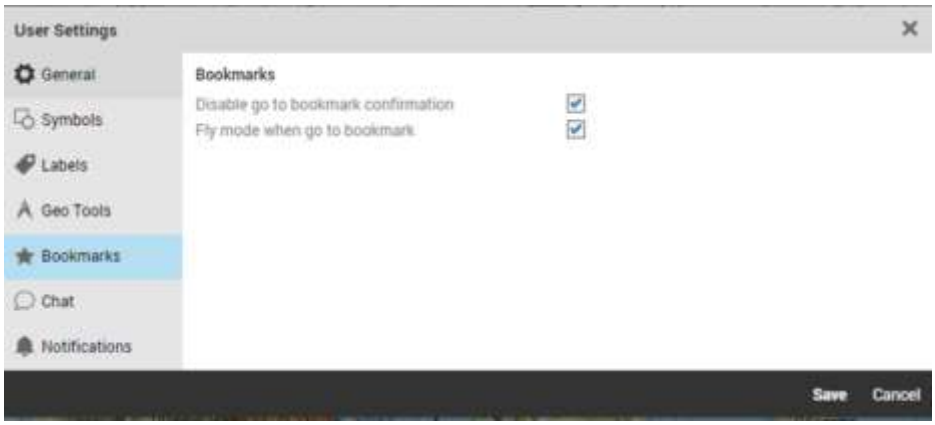

Figur 14 Rekommenderade inställningar för Bookmarks.

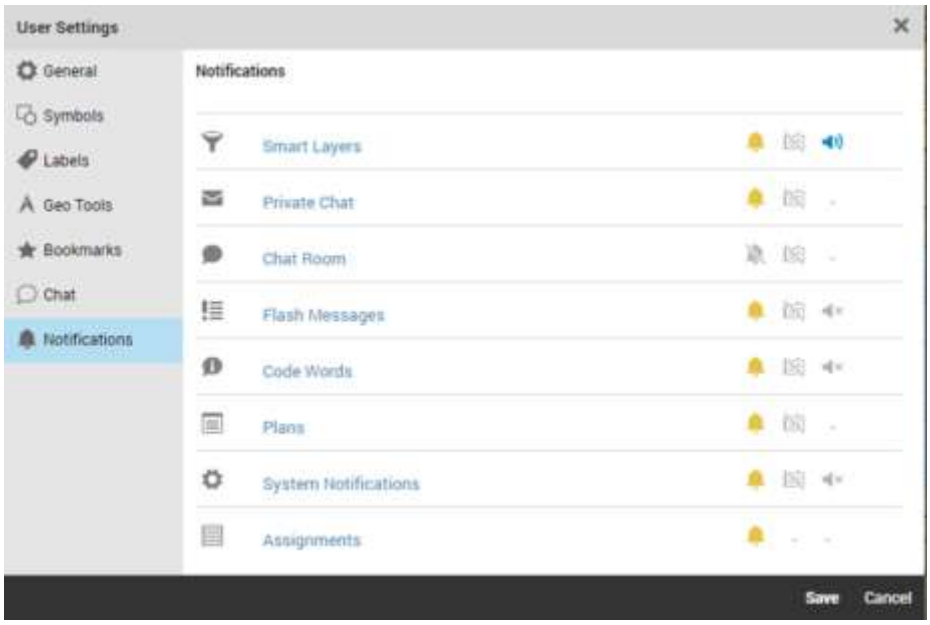

Figur 15 Möjliga val under Notifications.

Eftersom det inte finns någon koppling till ett externt nätverk är användning av *Notifications* mycket begränsad. De *Notifications* som kan användas är *Smart Layers* och *Plans*. Ifall dessa aktiveras skickar *Smart Layers* notiser utifrån de inställningar man angivit för *Smart Layer* medan *Plans* notifierar när en ny plan/order har importerats till SitaWare HQ.

3.2 Organisations Settings

Under *Organization Settings* finns två val: *Current Organization* respektive *Holding Reference ORBAT*.

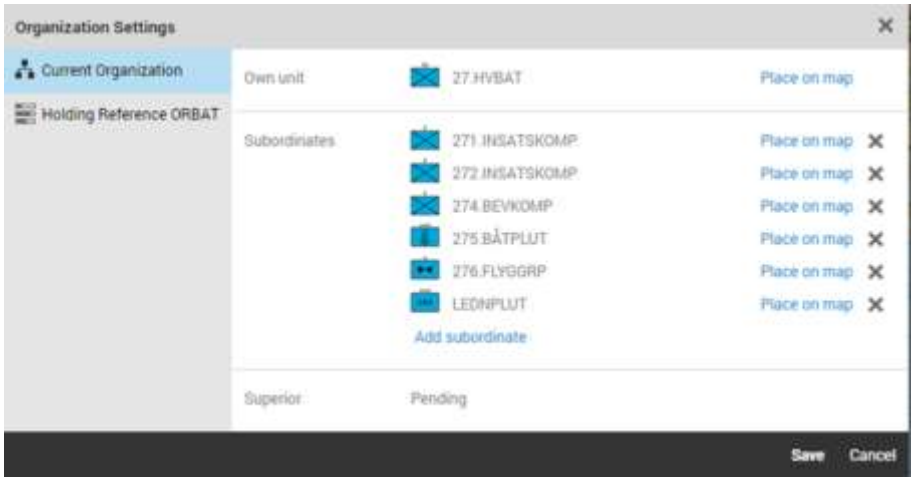

Figur 16 Visar aktuell organisation.

I *Current Organization* anges organisationstillhörighet. Man utgår då från en inläst ORBAT och väljer därefter sin organisation. Här kan man också välja att utgångsgruppera sina underenheter som hamnar i ett *Layer* (*Aggregated Layer)*. Det är inte rekommenderat att lägga ut förbanden från *Current Organization* då det inte går att exportera *Aggregated Layer*.

Figur 17 Visar den organisation som innehåller Holdings.

Ifall det finns fördefinierade *Holdings* till respektive förband så måste man under *Holding Reference ORBAT* välja sitt förband för att funktionen *Holdings* ska fungera.

Läs mer om detta i avsnitt **11.3 Inställningar för eget förband och resurser.**

4 Kartunderlag

4.1 Allmänt

Det går att byta kartunderlag i SitaWare HQ. Kartunderlaget motsvarar en tryckt papperskarta.

Välj önskat kartunderlag genom att klicka *Base Map* och sedan välja underlag. Exempel på kartunderlag i ISHv är skalbar markkarta, sjökort, ortofoto.

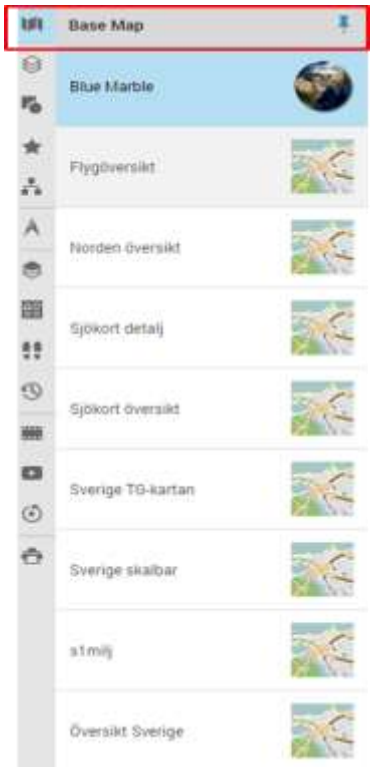

Figur 18 Val av Base Map och exempel på olika karttyper.

4.2 Kartunderlag till Frontline

Vanligtvis levereras geodata, såsom kartor och höjddata, till Frontline via bataljonsstaben. Detta framställs i bataljonsstabens SitaWare HQ-system via funktionen *Clip & Ship*.

Kompanierna beställer kartunderlag från bataljonen, som skapar begärda kartorna i SitaWare HQ. Kartorna levereras sedan som en fil via fildelning eller sparas på ett USB-minne som skickas via ordonnans.

Kompaniet importerar kartfilen till sin klient och lägger filen i C:*Maps*. Kartan kan därefter öppnas i Frontline. Hur detta görs framgår av Instruktion ISHv Frontline.

Kartor till Frontline framställs under *Management*-fliken i SitaWare HQ under *Maps and Overlays*. För att komma åt denna funktion krävs att stabsmedlemmen i fråga har behörighet, det vill säga har åtkomst till fliken *Management*.

Att skapa en karta med Clip & Ship görs enligt följande:

1. I *Management*-flikens navigationsmeny väljs *Maps and Overlays*. Nu visas administrationssidan för geodata och kartadministration.

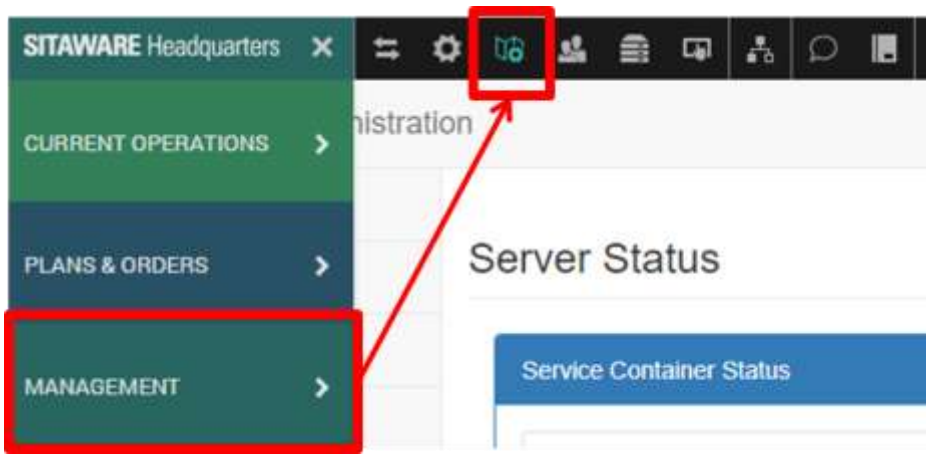

Figur 19 Val av Management och Maps and Overlays i SitaWare HQ.

2. Välj *Clip & Ship* i vänsternavigationen på denna sida.

Figur 20 Val av Clip & Ship.

3. En tom sida med menyn *Clip & Ship* visas. För att skapa nytt kartdatapaket välj, *Add Job* och därefter *Export Map*.

Figur 21 Meny för Add Job och Export Map.

4. En ny dialogruta med namn *Clip & Ship Export* visas.

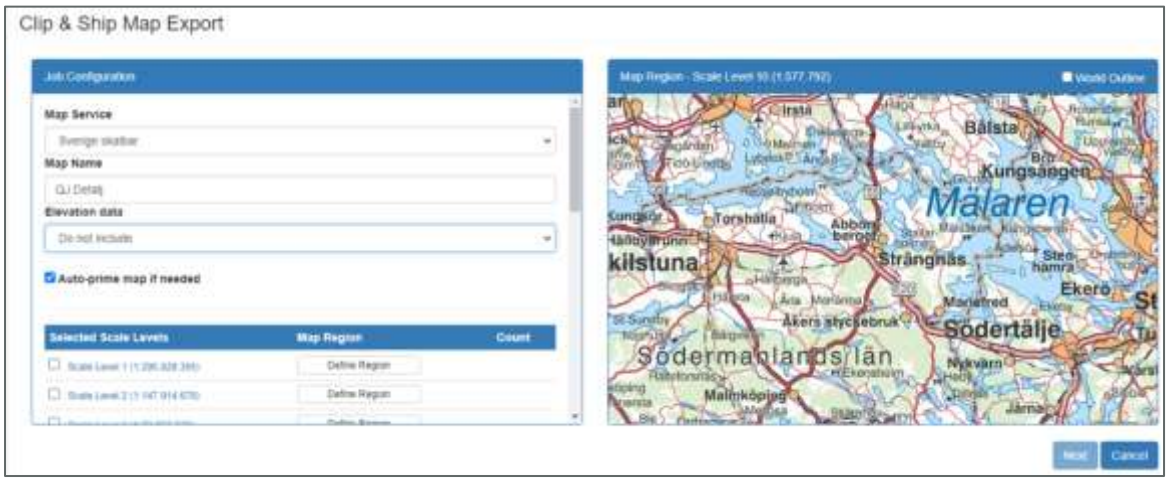

Figur 22 Meny för att välja karta och döpa karta.

5. Under *Map Service* välj den kartan som ska ligga till grund för den nya kartan.
6. Namnge kartan under *Map Name*. Om möjligt, välj ett unikt namn.
7. Höjddata (*Elevation data*) går inte att välja i detta steg.

Clip & Ship bygger på att kartan blir allt mer detaljerad ju mer man zoomar in. Det innebär att man kan välja ett något större område för den översta nivån och därefter väljer mindre och mindre områden inom utgångsområdet.

Observera kartskalan som anges vid respektive *Scale Level*. Undvik att välja en för stor kartskala då mängden data ökar stort ju större område och ju högre upplösning som väljs. Ett kompani behöver sällan en större skala än *Level 13* (1:72. 224).

För att välja skala och områden görs följande steg:

1. Markera lämplig *Scale Level*.
2. Klicka på *Define Region*.
3. Rita in området för vald *Scale Level* i kartfönstret.
4. Gå till nästa *Scale Level*. Gör om förfarandet. Normalt blir detta ett mindre område inom det först ritade området
5. Gå till nästa *Scale Level*. Gör om förfarandet ännu en gång. Normalt blir detta ett mindre område inom det tidigare ritade området.

6. Gör om förfarandet tills erforderliga kartskalor och områden är valda.

Figur 23 Valda Scale Level och valda kartområden.

7. Scrolla nu upp till där man kan välja *Elevation data*. Välj vilken *Scale Level* som ska innehålla höjddata i rullisten.

KOM IHÅG!
Kryssa i *Elevation data* innan du klickar på *Next*. Ifall denna inte är ikryssad kommer inte höjddatan att följa med kartan. Det går inte att komplettera med höjddata i efterhand utan att göra om hela förfarandet.

8. När *Elevation data* är vald, klicka på *Next*.

9. Nedanstående bild visas.



Figur 24 Karta redo att processas.

10. Starta jobbet genom att klicka på högerpilen. SitaWare HQ hämtar och paketerar då valda kartområden med höjddata. Beroende på valt område och skala kan det ta allt ifrån minuter upp till timmar.

11. När jobbet är färdigt visas nedanstående bild.

12. Kartan, som kan bestå av en filmapp med flera filer eller mappar, hittas via den sökväg som syns i bilden nedanför. Markera och kopiera sökvägen fram till och med *\nanomap*.

C:\ProgramData\Systematic\SitaWare Headquarters\nanomap

Figur 25 Sökväg till Nanomap.

13. Gå till Utforskaren och klistra in sökvägen.

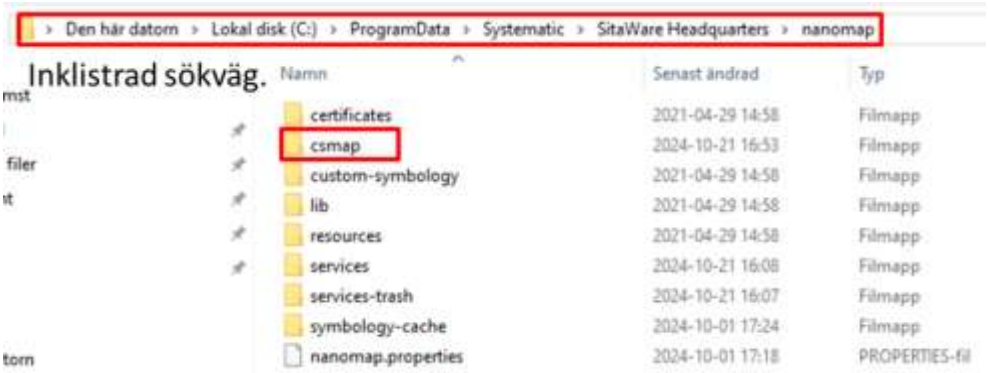

Figur 26 Mappstruktur i Nanomap med csmap.

14. Då visas ett mappträd med mappen *csmap*. Här finns *Clip & Ship* kartor som placerats via SitaWare HQ.

Skapa en genväg till csmap genom att dra csmap-mappen till och släppa den på Snabbåtkomst.

Figur 27 Skapa en snabbväg till csmap.

Det finns nu en genväg till *csmapp* där man enkelt kan hämta eller kopiera kartfiler som ska till ett kompani. Kartfilen kan sedan levereras via fildelning eller genom sparas på ett godkänt USB-minne.

5 Layers och Pictures

En viktig del i SitaWare HQ är att förstå *Layers* och *Pictures* och skillnaden dem emellan.

5.1 Layers

5.1.1 Allmänt

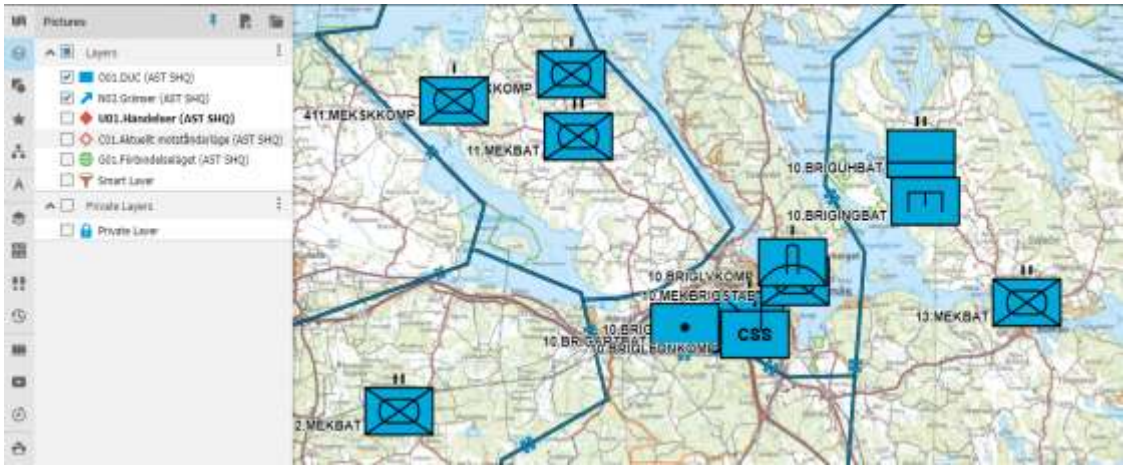

Figur 28 Exempel på Layers.

Ett *Layer* kan ses som ett specifikt ämnesområde där information lagras och hanteras. *Layers* kan jämföras med plastoleat som traditionellt har lagts på papperskartan och använts för att rita in egna förband och verksamhet, fiendens förband och verksamhet med mera.

Ett *Layer* kan öppnas, visas och editeras av flera användare samtidigt. Alla *Layers* är tillgängliga för samtliga användare som automatiskt kan ta del av varandras uppdateringar. Varje *Layers* kan tändas och släckas individuellt, vilket styr vilken information presenteras på kartan. Flera *Layers* kan vara tända samtidigt.

När symbol placeras i ett *Layer* så sparas informationen automatiskt. För att kunna placera en symbol i ett *Layer* måste avsett *Layer* vara aktiverat. Detta görs genom att antingen dubbelklicka på avsett *Layer* eller högerklicka och välja *Set Active Layer*.

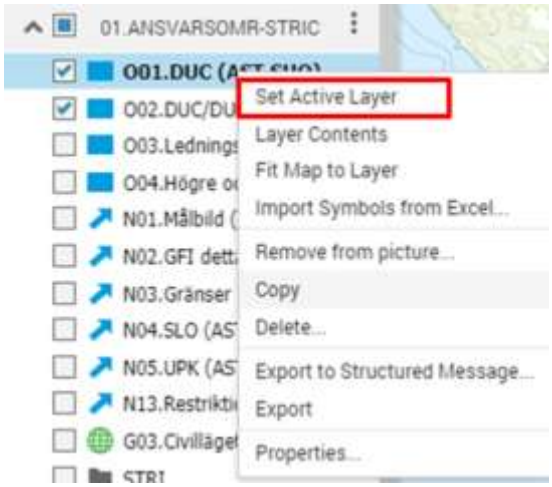

Figur 29 Aktivera ett Layer.

OBSERVERA!
Ett *Layer* måste alltid vara aktivt för att man ska kunna placera en symbol i ett *Layer*. Man kan dock radera, flytta eller uppdatera symboler i ett *Layer* utan att det är aktivt.

Administratören kan lägga till och ta bort *Layers* såväl som redigera vilka användargrupper som kan editera vilka *Layers*.

Numrerade och namngivna *Layers* (exempelvis N03.Gränser) i SitaWare HQ är fastställda och samma grundstruktur finns i andra informationssystem, som används av HC och staber inom Armén för utbyte av information mellan enheterna.

5.1.2 Operational Information Groups

För att lagra lägesinformation på ett strukturerat sätt som ska kunna delges annan part används *Layers*. Dessa kallas *Operational Information Groups* (OIG). I grunden utgörs de endast av fem huvudgrupper enligt internationella överenskommelser gjorda inom intresseorganisationen *Multilateral Interoperability Programme* (MIP). Denna organisation tar fram regelverk för datautbyte mellan olika nationers system.

När man kommunicerar med annat förband inom insatsorganisationen (t.ex. annan Hemvärnsbataljon, militärregionstab, brigad eller annan nation) inom ramen för en insats, så måste man förhålla sig till detta regelverk. Detta innebär att all information som ska överföras måste ”förpackas” i dessa fem huvudgrupper. På så sätt så hamnar rätt informationsobjekt i de rätta katalogerna (*Layers*), vilket skapar struktur i informationshanteringen.

Inom varje huvudgrupp (OIG) kan det finnas ett eller flera *Layers* men de tillhör och markeras med nedanstående symboler:

Friendly and Neutral (Organisational) – Egna förband – ska innehålla förbandssymboler om egna och neutrala förband.

Friendly and Neutral (Non-Organisational) – Taktisk grafik – ska innehålla taktisk grafik om egna och neutrala förband.

Uncorrelated Enemy and Unknown – Underättelserapporter – ska innehålla obearbetad rå information om fientliga eller okända förband, det vill säga underrättelserapporter.

Correlated Enemy and Unknown – Bedömt motståndarläge – ska innehålla bearbetad information om fientliga eller okända förband, det vill säga bedömande avseende fiendens styrka och aktiviteter.

Globally Significant – Globalt– ska innehålla övrig information som är allmänt relevant och som kan påverka alla aktörer.

5.1.3 Olika former av *Layers*

I SitaWare HQ förekommer olika typer av *Layers*.

Dels OIG-*Layers*, vilket innefattar egna förband, taktisk grafik, underrättelserapporter, bedömt fiendeläge och globalt.

Utöver OIG-*Layers* förekommer även privata *Layers*, smarta *Layers*, geo-*Layers*, plan-*Layers* och grupper.

Lager	Typ	Innebörd	Layersnamn
Lager # 1	OIG	Globalt *Layers*	Globally significant
Lager # 2	OIG	Egna förband	Friendly and Neutral (Organisational)
Lager # 3	OIG	Taktisk grafik	Friendly and Neutral (Non-Organisational)
Lager # 4	OIG	Underrättelserapporter	Uncorrated Enemy and Unknown
Lager # 5	OIG	Bedömt motståndarläge	Correlated Enemy and Unknown
Mitt privata lager	Privat	Eget privat *Layers* för specifik användare	Private layer
Ett filter	Filter	Dynamiskt *Layers* som uppdateras beroende på satta villkor	Smart layer
Skjutfalt_grans	Geo *Layers*	Ett *Layers* som kompletterar grundkartan med information	Geospatial Overlay
En plan	Plan-*Layers*	Planerings *Layers*	Plan Layer
En grupp av lager	Grupp	Flera *Layers* som samlas i en grupp	Group Layer

Tabell 1 Ikoner som kan förekomma i SitaWare HQ.

5.2 Pictures

5.2.1 Allmänt

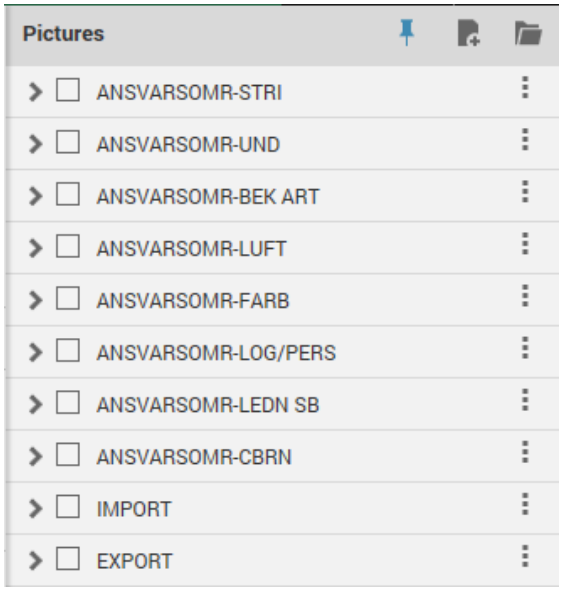

Figur 30 Fastställda Pictures i ISHv.

Layers, oavsett OIG-tillhörighet, kan grupperas i *Pictures* för att skapa en mer logisk överblick av lägesbilden. För att dölja viss information i en *Picture*, kryssa ur det *Layer* som ska döljas i aktuell *Picture*.

Picture vars namn inleds med **ANSVARSOMR** utgår från ansvaret för att föra in aktuell och relevant information i tilldelade *Layers*.

Observera att det bara finns ett *Layer* av varje slag. Ett *Layer* kan finnas i ett eller flera *Pictures* men alla ändringar av informationen görs fortfarande i ett *Layer*. Ändringar påverkar alla *Pictures* som innehåller det *Layer*.

I varje *Picture* finns även arbets-*Layers* indelade i arbetsmappar, exempelvis ”Stri” för Ansvarsområde-Stri. Dessa arbets-*Layers* är inte fastställda, utan till för att stabsmedlemmar ska kunna göra utkast, öva eller skapa kompletterande textrutor till stabsorientering som man inte vill ha i sina fastställda *Layers*.

5.2.2 Hantering av Pictures

Man kan skapa nya, radera, öppna befintliga eller ta bort en *Picture* från aktuell vy. Ifall en *Picture* raderas så tas den bort permanent, vilket inte kan ångras.

Att skapa en ny *Picture* görs enligt följande:

1. Klicka på *Create Pictures.*

Figur 31 Ikon för att skapa ny Picture.

2. Döp den nya *Picturen* och klicka på *Create*.

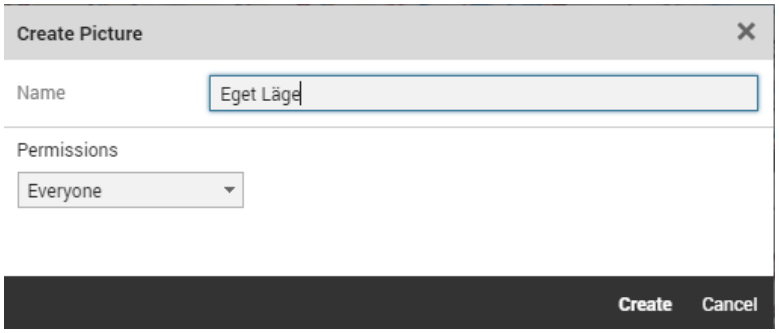

Figur 32 Meny för att döpa och skapa en Picture.

3. Den nya *Picture* är nu synlig i aktuell vy men tom. Klicka på *Add Content* för att lägga till *Layers* i en *Picture.*

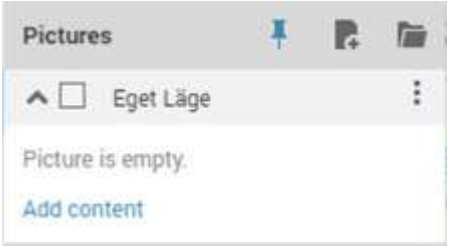

Figur 33 Skapad Picture utan några Layers.

För att ta bort en *Picture* från aktuell vy, klicka på åtgärdsprickarna eller högerklicka på aktuell *Picture* och välja *Remove from Panel*. Vald *Picture* är borttagen från aktuell vy men kan vid behov öppnas och läggas tillbaka in i vyn igen.

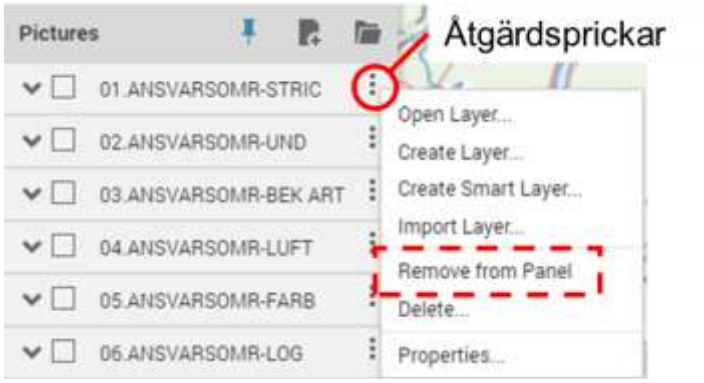

Figur 34 Ta bort en Picture från aktuell vy.

OBSERVERA!
Om man istället för *Remove from Panel* väljer *Delete* raderas aktuell *Picture* och kan inte öppnas igen. Dock finns alla *Layers* som fanns i den *Picture* kvar och kan öppnas i en annan *Picture*. Man kan skapa en ny *Picture* med samma namn som den *Picture* som raderats.

Att öppna en *Picture* som inte är synlig i aktuell vy görs enligt följande:

1. Klicka på *Open Picture*.

Figur 35 Ikon för att öppna en Picture.

2. Välj vilken typ av *Picture* som ska öppnas, det vill säga antingen en *Operational Picture* eller en från *Plans & Orders*.

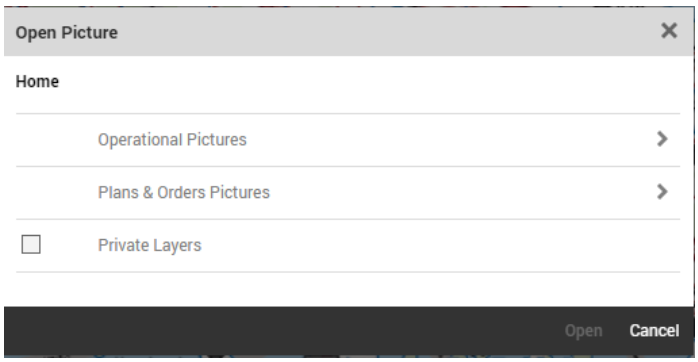

Figur 36 Meny för att välja vilken typ av Picture som skall öppnas.

3. Väljer man *Operational Picture* visas vilka som finns tillgängliga. Bocka i de som ska öppnas och välj *Open*.

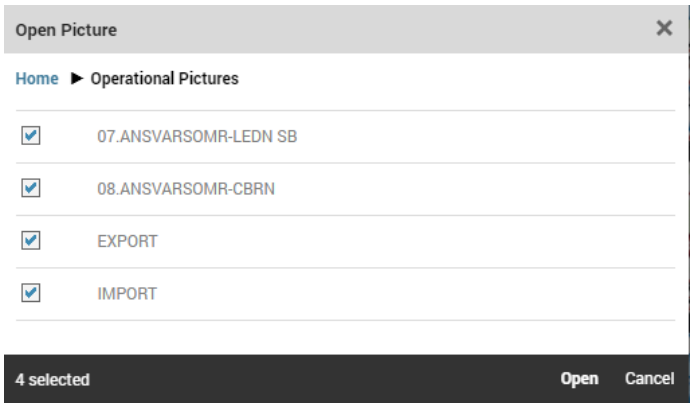

Figur 37 Val av Pictures som skall öppnas.

4. Väljer man en *Picture* från *Plans & Orders* så visas *Folder*-strukturen från *Plans & Orders*. Där kan man välja att visa en *Picture* som innehåller *Plan Layers* som är kopplade till en plan/order.

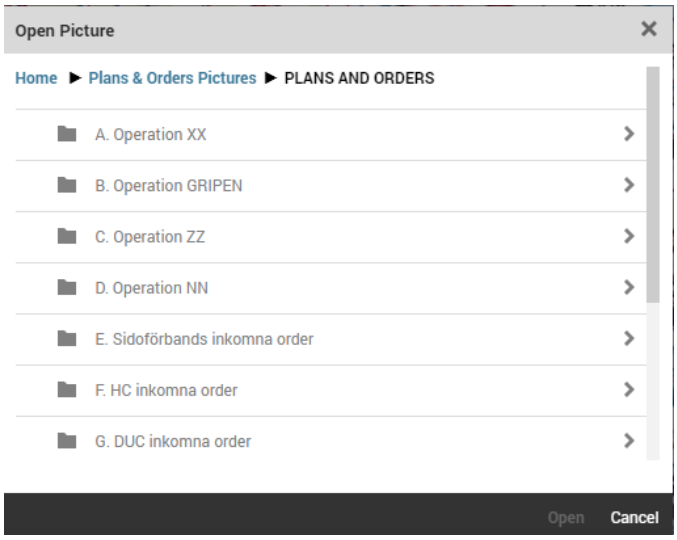

Figur 38 Folder struktur i Plans & Orders.

5. Bocka i vald order och klicka på *Open*.

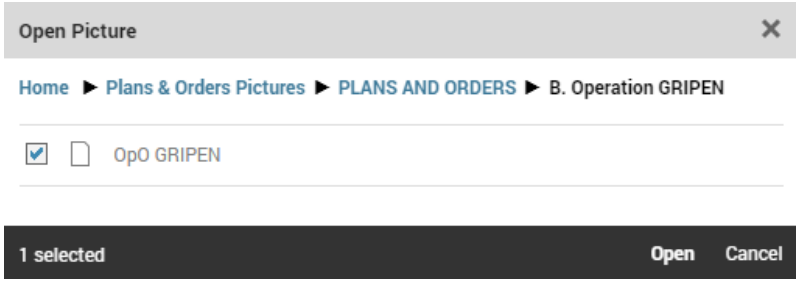

Figur 39 Vald order vars Picture skall öppnas.

6. Nu finns det en *Picture* synlig i aktuell vy som heter orderns namn och som innehåller de *Plan Layers* som är kopplade till ordern.

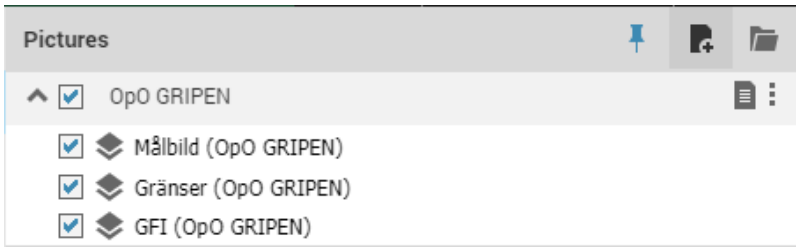

Figur 40 Öppnad Picture med Plan Layers.

5.3 Hantering av Layers

5.3.1 Allmänt

Man kan skapa, radera, öppna befintliga eller ta bort ett *Layer* från en *Picture*. Ifall ett *Layer* raderas så tas det bort permanent, vilket inte går att ångra.

5.3.2 Öppna ett Layer

Att öppna ett *Layer* i en *Picture* görs enligt följande:

1. Välj *Add Content*, klicka på åtgärdsprickarna eller högerklicka på vald *Picture*.

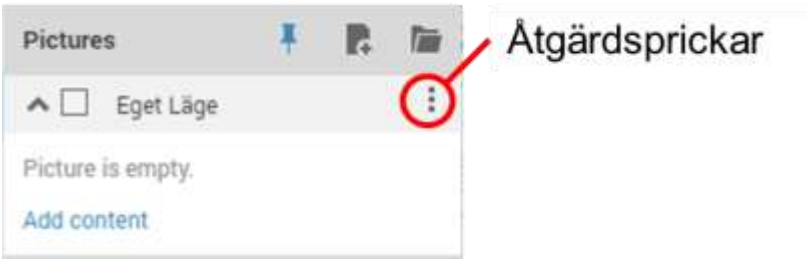

Figur 41 Öppna ett Layer i en Picture.

2. Välj *Open Layer*.

3. Välj vilken typ av *Layer* som ska öppnas. Normalt syns den egna SitaWare HQ servern överst i listan. Ifall denna nivå kryssas i syns alla *Operational Layers*, inklusive alla arbets-*Layers*, som finns i servern. Detta kan vara användbart för informationsledare/tekniker för att kontrollera vilka *Layers* som finns i systemet.

4. Vill man inte öppna alla *Layers* väljer man att klicka på pilen till höger om vald kategori för att expandera och se vilka *Layers* som finns tillgängliga. Kryssa i de *Layers* som ska öppnas.

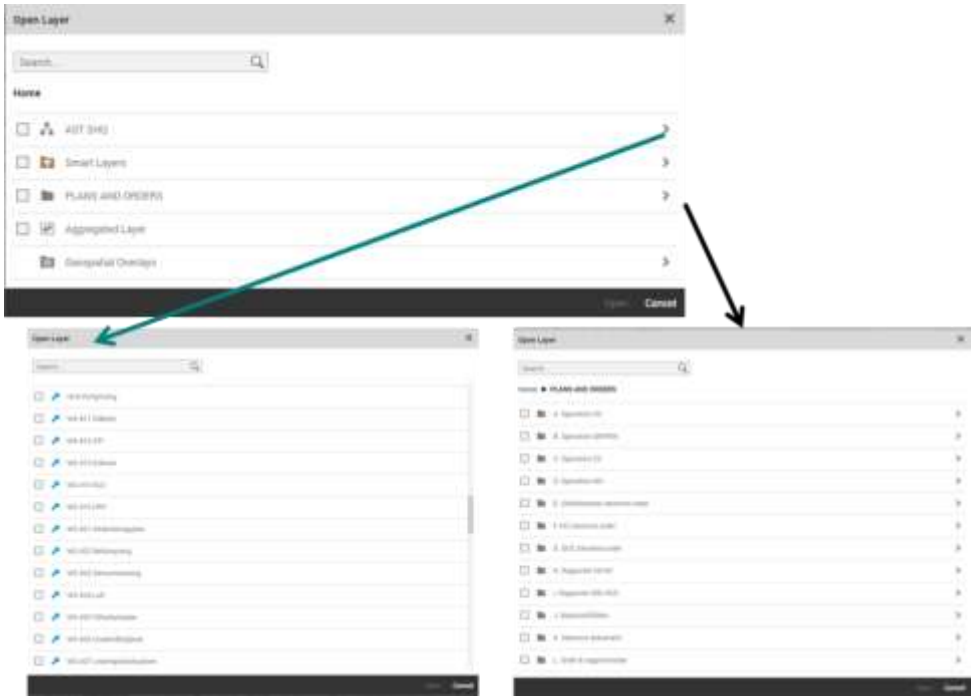

Figur 42 Val av Layers som skall öppnas i en Picture.

5. Efter att *Open* har valts kommer valda *Layers* att synas i den *Picture* som man utgått ifrån. Både *Operational Layers* och *Plan Layers* kan finnas i samma *Picture*.

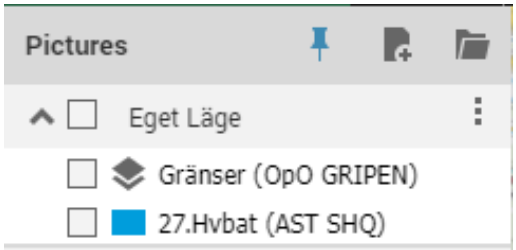

Figur 43 Picture med öppnade Layers, ett Plan Layer och ett Operational Layer.

Högerklicka på valt *Layer* för att öppna alternativa åtgärder.

För att aktivera *Layers*, klicka på *Set Active Layer* eller dubbelklicka på valt *Layer*. *Layers* namnet blir då markerat med **fetstil**.

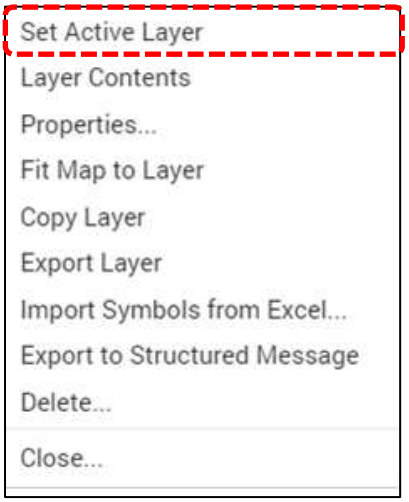

Figur 44 Layers-hanteraren och aktivera ett Layers.

OBSERVERA!
Om man trycker *delete* så raderar man ett *Layer* permanent – motsvarar att destruera ett oleat. Det går inte att återställa ett raderat *Layer*.

5.3.3 Skapa ett nytt Layer

Att skapa ett helt nytt *Layer* görs enligt följande:

- Klicka på åtgärdsprickarna och välj *Create Layer*.

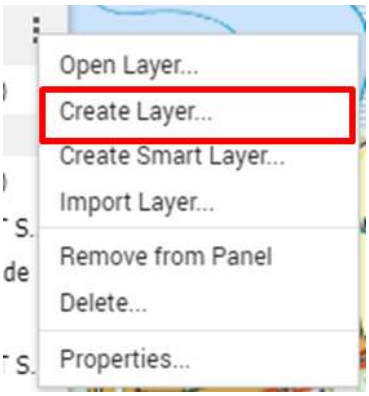

Figur 45 Meny för att skapa nytt Layer.

- Därefter skapar man sitt *Layer* i fem steg enligt bilden:

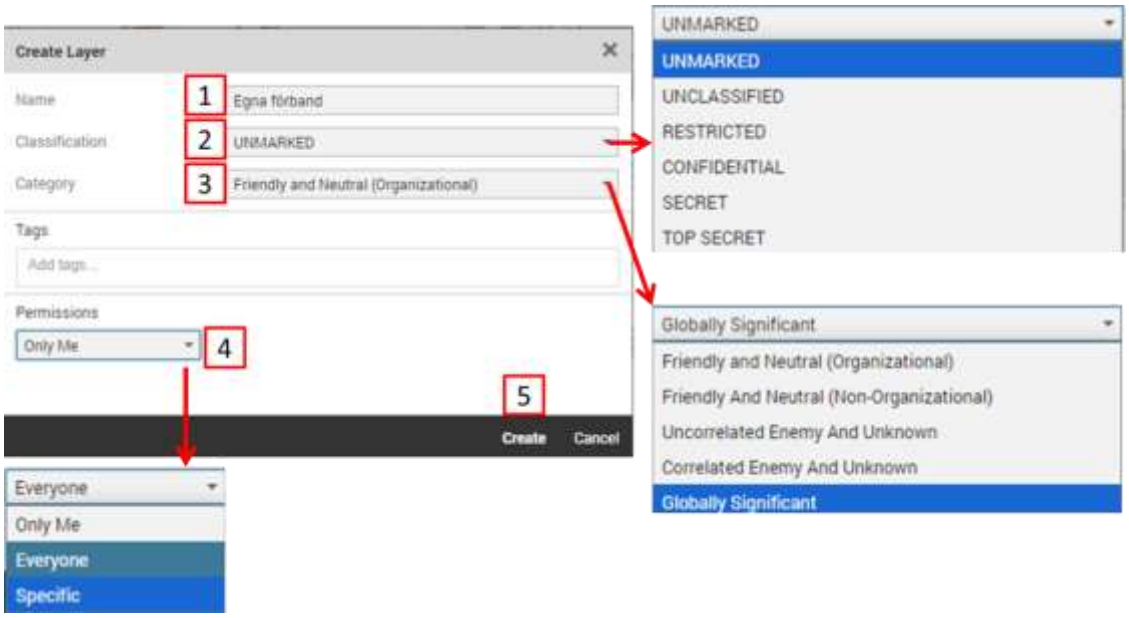

Figur 46 Formulär för att skapa ett nytt Layer.

1. Ange *Layer* namnet.
2. Välj sekretess i rullisten.
3. Välj *Layer* typ (OIG).
4. Välj *Layer* behörighet.
5. Klicka på *Next* för att skapa nytt *Layer*.

5.4 *Layers* innehåll

Layer Contents är ett register över alla symboler i ett *Layer*. Denna funktion är användbar om för att granska innehåll, hitta en särskild kartsymbol på kartan eller få upp en förteckning över exempelvis UPK-lista.

För att se innehåll i ett *Layer*, högerklicka på ett *Layer* och välj *Layer Contents*.

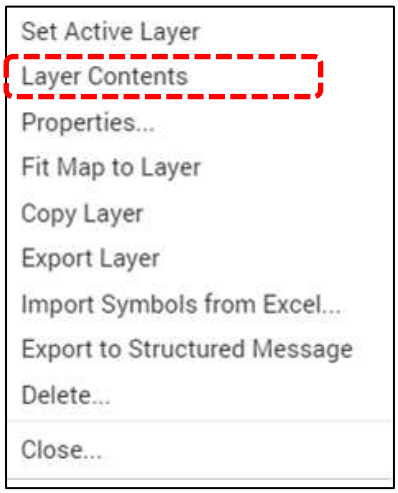

Figur 47 Layershanteraren och Layer Contents.

Genom att dubbelklicka på en av symbolerna i *Layer Contents* listan ställs kartan automatiskt in så att symbolen hamnar i centrum. Nedan visas ett exempel med en lista över UPK-punkter i *Layer N05. UPK*.

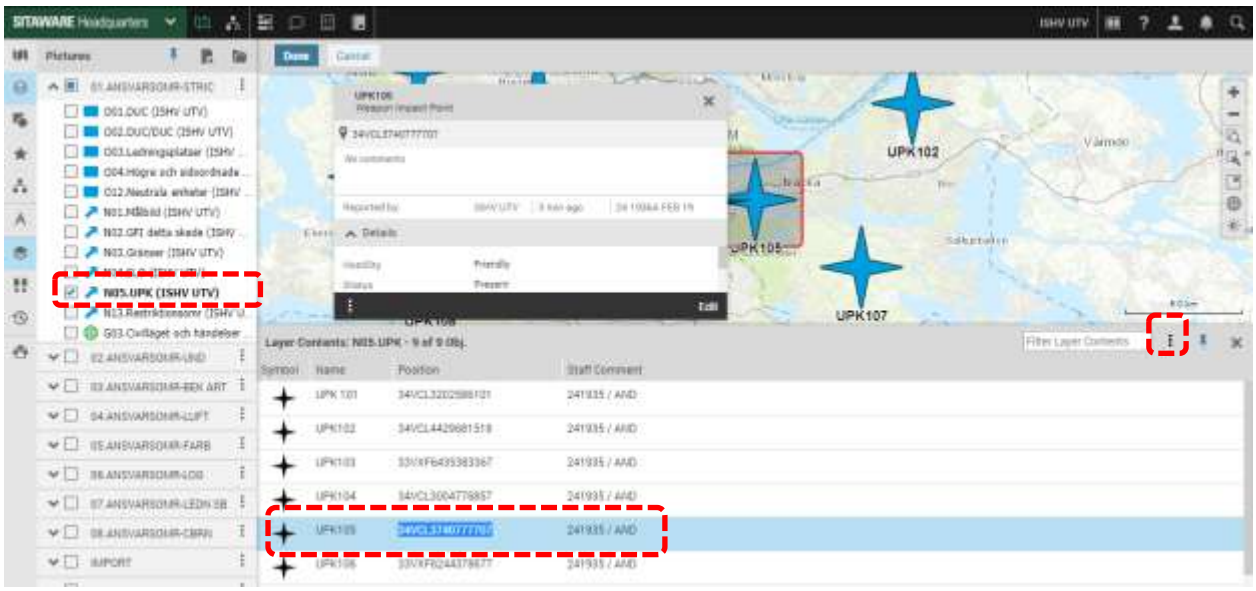

Figur 48 Layer contents med lista över UPK.

Dubbelklicka på en av kartsymbolerna för att öppna *Report Dialog*. För att filtrera informationen används de tre prickarna som är markerade ovan. I filtreringsfunktionen kan man även att välja vilka fält som ska visas i listan, exempelvis koordinater (position).

5.5 Skapa arbets-*Layers*

För att skapa arbets-*Layers* för att användas som till exempel utkast, textrutor till stabsorientering eller för övning används funktionen *Create Layer*.

Dessa *Layers* kallas arbets-*Layers* och är i grunden ett globalt *Layer* som ligger sorterat i en grupp under en *Picture*. Dessa arbets-*Layers* är inte fastställda. Informationen ska därav inte att betraktas som validerad.

För att skapa ett arbets-*Layers* högerklickar man på den valda gruppen och väljer *Create Layer*. Fyll i namn och tryck sedan på *Create*.

5.6 Skapa privata *Layers*

Varje användare har sin egen privata arbetsyta, *Private Layers*. Dessa kan användas vid planeringsarbete, som diskussionshjälpmedel eller som ett privat funktionsstöd. *Private Layers* kan endast ses av den användare som är inloggad och delas inte med någon annan i staben.

För att skapa *Private Layers*, välj att öppna en vy och nedanstående dialogruta öppnas. Klicka i *Private Layers*.

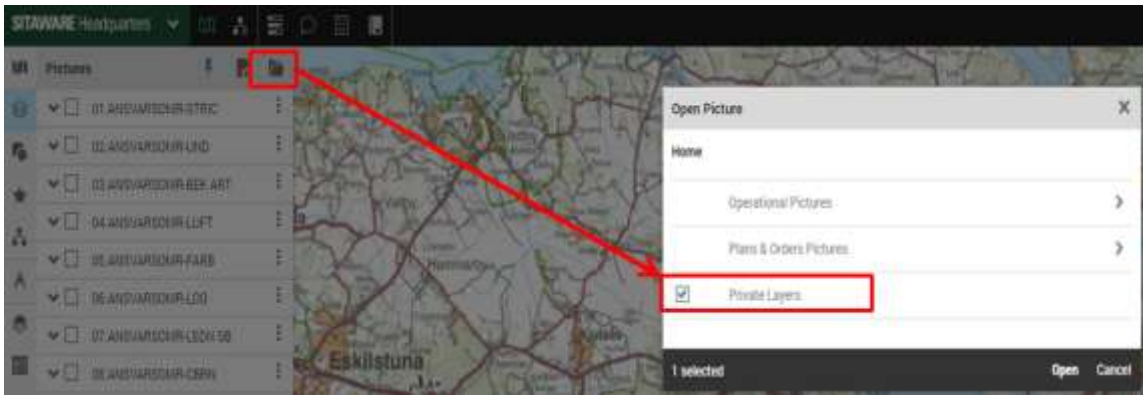

Figur 49 Dialogruta vid öppnande av Picture med Private Layers.

6 Kartsymboler och förband

6.1 Allmänt

Kartsymboler och förband finns i två former i SitaWare HQ. Ena delen är *ORBAT* och andra delen är *Symbol Toolbox*.

Symbolerna i SitaWare HQ är baserade på Handbok Gemensamma Symboler som i sin tur är baserad på internationella standarder såsom NATO APP-6 och US standard 2525.

ORBAT (förkortning av Order of battle) – förbandsstruktur – är en grundstruktur enligt Försvarsmaktens insatsorganisation och omfattar egna förbandssymboler med rätt symbol, klartextnamn (*Name*) och anropssignal (*Alternative name*) samt tilldelad materiel. Förbandsorganisationen distribueras centralt av Försvarsmakten och kommer ut som en teknisk order till Hemvärnsförbanden. Egna förbandssymboler ska alltid hämtas från *ORBAT*, inte skapas från *Symbol Toolbox*.

Symbol Toolbox är uppbyggt av ett antal symbolgrupper innehållande Försvarsmaktens gemensamma symboler. I respektive grupp återfinns symboler som kan kopieras till *Layers*. Det är även möjligt att söka efter en specifik symbol. *Symbol Toolbox* används främst till andra förband såsom motståndaren, civila parter och funktioner eller taktisk grafik. *Symbol Toolbox* används aldrig för att skapa egna förband, utan istället används *ORBAT* enligt ovan.

För att skapa spårbarhet avseende vem som har lagt ut information på lägeskartan används S*taff Comments* i *Report Dialog* som kommer fram när man lägger ut eller flyttar en symbol. Vid varje uppdatering ska även *Staff Comments* uppdateras i syfte att ensa aktuellt läge och skapa spårbarhet kring vem som har lagt ut eller uppdaterat symbolens information samt när detta gjordes.

6.2 Egna förband

Börja alltid med att under *Settings* välja *Organization Settings* och under *Holding Reference ORBAT* välja eget förband. Detta för att rapporterade *Holdings* ska kopplas till förbandsymbolen.

Börja med att aktivera *Layer* O02.DUC/DUC när ett eget förband ska läggas ut. Här placeras förbandssymbolerna från DUC/DUC, det vill säga plutoner och övriga direkt under DUC lydande enheter.

Att placera en förbandsymbol i ett *Layer* görs enligt följande:

1. Välj Organisation Viewer i verktygsfältet till vänster för att placera ut egna förband på lägeskartan. För att förbandssymbolerna ska visas måste ett *Layer* vara aktiverat.

2. Bestäm vilket *Layer* som symbolen ska appliceras i och aktivera det.

3. Expandera din organisation i ORBAT-listan och välj sedan det förband som ska placeras ut. Vänsterklicka en gång på symbolen på symbolen och flytta därefter muspekaren till rätt plats på lägeskartan för att flytta symbolen.

4. Innan förbandets position sparas framträder en dialogruta för *Symbol Properties* där information avseende förbandet ska fyllas i.

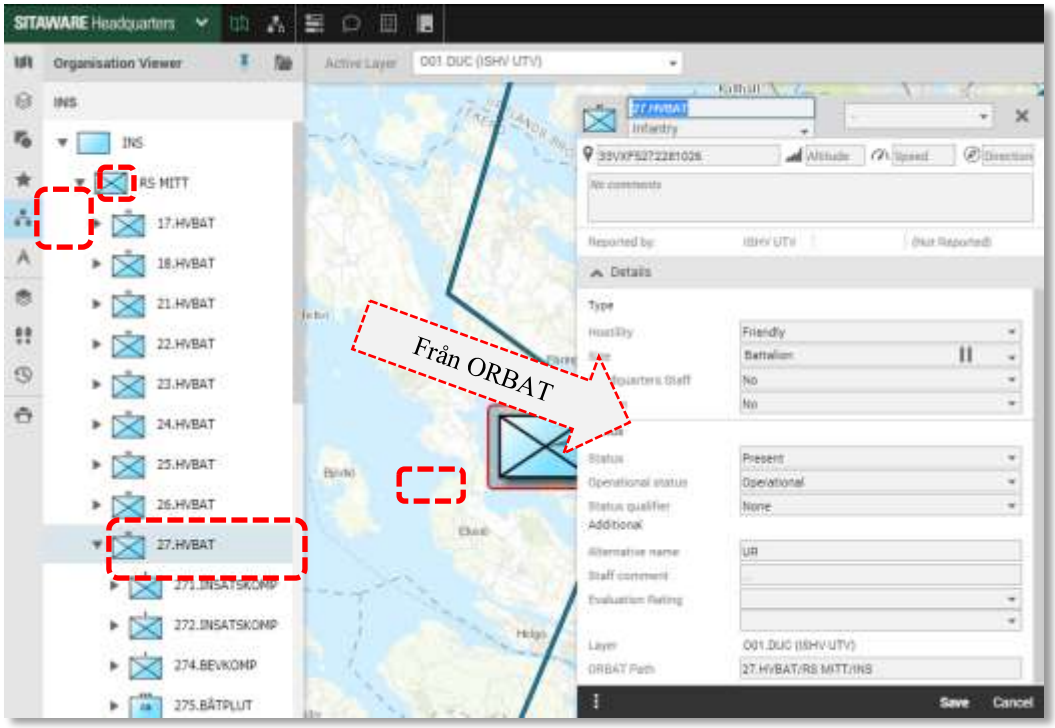

Figur 50. Placering av förband från ORBAT.

OBSERVERA!
Använd enbart ORBAT när man ska placera ut dina egna förband – för att säkerställa rätt information!

En förbandsymbol från ORBAT har viss förbandsinformation kopplad till sig. När symbolen placeras ut öppnas ett fönster (*Symbol Properties)* där förbandsinformationen kan editeras.

Det som är tillåtet att redigera eller lägga till när man använder symboler från *ORBAT* är *Position*, *Comments*, *Headquarter staff* och *Staff Comments*. I *Staff Comments* skrivs tidsnummer och egen signatur för spårbarhet i lägeskartan. Tryck sedan på *Save*.

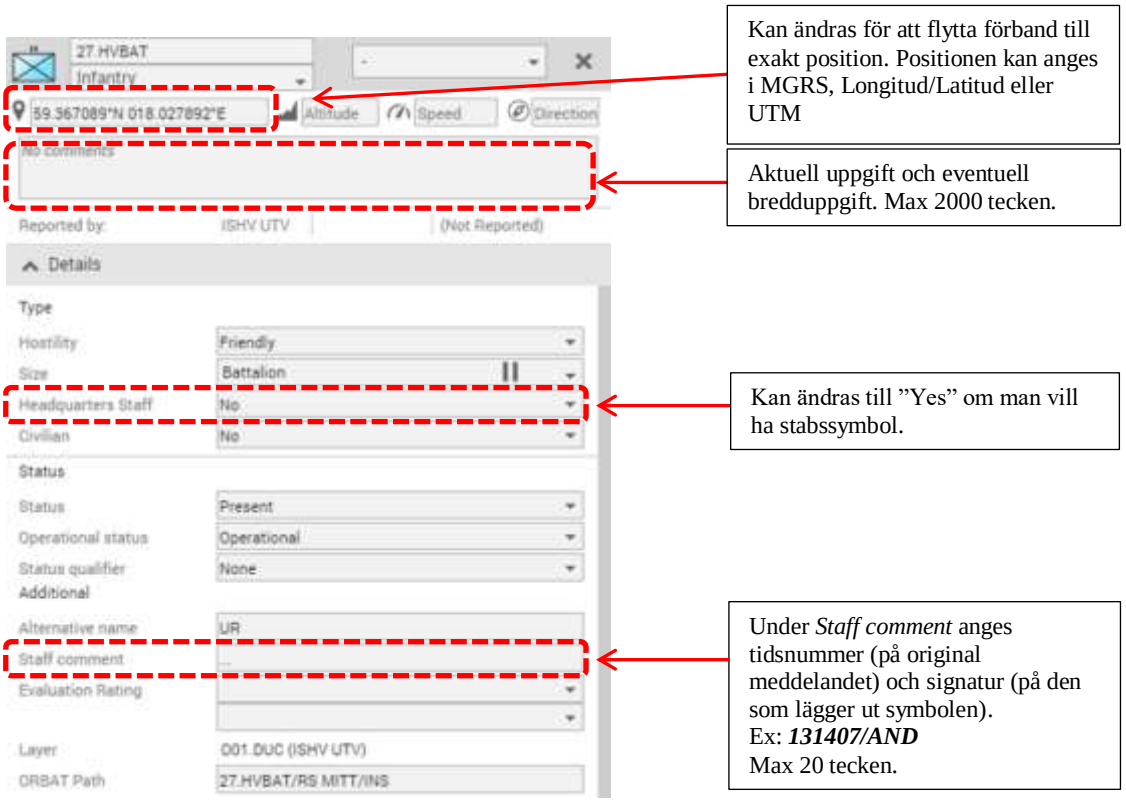

Figur 51. Report Dialog för egna förband.

Den information som automatiskt medföljer förbandssymboler från *ORBAT* är följande:

- Klartextnamn.
- Anropssignal.
- Förbandssymbol.
- Förbandsstorlek.
- Hierarki.
- Tilldelad materiel.

OBSERVERA!
Om man ändrar information som inte är tillåten att redigera kan ORBAT påverkas, vilket kan orsaka en förlust av nödvändig information.

När alla DUC/DUC förbandssymboler är utplacerade i *Layer* O02.DUC/DUC aktiverar man *Layer* O01.DUC. Här placeras förbandssymbolerna för DUC, det vill säga kompanisymboler och övriga direkt under bataljonen lydande enheter.

Nästa steg är att aggregera förbandssymbolerna för DUC/DUC i Layer O02DUC/DUC till förbandssymbolerna för DUC i Layer O01.DUC. Detta görs enligt följande:

1. Tänd O01.DUC och O02.DUC/DUC så att alla förbandssymboler syns.

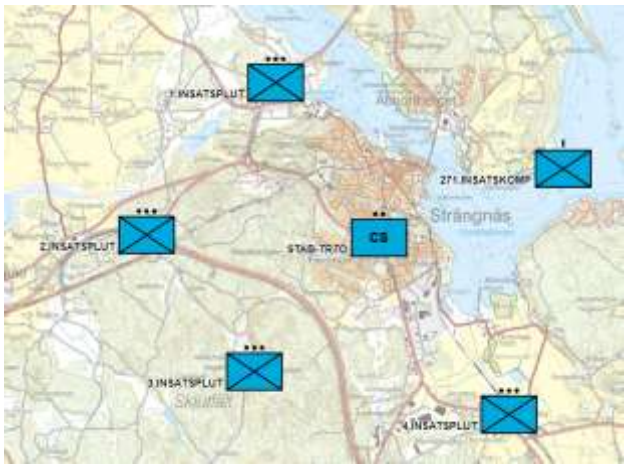

Figur 52 Både Layer O01 och O02 tända och synliga.

2. Högerklicka på kompanisymbolen och välj *Use as Aggregated Unit*.

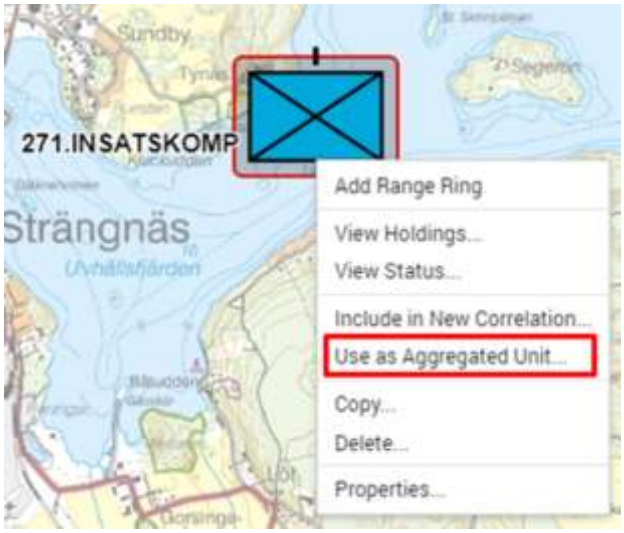

Figur 53 Meny efter högerklick på förbandssymbolen.

3. Klicka en gång på de underenheter som ska ingå i aggregeringen. I den övre menyn visas hur många underenheter som valts. När alla underenheter är markerade med en grå ruta, klicka på *Select*.

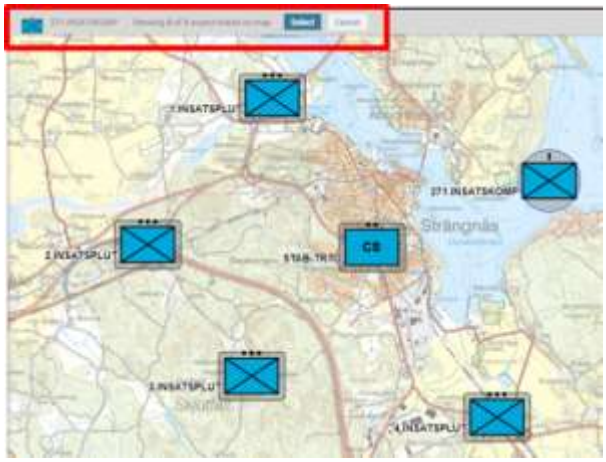

Figur 54 Markerad underenheter vid aggregering.

4. Efter att ha klickat på *Select* öppnas förbandsinformationsfönstret för kompanisymbolen. Längst ner i fältet visas valda underenheter. Här kan man också pausa eller ta bort aggregeringen från en underenhet.

5. Välj därefter *Save* för förbandsinformationen på kompaniet för att spara aggregeringen.

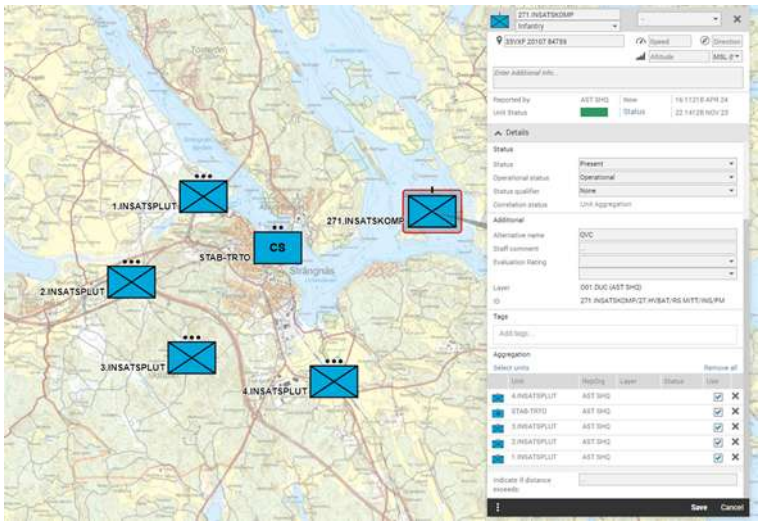

Figur 55 Förbandsinformationsfält efter vald aggregering.

6. Då visas en liten ruta i underkant med siffran på antalet underenheter som är aggregerade till kompanisymbolen.

Kompanisymbolen ligger nu centrerad i kompaniets gruppering. Ifall en underställd enhet i *Layer* O02.DUC/DUC flyttas kommer kompanisymbolen i *Layer* O01.DUC automatiskt att ändra position.

Figur 56 Aggregeringsikon med antal underenheter.

För att justera aggregeringen, högerklicka på kompanisymbolen och välja *Review Aggregation* för att lägga till nya eller ta bort underenheter.

6.3 Övriga kartsymboler

Välj *Symbol Toolbox* i verktygsfältet till vänster för att placera ut en kartsymbol på lägeskartan. För att kunna se kartsymbolerna måste ett *Layer* vara aktiverat. Bestäm vilket *Layer* som symbolen ska appliceras i och aktivera det.

Välj sedan den kartsymbolen som ska användas. I exemplet under används Minfält. Vänsterklicka en gång på symbolen och flytta därefter muspekaren till rätt plats på lägeskartan för att flytta symbolen. Innan positionen sparas på symbolen framträder en dialogruta *Symbol Properties* där information avseende kartsymbolen fylls i.

När man använder kartsymboler från *Symbol Toolbox* är det tillåtet ändra all information i dialogrutan *Symbol properties*. Välj ett lämpligt namn till symbolen och fyll vid behov i inställningar (*Mine Type*, *Mine Pattern*, *Self Destruct* i det här exemplet). *Staff comment* ska alltid fyllas i. Tryck sedan *Save*.

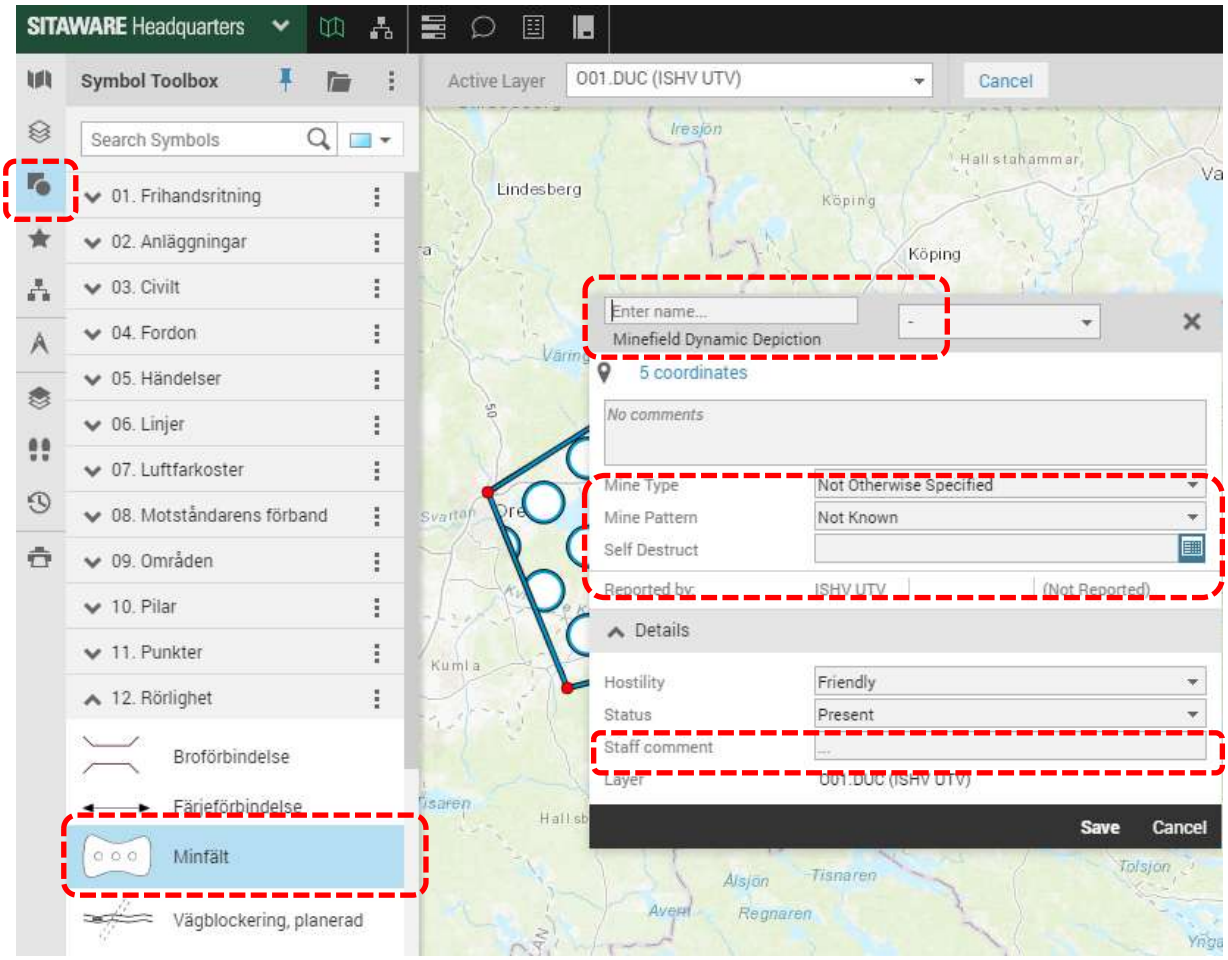

Figur 57 Hantering av övriga kartsymboler.

Sökfunktionen kan användas för att söka efter symboler. Det går att söka med både svensk och engelskt namn.

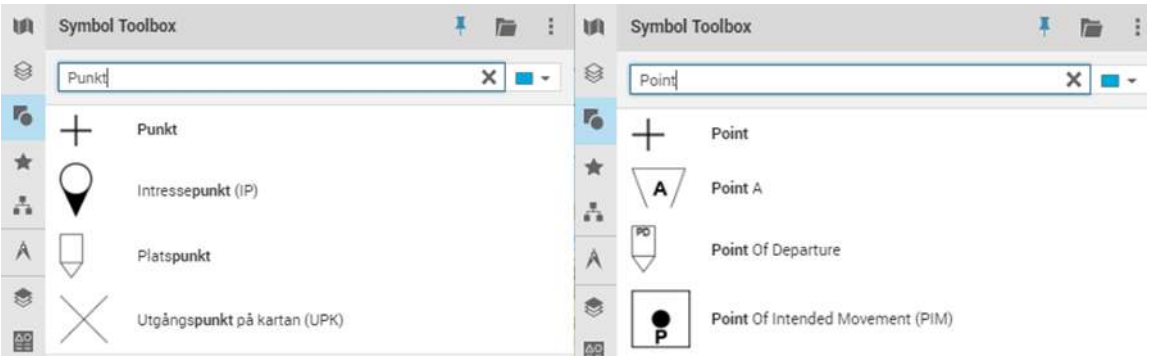

Figur 58 Exempel på sökning av symboler med svenskt namn respektive engelskt namn.

Det går också att söka utifrån tillhörighet (*Hostility*).

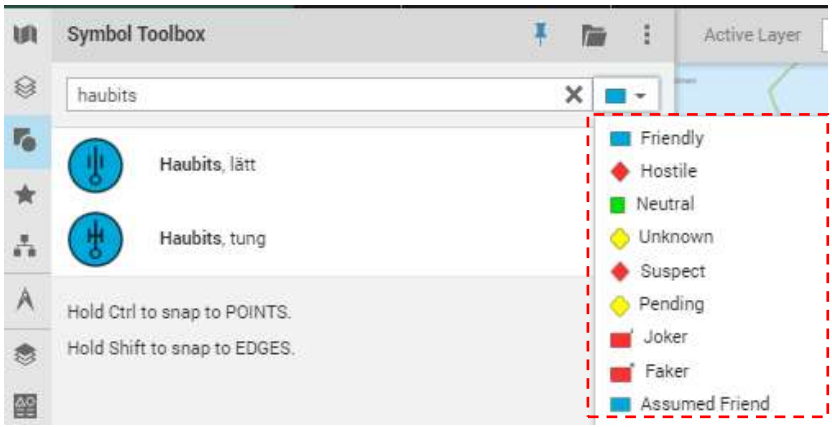

Figur 59 Exempel på sökning av symboler utifrån tillhörighet.

6.4 Flytta symboler som redan finns på lägeskartan

För att uppdatera lägesbilden behöver man inte lägga till nya kartsymboler utan det räcker med att flytta de befintliga kartsymbolerna. Det är inte nödvändigt att aktivera *Layers* för att kunna flytta symboler i kartan som tillhör olika *Layers*. Markera förbandet och dra det till önskad plats på kartan. Markering av förbandet kan göras antingen genom att vänsterklicka för en expanderad dialogruta eller högerklicka för mindre dialogruta. Markera, dra och släpp förbandet på önskad position.

För att flytta flera kartsymboler som ligger i närheten av andra symboler som inte ska flyttas, håll in CTRL på tangentbordet och markera de kartsymboler som ska flyttas eller tas bort. Håll sedan in muspekaren och släpp kartsymbolerna på ny plats för att flytta dem.

Det går även att flytta flera symboler samtidigt genom att använda *Select Objects in Area* till höger i fönstret vid *Mini Map* (Kartöversikt). Tryck på funktionen och markera sedan symbolerna genom att trycka på en punkt, håll in muspekaren och fånga förbanden. När förbandssymbolerna är markerade blir de skuggade.

Figur 60. Flytta kartsymboler med Select Objects in Area.

Klicka därefter på *Edit*. En röd ram visas runt förbanden. Därefter kan alla markerade förband flyttas samtidigt.

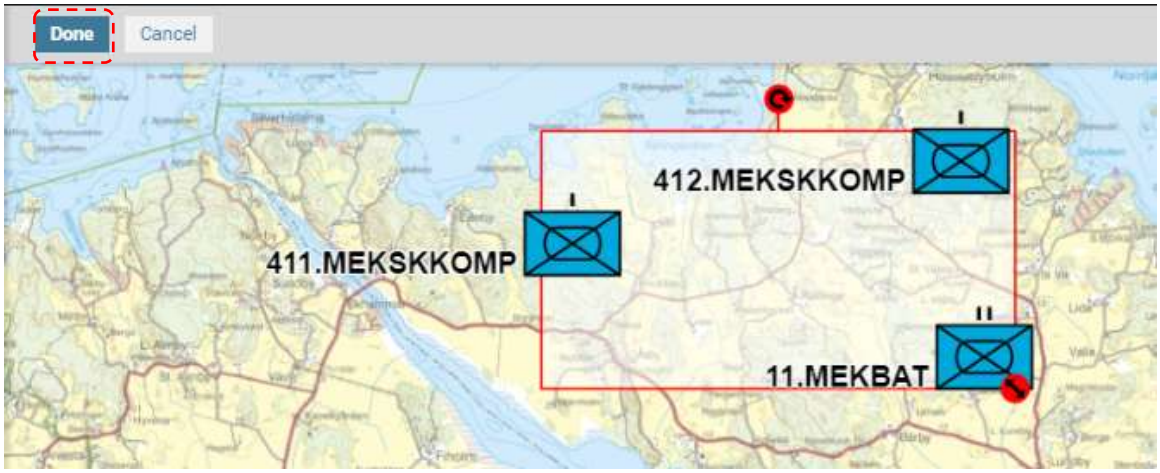

Figur 61. Flytta flera kartsymboler samtidigt.

När den röda rutan med symbolerna har flyttats till en ny plats, klicka på *Done*.

6.5 Flytta förband med koordinat

Ifall *Report Dialog* är öppen kan förband flyttas till en exakt position genom att skriva in koordinater.

Tryck på symbolen och *Report Dialog* öppnas. Skriv in koordinaten i rutan *Location* samt uppdatera *Staff Comment*.

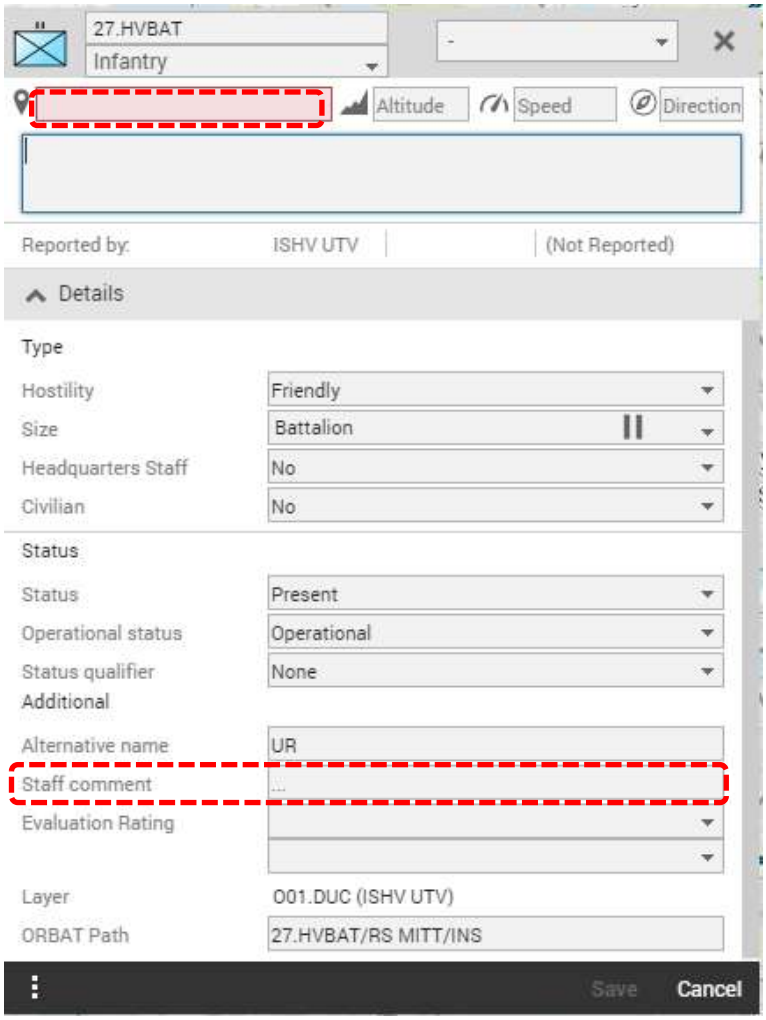

Figur 62 Flytta kartsymboler med koordinater.

När man trycker på *Save* kommer kartsymbolen att flytta sig till den nya bestämda platsen. Genom att använda *Layer Contents* samtidigt har man möjlighet att lokalisera kartsymbolen. Kom ihåg att uppdatera i *Staff Comment* med tidsnummer och signatur.

6.6 Kopiera symboler mellan Layers

Kopiera symboler mellan *Layers* enligt följande:

- Öppna Current Operations.
- Öppna Pictures.
- Välj det *Layer* som ska kopieras till och aktivera det genom att dubbelklicka eller högerklicka och välj sedan *Set Active Layer*.
- Tänd det *Layer* där symbolerna som ska kopieras finns.
- Klicka på *Select objects* in area.

Figur 63. Kopieringsordning.

- Markera alla symboler som ska kopieras genom att dra en ruta runt dem.
- Klicka därefter på *Copy*.

Figur 64 Markerade symboler för kopiering.

- En dialogruta öppnas där namnet på aktiverat *Layer* ska framgå. Ifall dialogrutan inte öppnas, använd istället rullistan för att hitta rätt *Layer*.
- Klicka på *Copy*.

Figur 65 Dialogruta för att välja Layer att kopiera till.

- Nu är symbolerna kopierade till valt mottagar-*Layer*. Genom att släcka det *Layer* som kopierats från och tända det som kopierats till kan resultatet kontrolleras.

För att kopiera enstaka symboler, markera istället en symbol i taget och välj *Copy*.

Ifall du vill kopiera flera symboler samtidigt, håll ner CTRL knappen och klicka på en symbol i taget. När du markerat alla symboler, släpp CTRL knappen och klicka på Copy för att kopiera de symboler man markerat.

6.7 ORBAT Editor

I ORBAT Editor kan man skapa egna organisationsträd såväl blå (egna förband), röda (fiendens förband), lila (civila) och gröna (neutrala enheter). Man kan även koppla *Holdings* till skapade enheter.

OBSERVERA!
Att skapa nya ORBAT görs normalt endast av en administratör eller driftledare.

Att skapa en ny ORBAT görs enligt följande:

1. Klicka på ikonen för ORBAT Editor som finns i den övre menyn.
2. Välj *Create ORBAT*.

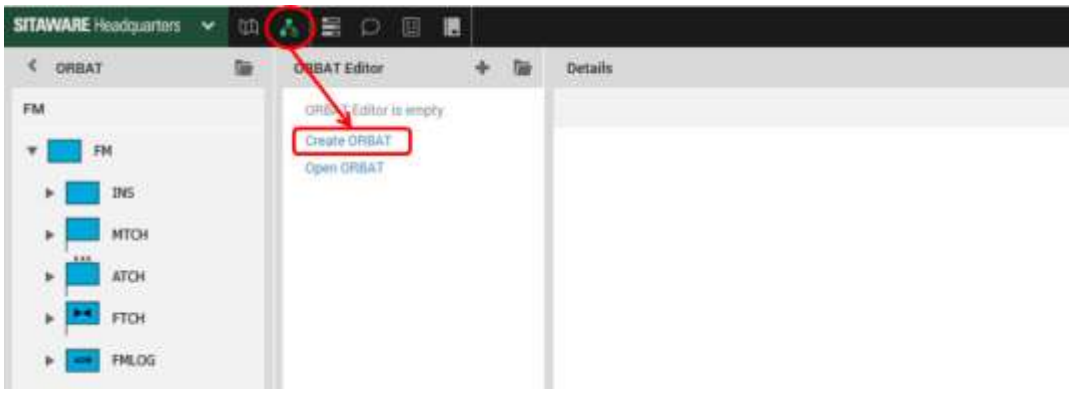

Figur 66 Öppna ORBAT Editor.

3. Namnge ORBAT och klicka på *Create*.

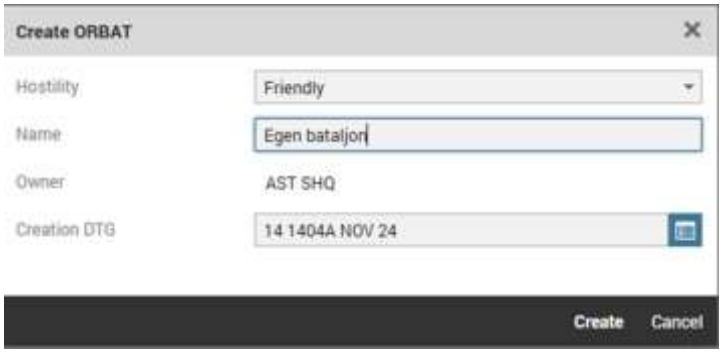

Figur 67 Skapa ett förband i ORBAT Editor.

4. Välj *Create Unit* för att skapa den översta nivån i organisationsträdet.

Figur 68 Skapa en underenhet i ORBAT Editor.

5. Fyll i egenskaperna för förbandet och välj *Create*.

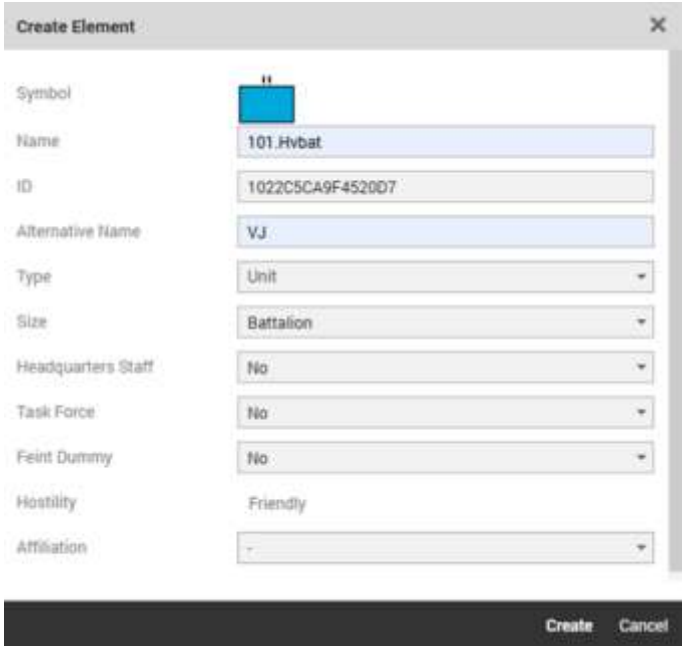

Figur 69 Egenskaper för ett förband i ORBAT Editor.

6. Den översta nivån av förbandet är skapat. Ändra egenskaperna genom att välja *Edit Details* samt lägga till *Holdings* via *Add Holding Types*.

Figur 70 Skapat förband i ORBAT Editor.

7. Högerklicka på förbandet och välj *New Element* för att skapa underenheter.

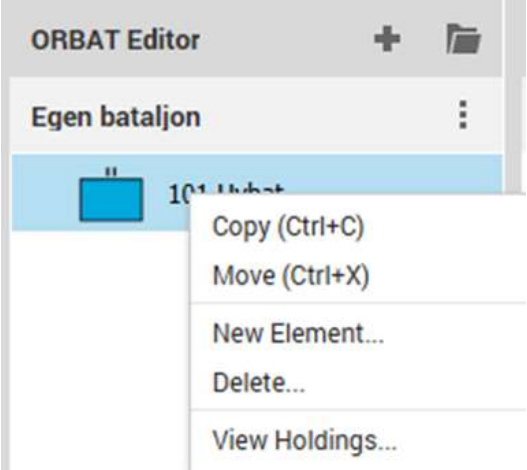

Figur 71 Meny för att skapa underenheter.

8. När en underenhet har skapats kan man även här justera egenskaper och lägga till *Holdings.*

Figur 72 Skapad underenhet.

Ifall att man vill använda förband från befintliga ORBAT görs det enligt följande:

1. Öppna en befintlig ORBAT i det vänstra fönstret.

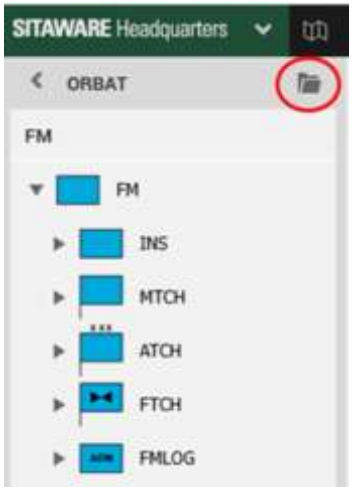

Figur 73 Öppna en befintlig ORBAT.

2. Klicka på den ORBAT som ska nyttjas.

Figur 74 Befintliga ORBAT i SitaWare HQ.

3. När ORBAT är på plats i det vänstra fönstret expanderar man det organisationsträdet tills man har hittat det förbandet som man vill nyttja i sin egenbyggda ORBAT.

4. Genom att med hjälp av musen dra förbandet från ORBAT-fönstret till ORBAT EDITOR-fönstret kan man kopiera förband från en befintlig till sin egenbyggda ORBAT.

   Alla underenheter som finns i den befintliga ORBAT följer med i kopieringen.

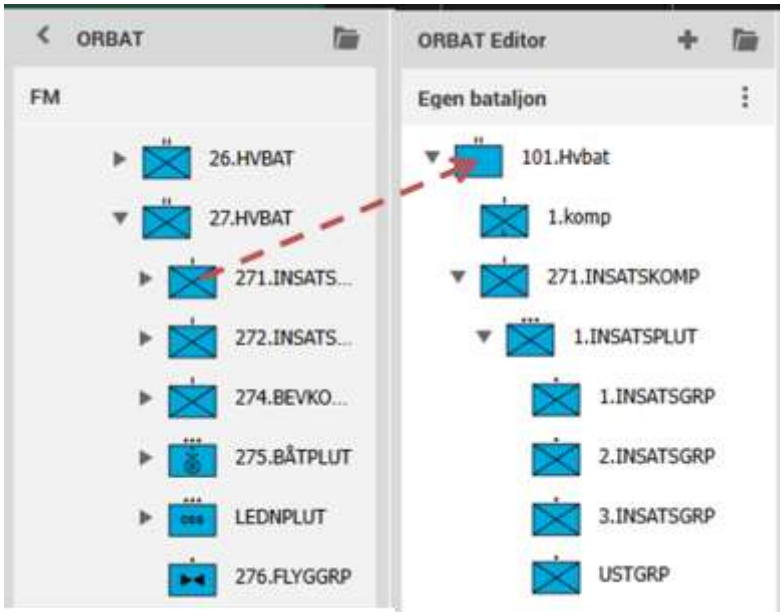

Figur 75 Skapa enheter med "drag and drop".

Egenbyggda ORBAT sparas automatiskt och kan öppnas och användas via *Organisation Viewer*.

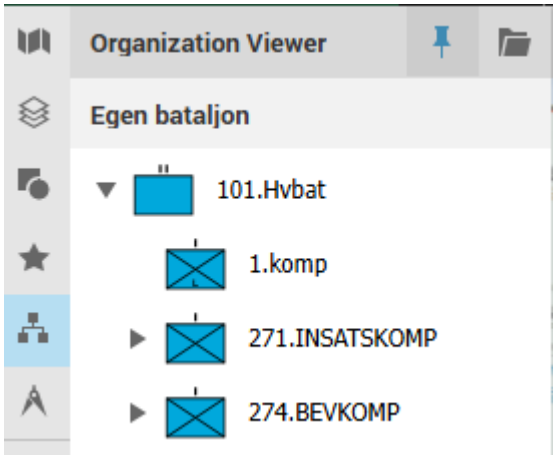

Figur 76 Egenbyggd ORBAT öppnad i Organisation Viewer.

6.8 Korrelera rapporter

Funktionen *Correlation* kan användas för att sammankoppla rapporter. Detta kan vara användbart ifall det har inkommit flera rapporter som tros kunna beröra samma händelse. Rapporterna kan antingen komma från samma eller olika rapportörer, och kan även ha rapporterats in olika tider.

Vanligen inkommer rapporter i *Layer U01.Händelser*.

***Correlation* görs enligt följande:**

1. Tänd *Layer U01.Händelser* där de inrapporterade symbolerna finns.

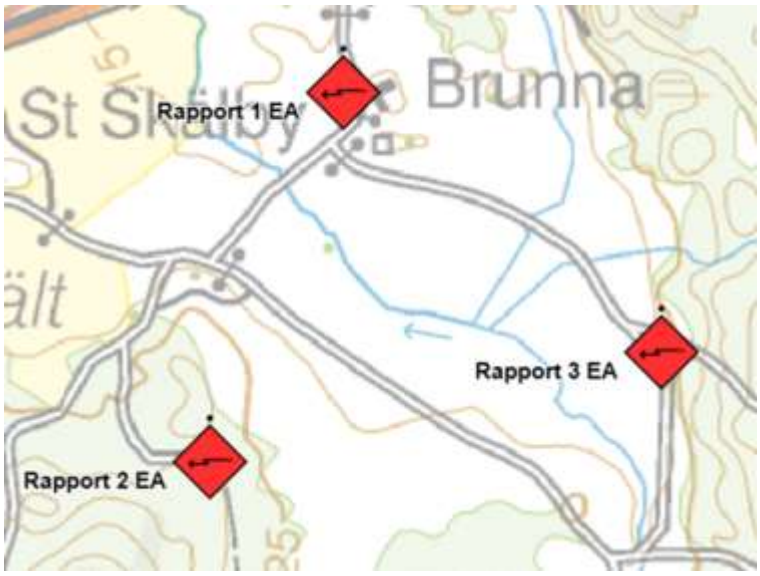

Bild 1. Exempel på lägesbild med tre tända händelselager med varsin patrullsymbol.

2. Högerklicka på en av symbolerna och välj *Include in New Correlation*.

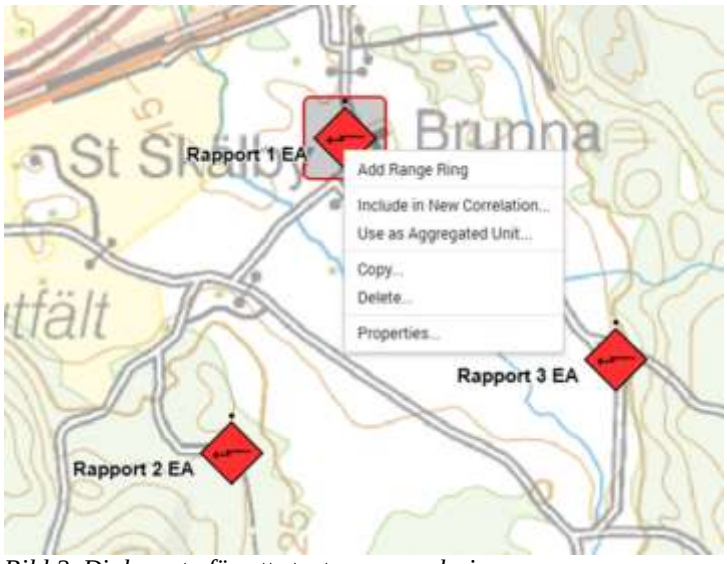

Bild 2. Dialogruta för att starta en correlering.

3. Markera de symboler som ska ingå i *Correlation*. I den övre delen av fönstret syns en dialogruta som visar antalet valda symboler. I den nedre delen visas ett annat fönster med de valda symbolerna.

   Om man i formuläret vid *Name* ändrar till *Manual* innan man klickar på *Done* kan man namnge den korrelerade symbolen

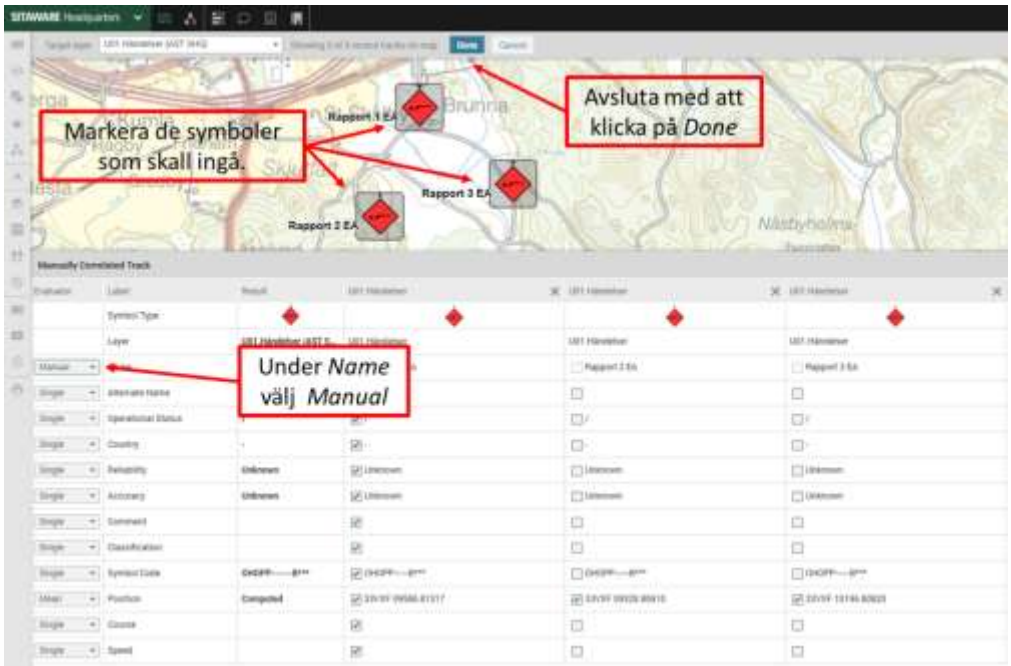

Bild 3. Correlation-fönster.

4. För att namnge den korrelerade symbolen, markera den och skriv in namnet i symbolrapporten. Avsluta med *Save*.

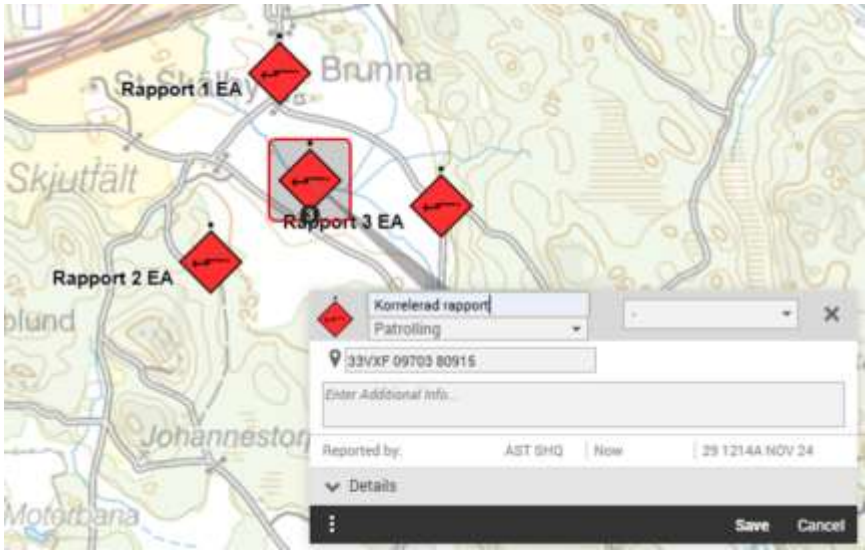

Figur 77 Byt namn på symbolen för korreleringen.

5. Nu finns den korrelerade symbolen med angivet namn och en siffra i underkant på symbolen. Siffran anger hur många symboler som är kopplade till den korrelerade symbolen.

6. Högerklicka på den sammanställda *Correlation*-symbolen och välj *Review Correlation* för att editera underlaget.

Bild 4. Dialogruta för att editera en Correlation.

7. På vänster sida i formuläret (se bild på nästa sida) finns ett antal parametrar som kan ändras utifrån bedömandet och ytterligare information som inkommer om rapporterna.

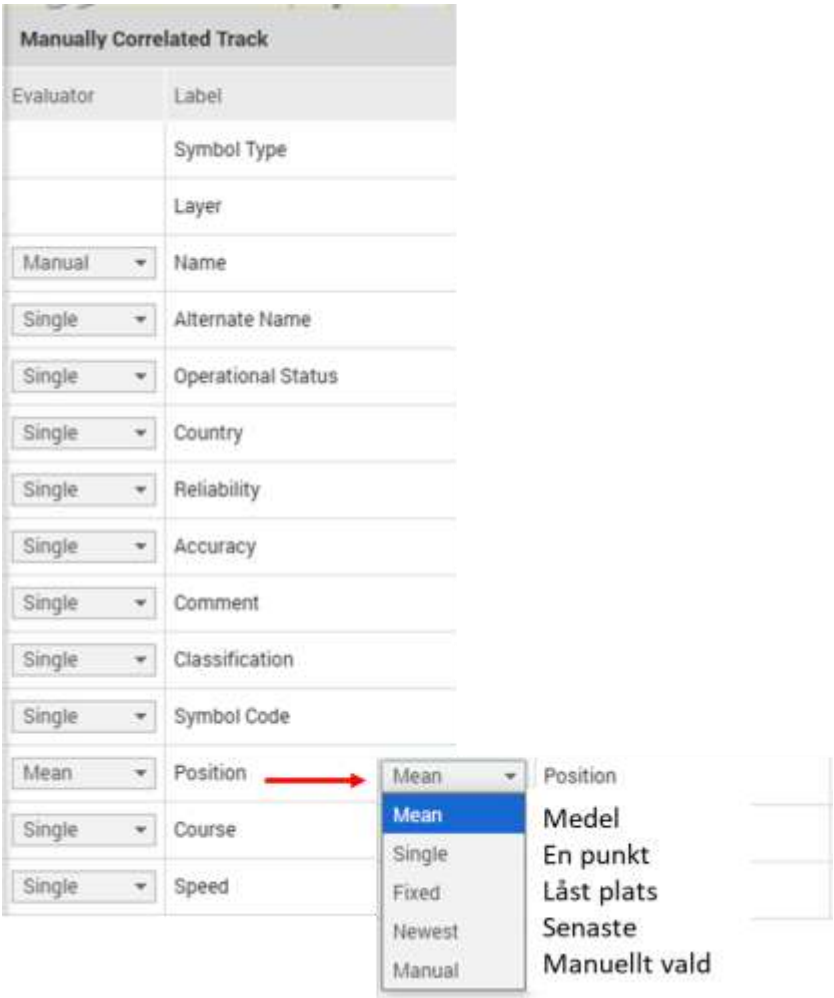

Bild 5. Exempel på parametrar vid korrelering.

Efterhand som man har fastställt huruvida det var en, två eller tre patruller kan de uteslutna rapporterna tas bort från korrelationen så att man till slut har endast fastställda rapporter kvar.

7 Bookmarks

7.1 Allmänt

Bookmarks gör det möjligt att producera fördefinierade *Pictures* som kan användas som hjälpmedel vid stabsorienteringar och andra genomgångar. En *Bookmark* innehåller valda *Layers*, kartbakgrund, ljusstyrka på kartan och zoomningslägen.

För att uppdatera ett fastställt *Bookmarks*, ställ in kartan så att den visar det område som ska visas, zooma till rätt nivå och panorera kartan så att rätt terrängområde visas. Tänd sedan de *Layers* som ska visas i aktuellt *Bookmark* och kontrollera att bilden rätt ut. Högerklicka därefter på *Bookmark* och välj *Update*.

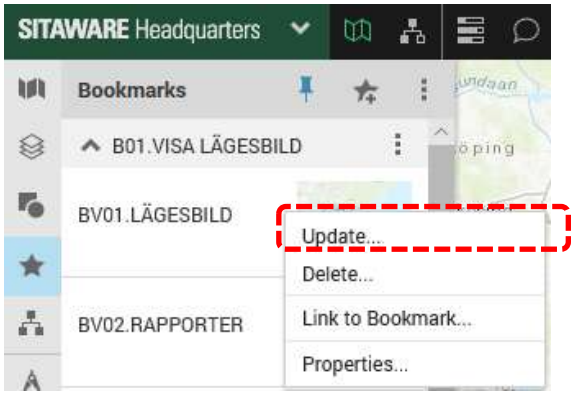

Figur 78 Uppdatering av Bookmarks.

7.2 Att spara presentationen efter en stabsorintering

Efter en stabsorientering så kan åhörare erhålla en kopia av alla *Bookmarks* som ingår i en *Bookmarks Folder* i form utav en Powerpoint presentation. Detta görs genom att klicka på de tre prickarna i foldern och välj *Export to PowerPoint*.

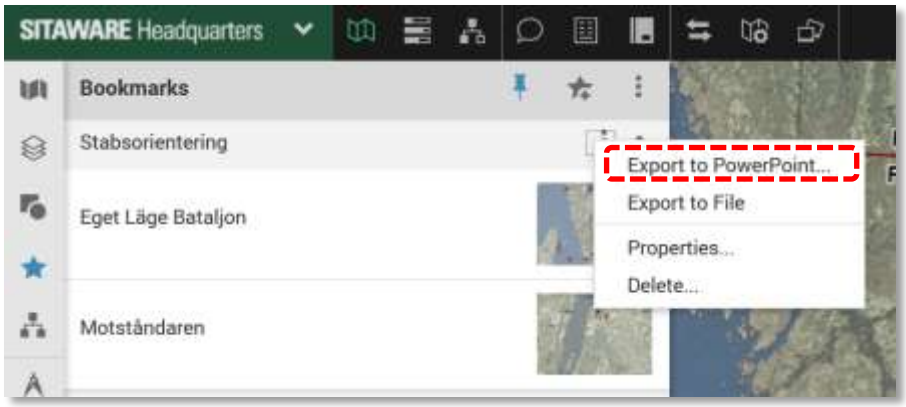

Figur 79 Export till Powerpoint.

8 Utskrifter från lägeskartan

8.1 Allmänt

I SitaWare HQ kan man skriva ut kartor och oleat på skrivaren. I ISHv sker utskriften i A4-format. Vid behov kan flertal sidor kombineras för att täcka ett större område.

Utskrift är en export av information och IMPEX blankett ska föras om det inte finns reglerat i stående stabsorder att utskrifter av vissa dokument ska ske med givna intervall.

8.2 Enkel utskrift från SitaWare HQ

Tryck på figuren som liknar en skrivare i verktygsfältet till vänster för att skriva ut en karta från SitaWare HQ.

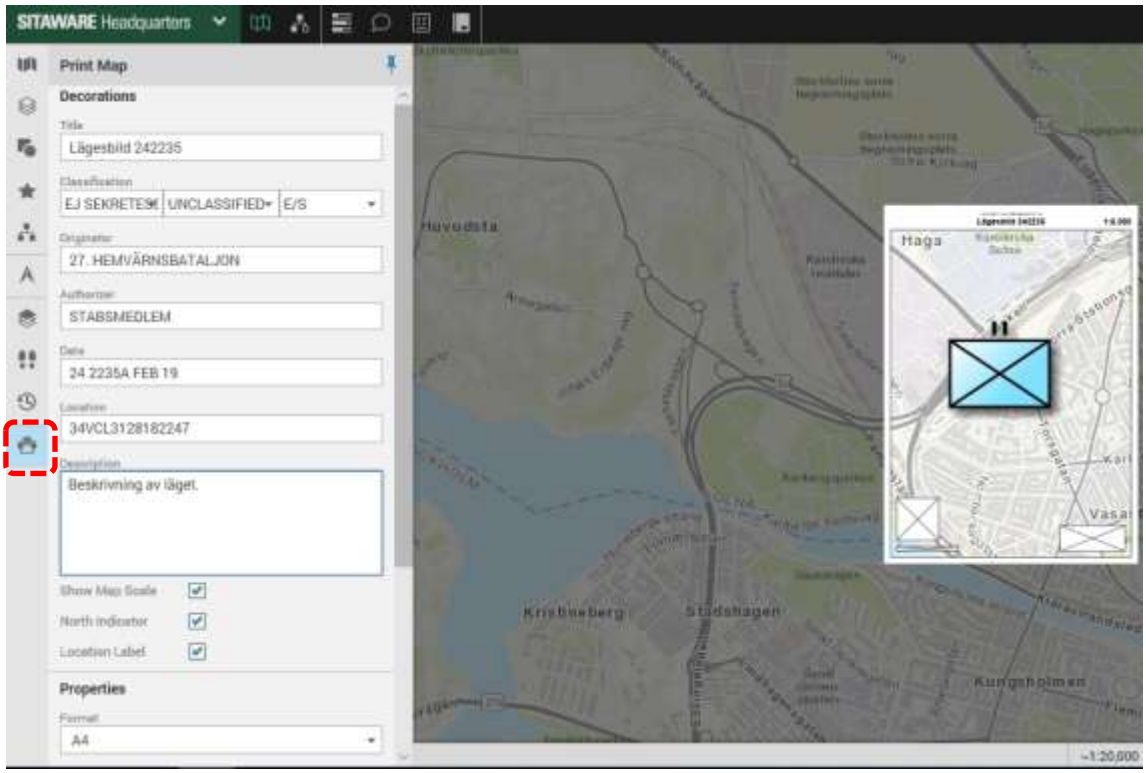

Figur 80 Utskrift från SitaWare HQ.

Fyll i följande information:

Fält	Beskrivning
Title	Namnet på utskriften t.ex. ”Lägesbild TNR”.
Classification	Informationssäkerhetsklassificering. Välj antingen: ”EJ SEKRETESS / UNCLASSIFIED E/S” eller ”BEGRÄNSAT HEMLIG / BH”
Originator	Vilket förband man tillhör samt vem man är.
Authorizer	Den som har godkänt utskriften tex. stabschef
Date	Fylls i automatiskt.
Location	Fylls i automatiskt.
Description	Ev. beskrivning eller sammanfattning av läget.

Tabell 2: Information till utskrift.

Ställ sedan in kartan utifrån vad man vill skriva ut, exempelvis vilka *Layers* som ska vara tända, om man ska ha rutnät, om man ska dimma kartan och vilken del av terrängen som ska vara med. Välj därefter ”*Print*” för att skriva ut från kartan.

8.3 Spara karta som PDF

Om man vill spara kartan som PDF väljer man att trycka på *Save* istället för *Print*.

8.4 Spara karta som en bild

För att spara en karta som en bild ställer man in kartan över området och aktiverar de *Layers* som man vill ha med i läget, högerklicka därefter på ett fritt område på kartan och Välj *Save or Copy Map as Image* och sedan *Save Map as Image*.

Välj vart i mappstrukturen bilden ska sparas och använd fastställd filnamnsstruktur. Kartbilden är nu sparad (med symboler) och kan användas i till exempel presentationer.

OBSERVERA!
Utskriften ska alltid informationssekretessklassificeras!

8.5 Flersidig utskrift

För att skriva ut flersidig utskrift för att täcka ett större område väljer man att bocka i *Poster Mode* och ställer sedan in nödvändiga inställningar. Då kommer kartan att skrivas ut med start från A1 i den ordning som presenteras (se exempel på nästa sida) vilket möjliggör att man kan sätta ihop kartan utifrån de utskrivna delarna.

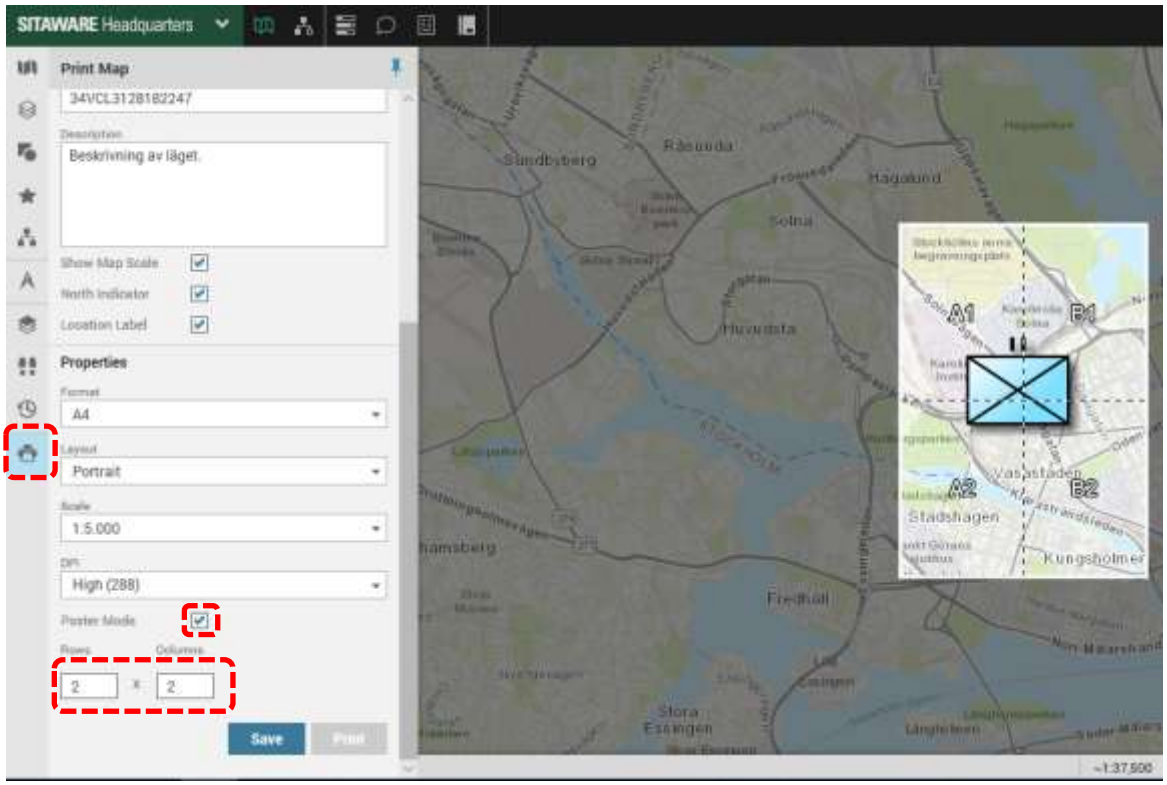

Figur 81 Flerutskrift över större område i SitaWare HQ.

8.6 Skriva ut oleat

Utskrivna kartor och oleat kan användas för att tydligare kunna visualisera stridsplaner, stridsidéer och stabsorienteringar för ett större antal åhörare ifall man inte har tillgång till SitaWare HQ vid presentationstillfället.

I kombination med utskrift på Overhead-plast kan distribution av UPK-punkter ske till DUC. Kontrollera med stab- och sambandsexpeditionen att skrivaren är laddad med OH-plastark och att ingen annan ska skriva ut innan man påbörjar stegen nedan.

Detta görs enligt följande:

1. Dimma kartan till dessa ljusaste inställningen (*Adjust Dim*) så kartbakgrunden blir helt vit. Lägg därefter på *Toggle grid* det vill säga rutnäten.

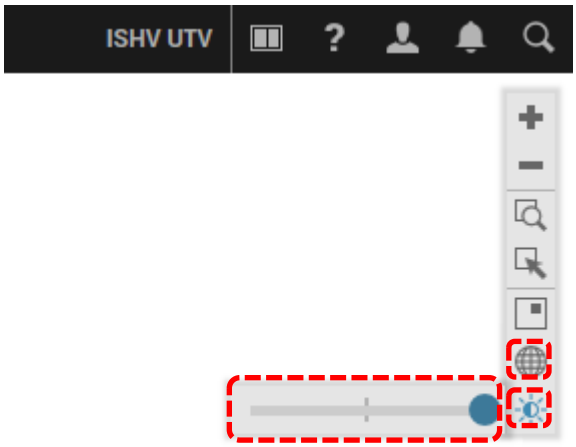

Figur 82 Adjust Dim och Toggle Grid vid utskrift av Oleat.

2. Ställ därefter in kartans plats och fyll i de nödvändiga fälten.

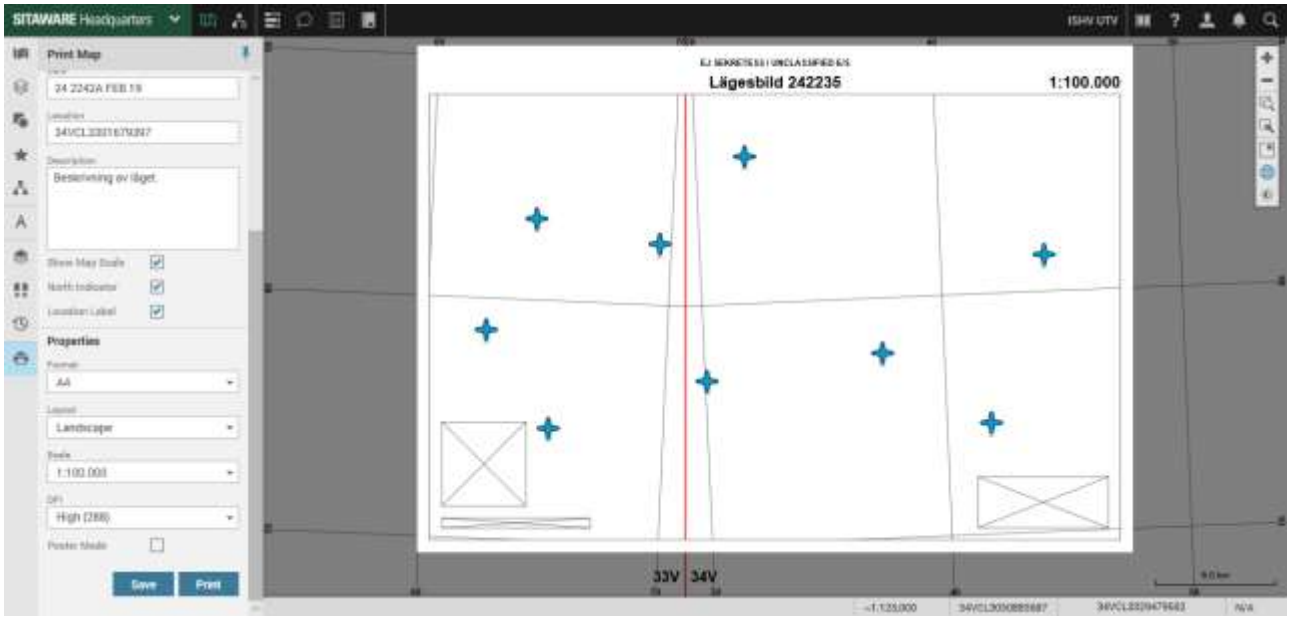

Figur 83 Utskrift av UPK som oleat.

3. Bilden nedan är nu redo att skrivas ut. I det här exemplet 1:100.000 på ett A4. Ofta är *Poster Mode* ett lämpligt val.

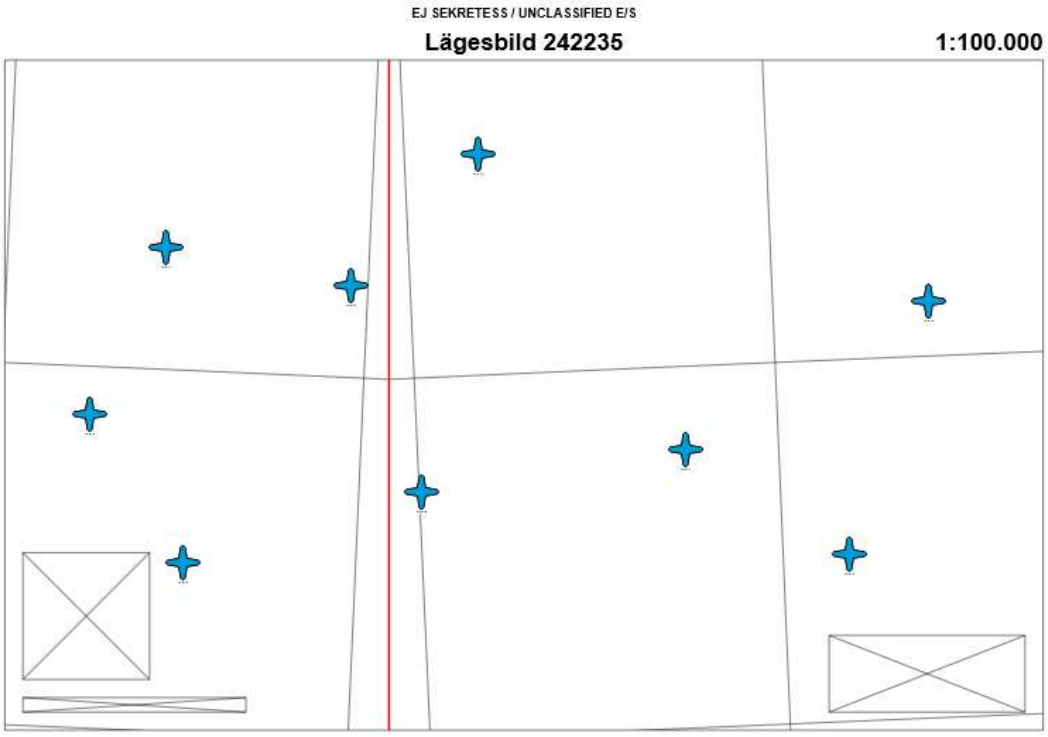

Figur 84 Utskrift av UPK som oleat.

9 Dela lägesbild med andra staber

9.1 Allmänt

Ifall en stab önskar dela med sig av information till annan stab så kan det vara lämpligt att dela med sig av *Layers*-informationen digitalt.

Alla förband i Försvarsmakten som använder SitaWare HQ har i princip samma information i sina *Layers*. För att undvika att blanda ihop egna och annat förbands *Layers* så ska exporterade *Layers* ges unika namn. Var noga med att döpa *Layers* så att mottagaren efter sin import direkt kan utgöra vilket som kommer från ditt förband.

I SitaWare HQ finns det en *Picture* för **IMPORT** och en för **EXPORT** som används för detta ändamål.

9.2 Exportera Layers

Att exportera ett *Layer* görs enligt följande:

1. För att exportera ett *Layers*, högerklicka på det *Layers* som ska delas med ett annat förband och välja *Copy Layer*.

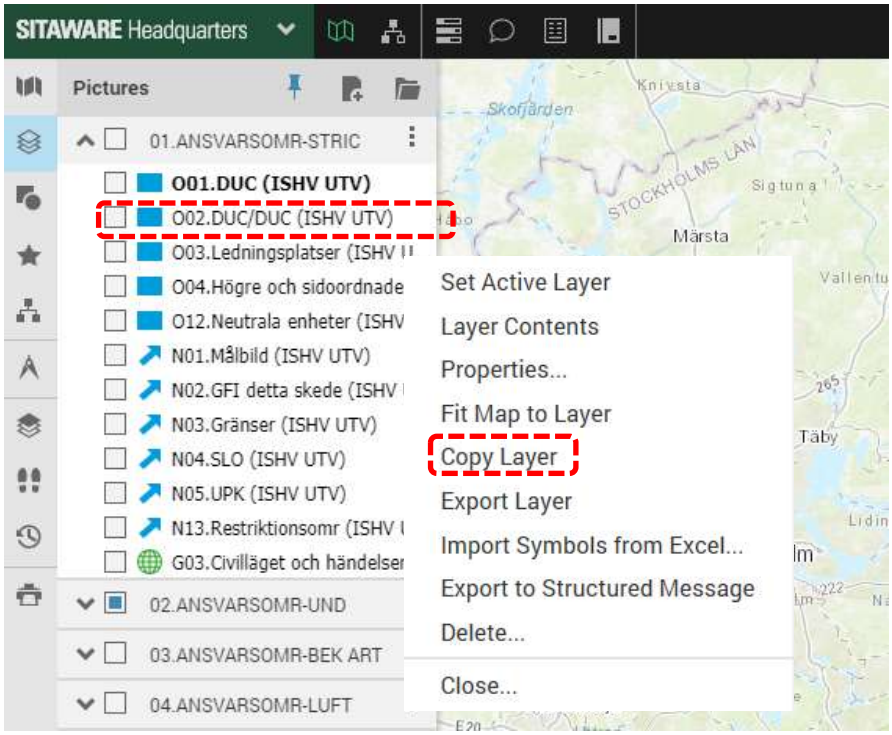

Figur 85 Kopiera Layers vid export.

2. Högerklicka på *Picture* **EXPORT** och välj *Paste Layer*.

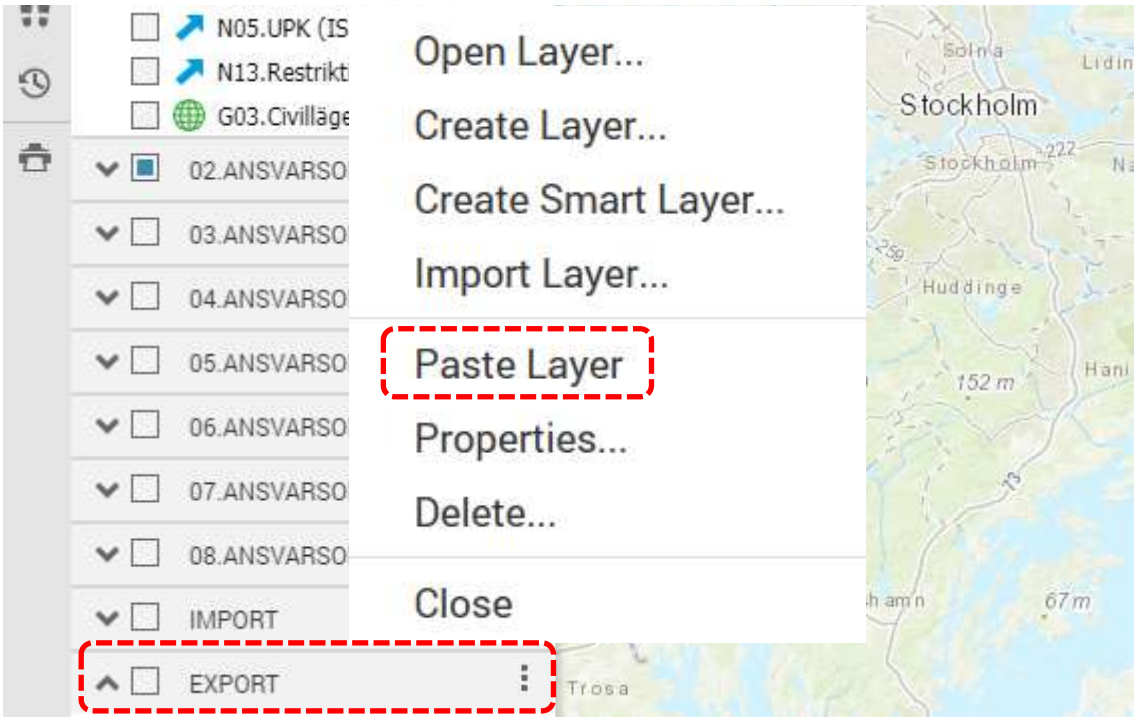

Figur 86 Klistra in Layers till Export-Picture.

3. Högerklicka på *Layer* i **EXPORT** och välj *Properties…* namnge *Layer* enligt filnamnsstrukturen och tryck på *Save*.

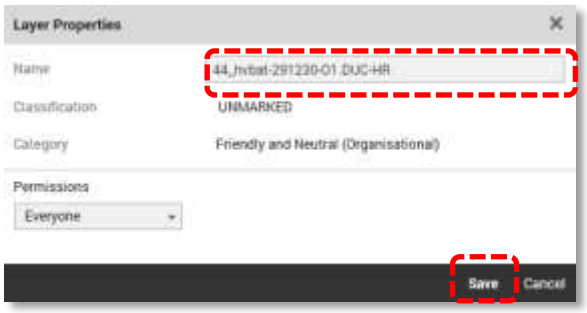

Figur 87 Dialogruta vid byte av Layersnamn.

Exempel
44hvbat-291230-O1.DUC-BH

4. Nu är *Layer* redo för export. Detta görs genom att högerklicka på *Layer* i *Picture* **EXPORT** och välja *Export Layer*. Spara sedan avsett *Layer* i mappstrukturen så att stabs- och sambandsexpedition kan fånga upp det och sända det till mottagande förband.

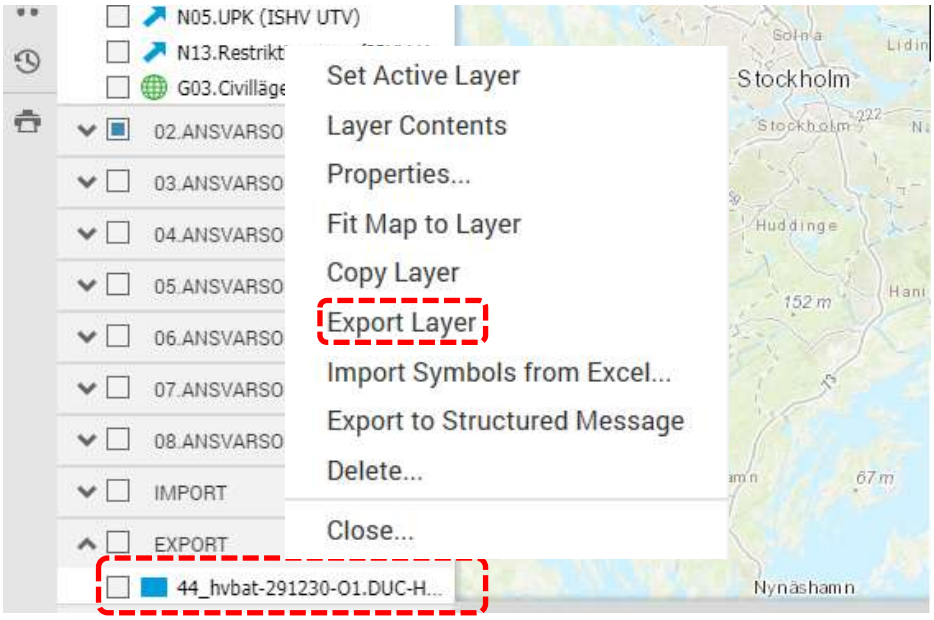

Figur 88. Exportera ett Layers.

9.3 Importera Layers

Att importera ett *Layer* görs enligt följande:

1. För att importera ett *Layer*, högerklicka på *Picture* **IMPORT** och välj sedan *Import Layer*.

2. Utforskaren visas. Använd mappstrukturen för att lokalisera och välja det *Layer* som ska importeras.

3. Markera *Layer* och tryck *Öppna*. Det importerade *Layer* har nu lagts till i Picture **IMPORT**.

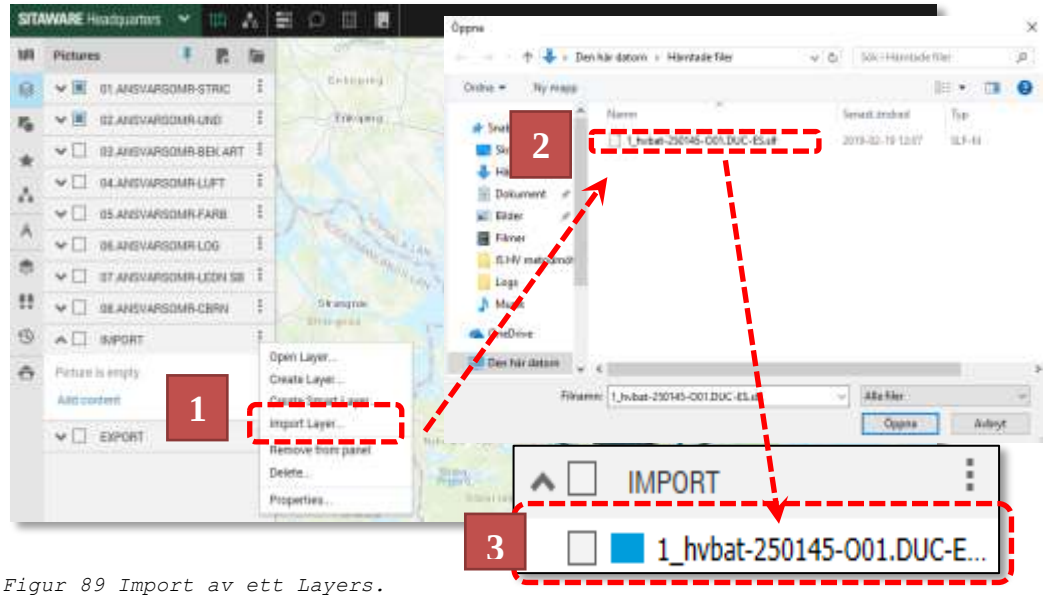

Figur 89 Import av ett Layers.

10 Verksamhetsjournal

10.1 Allmänt

Journal används i ISHv som verksamhetsjournal över alla händelser rörande verksamheten i staben. Utöver inkomna och utgående ärenden ska också stabsorientering, ordergivning, besök et cetera antecknas i verksamhetsjournalen. Verksamhetsjournalen följer den grund som beskrivs i *Handbok Stabstjänst Grunder 2016* samt gällande lagstiftning.

Funktionen är lättöverskådlig och till för att bataljonsstaben ska kunna ha ett spårbart, ensat och aktuellt läge över alla ärenden som hanteras inom verksamheten.

Det finns möjlighet att bevaka sin egen ”tagg” för varje sektion samt sortera informationen på ett lättöverskådligt sätt.

Ett ärende i journalen kan inte raderas, texten kan redigeras eller raderas men själva ärendet kan inte tas bort. Skrivs ett ärende in felaktigt bör det taggas till taggen *papperskorg*.

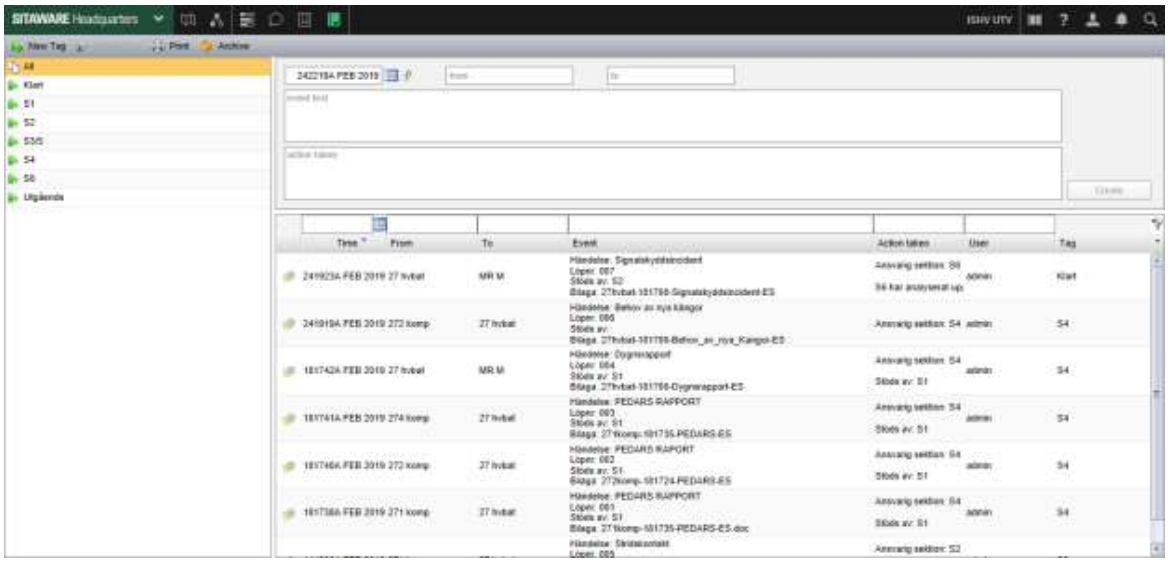

Figur 90 Verksamhetsjournalen i SitaWare HQ.

10.2 Verksamhetsjournalens innehåll

Följande kolumner finns i verksamhetsjournalen.

Kolumn	Användning
Time (TNR)	**Ska ändras** till aktuellt tidsnummer. TNR är de första sex siffror som står på ursprungliga dokumentet/filen/m-blanketten. Formatet är DDTTMM Tidzon Månad År. Ex: 020814A FEB 2019. Klockan 08:14 (normaltid) den 2:a februari 2019.
From (Från)	Vilket förband som sänt meddelandet i **klartext**. Ex: 261. komp eller 20. hvbat.
To (Till)	Vilket förband som mottagit meddelandet i **klartext**. Ex: 181. komp eller 37. hvbat.
Event (Händelse)	**Händelse:** **Löpnr:** **Stöds av:** **Bilaga:** **Händelse:** Här skrivs vad meddelandet handlar om, skriv tillräckligt mycket så att alla som läser förstår. Vill man läsa mer detaljer får man använda Löp-nr/TNR för att leta upp originaldokumentet. **Löpnr:** Treställigt ex 001, 002, 003 som också skrivs på Dokumentet/M-Blanketten. På de digitala dokumenten skrivs Löp-nr in i filnamnet när den sparas. **Stöds av:** Här noteras vilken eller vilka sektioner som Strich/VB bestämt ska ha informationen och/eller stödja ansvarig. **Bilaga:** Eventuellt dokument eller annan form av digital fil. Hänvisa vart filen finns och vad filen heter, ex ”mapp/filnamn.doc”
Action taken (Åtgärder)	Här ska alla åtgärder och beslut dokumenteras, alltid med ett TNR. Detta för att kunna följa vilka åtgärder och beslut som har vidtagits respektive fattats samt när. Ange signaturen på den som gjort åtgärden/tagit beslutet. Ex: ”S2: Analyserat underlaget och rapporterat ärendet till högre chef TNR 020850. / signatur. S3: Orienterat DUC TNR 020830. / signatur.”
*Tag (*Ansvarig sekt)	Vilken sektion som Strich/VB bestämt är ansvarig.
Creation Time (Skapad)	Skapas automatiskt när ärendet läggs in i verksamhetsjournalen eller när ärendet uppdateras.
User (Användare)	Skapas automatiskt. Den användare som gjorde senaste ändringen.

Tabell 3 Användning av kolumner i verksamhetsjournalen.

10.3 Utskrift av verksamhetsjournal

Utskrift av verksamhetsjournalen görs enligt följande:

1. Tryck på *Print*.

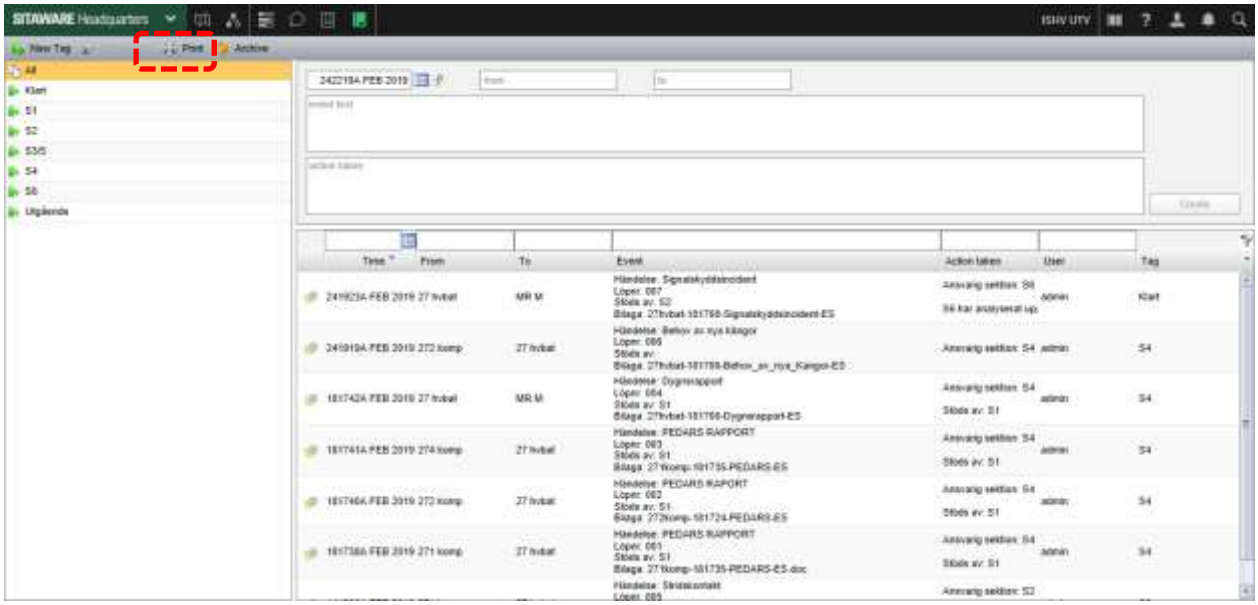

Figur 91 Skriva ut verksamhetsjournalen.

2. Verksamhetsjournalen visas i tabellformat. De mörka fälten är den senaste versionen av ett ärende. De ljusa fälten är tidigare versioner. Detta skapar en mer omfattande spårbarhet avseende varje ärende och dess hantering.

3. Tryck på *Print* för att skriva ut eller markera allt för att kopiera till Excel.

Figur 92. Skriva ut eller kopiera verksamhetsjournalen.

10.4 Sortera informationen i verksamhetsjournalen

För att sortera informationen i verksamhetsjournalen, högerklicka på valfri kolumn och välj *Configure Sort*.

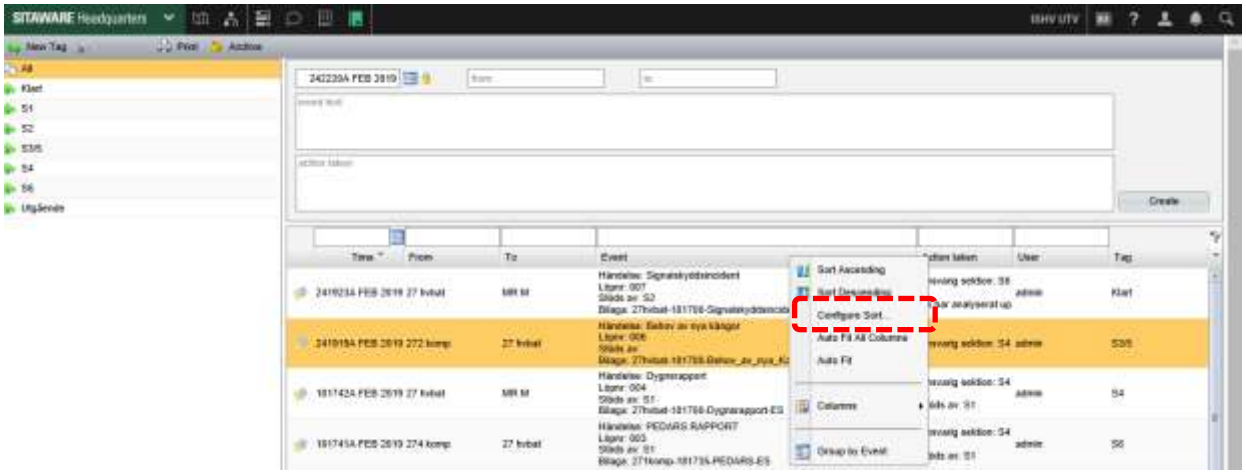

Figur 93. Sortera information i verksamhetsjournalen.

Efter att man har tryckt på *Configure Sort* dyker dialogrutan *Sort* upp på skärmen. Här kan man ställa in vad man vill visa och i vilken ordning.

I exemplet sker sorteringen först på *Tag* i ordningen *Descending* (nedåtstigande) och därefter *Time* (tid) i ordningen *Ascending* (stigande) och sedan *Event* (händelse) i ordningen *Ascending* (stigande). Tryck *Apply* när rätt ordning är inställd.

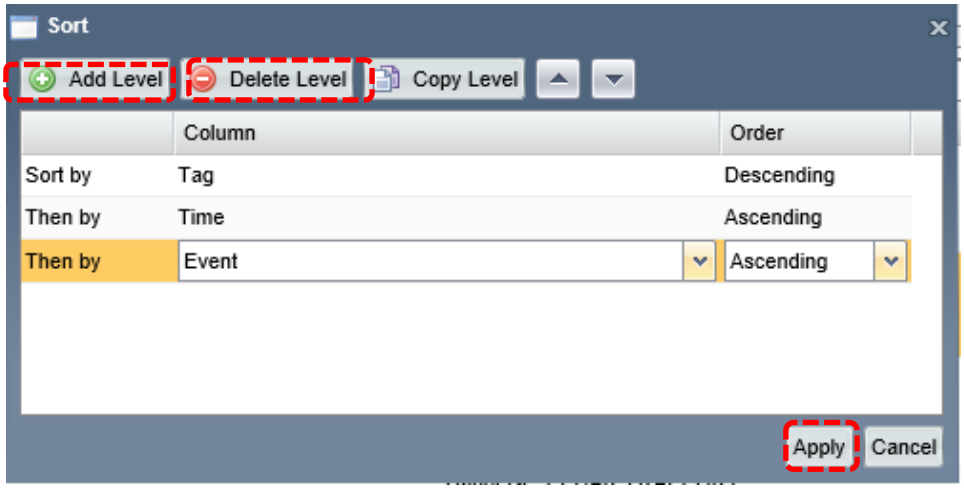

Figur 94. Dialogrutan "Sort" i verksamhetsjournalen.

10.5 Gruppera informationen i verksamhetsjournalen

För att sortera informationen kan man gruppera den i expanderbara fält. I exemplet nedan högerklickar man på *Tag* eller annan valfri kolumn och väljer *Group By Tag*.

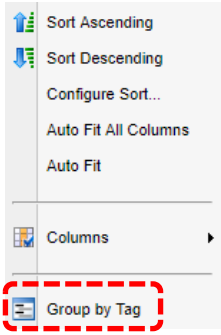

Figur 95 Gruppera information i verksamhetsjournalen.

När informationen har grupperats kommer alla ärenden att sorteras enligt nedan om man väljer att gruppera efter *Tag*.

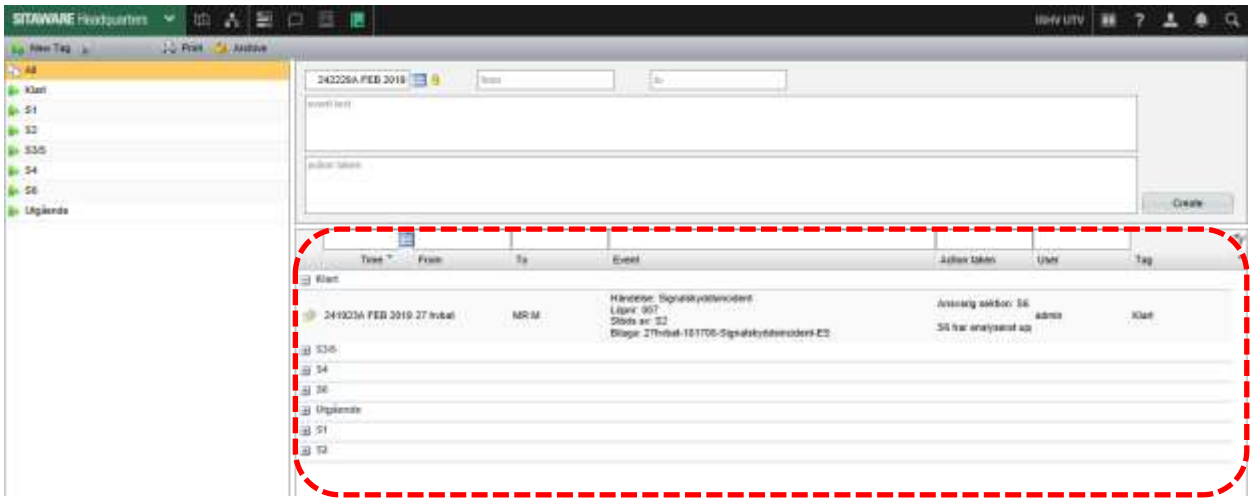

Figur 96. Information sorterad i grupper i verksamhetsjournalen.

10.6 Lägga till och ta bort kolumner

För att lägga till och ta bort kolumner, högerklicka på valfri kolumn och välj sedan *Columns*. Klicka i eller ur de kolumner som ska visas i verksamhetsjournalen.

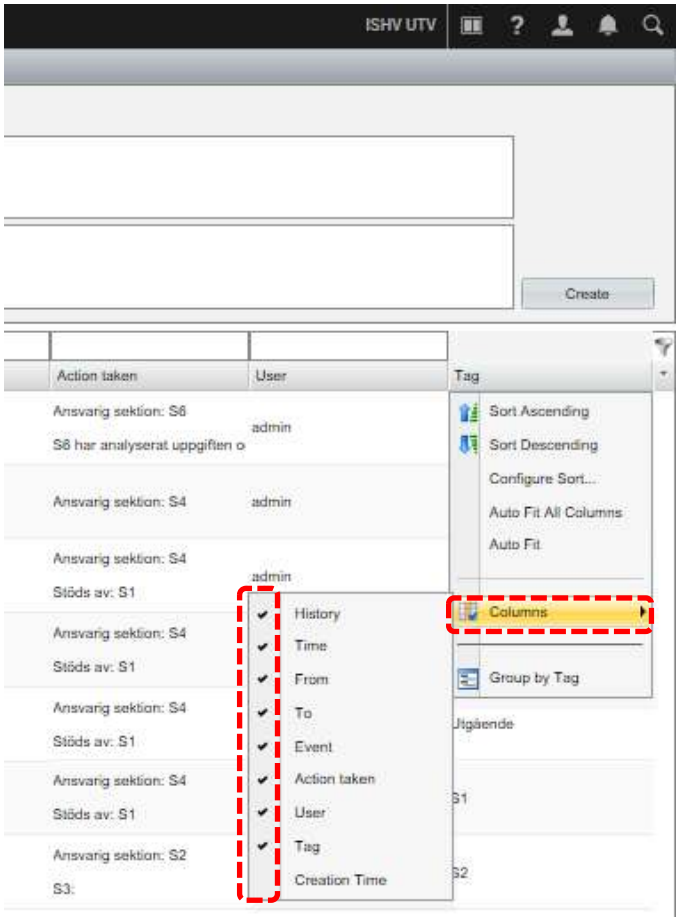

Figur 97 Lägga till och ta bort kolumner i verksamhetsjournalen.

10.7 Archive

Archive är en arkiveringsfunktion. Vid arkivering flyttas all information från verksamhetsjournalen till en fil som inte kan återläsas. Arkivering görs av teknikern när övningen är avslutad. Arkivfilen kan läsas i webbläsaren.

OBSERVERA!
Om man trycker *Archive* så arkiverar man journalen permanent vilket resulterar i att den aktuella journalen töms. Åtgärden kan inte ångras!

11 Underhållsläget (Holdings)

11.1 Allmänt

Holdings används i SitaWare HQ som förteckning över bataljonens tillgångar. I *Holdings* redovisas

- förbrukningsartiklar (*Consumable*) exempelvis ammunition eller bränsle,
- personal (*Personnel*) exempelvis personalkategorier eller befattningsvis, och
- materiel (*Equipment*) som fordon eller vapen, antal eller mängd.

Funktionen är lättöverskådlig och är till för att kunna ha ett ensat och aktuellt underhållsläge inom bataljonen för att dimensionera uppgifter eller användas som stöd vid planering och ledning av underhåll och försörjning.

Ansvaret för uppföljningen kan göras av både stridsledning-, logistik och personalsektion beroende på ansvarsfördelning inom staben.

11.2 Holdings kopplade till ORBAT

Normalförfarandet är att den centralt utskickade ORBAT har personal- och underhållsresurser kopplade till respektive förband, omfattande resurstyp och antal i grundtilldelning (RU). Denna grundtilldelning kallas för *Nominal Holdings* i SitaWare HQ.

Innan man börjar använda *Holdings* bör man via *ORBAT Editor* kontrollera, samt vid behov komplettera, tilldelningen av förbandets personal- och underhållsresurser. Detta görs enligt följande:

1. Öppna applikationen *ORBAT Editor*
2. Välj *Open ORBAT*
3. Välj aktuell ORBAT
4. Välj aktuellt förband
5. Kontrollera förbandets *Holdings*
6. Vid behov välj *Add Holding Types* och välj därefter vilken personal- och underhållsresurs som ska läggas till. Avsluta med *Select*.
7. Fyll i antalet som förbandet har som grundtilldelning av vald resurstyp.

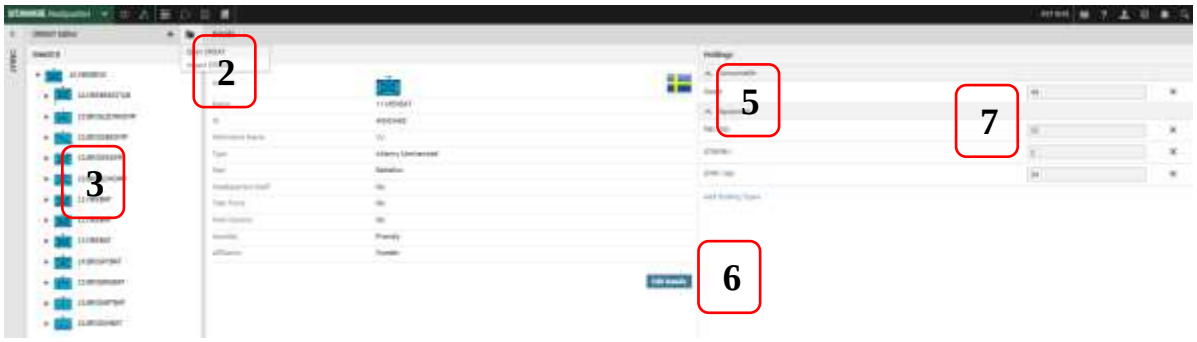

Figur 98 Kontrollera Holdings.

11.3 Inställningar för eget förband och resurser

Innan man börjar använda logistik- och personalresurser i SitaWare HQ behöver man ställa in två saker, vilket förband i hierarkin man tillhör samt vilka resurser man har tillförda. Detta görs enligt följande:

1. Välj *Settings* och välj sedan *Organization Settings.*

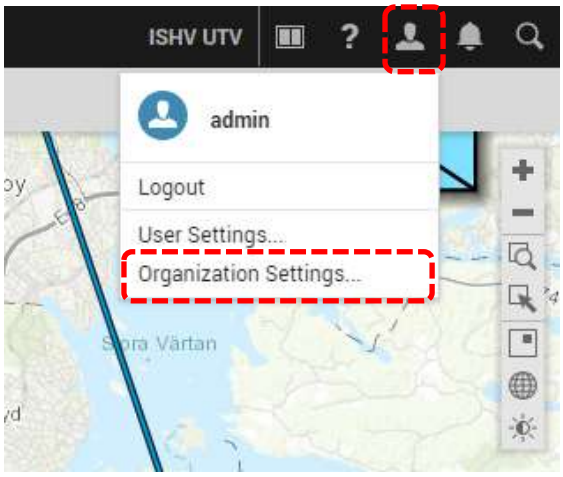

Figur 99 Hitta inställningar för Organization.

2. Välj sedan *Select Unit* och välj rätt enhet. Alternativet *Select ORBAT* visas. Välj den *ORBAT* som är inläst i ISHv för egna förband. Den innehåller din enhet.

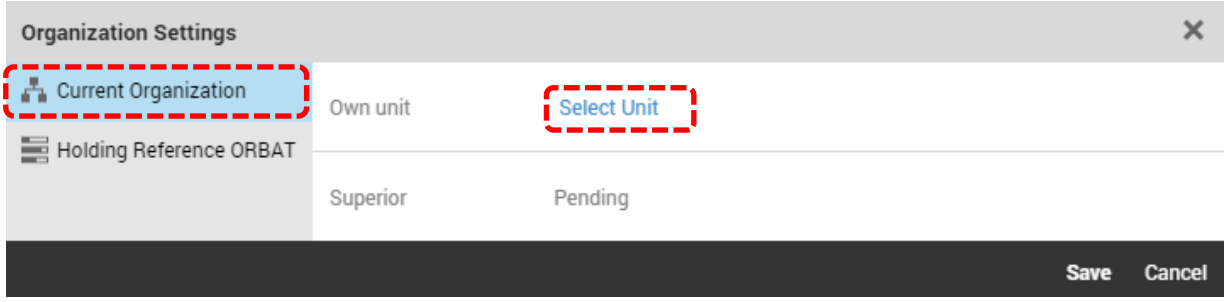

Figur 100 Välj din förbandsstruktur i Current Organization.

3. När förbandet har valts kommer det se ut på följande sett. I det här exemplet visas 27. HVBAT.

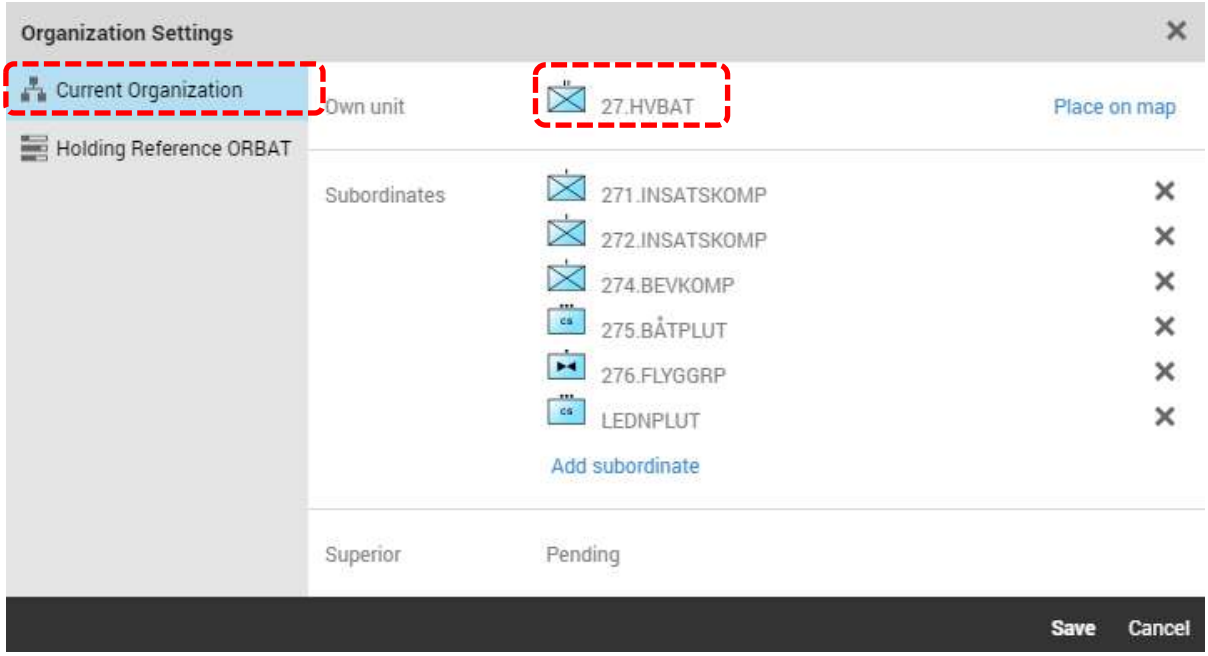

Figur 101 Välj din förbandsstruktur i Current Organization.

4. Ställ in vilka resurser som är tillförda. Alla resurser i Hemvärnet kommer inte att redovisas men en större del av ammunition, vapen och fordonstilldelning finns redovisat i systemet.
5. Tryck på *Holding Reference ORBAT* och därefter *Select ORBAT* för att tilldela resurser. Man får upp *Select Orbat* och väljer sedan den tilldelade *ORBAT* som finns i ISHv.



Figur 102 Välj dina tilldelade reurser i Holding reference.

6. Tryck på *Save* efter att ha valt *ORBAT*. Nu har resurser tilldelats och det går att kunna hitta vilken materiel samt vilka förbrukningsvaror och personalresurser som finns enligt den ORBAT som lästs in.



Figur 103 Spara dina inställningar i Organization settings.

11.4 Tilldela resurser till egna förband

När man har valt sitt förband och lagt till sina tillförda resurser är det dags att tilldela resurserna för sina egna förband. Här måste det beslutas om vilka resurser staben vill ha redovisade och har behov av för ett aktuellt underhållsläge då listan över tilldelad materiel är omfattande. Detta görs enligt följande:

1. Öppnar *Holdings* och välj *Holdings Template*. Detta behöver man göra för att tilldela sina egna förband resurser som man vill redovisa i underhållsläget.
2. Tryck på *Add/Remove Items*.

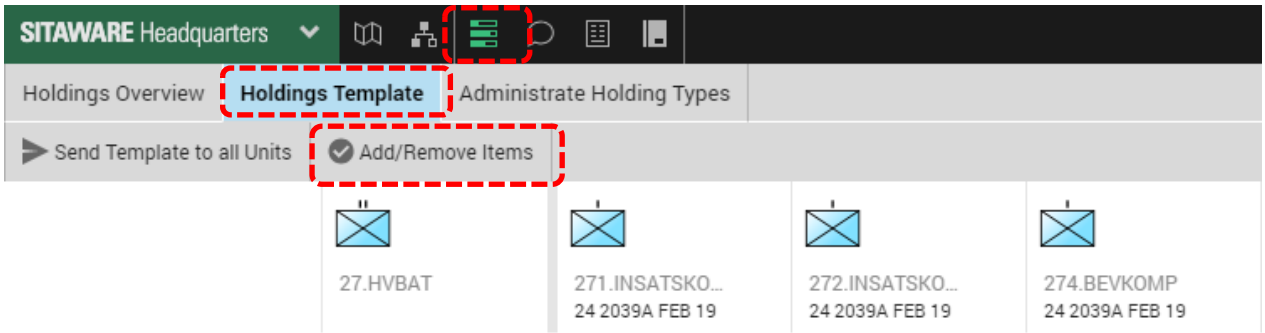

Figur 104 Tilldela egna förband sina resurser i Holdings Template.

3. Välj den/de förbrukningsvaror, materiel och personal som ska redovisas i underhållsläget. I det här exemplet har vi valt 7,62MM AK 4B-T. Det går att söka efter artiklar i *Search holdings*. Tryck sedan *Apply*.

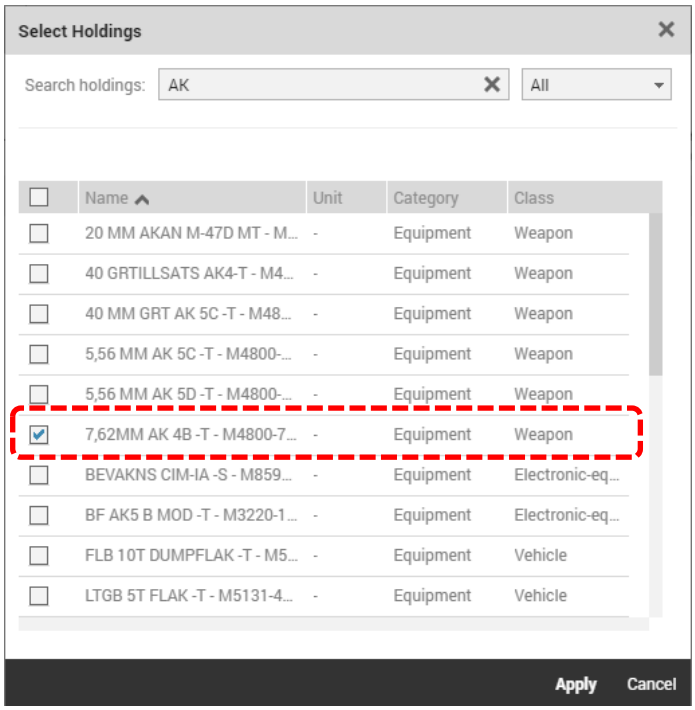

Figur 105 Tilldela resurser till egna förband.

4. Nu är resurser tillagda för det egna förbandet. För att göra så att de blir synliga i *Holdings Overview* (som används för att uppdatera det aktuella underhållsläget) så måste man aktivera resurserna för varje förband och skicka en mall till förbanden i hierarkin. Aktivera först resurserna för dina förband och sedan välj *Send Template to all Units*.

Siffrorna som visas är grundtilldelningen av det aktuella materiel-, förbruknings- eller personalslaget.

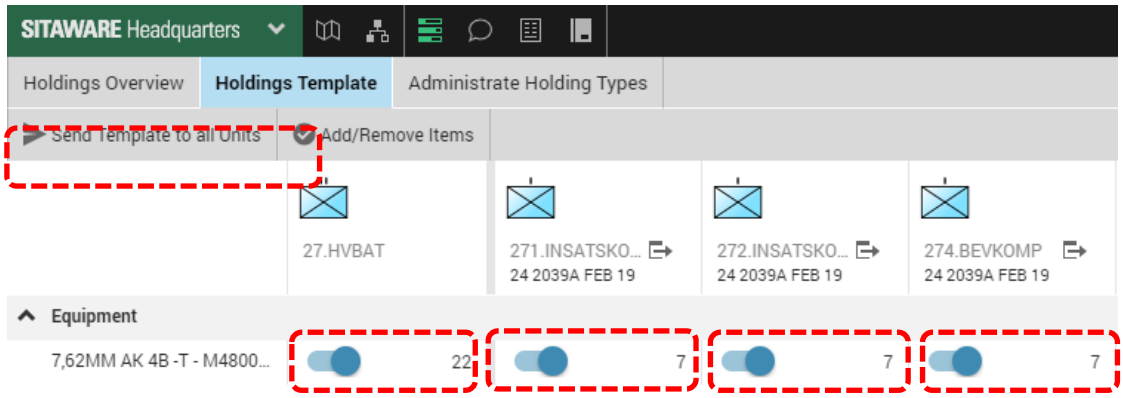

Figur 106 Aktivera tilldelad resurs för dina förband.

De resurser vars ”strömbrytare” är påslagna kommer att visas i kartan.

11.5 Underhållsläget inom bataljonen

Holding Overview är ett övergripande och lättöverskådligt verktyg, beroende på hur mycket resurser som redovisas. Verktyget används för att skapa en översikt över bataljonens underhållsläge.

Först när alla inställningar enligt ovan har ställts in och förbanden har tilldelats sina resurser kan underhållsläget inom bataljonen uppdateras. Detta görs enligt följande:

5. Välj *Holding Overview*. De materiel-, förbrukning- och personalslag som man har valt ska redovisas syns här. Siffran enligt RU visas. Nu kan underhållsläget inom bataljonen uppdateras.

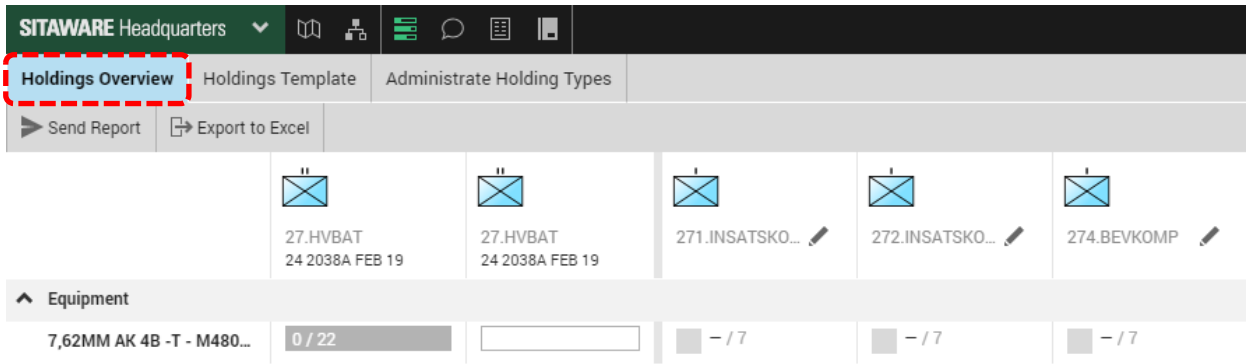

Figur 107 Holding Overviews efter att ha tilldelat sina resurser.

6. Tryck på figuren *Edit manually* som liknar en penna och hittas till vänster om förbandets namn. Fyll därefter i det aktuella underhållsläget för varje materiel-, förbruknings- och personalslag inom bataljonen.

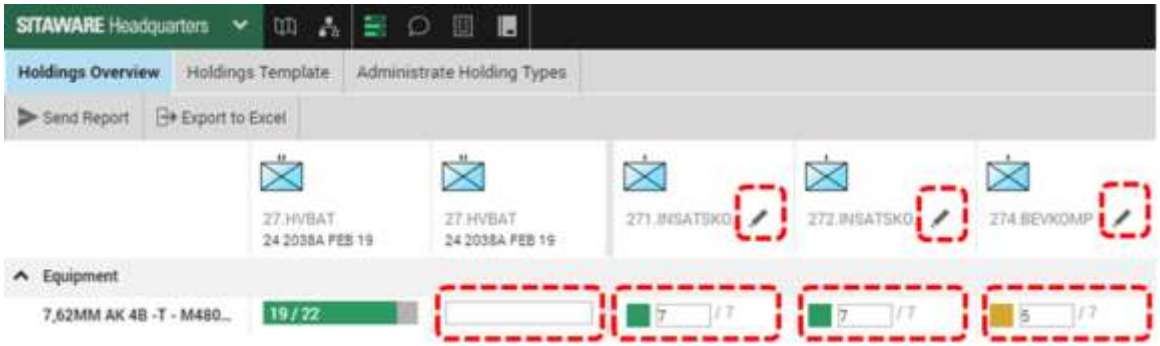

Figur 108 Uppdatera underhållsläget i Holdings Overview.

7. När man har uppdaterat läget kommer statusen att beskrivas i antal enligt RU i två former: Dels genom ”Antal / RU” och dels via RÖD-GUL-GRÖN. Beskrivning av betydelsen av färgerna finns nedan i kapitel 11.6 Status i relation till mängd.

   Man har nu ett överskådligt underhållsläge inom bataljonen. Detta uppdateras enklast genom att förändra antalet för ett visst materielslag vid varje enskilt förband enligt de rapporter som inkommer från DUC.

8. Tryck alltid *Send Report* efter att ha uppdaterat underhållsläget. Detta måste göras för varje enhet/förband (exempelvis 14 Hv Bat, 141 Insats komp, och så vidare) för att det ska uppdateras i kartvyn.

9. Byt organisation till respektive kompani och fristående enheter enligt 11.3 Inställningar för eget förband och resurser och *Send Report* enligt ovan.

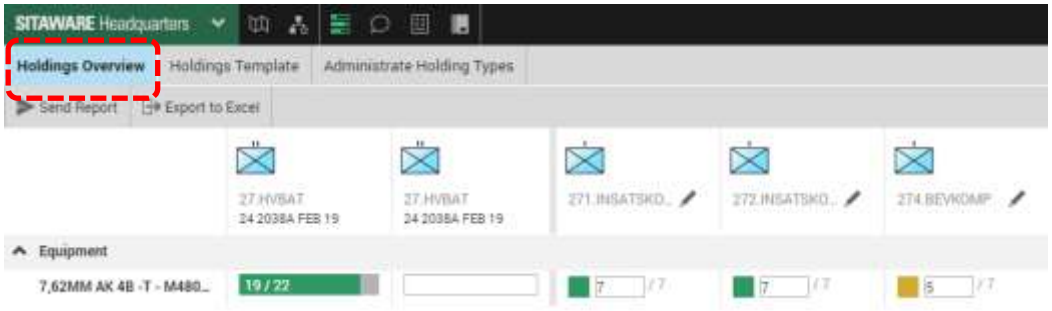

Figur 109 Underhållsläget i Holdings Overview.

11.6 Status i relation till mängd

Status	Färg	Innebörd
Grönt (Green)		100 % till 75 % av grundtilldelning eller RU
Gult (Yellow)		74 % till 50 % av grundtilldelning eller RU
Rött (Red)		49 % till 0 % av grundtilldelning eller RU

Tabell 4 Färgkoderna i relation till mängd.

11.7 Förenklat underhållsläge på lägeskartan

För att se det aktuella underhållsläget på ett förband, högerklicka på kartsymbolen på lägeskartan och välj *View holdings*.

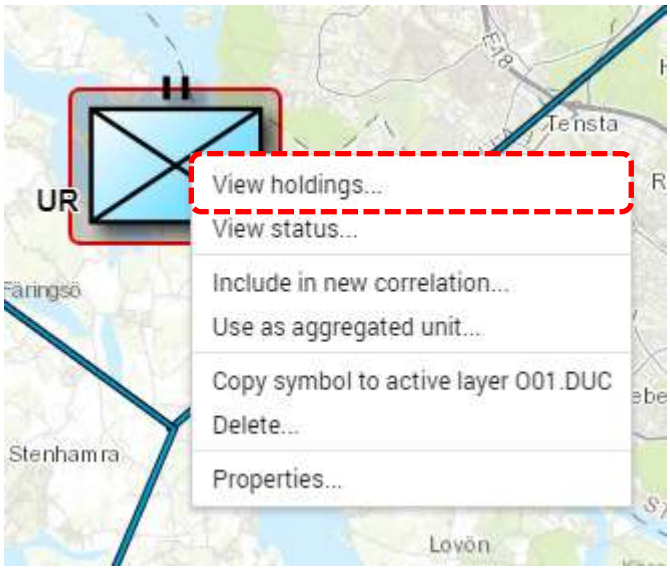

Figur 110 Underhållsläge på lägeskartan.

Förbandets underhållsläge avseende de valda resurserna visas nu.

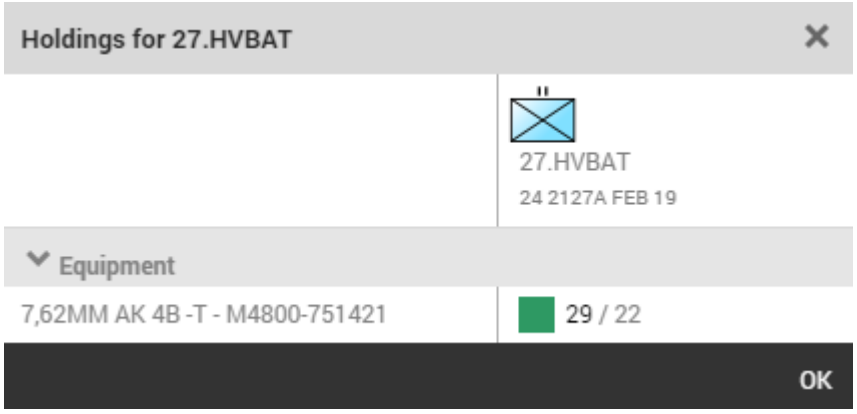

Figur 111 Underhållsläge på lägeskartan.

11.8 Exportera underhållsläget till Excel

Underhållsläget under fliken *Holdings Overview* kan exporteras till Excel. Genom att välja *Export to Excel* kan en fil erhållas som sedan kan distribueras till andra som inte har tillgång till SitaWare HQ. Underlaget kan användas som rapport till högre chef eller som underlag för kompanierna att rapportera in förändringar.

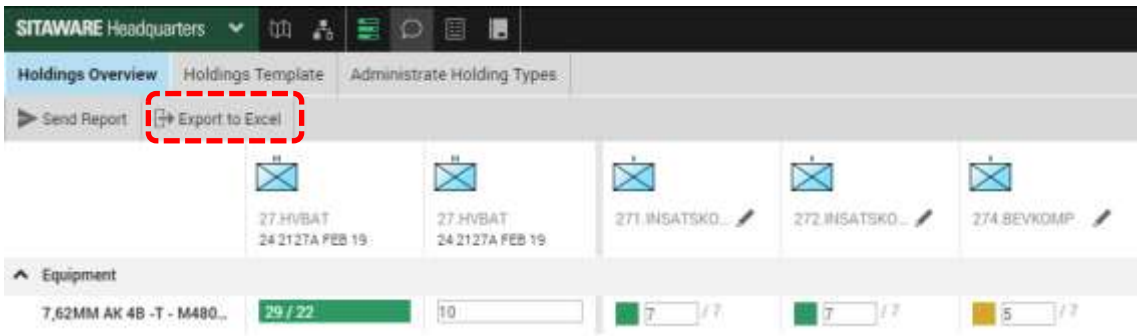

Figur 112 Exportera underhållsläget till Excel.

I Excelarket kan man välja att byta ut informationen i *Holding name*. Detta för att göra det mer lättöverskådligt för mottagaren. *aggr. act* kan bytas ut mot *Totalt*, *Act* kan bytas mot ”Aktuellt antal” och *Nom* kan bytas ut *RU*.

	A	B	C	D	E	F	G	H	I	J
1		27.HVBAT	27.HVBAT		271.INSATSKOMP		272.INSATSKOMP		274.BEVKOMP	
2	Holding name	aggr. act	act	nom	act	nom	act	nom	act	nom
3	**Equipment**									
4	7,62MM AK 4B -T - M4800-751421	29	10	22	7	7	7	7	5	7

Figur 113 Exempel på när underhållsläget har exporterats till Excel.

11.9 Flödesschema Holdings

Följande steg behöver göras när man börjar använda Holdings:

1. Skapa nya resurstyper i *Holdings/Administrate Holding Types*. Klicka på *Add* och skapa nya resurstyper.

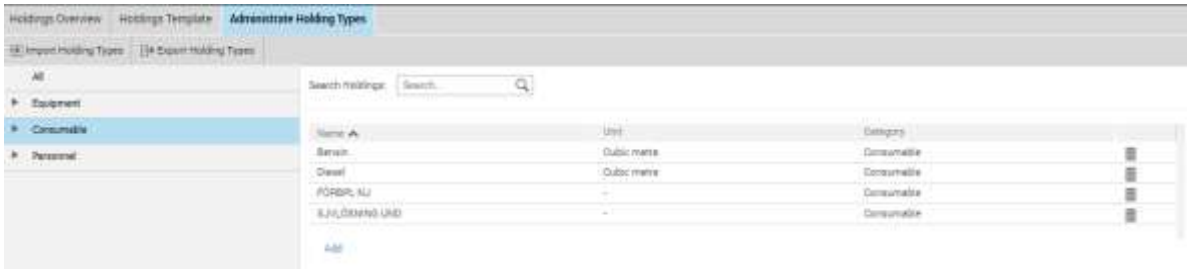

Figur 114 Administrate Holding Types.

2. Kontrollera att ORBAT innehåller rätt resurser och rätt antal i *ORBAT Editor*.

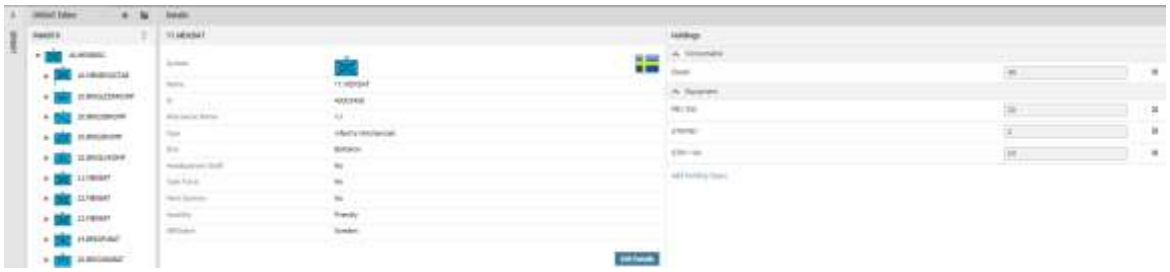

Figur 115 ORBAT Editor.

3. Skapa en rapportmall i *Holdings/ Holdings Templates*. Markera de resurstyper som ska följas upp för respektive förband (grå markering görs blå).

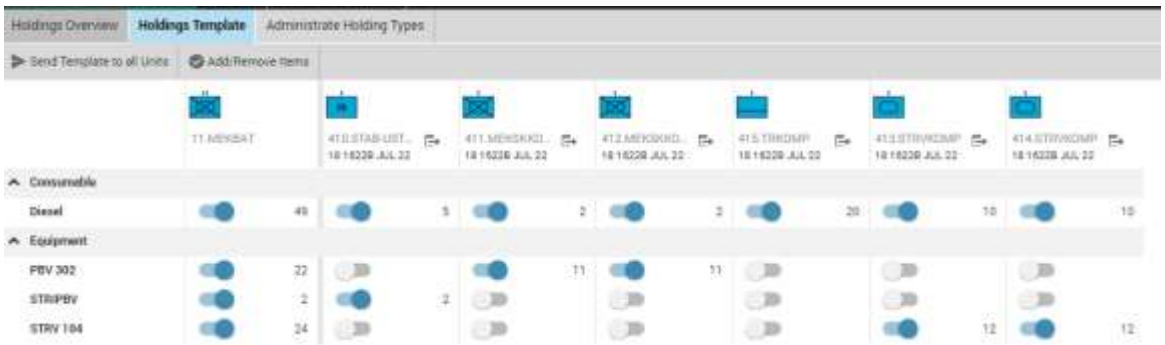

Figur 116 Holding Templates.

4. Skicka mallen till förbanden via *Send Template to all Units.* Detta måste göras även om man inte har någon kommunikation till andra förband.

5. Fyll aktuellt läge i *Holdings Overview*. Klicka på ”pennan” vid förbandet och fyll i.

Figur 117 Holding Overview.

6. Exportera vid behov läget till Excel.

12 Stridsvärdesrapport (Unit Status)

12.1 Allmänt

I *Holdings* följer man upp de resurser som förbandet ska ha som RU samt aktuellt läge.

Via *Unit Status* följer man upp förbandets stridsvärde baserat på förbandschefens värdering samt med en rapport av drivmedels- och ammunitionsläget. I Unit *Status* finns ingen beräkningsautomatik utan funktionen är i första hand ett verktyg för att bedöma och värdera aktuellt stridsvärde.

Det finns ingen systemkoppling mellan *Holdings* och *Unit Status*.

För att se och ange förbandets stridsvärde, högerklicka på aktuellt förband och välj *View Status.*

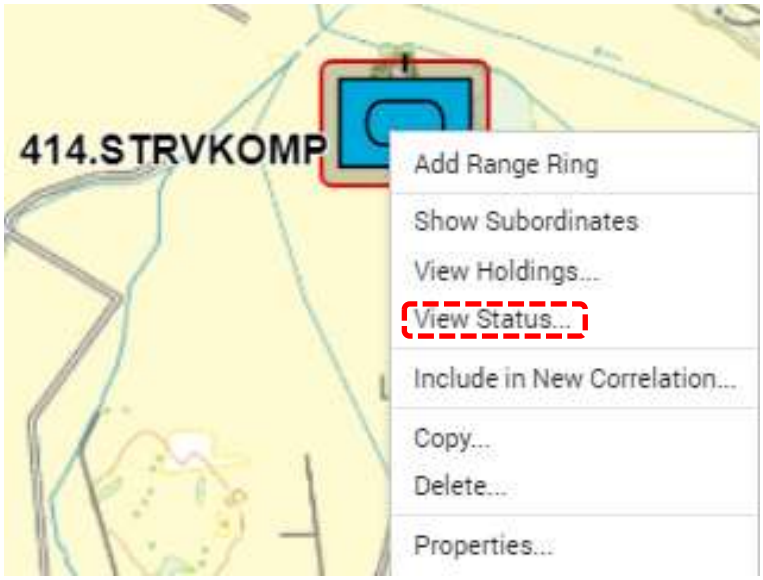

Figur 118 Visa aktuellt stridsvärde.

12.2 Statusområden

De fält som fylls i är följande:

Status	Innebörd
Unit Status	Förbandets sammanfattande stridsvärde
Shoot	Förbandets förmåga att avge eld. Omfattar bl.a. statusen på tilldelade vapen samt personalens förmåga att hantera vapnen.
Move	Förbandets förmåga att förflytta sig med egna resurser. Omfattar bl.a. statusen på tilldelade fordon samt personalens förmåga att hantera fordonen.
Communicate	Förbandets förmåga att kommunicera inom förbandet och med andra förband. Omfattar bl.a. statusen på tilldelad sambands- och informationssystemsutrustning samt personalens förmåga att hantera dessa system.
Sustain	Förbandets förmåga till uthållighet.
Force Protection	Förbandets förmåga att skydda egen stabsplats/grupperingsplats.
Personnel Status	Personalens övergripande status utifrån sjuka, skadade, kompetens, rätt utbildade, etc.
POL	Tillgång på drivmedel, oljor, smörjmedel, etc.
AM	Tillgång på ammunition av olika typer.
Personnel	Antal personer vid förbandet just nu.

Tabell 5 Ifyllande av stridsvärdesrapport.

Där färger används innebär de följande:

- Grönt: inga avgörande begränsningar. Full handlingsfrihet, kan lösa huvuduppgifter och andra uppgifter.
- Gult: vissa begränsningar. Begränsad handlingsfrihet, kan med begränsad ambitionsnivå lösa huvuduppgifter och andra uppgifter.
- Rött: avgörande begränsningar. Stor påverkan på handlingsfriheten att lösa huvuduppgifter och andra uppgifter.
- Svart: förbandet kan inte nyttjas. Behov av återhämtning/reorganisation.

13 Planer och orderverk

13.1 Allmänt

Plans & Orders används av staben för att skapa planer och orderverk för förbandet. Dessutom används funktionen för att skapa lägessammanfattningar som ska delges till kompanierna. Hur detta ska gå till finns reglerat i H ISHv Stabstjänst 2025.

Dispositionsmässigt är *Plans & Orders* är upplagt så att man hämtar en befintlig order- eller planeringsmall och sedan fyller på med information såsom till exempel order och *Layers*.

I kommande text används ordet **order** för såväl plan, order eller lägessammanfattning.

13.2 Skapa en order utifrån en befintlig mall

Att skapa en ny order görs enligt följande:

1. Välj *Plans & Orders*-fliken till vänster.

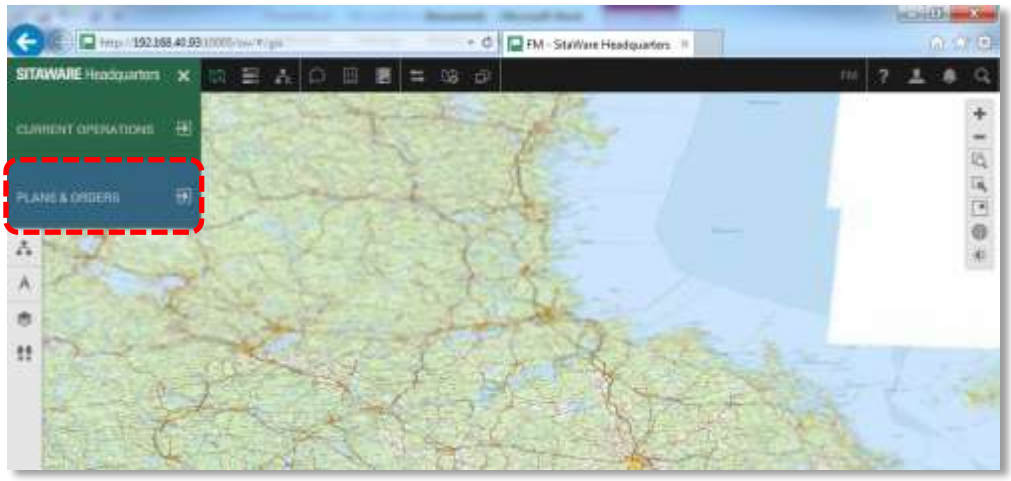

Figur 119 Skifta till Plans & Orders.

2. För att skapa en ny order väljs vanligtvis *Create From Existing Plan*.

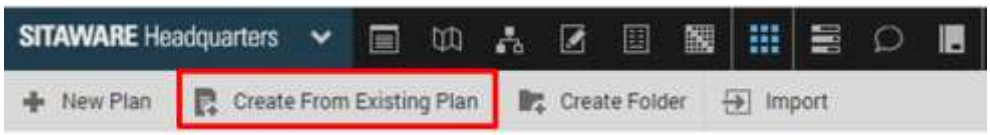

Figur 120 Ny order skapas från mall.

3. Nästa steg är att gå till den *Folder* där mallar finns.

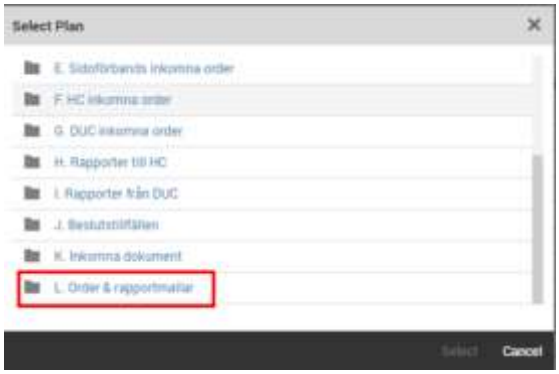

Figur 121 Folder för mallar.

4. Välj sedan den mall som ska användas. Ifall ordern ska skrivas ut rekommenderas mallen *5 punktsorder med interna mallar*, då denna endast blir ett dokument.

Figur 122 Val av ny order med interna bilagor.

5. Klicka på *Select* för att öppna formuläret med egenskaper för ordern.

6. Efter att mallen öppnats upp, fyll i orderns namn och nödvändig information. Glöm inte att ange informationssäkerhetsklass med prefix och postfix. Informationen ska fyllas i enligt tabellen nedan.

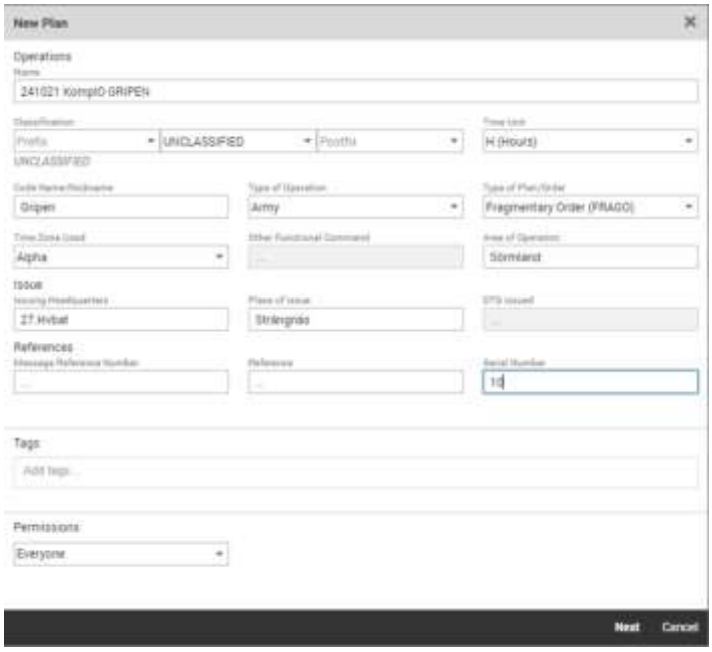

Figur 123 Egenskaper för en ny order.

Följande fält fylls i. Övriga lämnas tomma.

Fält	Beskrivning
Operation name	Orderns namn, till exempel ”BATO GRIPEN”.
Classification	Informationssäkerhetsklass, till exempel ES.
Code/nick name	Operationens särskilda namn, till exempel ”GRIPEN”
Type of operation	Typ av operation, till exempel ARMY.
Type of plan/order	Välj vilken orderform det är, till exempel FRAGO.
Timezone used	Ange A för vintertid och B för sommartid.
Area of operation	Operationsområde, till exempel SÖRMLAND.
Issue	Ert förband, till exempel 27. HEMVÄRNSBATALJON
Place of issue	Stabens grupperingsplats, till exempel STRÄNGNÄS.
Serial number	Löpnummer för orderverket, till exempel 10.
Reference	Referens, till exempel högre chefs order.

Tabell 6 Fält som fylls i när en order skapas i Plans & Orders.

Informationen kommer att sparas som metadata och kommer att kunna återfinnas i biblioteket i *Plans & Orders* i SitaWare HQ.

7. Klicka därefter *Next* och ange sedan vart i SitaWare HQ den nya ordern ska sparas.

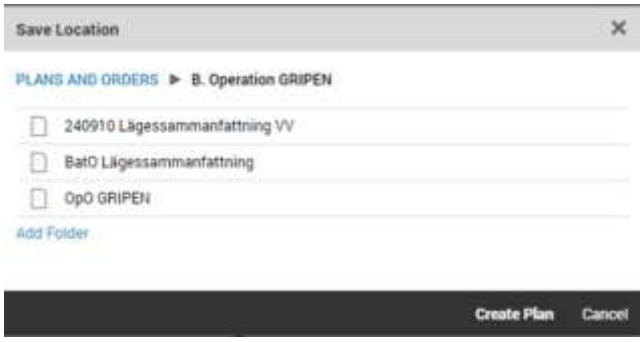

Figur 124 Spara ny plan/order

8. Klicka *Create Plan*. Ordern har nu sparats och den tomma ordern öppnas.
   Den ska nu fyllas med text, *Layers*, filer och dylikt.

Figur 125 Ny order med textdokument Huvuddokument.

9. Öppna dokumentet *Huvuddokument* genom att klicka på dokumentnamnet. Nu kan man och andra stabsmedlemmar editera dokumentet. I stort fungerar det som en vanlig dokumenthanterare, likt exempelvis Word. En begränsning är att man inte kan använda tabeller, vilket kan innebära att ordern behöver kompletteras med ett Excel-dokument.

Figur 126 Öppnat Huvuddokument.

På vänster sida finns genvägar till rubrikerna i ordern och i mittenfönstret sker all editering. Dokumentet sparas automatiskt. När ordern är färdigt kan den sparas som PDF eller exporteras som SitaWare HQ-plan. Det går även att skriva ut dokumentet.

OBSERVERA!
Flera stabsmedlemmar kan skriva samtidigt i ordern. Härvid ser man vem som skriver var genom att inloggningsnamnet syns vid texten.

13.3 Lägga till *Layers*

Layers används för geografisk information kopplad till ordern. Detta görs enligt följande:

1. Klicka på *Add* uppe till vänster och välj *Layer*.

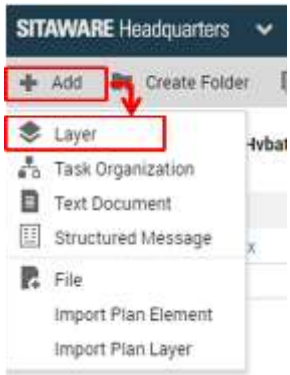

Figur 127 Lägga till Layers till en order.

2. Namnge och informationsklassificera skapat *Layer*. Spara genom att klicka *Save*.
3. *Layer* är nu sparat i ordern. Öppna skapat *Layer* genom att klicka på namnet.
4. Kartläget i SitaWare HQ öppnas nu. Om inte *Pictures* öppnas, klicka då på applikationen *Pictures* för att öppna.
5. Markera ditt *Layers* genom att bocka i checkrutan uppe till vänster. Aktivera *Layer* genom att dubbelklicka klicka på det eller högerklicka och välja *Set Active Layer*.

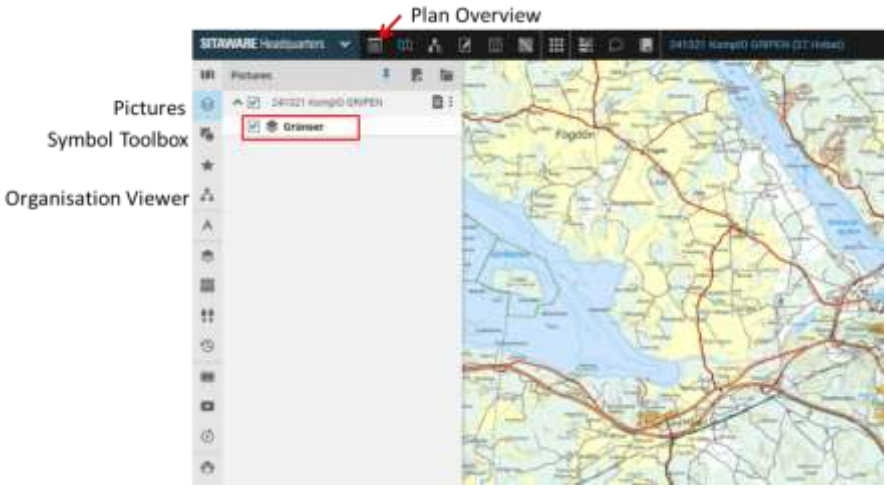

Figur 128 Plan Layers hantering i kartan.

6. Nu kan man editera valt *Layer* med olika funktioner, infoga symboler, frihandsrita, med mera. Använd *Symbol Toolbox* eller *Organisation Viewer*. *Layer* sparas automatiskt efterhand som information tillförs.
7. Klicka på *Plan Overview* för att återgå till *Plans & Orders.*

13.4 Filer kopplade till en order

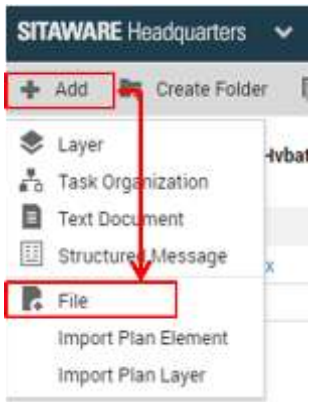

Figur 129 Lägga till filer till en order.

Om man har bilagor, exempelvis en förteckning över frekvenser eller personaltablå i Excel, kan filerna importeras som bilagor under *Add* och sedan *File.*

OBSERVERA!
Tillåtna format enligt SitaWare HQ usermanual är .docx, .xlsx, .pptx, .pdf, .jpg, .png och .zip. När filen är inlagd i ordern är den skrivskyddad. Vill man göra ändringar i filen måste man ta bort den från ordern, ändra filen och därefter lägga till den på nytt.

13.5 Statushantering

Allteftersom delar av ordern har färdigställs kan dess status ändras från *Draft* (utkast) till *Complete* (färdig) eller *Approved* (godkänt).

I huvuddokumentet kan status för respektive orderpunkt ändras så att orderredaktören och SC kan följa orderarbetet. Detta görs genom att högerklicka på en orderpunkt och därefter välja status.

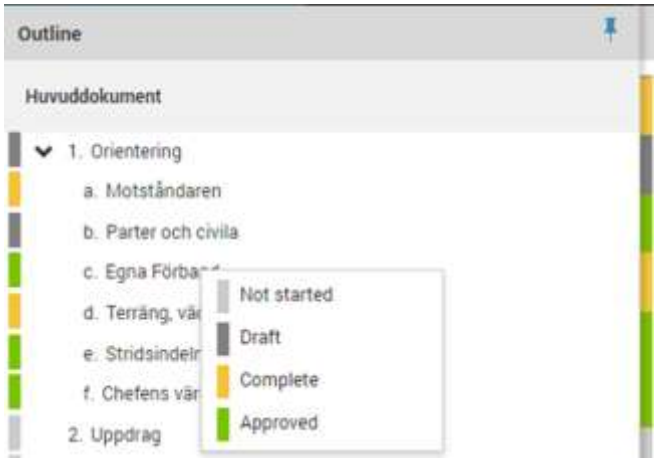

Figur 130. Status översikt för orderpunkter.

Även för ingående orderdelar, såsom *Layers* och dokument kan statusen ändras. Detta görs också genom högerklick följt av val av status.

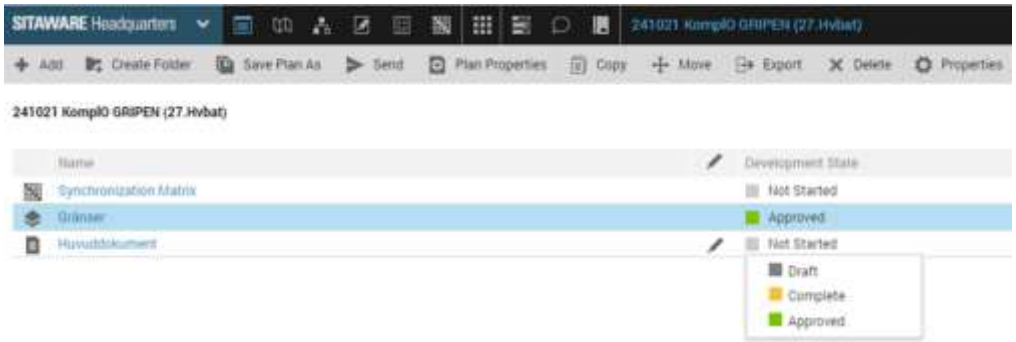

Figur 131 Statusändring för ingående orderdelar.

När orderredaktören eller SC bedömer att det är lämpligt kan hela planens status ändras. Det görs uppe till höger i fönstret enligt följande:

1. Det första statussteget är när hela ordern är färdig är att den låses för genomläsning via *Approval in progress.* Ordern är nu låst för editering under tiden som genomläsning sker.

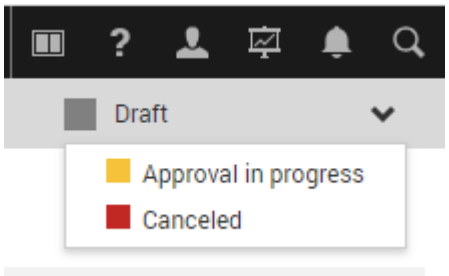

Figur 132 Val av status inför genomläsning och godkännande.

2. Behöver ändringar göras ändras statusen tillbaka till *Draft*. Annars ändras status till *Approved.*

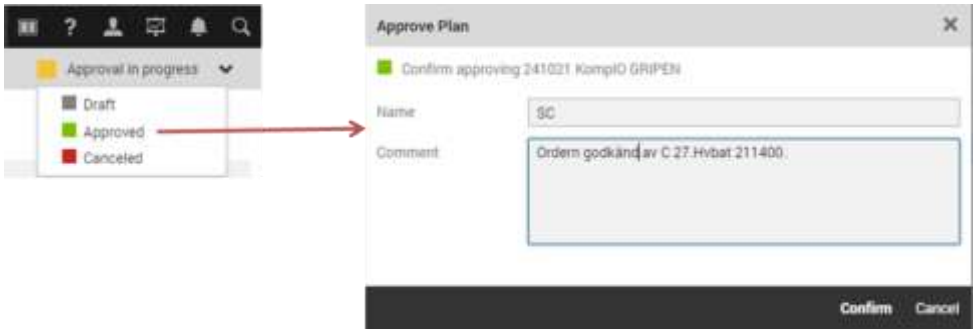

Figur 133 Val av status när ordern är godkänd.

3. Då man väljer *Approved* öppnas ett nytt fönster där ansvarig person och eventuella kommentarer anges.
4. Nästa steg är när ordern ska verkställas och bli gällande. Detta görs normalt efter att man genomfört ordergivning, eller i det fall att det är en lägessammanfattning som ska delges kompanierna, omedelbart innan utskick.

   Status ändras till *Issued*. Även öppnas ett nytt fönster där man antecknar vem som är ansvarig och eventuella kommentarer.

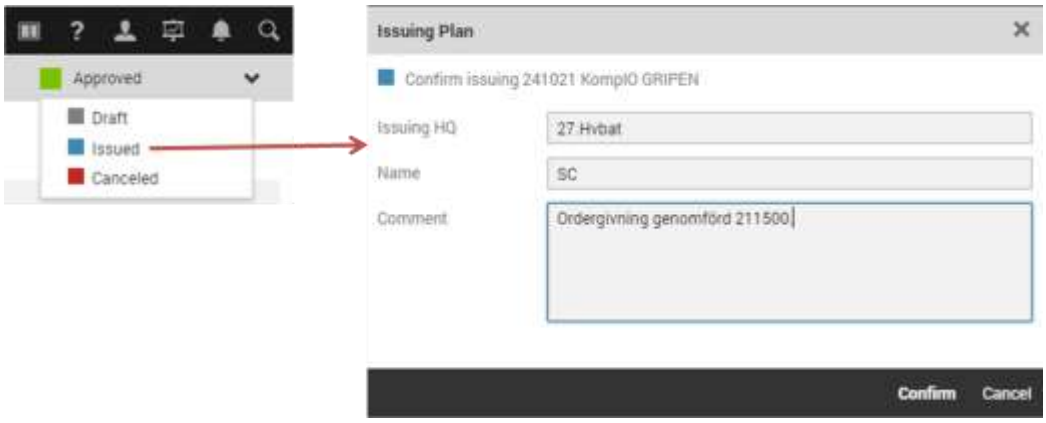

Figur 134 Status när ordern ska verkställas och bli gällande.

5. När ordern har fått status *Issued* kan den inte längre låsas upp och återgå till *Draft*. Statusen kan ändras till *Canceled*, vilket innebär att ordern är upphävd och inte längre gällande.

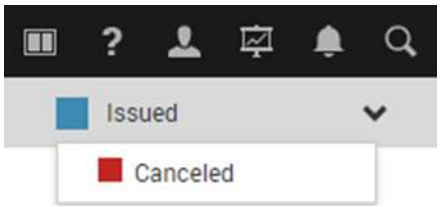

Figur 135 Val av status Cancelled för en order med status Issued.

TIPS!
Det är möjligt att skapa en ny order utifrån en tidigare order oavsett status. Detta görs genom att välja *Create From Existing Plan* och istället för att välja en mall välja en tidigare order. På så sätt kan man återanvända HC order eller egna tidigare skapade order.

13.6 Exportera order

Order kan exporteras, vilket kan vara lämplig metod för delgivning eller orderuttag.

För både order och lägessammanfattningar görs detta enligt följande:

1. Gå till den *Folder* där ordern som ska exporteras finns.
2. Klicka på textikonen på ordern och därefter på *Export* uppe i menyraden, alternativt högerklicka på ordern och välja *Export*.

Figur 136 Export av en order alternativ 1.

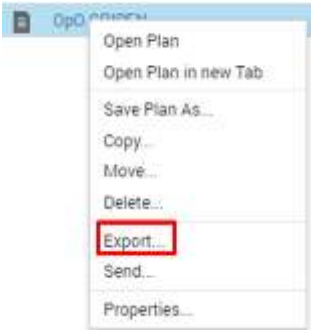

Figur 137 Export av en order alternativ 2.

3. Ordern är nu exporterad och återfinns via Utforskaren under *Hämtade filer*. Ordern kan nu skickas via fildelning eller sparas ner på ett godkänt USB-minne för fortsatt leverans.

13.7 Importera order

Att importera en order eller lägesrapporter från kompanierna görs enligt följande:

1. Välj först till vilken *Folder* man vill importera ordern eller lägesrapporten till.
2. Klicka sedan *Import* i övre vänster hörn.

Figur 138 Import av order.

3. Ordern eller lägesrapporten kommer att vara skrivskyddad. Klicka på *Import* i dialogrutan.

Figur 139 Dialogruta vid Import.

Ordern är nu importerad och återfinns i den *Folder* som var öppen när man gjorde importen. För att flytta den importerade ordern, högerklicka på den och väljer *Move*. Det går nu att välja en annan *Folder* dit ordern ska flyttas.

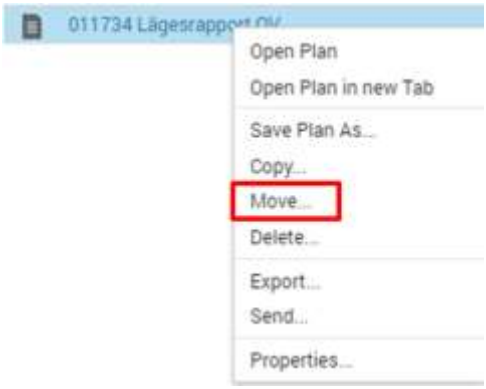

Figur 140 Flytta en order till annan Folder.

13.8 Hantera lägesrapporter från kompani

Lägesrapporten från kompanierna inkommer till bataljonsstaben dagligen enligt SO. Lägesrapporten inkommer normalt som en fil via fildelning alternativt på ett USB-minne via ordonnans.

Bataljonen importerar lägesrapportfilerna till Plans & Orders enligt följande:

1. Hämta filen från fildelning eller importera filen från USB-minne till en lämplig lagringsplats i mappstrukturen. Observera att vid import från ett USB-minne från kompaniet kan den ligga i mappen *etc/Plans*.
2. Välj därefter till vilken *Folder* i *Plans & Orders* lägesrapporten ska importeras till.
3. Klicka sedan *Import* i övre vänster hörn.
4. Välj lägesrapportfilen i Utforskaren.

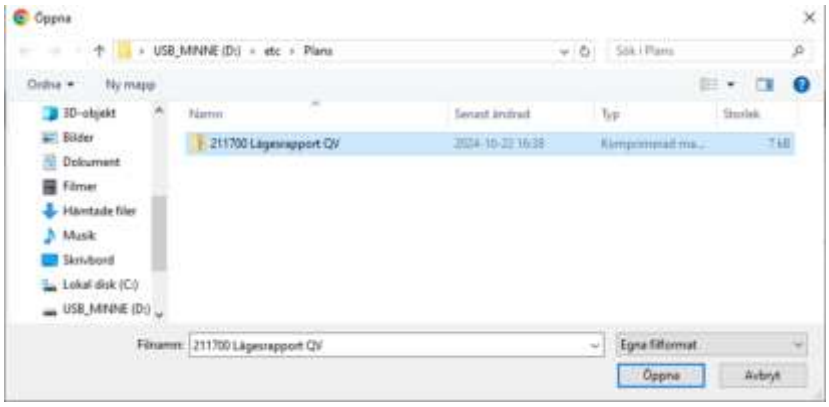

Figur 141 Inkommen lägesrapport i Utforskaren.

5. Välj *Import*. Lägesrapporten importeras skrivskyddad.

Figur 142 Import fönster.

6. Nu är lägesrapporten importerad in i vald *Folder*.

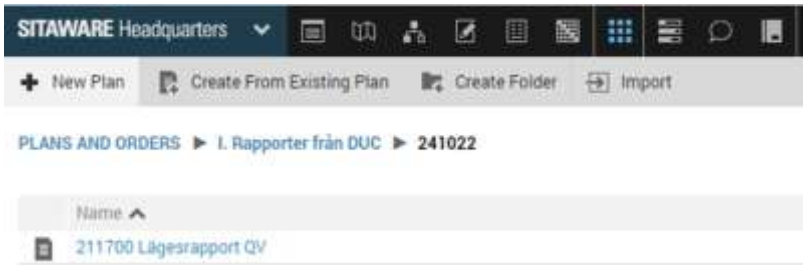

Figur 143 Importerad lägesrapport från Frontline.

7. Klicka på lägesrapporten för att öppna den och visa de *Layers* och det textdokument som ingå i lägesrapporten.

8. När man klickar på ett *Layers* i lägesrapporten öppnas det i kartvyn och man kan ta del av informationen. Härifrån kopieras vald information till bataljonens egna *Current Layers* beskrivet i kapitel **6.6 Kopiera symboler mellan *Layers***.

Figur 144 Öppnat lägesrapport Layer i kartvyn.

9. För att ta del av textinformationen, klicka på *Textdel*. Härvid öppnas ett textfält. Från detta textfält kan man kopiera vald text och klistra in i eget rapportunderlag till HC.

Figur 145 Öppnad textdel till en lägesrapport från kompani.

14 IRIS FORMS

14.1 Allmänt

Applikationen FORMS i SitaWare HQ är ett verktyg som kan hantera formaterade rapporter utifrån NATO standard såsom AdatP-3 och APP-11-I.

FORMS har en egen hjälpfunktion som kan nås genom att trycka på hjälpknappen (?) när man är inne i en FORMS mall.

FORMS stödjer rapportering med mallar utifrån Försvarsmaktens Meddelande Katalog (FMMK).

Denna instruktion hanterar endast den enklaste formen av användning av FORMS, såsom var man hittar FORMS och hur man skapar och editerar dess innehåll, för att sedermera validera innehållet och skicka det till en mottagare.

14.2 Skapa FORMS rapport

En FORMS rapport skapas enligt följande:

1. Gå till Current Operations.
2. Klicka på FORMS applikationsikon.

Figur 146 Startikon för FORMS och hjälpfunktion i FORMS.

3. Nu öppnas en FORMS sida med nedanstående menyer.

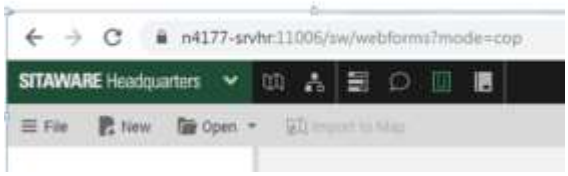

Figur 147 Meny för att skapa ny eller öppna en FORMS rapport.

4. Klicka på *New* och ett fönster med tillgängliga FORMS mallar öppnar sig.

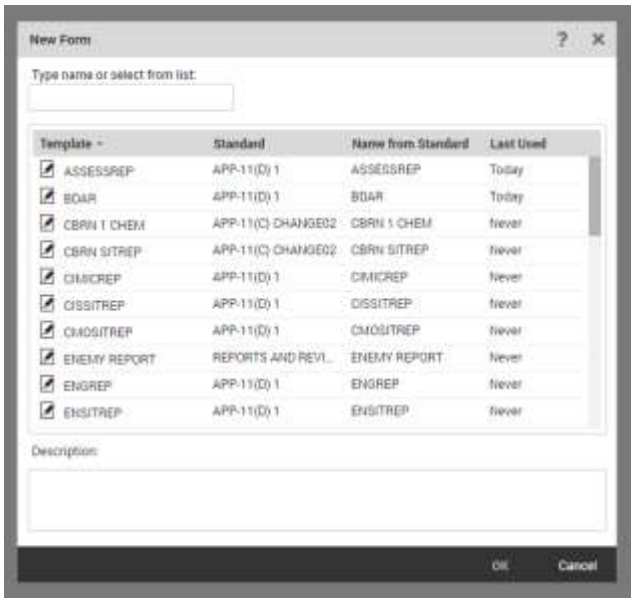

Figur 148 Lista med tillgängliga FORMS rapporter.

5. Sök FORMS-mallar genom att skriva dess namn i den översta rutan, exempelvis UNITREP.

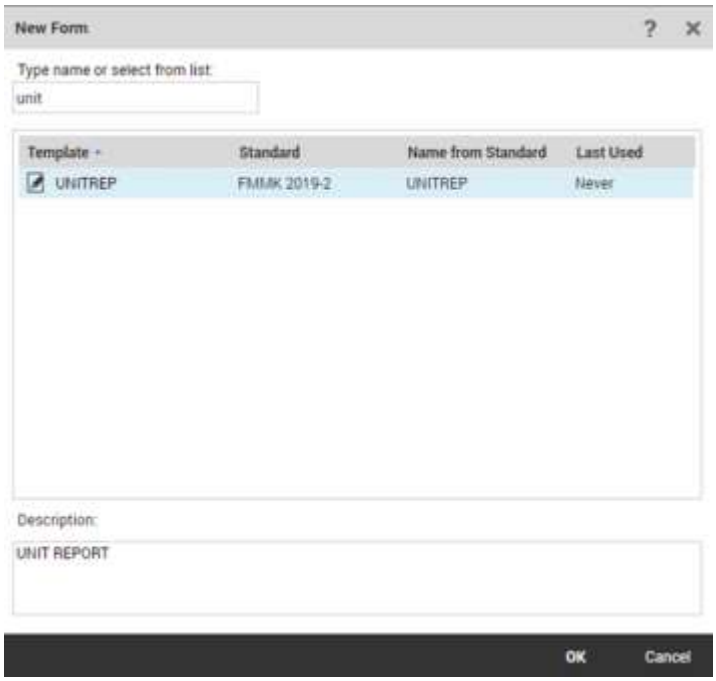

Figur 149 Sökruta för FORMS rapporter.

6. Applikationen söker då upp den FORMS-mall som matchar sökningen. Markera mallen och klicka på *OK*.

Figur 150 Öppnad tom FORMS rapport.

7. Man kommer direkt in i FORMS-mallen och kan börja fylla i information.

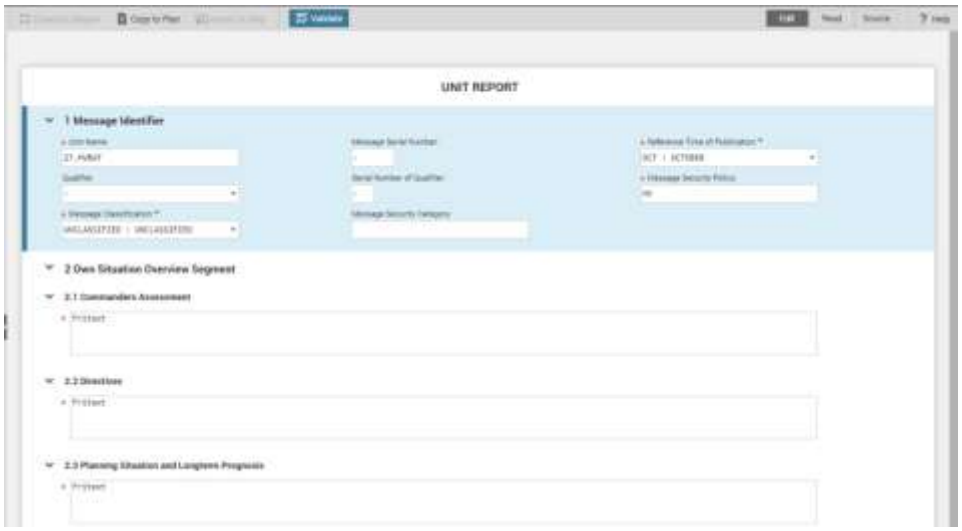

Figur 151 FORMS rapport med tvingande fält.

8. Rutor som har en asterisk * är tvingande och måste fyllas med information. Vid behov, klicka på hjälp (?) för att få information om vilken typ av information som ska fylla i.

OBSERVERA!
Bokstäverna Å, Ä eller Ö kan inte användas i FORMS.

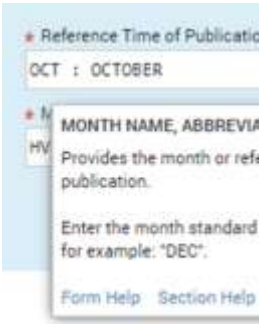

Figur 152 Hjälpfunktion för ett FORMS fält.

9. Fyll i vald FORMS-rapport och skriv med klartext förbandsnamnet för att undvika missförstånd.

10. Många FORMS-mallar har ett stödverktyg för att ange koordinater från en karta. Klicka på ”platsmarkören” för att komma till en kartvy.

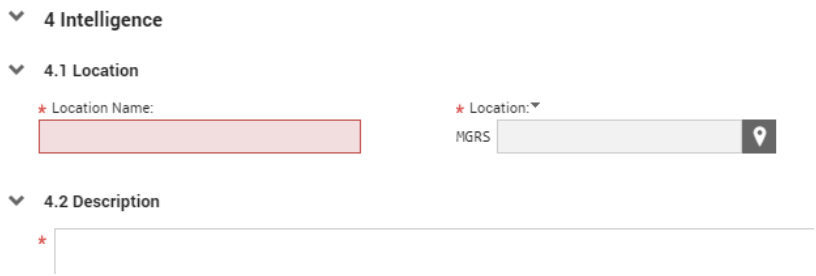

Figur 153 Platsmarkör i FORMS.

11. I kartvyn klickar man på en plats i kartan och platsmarkören markerar vald plats.

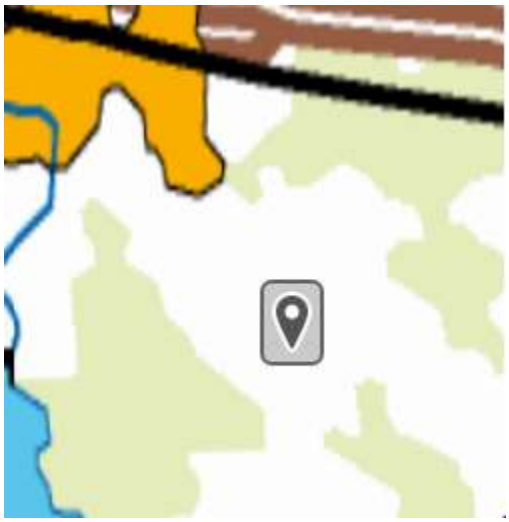

Figur 154 Vald plats i kartvyn.

12. Klicka på *Select* när positionen ser korrekt ut.

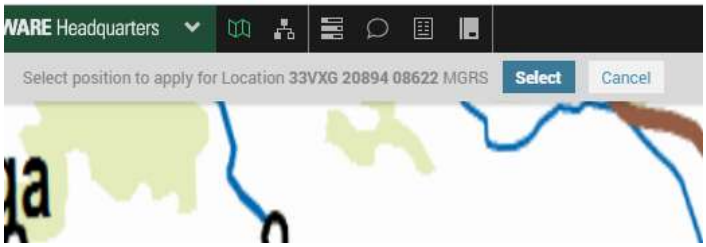

Figur 155 Val av plats i kartvyn.

13. Positionen kommer då med i FORMS-mallen.

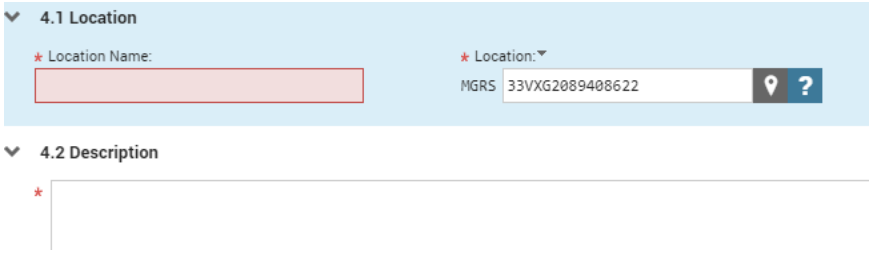

Figur 156 Infogade koordinater i FORMS-rapporten.

14. När hela FORMS-mallen är ifylld, klicka på *Validate* i det övre verktygsfältet.

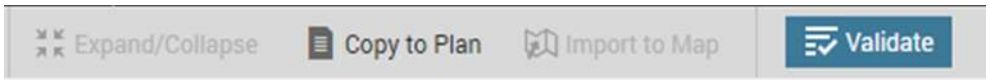

Figur 157 Funktion för att validera en FORMS rapport.

15. FORMS går då igenom dokumentet och kontrollerar att alla de fält som ska fyllas i är ifyllda och har rätt format. När alla parametrar har fyllts i korrekt visas en grön ruta.

Figur 158 Validerad FORMS rapport.

16. Har en ruta som ska vara ifylld missats kommer FORMS att indikera detta när man klickar på *Validate* och visa den första rutan som ska fyllas i korrekt.

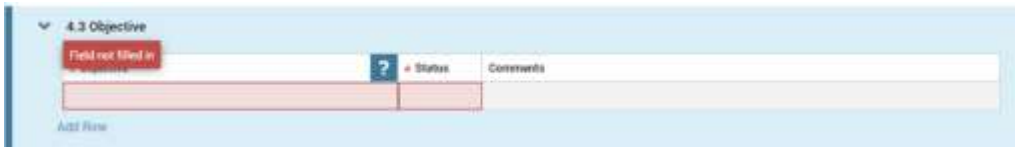

Figur 159 Ej korrekt ifyllt fält.

17. Längst ner i rapporten visas en lista med alla upptäckta fel.

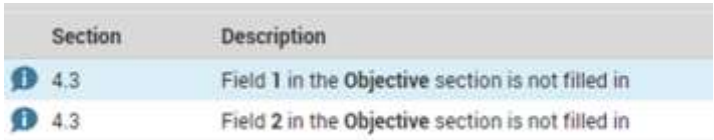

Section	Description
4.3	Field **1** in the **Objective** section is not filled in
4.3	Field **2** in the **Objective** section is not filled in

Figur 160 Lista med upptäckta fel.

18. När detta är genomfört detta kan man kontrollera hur texten ser ut genom att klicka på *Read* knappen i det övre högra verktygsfältet. Nu visas hur rapporten kommer att visas hos mottagaren.

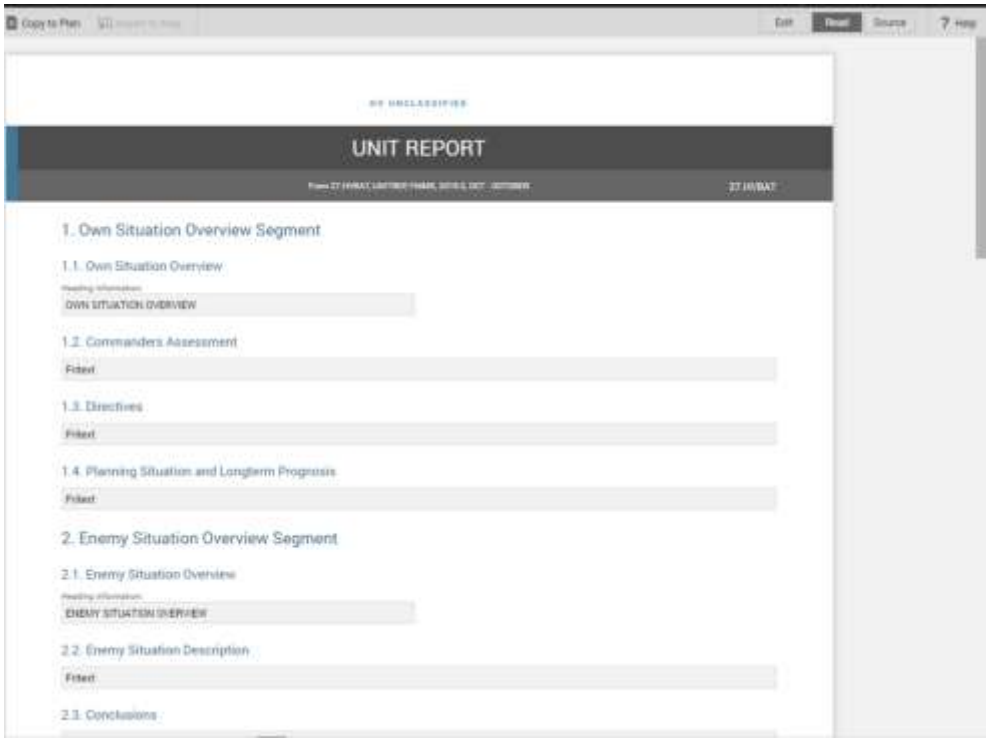

Figur 161 Rapporten i Read.

19. Klicka på Source för att se den information som de facto skickas till mottagaren.

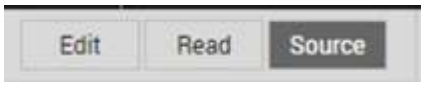

Figur 162 Funktion för att visa data i en FORMS rapport.

20. Med hänsyn till att endast innehållet i rapporten skickas och inte själva formuläret innebär det att FORMS-rapporter lämpar sig bäst när överföringen av rapporten måste ske via radio eller motsvarande.

```
MSGID/UNITREP/FMMK/2019-2/27.HVBAT/-/OCT/-/-/HV/UNCLASSIFIED//
HEADING/OWN SITUATION OVERVIEW//
GENTEXT/COMMANDERS ASSESSMENT/Fritext//
GENTEXT/DIRECTIVES/Fritext//
GENTEXT/PLANNING SITUATION AND LONGTERM PROGNOSIS/Fritext//
HEADING/ENEMY SITUATION OVERVIEW//
GENTEXT/ENEMY SITUATION DESCRIPTION/Fritext//
GENTEXT/CONCLUSIONS/Fritext//
HEADING/OWN CAPABILITIES OVERVIEW//
CAPASS/MOV/GREEN/Fritext//
SUBSTAT/FRITEXT/GREEN//
GENTEXT/CURRENT ACTIVITIES/Fritext//
GENTEXT/PLANNED ACTIVITIES/Fritext//
OBJSTAT/Fritext/GREEN/Fritext//
SUBSTAT/1.HVKOMP/GREEN//
GENTEXT/CURRENT ACTIVITIES/Fritext//
GENTEXT/PLANNED ACTIVITIES/Fritext//
FUNCSTAT/LOG/GREEN/Fritext//
HEADING/CIS//
GENTEXT/CIS SITUATION SUMMARY/Fritext//
CISSTAT/COMM/GREEN/Fritext//
HEADING/CIVILLIAN SITUATION//
STATCOL/GREEN//
GENTEXT/CIVILIAN SITUATION SUMMARY/Fritext//
```

Figur 163 Data i en FORMS rapport.

Många FORMS-mallar är utformade så att man kan välja på hur mycket information man vill delge genom att vissa paragrafer är inaktiverade tills de används. Genom att klicka på en grå paragraf öppnar man upp den och kan fylla i information i paragrafen.

Figur 164 Gråmarkerad paragraf som görs aktiv.

Om paragrafen inte ska användas, högerklicka på den och välj *Delete*.

Efter att FORMS-rapport är klar, spara FORMS-rapporten genom att så klicka på *Save* och välj *Save As Local File*, så hamnar filen i Utforskaren under Hämtade filer.

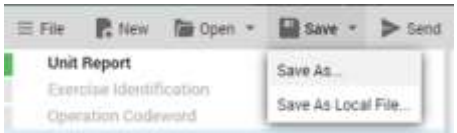

Figur 165 Spara rapport lokalt.



Figur 166 Nedsparad rapport i Hämtade filer.

Härifrån kan den sedan döpas om och flyttas till lämplig plats i mappstrukturen samt skickas med fildelning eller via USB-minne.

14.3 Ta emot FORMS rapport

När en FORMS-rapport inkommit via fildelning eller USB-minne ska den sparas till en lämplig plats i mappstrukturen.

Att öppna en FORMS-rapport i SitaWare HQ görs enligt följande:

1. Öppna FORMS i SitaWare HQ.
2. Klicka på *Open* och därefter på *Open local file*.

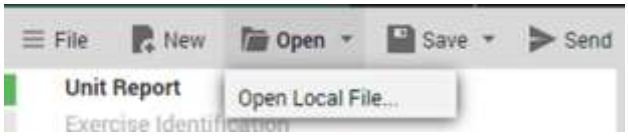

Figur 167 Öppna en lokalt sparad FORMS rapport.

3. Leta reda på aktuell FORMS-rapport i Utforskaren och klicka *Open*.
4. FORMS-rapporten kan öppnas och läsas eller skrivas ut. Ifall det är en egen rapport kan den också editeras enligt tidigare beskrivning.

14.4 FORMS rapport från ett Layer

14.4.1 Skapa rapport från ett Layer

För rapportmallarna OWNSITREP och ENSITREP kan man enkelt skapa rapporter direkt från ett *Layer* för att delge egna förbands läge samt motståndarläge.

Detta görs för OWNSITREP på följande sätt:

1. Gå till *Current Operations*.
2. I *Pictures* gå till det *Layer* där man har egna förband (O01.DUC, O02.DUC/DUC eller O03.Ledningsplatser).
3. Välj vilket *Layer* som ska användas i rapporten.
4. Högerklicka på valt *Layer* och välj *Export to structured message.*

OBSERVERA!
Endast förbandsymboler kan exporteras från ett *Layer* till en FORMS-rapport.

5. I dialo

grutan väljs OWNSITREP.

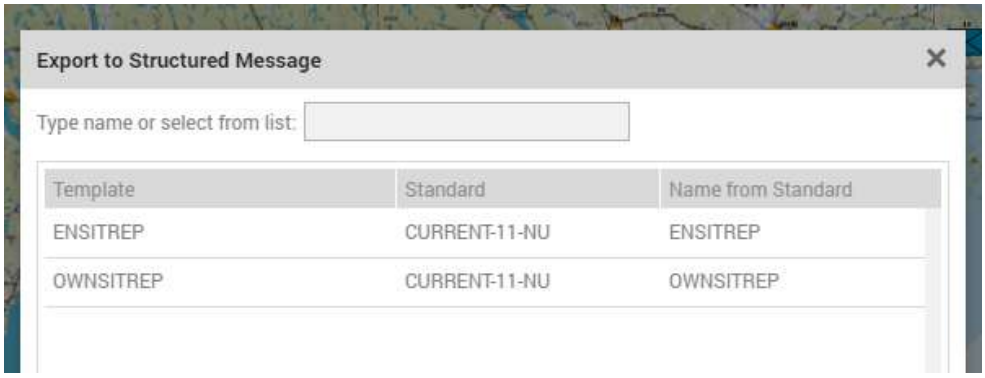

Figur 168 Möjliga FORMS rapporter.

6. När man valt aktuell FORMS-rapport så omvandlar FORMS all information till text i rapporten.

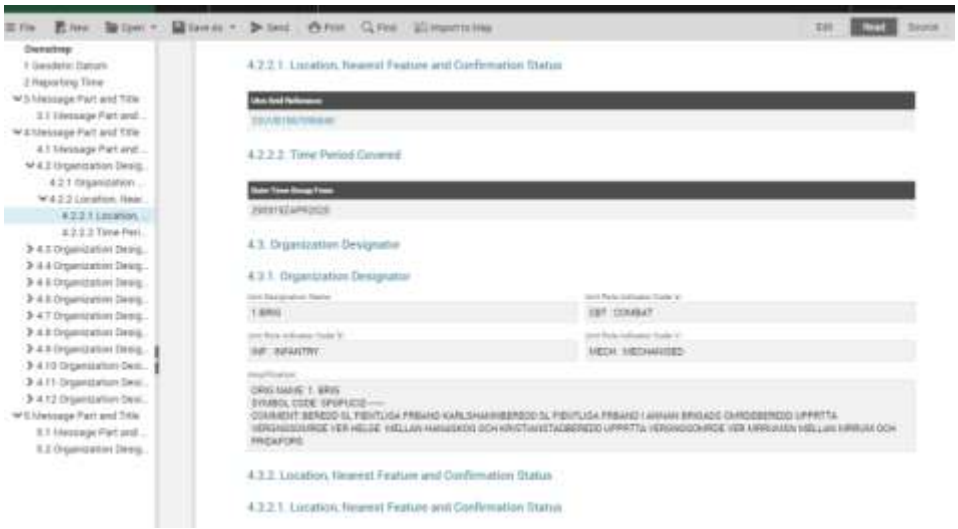

Figur 169 Skapad rapport från ett Layer med kommentarer.

De kommentarer som finns inskrivna i förbandssymbolens *Symbol Properties/Comments* följer också med i rapporten.

Ska man skapa en INTSITREP gör man på motsvarande sätt men väljer då ett *Layer* som innehåller fiendens förbandssymboler.

14.4.2 Öppna rapport i kartvyn

Har man fått en OWNSITREP eller ENSITREP så kan informationen i rapporten visas i ett *Layer*. Detta görs på följande sätt:

1. Gå till Current Operations.

2. Öppna FORMS.
3. Öppna FORMS-rapporten.
4. Välj *Import to Map*.

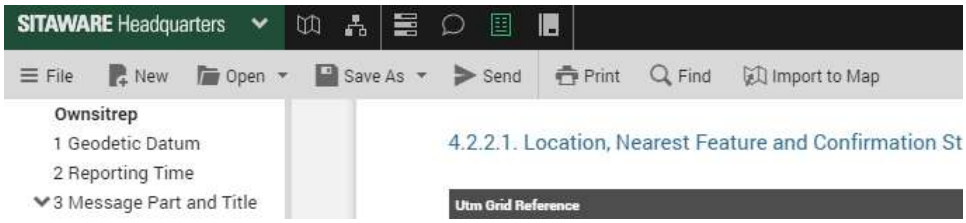

Figur 170 Meny för att öppna en FORMS rapport i ett Layer.

5. Välj ett *Layer* som informationen ska importeras till. Företrädesvis så har man skapat ett stabsintern lager som heter exempelvis Datum-OWNSITREP_Förband. Klicka därefter på *OK*.
6. Informationen omvandlas nu till en geografisk bild med symboler med innehåll. Observera att Å, Ä och Ö inte kommer att visas.

14.5 Instruktion för import av FMMK i IRIS Forms

I det fall då HC fastställt att FORMS ska användas för rapportering behöver man säkerställa att man har de senaste rapportmallarna ur FMMK installerade. Detta görs enligt följande:

1. Tillse att importfilen finns tillgänglig på servern och att det är den senaste versionen av FMMK.
2. Öppna upp IRIS WebForms administrativa gränssnitt i webbläsaren. Adress återfinns i administrationsmanual för SitaWare HQ, normalt: https://<host>:11006/apa-webcontent/rproxy/webforms/administration.html

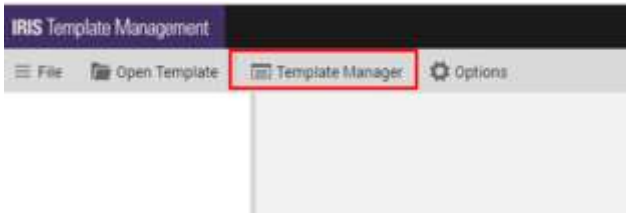

Figur 171 Gränssnitt för IRIS administration.

3. Öppna *Template Manager* och klicka på *Import Local*.

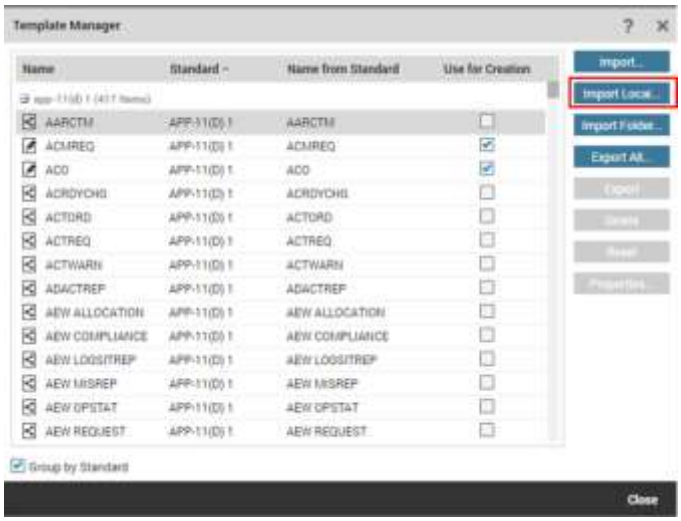

Figur 172 Meny för import av FORMS mallar.

4. Nu öppnas Utforskaren. Välj den fil som ska importeras (fil med filändelse ’.icp’) och klicka på *Öppna.*

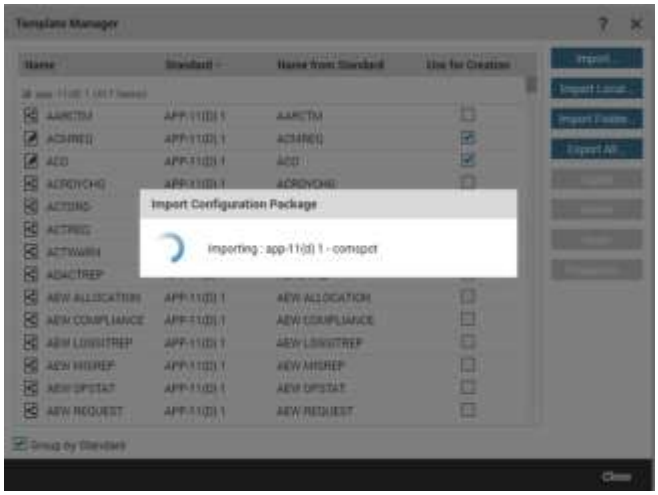

Figur 173 Import av FORMS-mallar.

5. Vänta tills importen är klar, kontrollera att importerade meddelandemallar visas i listan.
6. Om vissa meddelandemallar inte används i aktuell installation/nod, bocka ur rutan *Use for Creation* längst till höger i listan. Stäng därefter *Template Manage.*

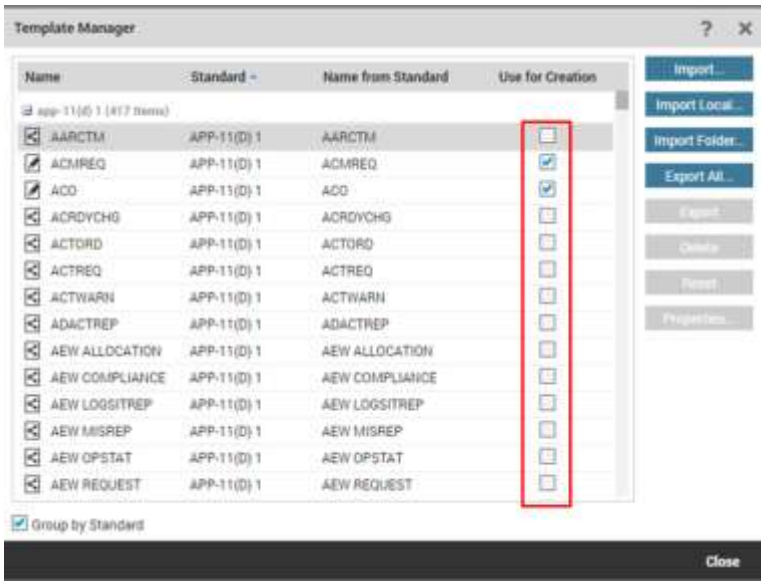

Figur 174 Val av vilka mallar som skall vara tillgängliga då man skapar nya rapporter.

Inga meddelandemallar får raderas utan specifik order från högre chef då man inte kan ta emot en meddelandemall som man inte har i *Template Manager*.

TIPS!
När HC fastställt vilka mallar i FORMS som ska användas rekommenderas att man bockar ur alla övriga mallar i listan så att endast de fastställda kommer vara valbara i FORMS.

Avsluta med att kontrollera i SitaWare HQ FORMS att mallarna finns tillgängliga genom att välja *New Form* och scrolla igenom listan.

15 Övriga verktyg och stöd

15.1 Geografiska analysverktyg

Geo Tools är grafiska verktyg som man kan använda för analys av terräng på kartan, till exempel i samband med planering där man vill räkna ut längden på en landningsbana eller lämpliga placeringar av o-platser och sambandsutrustningar.

***Range/Bearing Tool*:** Används för att kart-rekognosera längd över ett visst streck. Lämpligt att använda vid bedömandet av beräknandet av längden på en landningsbana, en avståndssträcka vid framryckning eller avståndet mellan förband.

***Highest Point Tool*:** Används för att kart-rekognosera höjddata inom ett visst område där man behöver ta ut högsta höjden. Verktyget är lämpligt att använda vid bedömandet av vart man kan placera en o-plats, sambandsutrustning.

***Area of Sight Tool*:** Används för att kart-rekognosera höjddata inom ett avgränsat område. Verktyget är lämpligt att använda vid bedömandet av vart man kan placera sambandsutrustning eller beräkna framkomlighet.

***Line of Sight Tool*:** Används för att kart-rekognosera höjddata över ett visst streck. Verktyget är lämpligt att använda vid bedömandet av vad en o-plats kan se eller hur man kan placera skarpskytt vid till exempel flygplats.

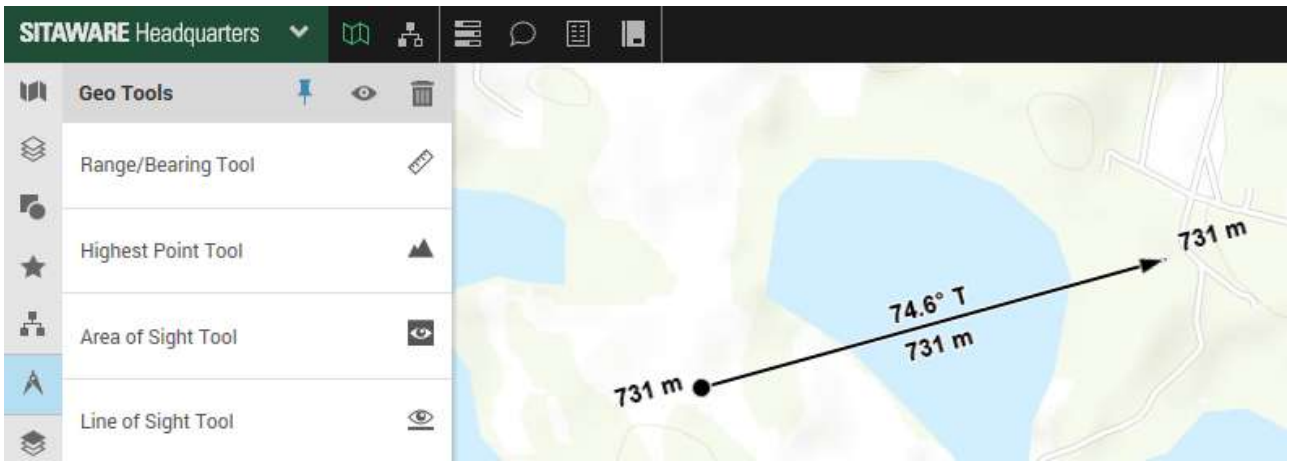

Figur 175 Geoverktyg i SitaWare HQ.

15.2 Söka koordinater och konvertera koordinater

I SitaWare HQ kan man även söka efter koordinater. Genom att skriva in koordinaten i fältet enligt nedan och sedan trycka enter flyttas kartan till den plats koordinaten befinner sig på.

Platsen är mitten av kartan. Det kan vara lämpligt att zooma in rejält i kartan innan man lägger in koordinaten.

Vill man veta punkten specifikt rekommenderas att lägga ut en kartsymbol lämpligen istället och att följa direktiven enligt 6.5 Flytta förband med koordinat.

När man trycker på fältet kommer det upp flera fält med olika koordinatsystem. Det är konverterade koordinater för andra positionssystem som man kan använda ifall man behöver kommunicera med andra myndigheter eller stridskrafter.

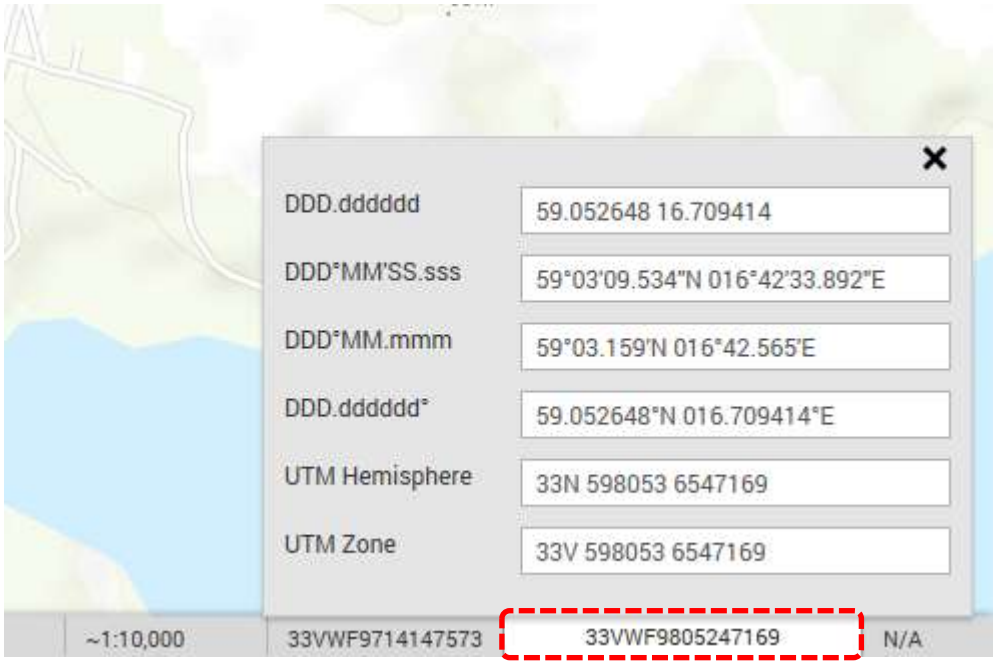

Figur 176 Söka efter och konvertera koordinat.

15.3 Söka efter platser eller kartsymboler

SitaWare HQ sökfunktion kan användas för att söka efter platser och kartsymboler, exempelvis städer, kommuner, egna förband, andra kartsymboler. Om man dubbelklickar på sökresultatet centrerar kartan sig och man finner platsen eller kartsymbolen.

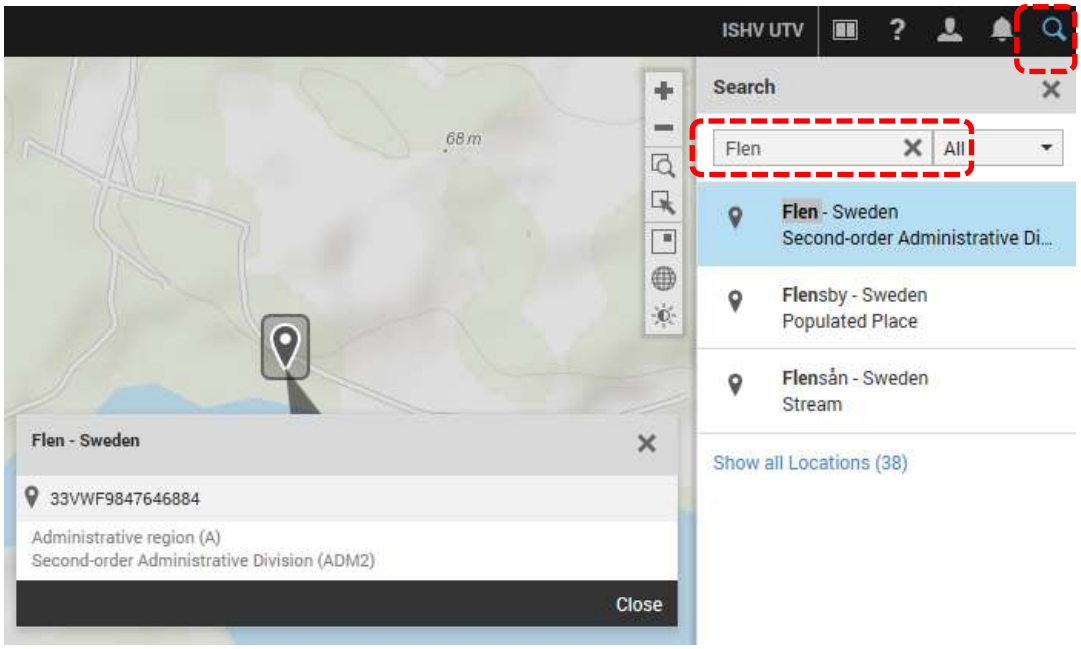

Figur 177 Sökfunktionen med platser och kartsymboler.

15.4 Flera fönster

SitaWare HQ stödjer visning av olika flera applikationer samtidigt i en *Split Screen* presentation. Användaren kan alltså arbeta med information från två applikationer samtidigt.

Systemet stödjer däremot inte ha samma applikation öppen två gånger i en *Split Screen*. Exempelvis går det inte att ha två kartfönster öppna samtidigt. Detta åstadkommes istället genom att starta ytterligare en session av SitaWare HQ (öppna en ny flik i webbläsaren med SitaWare HQ).

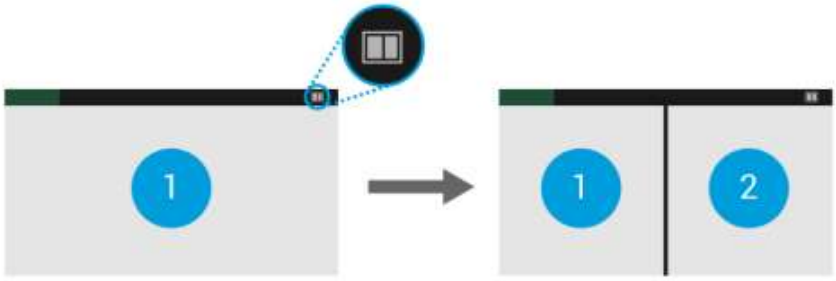

Figur 178 Split Screen finns i övre högra hörnet.

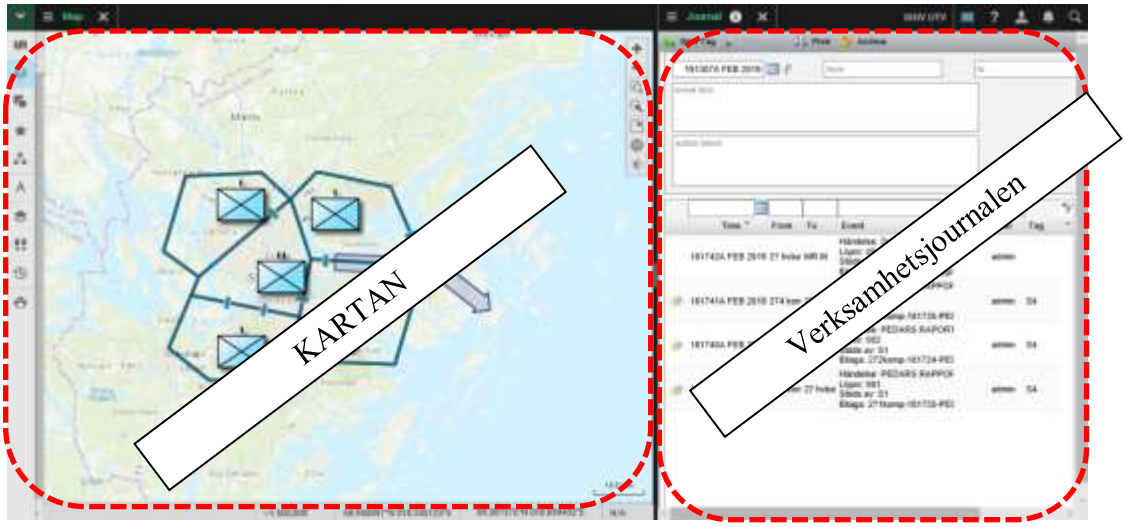

Figur 179 Exempel på Split Screen med lägeskarta och verksamhetsjournal.

15.5 Presentationsverktyg

Presentation Tools återfinns under den övre applikationsmenyn och kan användas vid presentationer för att förstärka beskrivningar.

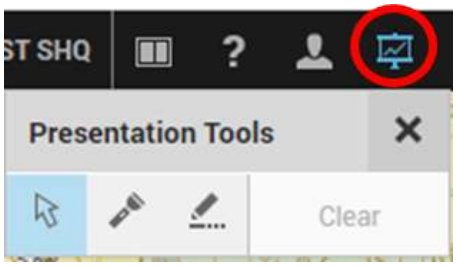

Figur 180. Meny för Presentation Tool.

Under *Presentation Tool* finns tre stycken val. Det första är en ”ficklampa”. Klicka på symbolen med en ficklampa för att välja färg och storlek på ”ljuskäglan”. Ficklampan hålls tänd när man håller ner vänster musknapp och används som digital pekpinne.

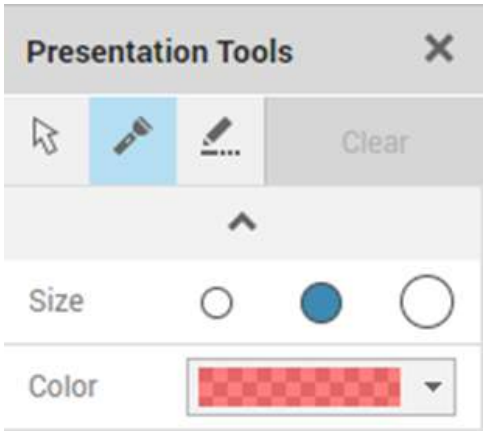

Figur 181 Presentations "ficklampa".

Den andra funktionen är möjlighet att frihandsrita linjer. Även här kan man välja färg och tjocklek på linjerna. Dessutom kan man med *Duration* välja hur länge linjerna ska synas i bilden. För att ta bort ritade linjer innan vald tid, klicka på *Clear* så raderas alla ritade linjer.

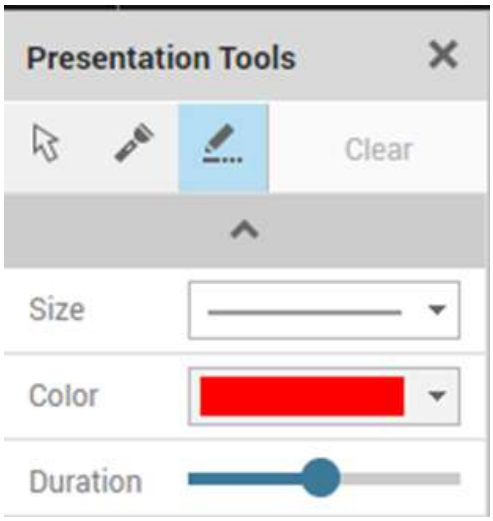

Figur 182 Presentationsstreck.

Alla ritade linjer finns bara i *Presentation Tool* och inte i några *Layers*. För att behålla något ritat från *Presentation Tool*, välj en ”evig” *Duration*, aktivera ett lämpligt *Layer* och rita sedan av det som ska sparas. Välj *Clear* när du är klar med *Presentation Tool*.

Ett exempel kan vara då en chef vid en stabsorientering gör ett första utkast till målbild och staben har behov av att använda underlaget inför fortsatt arbete med målbilden.

15.6 Smart Layers

Smart Layers används för att filtrera information ur ett eller flera *Layers*. Ifall ett Layer upplevs för informationstungt och svårt att överblicka kan man i staben skapa så kallade *Smart Layers*.

Smart Layers är *Layers* som kan hämta och visa information från ett eller flera andra *Layers* utifrån ett filter. Detta filter kan utgå från förbandsstorlek, namn på geografiskt område, symbolkod, förbandstyp, med mer. Olika filterurval kan kombineras.

Smart Layers kan inte replikeras utan används endast inom egen stab. Det kan vara lämpligt att skapa en *Picture* för stabens gemensamma *Smart Layers* och att informationsledare är ansvarig för att vid behov skapa dessa *Layers*.

OBSERVERA!
Att skapa *Smart Layers* kräver en god kunskap om vilken information som finns i ordinarie *Layers* samt god förmåga att bygga filter, speciellt om det ska vara kombinerade filterparametrar.

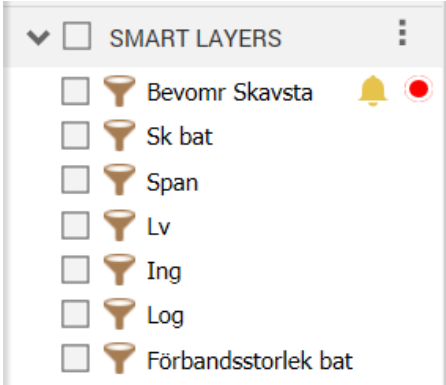

Figur 183 Exempel på en Picture för gemensamma Smart Layers.

15.6.1 Skapa ett Smart Layer, förändringar.

I nedanstående text och bild visas ett *Smart Layer* som följer upp alla ändringar av förband i ett visst lager.

Detta Smart Layer skapas enligt följande:

1. Välj aktuell *Picture* och högerklicka på de tre prickarna.
2. Klicka därefter på *Create Smart Layer*.
3. I fönstret *Create Smart Layer* namnge *Smart Layer* och beskriv om så behövs syftet med *Smart Layer*, i *Name*-respektive *Description*-rutan.
4. Klicka därefter på *Sources*.

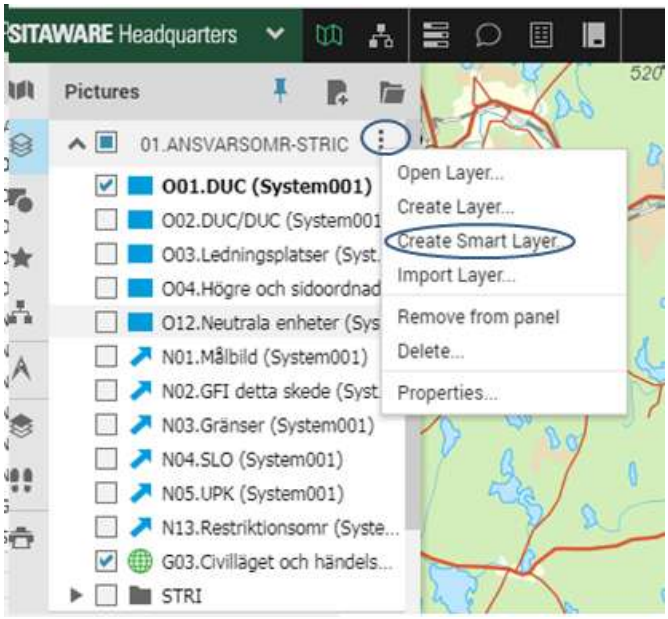

Figur 184 Skapa Smart Layers.

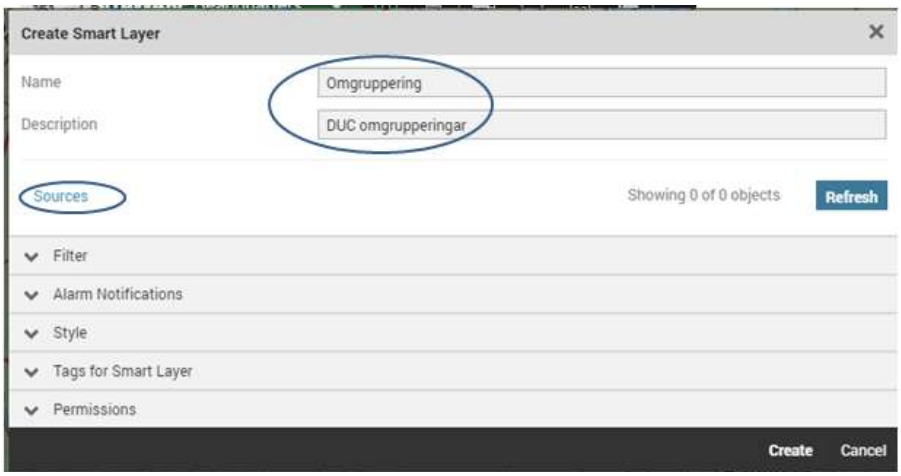

Figur 185 Exempel på namngivning av Smart Layers.

5. För att kunna välja från vilket *Layer* informationen ska hämtas till *Smart Layer*, klicka i *Add Sources Layers* i fönstret *Manage Sources*.

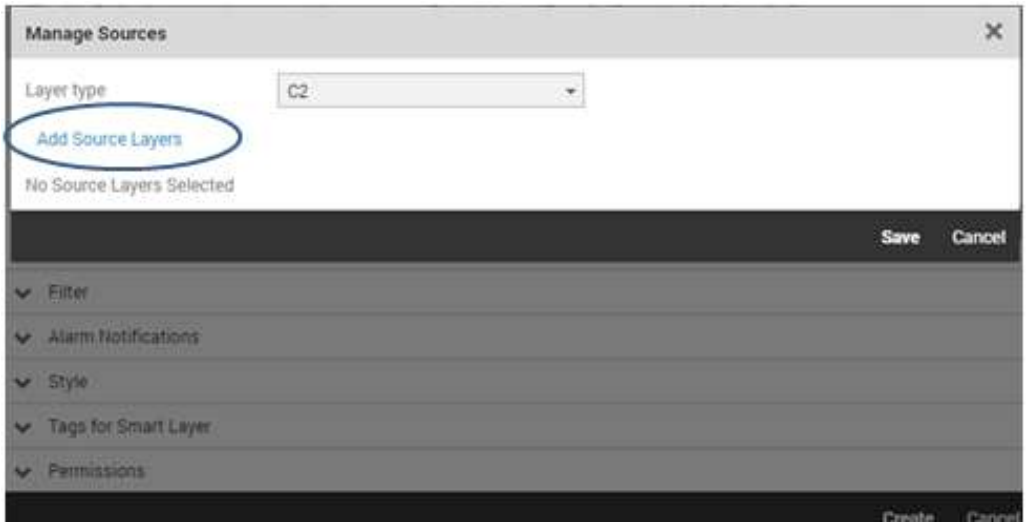

Figur 186 Val av Layer.

6. I *Select Source Layers*-fönstret visas nu valmöjligheterna. Aktuellt *Smart Layer* utgår från lagerstrukturen. Här väljs ifrån vilken nod informationen ska komma ifrån.
7. Klicka på aktuell nod. Bocka i det *Layer* som informationen ska komma ifrån och klicka på *Select*.

OBSERVERA!
Om informationen som visas i aktuellt *Smart Layer* kommer från olika *Layers* så måste dessa bockas för i fönstret *Select Sources Layers*.

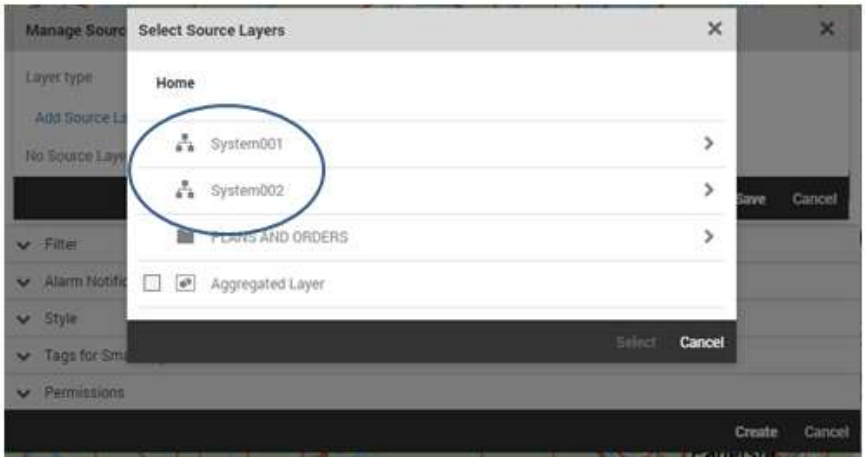

Figur 187 Val av nod.

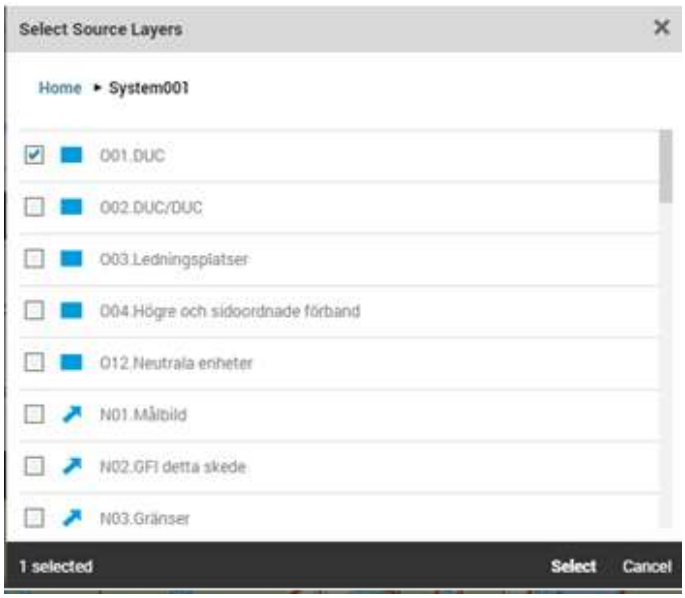

Figur 188 Select Source Layers.

8. I fönstret *Manage Sources* visas hur många symboler som finns i aktuellt lager. Klicka på *Save*.

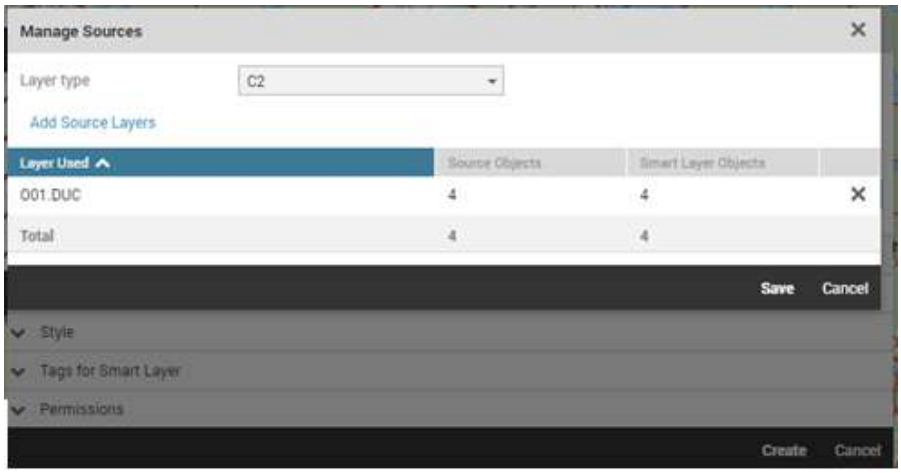

Figur 189 Manage Sources.

9. Klicka på *Refresh* i fönstret för *Smart Layer Properties* för att uppdatera antalet symboler. Genom att ange ett antal förutsättningar bestäms vilken information som ska redovisas i aktuellt *Smart Layer*. I detta fall ska informationen visa när förbandssymboler ändrar position.
10. Filter väljs enligt nedanstående bild. *Alarm Notifications* kopplas också på enligt nedanstående bild. Klicka därefter på *Save*.

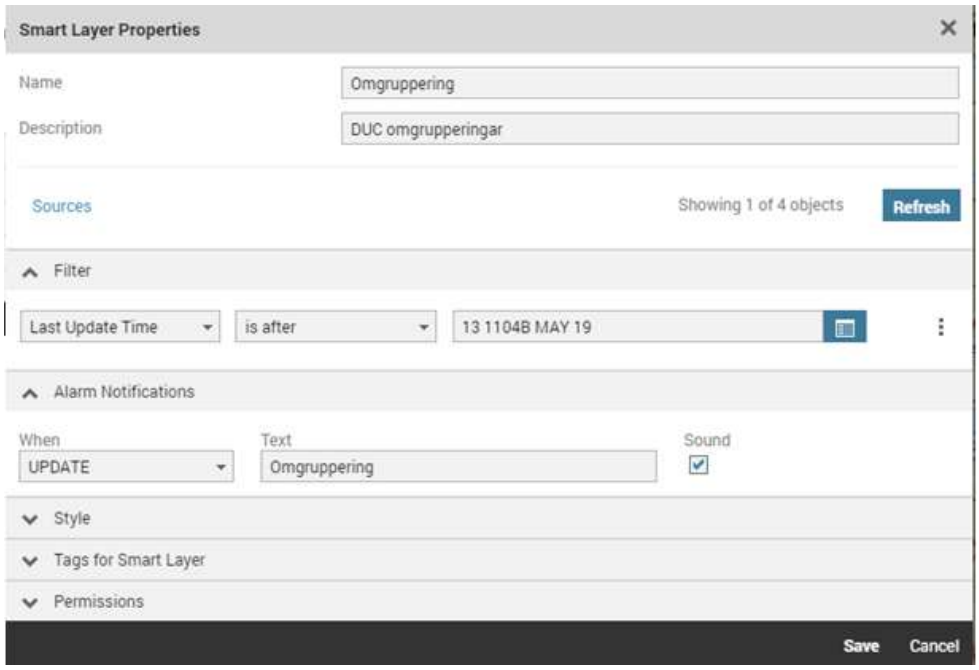

Figur 190 Smart Layer Properties.

I *Smart Layer Omgruppering* kommer de förbandssymboler som har ändrat position att finnas. Uppe i högra hörnet på kartbilden kommer det också att visas ett fönster som talar om att en positionsändring har skett.

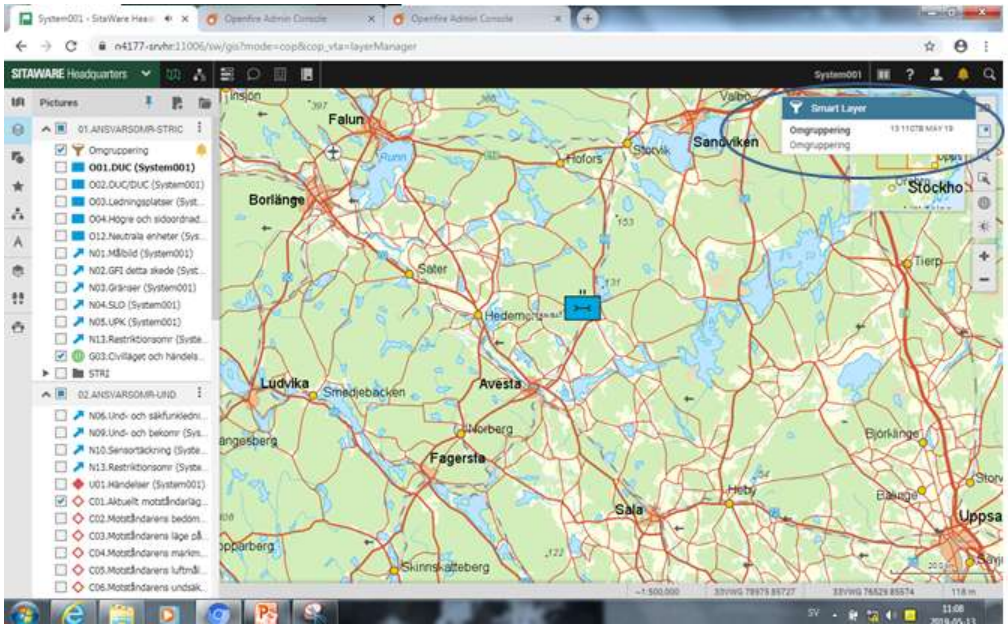

Figur 191 Information om positionsändring.

Alla positionsförändringar som har skett kan ses i *Notification* och i fliken *Smart Layer*.

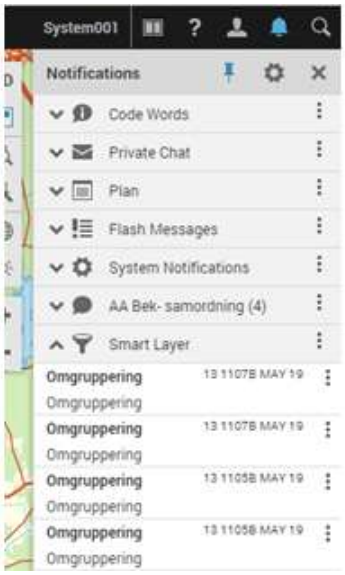

Figur 192 loggning av händelse.

15.6.2 Skapa Smart Layers, område

I detta exempel skapas ett *Smart Layer* som informerar när ett förband förflyttar sig in i ett område. I detta exempel är utgångspunkten samma som i tidigare *Smart Layer*. Det vill säga *Picture 01. ANSVARSOMRÅDE- STRIC* och *Layer O01. DUC* nyttjas.

1. Rita in ett polygonområde från *Symbol Toolbox* i rätt *Layer* (*N13. Restriktionsomr.*) och döp det.

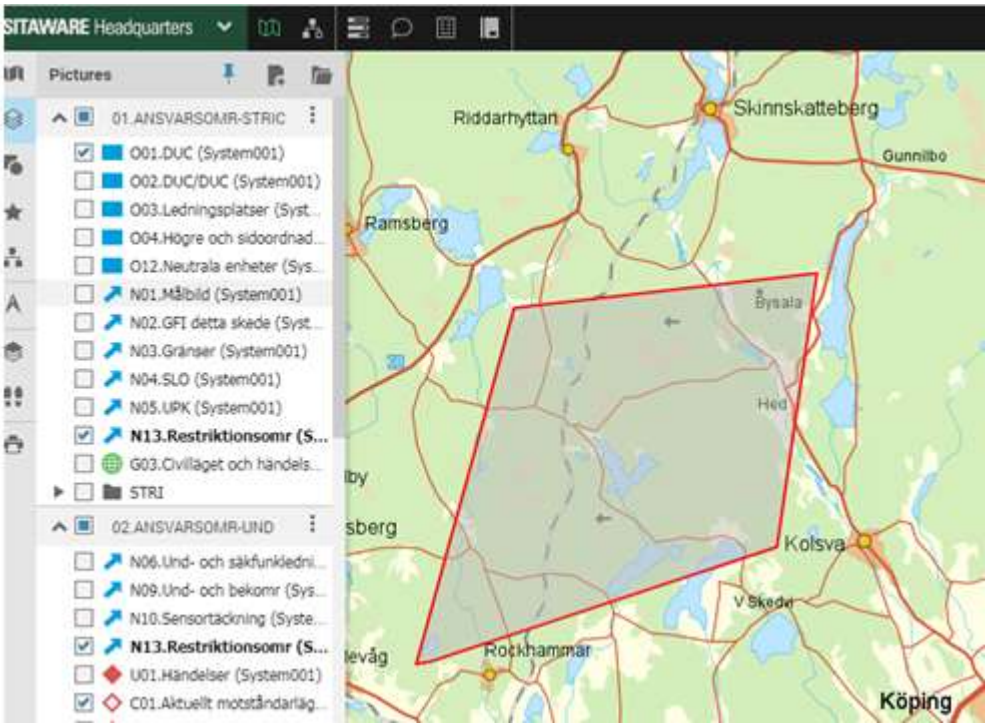

Figur 193 Område Smart Layer.

2. Skapa ett *Smart Layer* i aktuell *Picture*. Namnge samt beskriv det i fönstret *Create Smart Layer*.

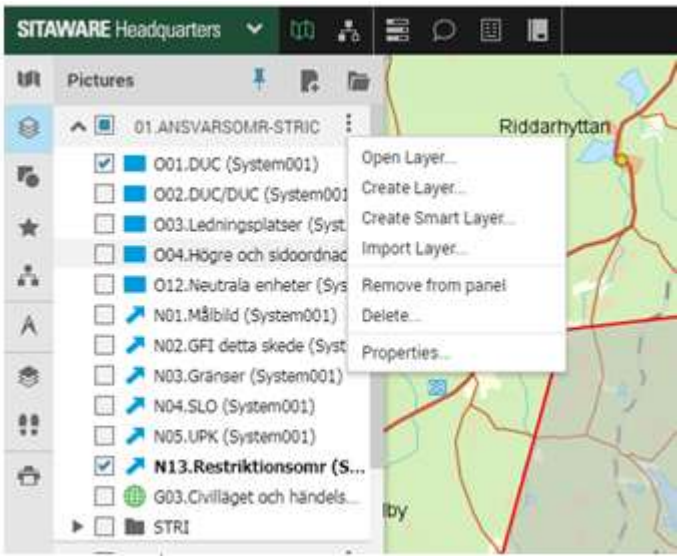

Figur 194 Create Smart Layer.

OBSERVERA!
Om informationen som visas i aktuellt *Smart Layer* kommer från olika *Layers* så måste dessa bockas för i fönstret *Select Sources Layers*.

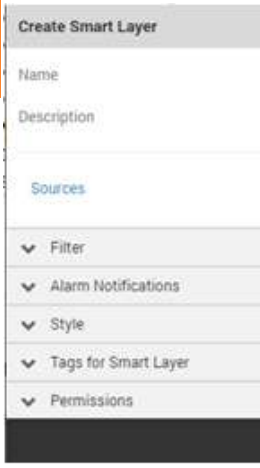

Figur 195 Exempel på namngivning av Smart Layer.

3. Välj filterinställning. I detta fall är valet *Monitored Area*, *is inside* och klicka på *Select Area*.

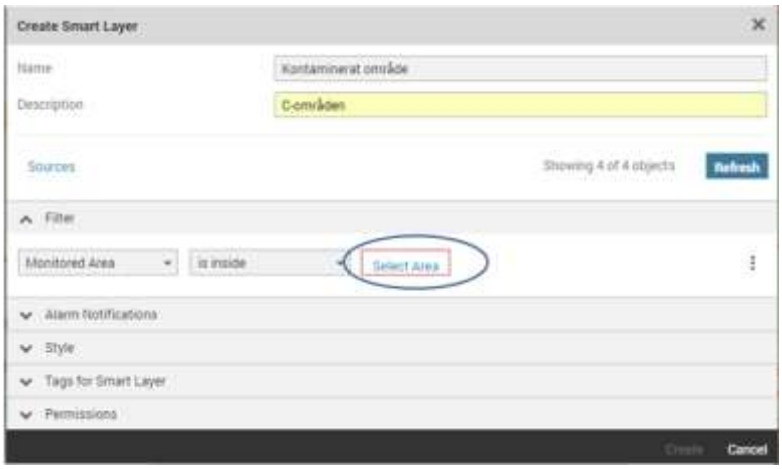

Figur 196 Filter.

4. Markera aktuellt område och klicka på *Select*.

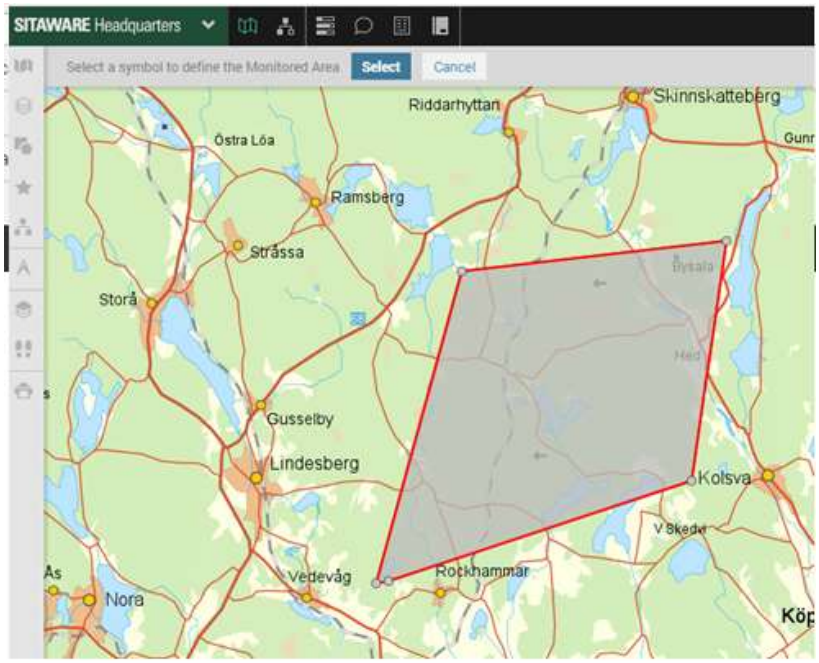

Figur 197 Val av område.

5. I fönstret *Create Smart Layer* under fliken *Filter* visas det aktuella området som har valts.
6. Klicka på *Create*. Nu är *Smart Layer* med *Alarm Notification* är klar att använda.

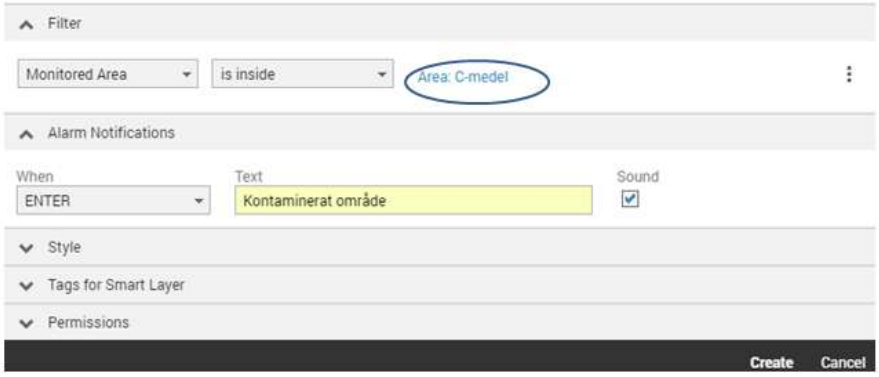

Figur 198. Kvittens av valt område i Smart Layer.

Bilaga 1 Översättningstabell

Engelskt namn	Svensk översättning
Funktioner i kartvyn	
Current Operations	Nuvarande läge
Base Map	Kartor
Pictures	Vy
Layers	Oleat
Properties	Egenskaper
Symbol Toolbox	Symbolbibliotek
Bookmarks	Bokmärken
Organization Viewer	Förbandsorganisation
Layer Contents	Oleat-innehåll
Print Map	Utskrift (av karta och oleat)
ORBAT Editor	Verktyg för Förbandsorganisation
Holdings	Underhållsläge
Unit Status	Stridsvärdesrapport
Forms	Rapportmallar
Journal	Verksamhetsjournal
Split View	Delad skärm
Settings	Inställningar
User Settings	Användarinställningar
Notifications	Användarlarm
Search	Sökfunktion
Funktioner i öppnade symboler	
Symbol Properties	Förbands/symbol information
Additional information	Tilläggsinformation (max 2000 tecken)
Hostility	Graden av fiendskap. Symbolens förhållande (eget, fientligt, neutralt, okänt, mm) till svenska förband.
Alternative name	Anropssignal
Staff comments	Korta kommentarer (max 20 tecken)
Funktioner för planer och order	
Plans & Orders	Planer och orderverk
Plan Browser	Visningsvy av samtliga planer/order
Plan Overview	Visningsvy för öppnad plan/order
Add	Lägg till
Folder	Mapp
Heading	Rubrik
Draft	Utkast (under utarbetande)
Approval in progress	Låst för godkännande
Approved	Godkänd
Issued	Fastställd/gällande

Canceled	Upphävd/avbruten
Funktioner för underhållsläget	
Nominal Holdings	Grundtilldelning (RU)
Equipment	Utrustning/materiel
Consumable	Förbrukningsmateriel (inklusive ammunition och drivmedel)
Personel	Personal

Bilaga 2 Övningsuppgifter och test

Momenten görs i nummerordning då vissa moment bygger på tidigare genomförda moment.

Efter genomgången utbildning behöver den kompletteras med tillämpning för aktuell stab. Det vill säga styrningar ur stående stabsorder för hur lägesbilden, orderarbete, meddelandehantering, rapportering et cetera ska hanteras inom staben samt informationsutbytet med andra staber.

Övningarna bygger på att ISHv är upprättat och rätt konfigurerat med inlästa informationsprodukter. Innan övningarna skapas:

- I *Plans & Orders* en *Folder* som döps till Operation UTB. I den läggs en lämplig order som innehåller både ett huvuddokument och plan-*Layers*.
- I mappstrukturen under mapp Gemensam skapas en mapp som döps till Utbildning.
- I Journalen hittas en Tag som heter Utbildning

Vid lösandet av övningsuppgifterna nyttjas anropssignaler med befattningsnummer ur FAL-A enligt nedan:

Nr	Funktion/Befattning	Nr	Funktion/Befattning
1	Chef	**40**	**Underhåll/Logistik**
2	Ställföreträdande chef	41	Chef/kvartersmästare
3	Stabschef	48	Teknisk chef
4	Förvaltare	42-47,49	Underhålls/logistikbefattningar
5-9	Gemensamma befattningar	**50**	**Fältarbeten**
10	**Personal**	51	Chef
11	Personalchef	52-54	Fältarbetsbefattningar
12-19	Personalbefattningar	**55**	**Luft**
20	**Underrättelse- och säkerhet**	56	Chef
21	Chef	57-59	Luftbefattningar
22-29	Underrättelse- och säkerhetsbefattningar	**60**	**Samband/ledningssystem**
30	**Stridsledning**	61	Chef
31	Chef	65	Signalskyddschef
32-34	Stridsledningsbefattningar	62-64, 66-69	Sambands/ledningssystemsbefattningar
35	**Bekämpning**	**70-79**	**Nätdrift**
36	Chef	**80-89**	**Sjukvårdsledning**
37-39	Bekämpningsbefattningar	**90-99**	**Reserv**

Börja med att logga in i systemet och starta Sitaware HQ. Gå till *Bookmarks* och öppna stabens Start-*Bookmark*. Stäng därefter appen *Bookmark* så att hela kartan syns.

Övningarna inleds med en referens till denna instruktion. I de fallen att ingen relevant anvisning finns hänvisas till den inbyggda hjälpfunktionen alternativt *SitaWare Headquarters User Manual*.

Öppna *Current Operations* och genomför övningsmomenten.

Övning 1: Navigera i gränssnittet Current Operations

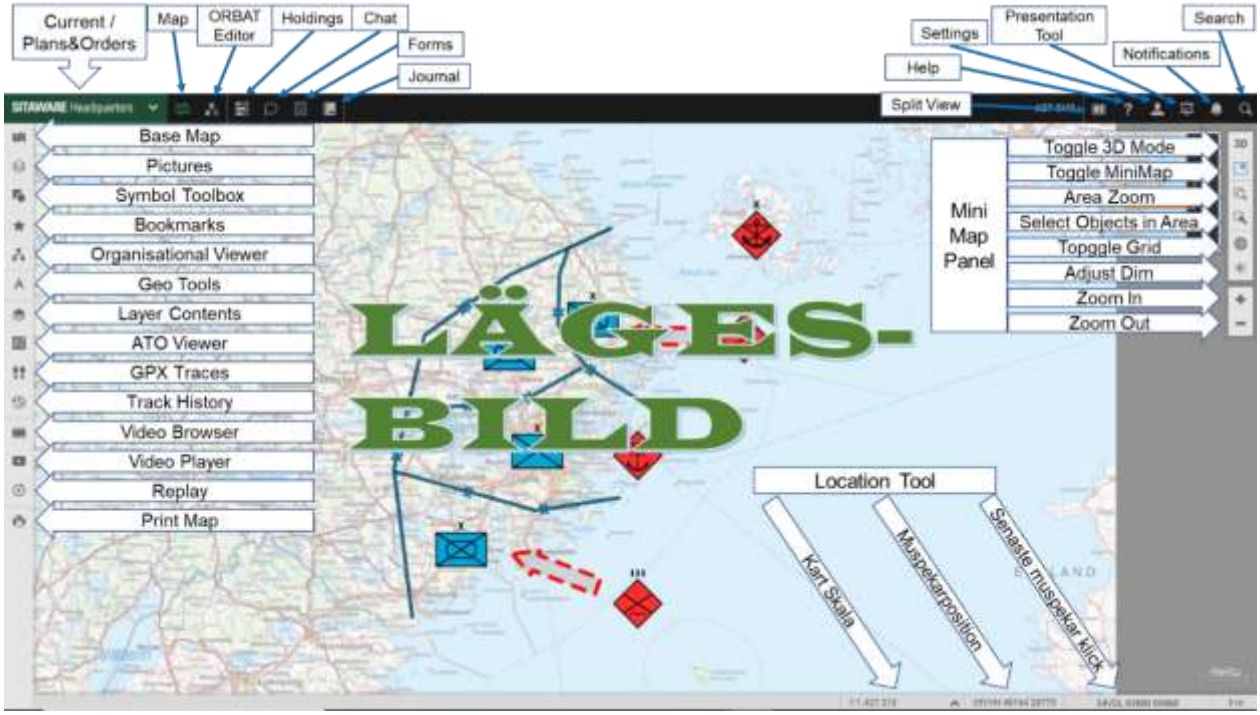

Navigera runt i gränssnittet genom att föra muspekaren över respektive app för att identifiera var olika appar återfinns i *Current Operations*. Avsluta med att stänga alla appar så att endast kartbilden syns.

Övning 2: Navigera i gränssnittet Plans & Orders

Byt från *Current Operations* till *Plans & Orders*.

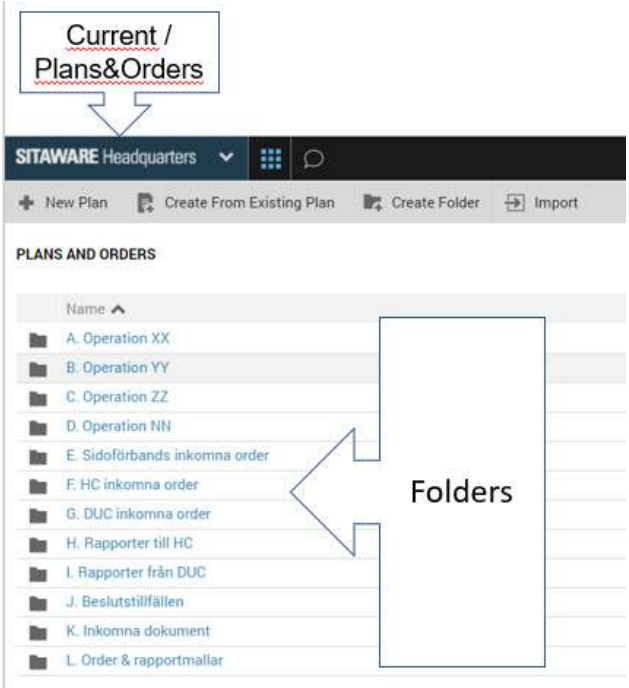

Navigera runt i foldrarna, avsluta med att öppna folder **Operation UTB** och öppna den order som finns där genom att klicka på den.

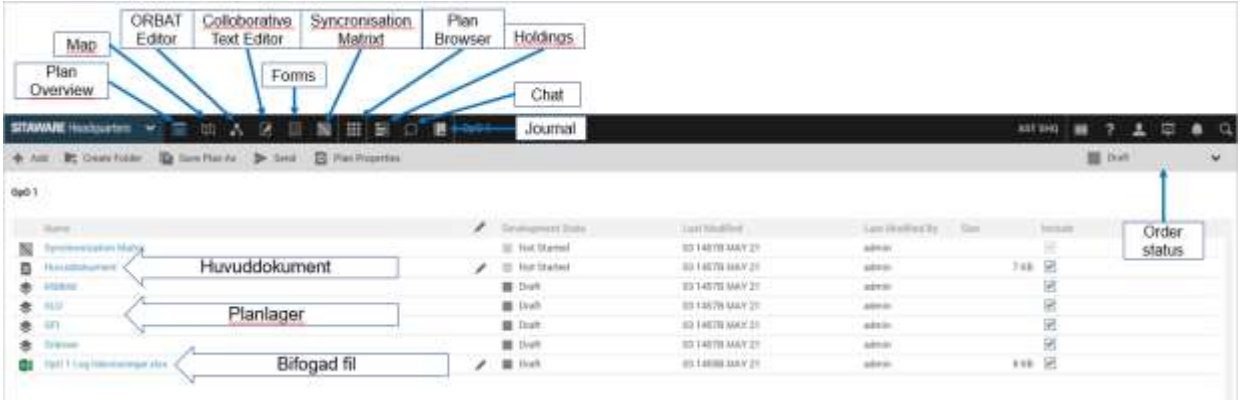

Navigera runt i gränssnittet genom att föra muspekaren över respektive app för att identifiera var olika funktioner återfinns i *Plans & Orders*. Avsluta med att gå tillbaka till *Plan Browser* för att se samtliga delar i OpO.

Gå till *Current Operations* och genomför kommande övningsmoment.

Övning 3: Personliga inställningar

Anvisning	3. Personliga inställningar

Mom	Verksamhet	Klart
1	Öppna appen *Settings* / *User Settings*	
2	Kontrollera i *General* att positionsformatet är MGRS.	
3	Kontrollera i *General* att *Browser Navigation* är *Use existing browser tab.*	
4	I *Symbols* ställ in *Size on map* och skala 1:2500 000 samt bocka ur *Always expand Report Dialog.*	
5	I *Labels* ställ in *Label Size* och skala 1:2500 000.	
6	Avsluta med att välja *Save* för att spara inställningarna.	

Övning 4: Grundläggande karthantering

Anvisning	4. Kartunderlag

Mom	Verksamhet	Klart
1	Kontrollera vilka kartor som finns i systemet. Vid behov byt karta. **Tips:** Detta görs i appen *Base Map*.	
2	Justera kartan genom att:	
	a. Zooma in och ut ur kartan (både med mus och med *Mini Map* verktygen).	
	b. Ändra skalan till 1:250 000. **Tips:** Görs längs ner i gränssnittet i *Location Tool*.	

	c. Tänd och släck rutnätet. **Tips:** Görs vid *Mini Map Panel.*	
	d. Justera ljusstyrkan för kartan. **Tips:** Görs vid *Mini Map Panel.*	
3	Ange vad som finns på koordinaten: 33V XF 15601 83641. Zooma in till ca 1:10 000. **Tips:** Skriv in koordinaterna i koordinatfönstret längs ner till höger i gränssnittet, tryck *Enter* för att centrera kartan på angivna koordinater.	
4	Ange koordinaterna för egen stabsplats. **Tips:** Klicka på platsen i kartan och kopiera koordinaterna från koordinatfönstret längs ner till höger i gränssnittet. Kan göras med CTRL+C och sedan kan man klistra in koordinaterna i ett dokument med CTRL+V.	
5	Ange längden på Ölandsbron, i meter, från brofästet Svinö till brofästet Öland. **Tips:** Använd *Geo Tools* / *Range Tool* för att mäta längden.	

Övning 5: Lägesbild

Anvisning	6. Kartsymboler och förband

Mom	Verksamhet	Klart
1	Skapa en egen mapp i *SitaWare HQ/Current/Pictures* i arbetsmappen som finns i din funktions *Picture* **Tips:** Högerklicka på arbetsmappen och välja *Create Group*. Döp mappen till din anropssignal. I mappen skapas egna *Layers* (totalt 5 st enligt nedan) för de uppgifter som behöver detta.	
2	Skapa en lägesbild för en bataljon med fyra kompanier i din arbetsmapp bestående av följande:	
	a. Ett *Layer* **Gränser** med yttre (bataljon) och inre (kompani) förbandsgränser. **Tips:** Högerklicka på egen mapp och välj *Create Layer*. Hämta förbandsgränser från *Symbol Toolbox* flik 08.Linjer.	
	b. Ett *Layer* **DUC** med förbandssymboler (från ORBAT) ner till och med kompani. Fyll i en stridsuppgift i kompanisymbolerna. **Tips:** Högerklicka på egen mapp och välj *Create Layer*. Hämta förbandssymbolerna från *Organization Viewer*. Klicka på aktuell förbandssymbol, för in muspekaren på kartan och klicka en gång för att	

	lägga in symbolen. I den öppnade förbandsrapporten fyll i en uppgift i det övre fältet *Enter Additional Info….* Klicka på *Save* och upprepa förfarandet tills alla förband är utlagda i kartan. Behöver ett förband flyttas i kartan så klicka på förbandet så att det får en röd ram, dra därefter förbandet till ny plats med musen.	
	c. Ett *Layer* **UPK** med minst 5 st UPK-er. **Tips:** Högerklicka på egen mapp och välj *Create Layer*. Hämta UPK från *Symbol Toolbox* flik 07.Punkter.	
	d. Ett *Layer* **SLO** med minst 5 st samordningslinjer. **Tips:** Högerklicka på egen mapp och välj *Create Layer*. Hämta samordningslinjer från *Symbol Toolbox* flik 08.Linjer.	
	e. Ett *Layer* **Målbild** med en målbild omfattande frihandsritnings pilar, områden och textrutor. **Tips:** Högerklicka på egen mapp och välj *Create Layer*. Hämta symboler och minst en textruta från *Symbol Toolbox* flik 01.Ritverktyg.	
3	Spara ner lägesbilden i Gemensam/Utbildning som PDF, med alla *Layers* tända. **Tips:** Tänd alla 5 *Layers*, justera kartan och välj *Print Map* och *Poster mode* (2x2). Fyll i fälten i *Decorations* och avsluta med *Save*. Sparad lägesbild finns nu i *Downloads* och kan flyttas till Gemensam/Utbildning.	
4	Kontrollera innehållet i eget *Layer* DUC med *Layer Contents*. Växla mellan olika kolumner. **Tips:** Högerklicka på aktuellt *Layer* och välj *Layer Contents*. Byt kolumner via åtgärdsprickarna på höger sida i fönstret (*Select Columns*). Avsluta med att stänga fönstret *Layer Contents*.	

Övning 6: Geo Tools

Anvisning	15.1. Geografiska analysverktyg

Mom	Verksamhet	Klart
1	Använd appen *Geo Tools*: **Tips:** Vid alla mätningar undvik att mäta i skala större än 1:50 000 då mätningen riskerar att ta lång tid att genomföra.	
	a. Välj skala 1:5000 och mät högsta punkten inom ett område. Radera mätningen.	
	b. Välj skala 1:10 000 och mät siktlinjen för en observatör på 3 m höjd och för ett mål som är 4 m högt. Radera mätningen.	
	c. Välj skala 1:50 000 och skapa räckviddscirklar för 500m, 1000m, 1500m och 2000m. Välj olika färger för respektive cirkel.	
	d. Flytta centrum på räckviddscirklarna till ny plats i kartan.	
	e. Dölj räckviddscirklarna (ska inte raderas).	

Övning 7: Journal

Anvisning	10. Verksamhetsjournal

Mom	Verksamhet	Klart
1	Öppna Journalen.	
2	Skapa en civil händelse omfattande en brand i hamnen Oxelösund. Informationen kommer från Lsty Sörmland. **Tips:** Fyll i direkt i fälten och välj *Create*. När händelsen är skapad, öppna den och sätt *Tag Utbildning* och välj *Save*.	
3	Skapa en händelse om att stabens dagliga förbandsrapport är skickad till HC. Gör på samma sätt som i mom 2.	
4	Uppdatera att branden i hamnen Oxelösund nu är släckt. **Tips:** Öppna händelsen genom att dubbelklick på den och uppdatera den och välj *Save*.	
5	Gruppera alla händelser efter tid. **Tips:** Detta görs i kolumnrubrik *Time* och väljer *Group by Time*.	
6	Skriv ut (spara som PDF) alla civila händelser. **Tips:** Markera *Tag Utbildning* och klicka på *Print*. Klicka på *Print Preview* och välj PDF och spara filen på X:.	

7	Ändra kategori (*Tag*) för händelsen om branden i hamnen Oxelösund till *Arkiv*. **Tips:** Öppna händelsen och byt *Tag*. Klicka på *Save*.	
8	Öppna Journalen och chatten i ett delat fönster. **Tips:** Öppna *Journalen* och därefter välj appen *Split View*. Välj *Chat* i *Split View* fönstret. Stäng *Split View* genom att klicka på appen *Split View*.	

Övning 8: Plans & Orders

Anvisning	13. Planer och orderverk

Mom	Verksamhet	Klart
1	Öppna *Plans & Orders*.	
2	Skapa en egen *Folder* i folder **Operation UTB** via *Create Folder* i *Plans&Orders*, döp den till egen anropssignal.	
3	Skapa en ny oporder från 5.punktsordern. **Tips:** Välj *Create From Existing Plan* och hämta mallen från mapp *Templates.* Välj med 5.punktsmallen med interna bilagor.	
4	Döp din order till din befattning.	
5	Säkerställ rätt orderegenskaper (*Properties*) och spara den i egen *Folder*.	
6	Fyll i något kort i minst 5 st rubriker/underrubriker i *Huvuddokument* och klarmarkera dessa genom att ändra status till *Approved* (grön). Inga bilagor ska användas.	
7	Lägg till 5 st plan-*Layers*, döp dessa till **Målbild**, **Gränser**, **IGU**, **UPK** och **SLO**. **Tips:** Görs i *Plan Overview* och via *Add* och där väljs *Layer*.	
8	Kopiera symbolerna från de fem lägesbildslagren till respektive planlager. **Tips:** Gå till *Current Operations*. Expandera egen arbetsmapp så att alla egna *Layers* syns. Gå till *Open Picture* och välj *Plans & Orders Pictures*. Välj där din order och klicka på *Open*. Att kopiera symboler mellan lager görs enligt följande: 1. Aktivera det *Layer* som ska kopieras till genom att dubbelklicka på det så ett det får **fetstil** alternativt högerklicka på valt *Layer* och välj *Set Active Layer*. Tänd inte valt *Layer*, det vill säga klicka inte i rutan till vänster om valt *Layer*.	

	2. Tänd det *Layer* som man vill kopiera från, det vill säga klicka i rutan till vänster om lagret. Ha endast det *Layer* tänt. 3. Ska man kopiera en enskild symbol, högerklicka på aktuell symbol och välj *Copy symbol to active layers xxxx*. Kontrollera att det är rätt mål *Layer* som är aktiverat. 4. Då man kopierar en enskild symbol kommer *Unit Report* att öppnas, välj *Save*. 5. Släck det *Layer* som man kopierat från. Kontrollera att symbolen är kopierad till eget *Layer*. 6. Ska man kopiera flera symboler samtidigt, använd verktyget *Select objects in area* som finns i *Mini Map* panelen. Markera de symboler som ska kopieras och högerklicka på en av symbolerna och välj *Copy all symbol to active layers xxxx*. Kontrollera att det är rätt mål lager som är aktiverat dvs *xxxx*. 7. Släck det *Layer* som man kopierat från. Kontrollera att symbolerna är kopierad till eget *Layer*. Gå tillbaka till *Plans & Orders* och egen order (*Plan Overview*).	
9	Lägg till ett exceldokument till ordern. **Tips:** Görs i *Plan Overview* och via *Add* och där väljs *File*.	
10	Gör ordern klar för godkännande genom att ändra status på orderpunkter och order delar till *Complete*/gul.	
11	Gör ordern klar för fastställande genom att ändra status på orderpunkter och order delar till A*pproved*/grön.	
12	Fastställ order. Säkerställ att alla orderpunkter och ordern har rätt status (*approved*/grön) innan du fastställer ordern i orderfönstret övre högra hörnet (*Issue Order*).	
13	Skriv ut huvuddokumentet som PDF och spara det i Gemensam/Utbildning. **Tips:** I *Plan Overview* öppna huvuddokumentet och välj *Save as PDF*. Dokumentet hamnar i *Downloads* i utforskaren och kan nu flyttas till Gemensam/Utbildning.	
14	Kopiera en inkommen order från *K.Inkommande dokument* till egen *Folder*. **Tips:** Högerklicka på vald order och välj *Copy*. Välj därefter den mapp dit order ska kopieras och välj *Save*.	

Övning 9: Sökfunktion

Anvisning	15.3. Söka efter platser eller kartsymboler
	Samtliga moment genomförs i appen *Search*.

Mom	Verksamhet	Klart
1	Sök efter egen stabs hemort och centrera på svaret. **Tips:** Dubbelklicka på svaret för att centrera.	
2	Sök efter ett av dina utlagda förband och centrera på förbandet. **Tips:** Dubbelklicka på svaret för att centrera.	
3	Sök efter din tidigare skapade oporder.	
4	Gå tillbaka till *Current Operations*.	

Övning 10: Bookmarks

Anvisning	7. Bookmarks

Mom	Verksamhet	Klart
1	Skapa en *Bookmark folder*, döp den till egen anropssignal. **Tips:** Klicka på åtgärdsprickarna och välj *Create Bookmark Folder*.	
2	Skapa en *Bookmark* för varje *Layer* (dvs 5 st) från lägesbilden. Döp varje *Bookmark* till samma namn som respektive *Layer*. **Tips:** Börja med att i *Pictures* släcka alla andra *Layers* och tända eget *Layer* **Gränser**. Zooma in lämpligt område och eventuellt dimma kartan. Gå till *Bookmarks* och öppna egen *Bookmark Folder* och klicka på ikonen *Create Bookmark*. Döp din Bookmark till **Gränser** och klicka på *Create*. Gör om förfarandet för övriga lager.	
3	Spara en PPT från din *Bookmark Folder*. **Tips:** I egen *Folder* klicka på åtgärdsprickarna och välj *Export to PowerPoint*. Öppna bildspelet samt spara på Gemensam/Utbildning.	
4	Skapa en *Bookmark* Oporder med den egna orderns alla *Layers*. **Tips:** Börja med att i *Pictures* släcka alla tända *Layers* och därefter gå till *Open Picture* och välj *Plans & Orders Pictures*. Välj där din order och klicka på *Open*. Tänd alla plan-*Layers* i ordern, zooma in lämpligt område och dimma kartan vid behov.	

	Gå till *Bookmarks* och öppna egen *Bookmark Folder* och klicka på ikonen *Create Bookmark*. Döp din *Bookmark* till **Opo** och klicka på *Create*.	
5	Öppna *Bookmark* **Gränser** kontrollera i *Pictures* vilka *Layers* som är tända. Öppna därefter egen *Bookmark* **OpO** och kontrollera i *Pictures* vilka *Layers* som är tända.	
6	Uppdatera *Bookmark* Oporder genom att ta bort **Målbild** och byta karta. **Tips:** Börja med att i *Pictures* släcka lager **Målbild** och därefter byta karta i *Base Map* för att slutligen gå till *Bookmark* **OpO** och högerklicka och välja *Update*.	

Övning 11: Presentation

Anvisning	15.5. Presentationsverktyg

Mom	Verksamhet	Klart
1	Förbered en presentation med stöd av *Presentation Tool*. Använd din *Bookmark* **OpO.**	
	a. Välj en stor gul cirkel.	
	b. Välj en tjock röd linje med 20 s varaktighet.	
2	Prova att nyttja valda inställningar, kontrollera att linjen försvinner.	

Övning 12: ORBAT

Anvisning	6.7. ORBAT Editor

Mom	Verksamhet	Klart
1	Öppna *ORBAT Editor*	
2	Gör en ORBAT för egen HV-bat och döp den till egen anropssignal. Hämta förband från ORBAT FM. **Tips:** Klicka på *Create ORBAT* och namnge ORBAT till UTB HVbat. Klicka *Create*. Öppna aktuell blå ORBAT i det vänstra fönstret (*ORBAT*). Ha båda fönstren öppna (*ORBAT* och *ORBAT Editor*) hela tiden. I *ORBAT Editor*-fönstret klicka på *Create Unit*, döp symbolen till HVbat-UTB, gör den till *unit*, storlek *Bataljon* och *Headquarters Staff* och avsluta med *Create*. Nyttja ”*drag and drop”* för att dra förbanden från *ORBAT*-fönstret till symbolen för HVbat i *ORBAT Editor*-fönstret. Ha tålamod, det tar en stund innan de syns i *ORBAT Editor*-fönstret.	
4	Klicka på *Map* (alternativt *Current Operations*) för att öppna och kontrollera egen ORBAT i *Organisation Viewer*.	

Övning 13: Forms

Anvisning	14. IRIS FORMS

Mom	Verksamhet	Klart
1	Skapa en *Forms*-rapport (*Own sitrep*) från eget *Layer* **DUC**. **Tips:** Detta görs genom att i *Pictures* högerklicka på eget *Layer* **DUC** och välj *Export to Structured Message*. Välj *OWNSITREP* och klicka på *OK*.	
2	Byt *Reporting Unit* till egen anropssignal och spara rapporten på Gemensam/Utbildning. **Tips:** Byt status till *Edit*. Gå till fält *3 Reporting Unit*, skriv in din anropssignal. Klicka på *Validate* för att kontrollera att rapporten är korrekt ifylld. Byt status till *Read* samt klicka på *Save As* och välj *Save As Local File*. Filen finns nu i *Download*s och kan flyttas till Gemensam/Utbildning.	
3	Skapa ett *Layer* **egen anropssignal +Lägesrapport** (exvis AA60	

	Lägesrapport) i egen mapp i *Pictures*. **Tips:** Gå till *Current Operations* öppna *Pictures* och tidigare skapad mapp. Högerklicka på egen mapp och välj *Create Layer*.	
4	Öppna egen *Forms*-rapport från Gemensam/Utbildning. **Tips:** Öppna *Forms* och välj *Open* och *Open Local File*. Markera egen fil från Gemensam/Utbildning.	
5	Importera Forms-rapporten till eget lager **egen anropssignal +Lägesrapport**. **Tips:** När egen forms-rapport är öppnad välj *Import to Map*. Scrolla i *Select Target Layer* och välj eget *Layer* och klicka *OK*.	

6	Kontrollera att förbandssymbolerna nu finns i eget *Layer* **egen anropssignal +Lägesrapport**. **Tips:** I *Pictures* släcks alla andra *Layers* utom eget *Layer*.	
7	Skapa en daglig förbandsrapport i *Forms* från mallen *Unit Report*. **Tips:** I *Forms* gå till *New* och välj *Unit Report*. För att snabbt hitta mallen skriv *Unit Report* i sökfältet. Fyll i rubrik 1 och 2.1. Validera därefter rapporten. Scrolla igenom validerings-kommentarerna.	
8	Spara utkastet till daglig förbandsrapport (*Unit Report*) på Gemensam/Utbildning. **Tips:** Gå till *Save As* och välj *Save As Local File*. Filen finns nu i *Download*s och kan flyttas till Gemensam/Utbildning.	

Övning 14: Övrigt avancerat

Anvisning	15.6. Smart Layers

Mom	Verksamhet	Klart
1	Skapa ett *Smart Layer* och döp det till din anropssignal:	
	a. Välj dina egna *Layers* som källa	
	b. Välj att valt *Layer* bara ska visa egna bataljonssymboler	
2	Aggregera egna förband enligt följande:	
	a. Skapa ett nytt *Layer* och döp det till **egen anropssignal + Aggregering**	
	b. Kopiera bataljonssymbolen från eget *Layer* DUC till aggregerings-*Layer*.	
	c. Aggregera den bataljonens alla kompanisymboler från eget *Layer* DUC till bataljonssymbolen i aggregerings-*Layer*.	
	d. Flytta kompanisymbolerna i eget Layer DUC och kontrollera att bataljonssymbolen i aggregerings-*Layer* flyttar sig.	
3	Korrelera motståndarförband enligt följande:	
	a. Skapa ett nytt Layer och döp det till **egen anropssignal + Korrelering**	
	b. Lägg in fyra motståndarförband inom ett begränsat område.	
	c. Välj ett av dessa förband och välj att korrelera övriga förband till detta förband.	
	d. Kontrollera vilka korreleringsverktyg som finns i tabellen.	

Gränssnittstest

1. Fyll i rätt nummer i tabellen för respektive app.

Nr	App
	GEO-TOOLS
	ORGANISATION VIEWER
	LAYER CONTENTS
	GPX-TRACES
	PRINT MAP
	BASE MAP
	SYMBOL TOOLBOX
	BOOKMARKS
	TRACK HISTORY
	PICTURES
	VIDEO BROWSER
	VIDEO PLAYER
	REPLAY
	ATO VIEWER

Nr	App
	TOGGLE 3D MODE
	ZOOM OUT
	ADJUST DIM
	AREA ZOOM
	TOGGLE MINI MAP
	ZOOM IN
	SELECT OBJECTS IN AREA
	TOGGLE GRID

Nr	App
	SEARCH
	SPLIT VIEW
	SETTINGS
	HELP
	NOTIFICATIONS
	PRESENTATION TOOL

Nr	App
	ORBAT EDITOR
	FORMS
	HOLDINGS
	MAP
	CHAT
	JOURNAL

Nr	App
	PLAN BROWSER
	JOURNAL
	MAP
	CHAT
	ORGANISATION EDITOR
	COLLABORATIVE TEXT EDITOR
	PLAN OVERVIEW
	HOLDINGS
	SYNCRONISATION MATRIX
	FORMS

Begrepp

Begrepp	Förklaring
Informationsprodukter	I denna instruktion används Informationsprodukter som ett samlingsbegrepp för den data som importeras in i ISHv såsom ORBAT, Bookmarks, Pictures and Layers, Plans & Orders-mallar, Holding Types, FORMS-mallar et cetera.
IMPEX	Enligt H Nomen Led 2016: Import- och exportfunktion för filer i ett säkerhetsklassat system. Import och export är en funktion för att ta ut och ta in information, det kan vara med stöd av applikationer, hårdvara eller med administrativa metoder.
Metadata	Med metadata avses strukturerad information som beskriver, förklarar, lokaliserar eller på annat sätt underlättar åtkomst, användning eller administration av informationsresurser. Metadata kallas ofta data om data eller information om information. Enligt H Nomen Led 2016: Data om data. Beskriver till exempel ett dokument om vem som skapat det och när det är skapat samt modifierat.
Stabsapplikationer	Digitala applikationer (program) i informationssystemet ISHv som nyttjas av stabsmedlemmar för att stödja stabstjänstarbetet såsom planering, genomförandeledning, uppföljning, utvärdering, et cetera.
Operationsorder (OpO)	Operationsorder, den order högre chef (Regional stab) ger ut som insatsorder till exempelvis Hemvärnsförband.
Bataljonsorder (BatO)	Bataljonsorder är den insatsorder som bataljonsstaben ger till sina DUC.
Stående order (SO)	Enl H Stabstj G: Stående order (SO) utarbetas och används för att man ska förenkla verksamheten inom respektive förband. I stående order sammanförs bestämmelser avsedda att gälla under längre tid, oberoende av hur övrig verksamhet kommer att bedrivas. Innehållet ska vara av rutinkaraktär. Denna typ av order ska vara skriftlig.
Stående Stabsorder SSO	Enl H Stabstj G: Stående stabsorder (SSO) utarbetas och används för att man ska förenkla verksamheten inom staben. I stående order sammanförs bestämmelser avsedda att gälla under längre tid, oberoende av hur övrig verksamhet kommer att bedrivas. Innehållet ska vara av rutinkaraktär. Denna typ av order ska vara skriftlig.
Chefsomgång (L1)	Chefsomgång är en främre ledningsplats med förbandschef och för uppgiften erforderlig stabspersonal.
Stabsplats (L3)	Stabsplats L3 är en bakre stabsplats till exempel bataljon där funktionsledning och planering och bedömningar genomförs.

SitaWare HQ	SitaWare HQ är en applikation baserad i servermiljö för lägesuppdatering, planering och orderverk, rapportering, chatt samt verksamhetsverksamhetsjournal.

Redaktionell information

Instruktion SitaWare HQ 6.9 är framtagen av Hemvärnets Stridsskola.

Den här versionen är första utgivna versionen av Instruktion SitaWare HQ men utgår ifrån tidigare Direktiv IS HV Användare [FM2019-1048:3]. Observera att direktivet inte är fastställt. Instruktionen är avsedd att ersätta direktivet.

Redaktör för instruktionen är RO/major Wilhelm Glatz.

En granskning genomfördes under tidsperioden 2023-12-12 till 2024-03-22. Granskningsutskicket hittas i VIDAR med handlingsnummer FM2023-15396:2

Svar med förslag på justeringar inkom från MR S, MR N, MR V, P 18, FRO och RHS.

Instruktionen är fastställd av C HvSS som fick den fick den föredragen 2024-01-15.

Bildförteckning

Den här publikationen innehåller inga bilder med verkshöjd.

Figur 1 Startsida ISHv....8
Figur 2 Flik för Current Operations....9
Figur 3 Flik för Plans & Orders....9
Figur 4 Flik för Management....9
Figur 5 Aktiverande av hjälpfunktionen....10
Figur 6 Hjälpfunktionen....10
Figur 7 Gränssnitt för Current Operations....11
Figur 8 Gränssnitt för Plans & Orders....11
Figur 9 Val under Settings....13
Figur 10 Rekommenderade inställningar för General....13
Figur 11 Rekommenderade inställningar för Symbols....14
Figur 12 Rekommenderade inställningar för Labels....15
Figur 13 Rekommenderade inställningar för Geo Tools....15
Figur 14 Rekommenderade inställningar för Bookmarks....16
Figur 15 Möjliga val under Notifications....16
Figur 16 Visar aktuell organisation....17
Figur 17 Visar den organisation som innehåller Holdings....17
Figur 18 Val av Base Map och exempel på olika karttyper....18
Figur 19 Val av Management och Maps and Overlays i SitaWare HQ....19
Figur 20 Val av Clip & Ship....19
Figur 21 Meny för Add Job och Export Map....20
Figur 22 Meny för att välja karta och döpa karta....20
Figur 23 Valda Scale Level och valda kartområden....21
Figur 24 Karta redo att processas....21
Figur 25 Sökväg till Nanomap....22
Figur 26 Mappstruktur i Nanomap med csmap....22
Figur 27 Skapa en snabbväg till csmap....23
Figur 28 Exempel på Layers....24
Figur 29 Aktivera ett Layer....25
Figur 30 Fastställda Pictures i ISHv....28
Figur 31 Ikon för att skapa ny Picture....29
Figur 32 Meny för att döpa och skapa en Picture....29
Figur 33 Skapad Picture utan några Layers....29
Figur 34 Ta bort en Picture från aktuell vy....30
Figur 35 Ikon för att öppna en Picture....30
Figur 36 Meny för att välja vilken typ av Picture som skall öppnas....30
Figur 37 Val av Pictures som skall öppnas....31
Figur 38 Folder struktur i Plans & Orders....31
Figur 39 Vald order vars Picture skall öppnas....31
Figur 40 Öppnad Picture med Plan Layers....32
Figur 41 Öppna ett Layer i en Picture....32
Figur 42 Val av Layers som skall öppnas i en Picture....33
Figur 43 Picture med öppnade Layers, ett Plan Layer och ett Operational Layer....33
Figur 44 Layers hanteraren och aktivera ett Layers....34

Figur 45 Meny för att skapa nytt Layer....34
Figur 46 Formulär för att skapa ett nytt Layer. 35
Figur 47 Layershanteraren och Layer Contents....36
Figur 48 Layer contents med lista över UPK. 36
Figur 49 Dialogruta vid öppnande av Picture med Private Layers. 37
Figur 50 Placering av förband från ORBAT. 39
Figur 51 Report Dialog för egna förband....40
Figur 52 Både Layer O01 och O02 tända och synliga. 41
Figur 53 Meny efter högerklick på förbandssymbolen. 41
Figur 54 Markerad underenheter vid aggregering. 42
Figur 55 Förbandsinformationsfält efter vald aggregering....42
Figur 56 Aggregeringsikon med antal underenheter....43
Figur 57 Hantering av övriga kartsymboler. 44
Figur 58 Exempel på sökning av symboler med svenskt namn respektive engelskt namn. 44
Figur 59 Exempel på sökning av symboler utifrån tillhörighet. 45
Figur 60 Flytta kartsymboler med Select Objects in Area. 45
Figur 61 Flytta flera kartsymboler samtidigt....46
Figur 62 Flytta kartsymboler med koordinater....47
Figur 63 Kopieringsordning. 48
Figur 64 Markerade symboler för kopiering. 48
Figur 65 Dialogruta för att välja Layer att kopiera till....49
Figur 66 Öppna ORBAT Editor. 50
Figur 67 Skapa ett förband i ORBAT Editor....50
Figur 68 Skapa en underenhet i ORBAT Editor....50
Figur 69 Egenskaper för ett förband i ORBAT Editor....51
Figur 70 Skapat förband i ORBAT Editor. 51
Figur 71 Meny för att skapa underenheter. 52
Figur 72 Skapad underenhet....52
Figur 73 Öppna en befintlig ORBAT. 53
Figur 74 Befintliga ORBAT i SitaWare HQ. 53
Figur 75 Skapa enheter med "drag and drop"....54
Figur 76 Egenbyggd ORBAT öppnad i Organisation Viewer....54
Figur 77 Byt namn på symbolen för korreleringen....58
Figur 78 Uppdatering av Bookmarks....60
Figur 79 Export till Powerpoint....61
Figur 80 Utskrift från SitaWare HQ. 62
Figur 81 Flerutskrift över större område i SitaWare HQ. 64
Figur 82 Adjust Dim och Toggle Grid vid utskrift av Oleat. 65
Figur 83 Utskrift av UPK som oleat. 65
Figur 84 Utskrift av UPK som oleat. 66
Figur 85 Kopiera Layers vid export....67
Figur 86 Klistra in Layers till Export-Picture....68
Figur 87 Dialogruta vid byte av Layersnamn. 68
Figur 88 Exportera ett Layers....69
Figur 89 Import av ett Layers....70
Figur 90 Verksamhetsjournalen i SitaWare HQ. 71
Figur 91 Skriva ut verksamhetsjournalen....73
Figur 92 Skriva ut eller kopiera verksamhetsjournalen. 73
Figur 93 Sortera information i verksamhetsjournalen....74

Figur 94 Dialogrutan ”Sort” i verksamhetsjournalen. 74
Figur 95 Gruppera information i verksamhetsjournalen. 75
Figur 96 Information sorterad i grupper i verksamhetsjournalen. 75
Figur 97 Lägga till och ta bort kolumner i verksamhetsjournalen. 76
Figur 98 Kontrollera Holdings. 78
Figur 99 Hitta inställningar för Organization. 78
Figur 100 Välj din förbandsstruktur i Current Organization. 79
Figur 101 Välj din förbandsstruktur i Current Organization. 79
Figur 102 Välj dina tilldelade reurser i Holding reference. 80
Figur 103 Spara dina inställningar i Organization settings. 80
Figur 104 Tilldela egna förband sina resurser i Holdings Template. 80
Figur 105 Tilldela resurser till egna förband. 81
Figur 106 Aktivera tilldelad resurs för dina förband. 82
Figur 107 Holding Overviews efter att ha tilldelat sina resurser. 82
Figur 108 Uppdatera underhållsläget i Holdings Overview. 83
Figur 109 Underhållsläget i Holdings Overview. 83
Figur 110 Underhållsläge på lägeskartan. 84
Figur 111 Underhållsläge på lägeskartan. 84
Figur 112 Exportera underhållsläget till Excel. 85
Figur 113 Exempel på när underhållsläget har exporterats till Excel. 85
Figur 114 Administrate Holding Types. 86
Figur 115 ORBAT Editor. 86
Figur 116 Holding Templates. 86
Figur 117 Holding Overview. 87
Figur 118 Visa aktuellt stridsvärde. 88
Figur 119 Skifta till Plans & Orders. 90
Figur 120 Ny order skapas från mall. 90
Figur 121 Folder för mallar. 91
Figur 122 Val av ny order med interna bilagor. 91
Figur 123 Egenskaper för en ny order. 92
Figur 124 Spara ny plan/order 93
Figur 125 Ny order med textdokument Huvuddokument. 93
Figur 126 Öppnat Huvuddokument. 94
Figur 127 Lägga till Layers till en order. 94
Figur 128 Plan Layers hantering i kartan. 95
Figur 129 Lägga till filer till en order. 95
Figur 130 Status översikt för orderpunkter. 96
Figur 131 Statusändring för ingående orderdelar. 96
Figur 132 Val av status inför genomläsning och godkännande. 97
Figur 133 Val av status när ordern är godkänd. 97
Figur 134 Status när ordern skall verkställas och bli gällande. 98
Figur 135 Val av status Cancelled för en order med status Issued. 98
Figur 136 Export av en order alternativ 1. 99
Figur 137 Export av en order alternativ 2. 99
Figur 138 Import av order. 99
Figur 139 Dialogruta vid Import. 100
Figur 140 Flytta en order till annan Folder. 100
Figur 141 Inkommen lägesrapport i Utforskaren. 101
Figur 142 Import fönster. 101

Figur 143 Importerad lägesrapport från Frontline. 101
Figur 144 Öppnat lägesrapport Layer i kartvyn. 102
Figur 145 Öppnad textdel till en lägesrapport från kompani. 102
Figur 146 Startikon för FORMS och hjälpfunktion i FORMS. 103
Figur 147 Meny för att skapa ny eller öppna en FORMS rapport. 103
Figur 148 Lista med tillgängliga FORMS rapporter. 104
Figur 149 Sökruta för FORMS rapporter. 104
Figur 150 Öppnad tom FORMS rapport. 105
Figur 151 FORMS rapport med tvingande fält. 105
Figur 152 Hjälpfunktion för ett FORMS fält. 106
Figur 153 Platsmarkör i FORMS. 106
Figur 154 Vald plats i kartvyn. 106
Figur 155 Val av plats i kartvyn. 106
Figur 156 Infogade koordinater i FORMS-rapporten. 107
Figur 157 Funktion för att validera en FORMS rapport. 107
Figur 158 Validerad FORMS rapport. 107
Figur 159 Ej korrekt ifyllt fält. 107
Figur 160 Lista med upptäckta fel. 107
Figur 161 Rapporten i Read. 108
Figur 162 Funktion för att visa data i en FORMS rapport. 108
Figur 163 Data i en FORMS rapport. 109
Figur 164 Gråmarkerad paragraf som görs aktiv. 109
Figur 165 Spara rapport lokalt. 109
Figur 166 Nedsparad rapport i Hämtade filer. 109
Figur 167 Öppna en lokalt sparad FORMS rapport. 110
Figur 168 Möjliga FORMS rapporter. 111
Figur 169 Skapad rapport från ett Layer med kommentarer. 111
Figur 170 Meny för att öppna en FORMS rapport i ett Layer. 112
Figur 171 Gränssnitt för IRIS administration. 112
Figur 172 Meny för import av FORMS mallar. 113
Figur 173 Import av FORMS-mallar. 113
Figur 174 Val av vilka mallar som skall vara tillgängliga då man skapar nya rapporter. 114
Figur 175 Geoverktyg i SitaWare HQ. 115
Figur 176 Söka efter och konvertera koordinat. 116
Figur 177 Sökfunktionen med platser och kartsymboler. 117
Figur 178 Split Screen finns i övre högra hörnet. 118
Figur 179 Exempel på Split Screen med lägeskarta och verksamhetsjournal. 118
Figur 180 Meny för Presentation Tool. 119
Figur 181 Presentations "ficklampa". 119
Figur 182 Presentationsstreck. 120
Figur 183 Exempel på en Picture för gemensamma Smart Layers. 121
Figur 184 Skapa Smart Layers. 121
Figur 185 Exempel på namngivning av Smart Layers. 122
Figur 186 Val av Layer. 122
Figur 187 Val av nod. 123
Figur 188 Select Source Layers. 123
Figur 189 Manage Sources. 124
Figur 190 Smart Layer Properties. 124
Figur 191 Information om positionsändring. 125

Figur 192 loggning av händelse. 125
Figur 193 Område Smart Layer. 126
Figur 194 Create Smart Layer. 126
Figur 195 Exempel på namngivning av Smart Layer. 127
Figur 196 Filter. 127
Figur 197 Val av område. 128
Figur 198 Kvittens av valt område i Smart Layer. 128

Tabellförteckning

Tabell 1 Ikoner som kan förekomma i SitaWare HQ. 27
Tabell 2: Information till utskrift. 63
Tabell 3 Användning av kolumner i verksamhetsjournalen. 72
Tabell 4 Färgkoderna i relation till mängd. 83
Tabell 5 Ifyllande av stridsvärdesrapport. 89
Tabell 6 Fält som fylls i när en order skapas i Plans & Orders. 92

Källförteckning

I den här versionen av instruktionen har följande källor använts:

Källor utanför Försvarsmakten
NATO JOINT SYMBOLOGYAPP-6
US MIL-STD-2525C
User Manual for SitaWare HQ ver 6.9

Källor inom Försvarsmakten
Instruktion ISHv Gemensamma funktioner 2025

Regler, bestämmelser och handböcker som påverkat innehållet i denna instruktion

Handbok	Handbok ISHv Stabstjänst 2025 (H ISHv Stabstj 2025)
	Handbok Gemensamma symboler 2019 (H GEM SYMB 2019)