INSTRUKTION ISHV FRONTLINE 2.3 2025

INTRODUKTION

Denna instruktion beskriver det praktiska användandet av stabsapplikation Frontline som finns i ISHv på kompaninivån. Målgruppen är Hemvärnskompanichefer med kompaniledningar.

Instruktionen är en del av en serie instruktioner som HvSS tagit fram för att stödja militärregionerna samt hemvärnskompani- och bataljonsstaber i nyttjandet av ISHv.

Då innehållet kan komma att påverkas av systemuppdateringar av ISHv programvara ges dessa texter ut som instruktioner. Notera att instruktioner inte är en publikationstyp och att de därmed inte kommer ha en förrådsbeteckning eller att tryckas. Vid behov kan instruktionerna skrivas ut från egen skrivare.

Eftersom innehållet är föränderligt är det viktigt att säkerställa att den senaste versionen används. De senaste versionerna av instruktionerna kommer att finnas tillgängliga i VIDAR och på HvSS/UtvE samarbetsyta:
samarbetsytor.emilia.swedi.mil.se/samarbetsytor/hvssutveckling.

Instruktionen gäller i fred och hela konfliktskalan.

Innehållet i denna instruktion omfattas inte av sekretess.

ÄNDRINGAR

Version Instruktion	Ändring nr	Version Programvara	Gäller från	Vidarhandling för beslut	Anmärkning
1.0	0	2.3	2025-02-01	FM2023-15396:3	

Förslag på ändringar och förtydliganden insänds till hvss-utv@mil.se.

ANDRA HJÄLPMEDEL FÖR ISHV-ANVÄNDARE

Denna instruktion kompletteras av följande dokument:

- **Handbok ISHv Stabstjänst 2025** innehåller anvisningar med förklaringar och beskrivningar avseende hur ledningsstödsystemet ISHv kan nyttjas för att stödja stabsarbete. Alla stabsmedlemmar i en Hemvärnsbataljonsstab och militärregionalstab samt hemvärnskompanichefer med kompaniledningar behöver läsa den handboken för att förstå hur handhavandet ska tillämpas kopplat till stabstjänstmetoderna.

- **Instruktion ISHv Gemensamma funktioner 2025** beskriver användandet av de stabsstödsfunktioner som är gemensamma för militärregion, bataljons- och kompaninivå. Alla i kompaniledningen såväl stabsmedlemmar i militärregionstab och bataljonsstab bör läsa denna för att få en komplett förståelse för det egna stabsstödssystemets applikationer.

- **Instruktion ISHv SitaWare HQ 2025** beskriver det praktiska användandet av bataljonsnivåns stabsapplikation SitaWare HQ. Målgruppen är hemvärnsbataljonstaber, militärregionstaber och härvid i första hand stabschef, sektionschefer, stabsassistenter och driftledare vid bataljonsstab. Övriga stabsmedlemmar bör också läsa denna bok så att hela staben får en förståelse för hur ISHv används inom staben.

- Instruktionerna och handboken är komplement till i systemet medföljande **systemböcker ISHv (I-bok och R-bok).**

LÄSANVISNING

Instruktionen är indelad i 10 kapitel.

Kapitel **ett** innehåller grunder ISHv och hur man startar **Frontline**.

Kapitel **två** beskriver hur man får **kartdata** till Frontline samt det övergripande **gränssnittet**.

Kapitel **tre** redogör för vilka **huvudfunktioner** som kan användas i Frontline.

Kapitel **fyra** till och med kapitel **tio** beskriver hur man **praktiskt** kan använda ISHv funktionerna i Frontline.

Beskrivning av användandet av **alla** funktioner i Frontline återfinns i hjälpfunktionen.

Varje användande som beskrivs i denna instruktion är anpassat efter de metoder som är fastställda för Hemvärnet och följer den utbildning som är framtagen av Hemvärnets Stridsskola.

INNEHÅLLSFÖRTECKNING

1 ISHv 7
1.1 Grunder 7
1.2 Start av Frontline 7
2 Frontline grunder 8
2.1 Kartdata till Frontline 8
2.2 Gränssnitt 9
3 ISHv funktioner i Frontline 10
3.1 Allmänt 10
3.2 Anslutningslarm 10
3.3 Huvudfunktioner 11
4 Meny 13
4.1 Rapport 14
4.2 Bokmärken 15
4.3 USB-kopia 16
4.4 Inställningar 17
4.5 Avsluta 18
4.6 Geoverktyg 19
4.7 Om 20
5 Lager 21
6 Kartor 22
7 Planer 24
7.1 Hantera planer/order 24
7.2 Egenskaper för planer/order 25
7.3 Skapa ny plan/order 25
7.4 Hantera lager i planer/order 30
7.5 Rita en ny symbol i ett lager. 31
7.6 Editera en befintlig symbol i ett lager. 35
7.7 Kompaniets nyttjande av Planer 36
8 Stridsledningsoleat 38
9 Symbolfavoriter 39
10 Bokmärken 42

Begrepp 43
Redaktionell information 44
Bildförteckning 44
Tabellförteckning 47
Källförteckning 48

1 ISHV

1.1 Grunder

ISHv är ett informationssystem anpassat för Hemvärnets behov och syftar till att öka Hemvärnets ledningsförmåga på bataljons- och kompaninivå.

Skillnaden mellan bataljonsnivån och kompaninivån är att bataljonsnivån nyttjar stabsstödsapplikationen SitaWare HQ och att kompaninivån nyttjar stabsstödsapplikationen Frontline. Dessa två stabsstödsapplikationer kan med hjälp av import/export funktioner utbyta geografisk lägesinformation samt planer och order. Därutöver skiljer sig antalet klienter och serverlösning. Båda nivåer har en presentationsutrustning som kan stödja vid ordergivningar, föredragningar, orienteringar, et cetera.

ISHv är ackrediterat upp till begränsat hemligt (BH), ingen information med högre klassning får föras in i systemet. Öppen information och annan information som omfattas av annan sekretess enligt Offentlighet- och sekretesslagen (OSL) får hanteras i systemet.

1.2 Start av Frontline

Logga in med TEID-kort och kontrollera att status för Server1 (SRV1) lyser grönt.

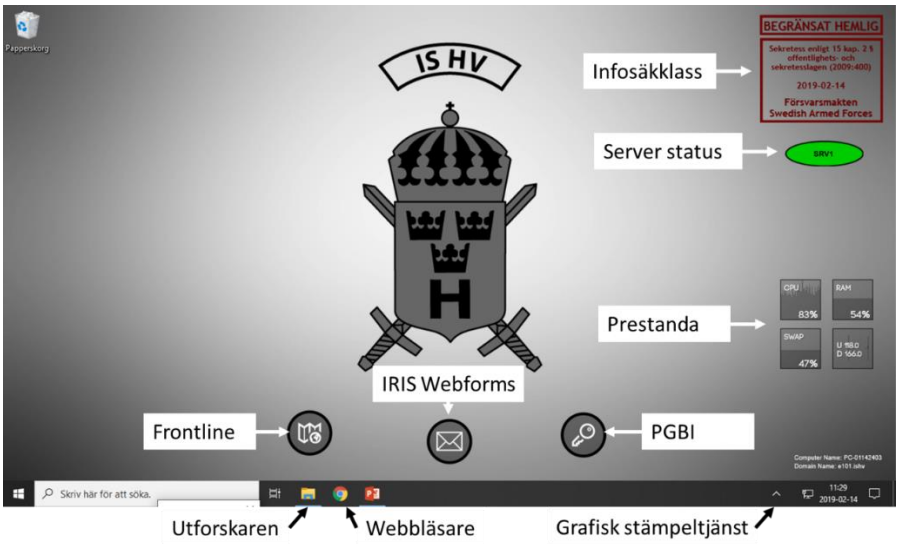

Figur 1 Startbild ISHv kompani.

För att starta Frontline:
Tryck på symbolen Frontline som är den första från vänster till höger av de tre aktiva ikoner som finns på skrivbordet.

2 FRONTLINE GRUNDER

2.1 Kartdata till Frontline

I Frontline finns ett antal grundkartor inlästa. Ifall kompaniet har andra kartbehov anmäls detta till bataljonen som i SitaWare HQ med verktyget *Clip and Ship* kan skapa anpassade kartor. Här finns såväl landkartor som sjökort. Kartfilerna från SitaWare HQ exporteras ut ur SitaWare HQ och skickas till kompaniet via fildelning alternativt via ordonnans med USB-sticka.

Kartfilerna importeras till kompaniklienten och läggs i mappen C:\ *Maps*. Därefter kan kartorna öppnas i Frontline. Se även avsnitt **6 Kartor**.

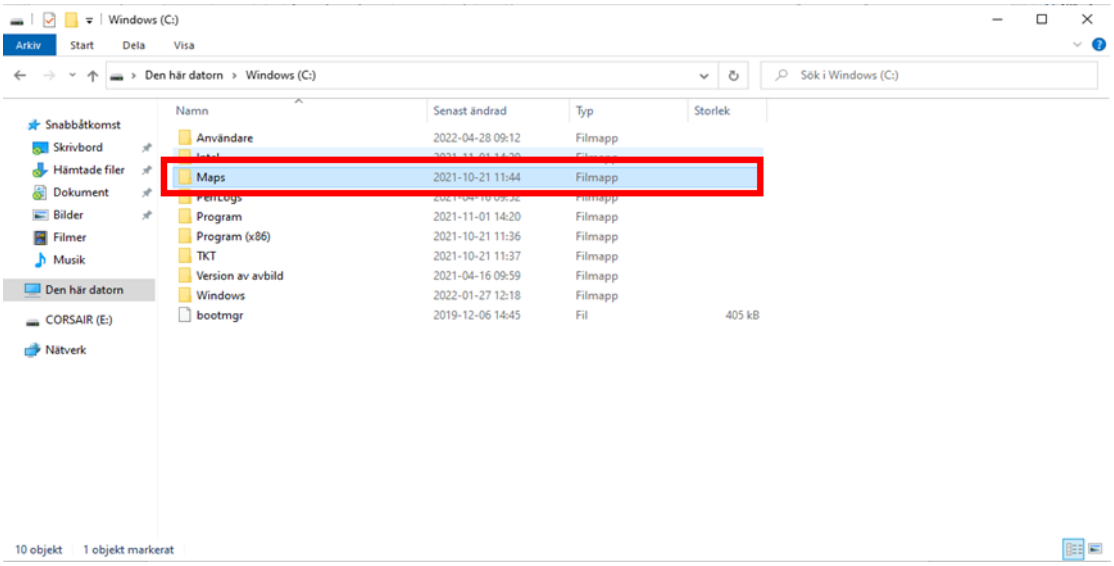

Figur 2 Kartmapp för Frontline på kompaniklienten.

OBSERVERA!
När man i SitaWare HQ via Clip and Ship skapar kartor till Frontline ska höjddata bockas i. Utan höjddata fungerar inte vissa av Frontlines geoverktyg.

2.2 Gränssnitt

Frontlines gränssnitt domineras av ett kartfönster där ISHv-funktionerna i huvudsak återfinns på höger sida.

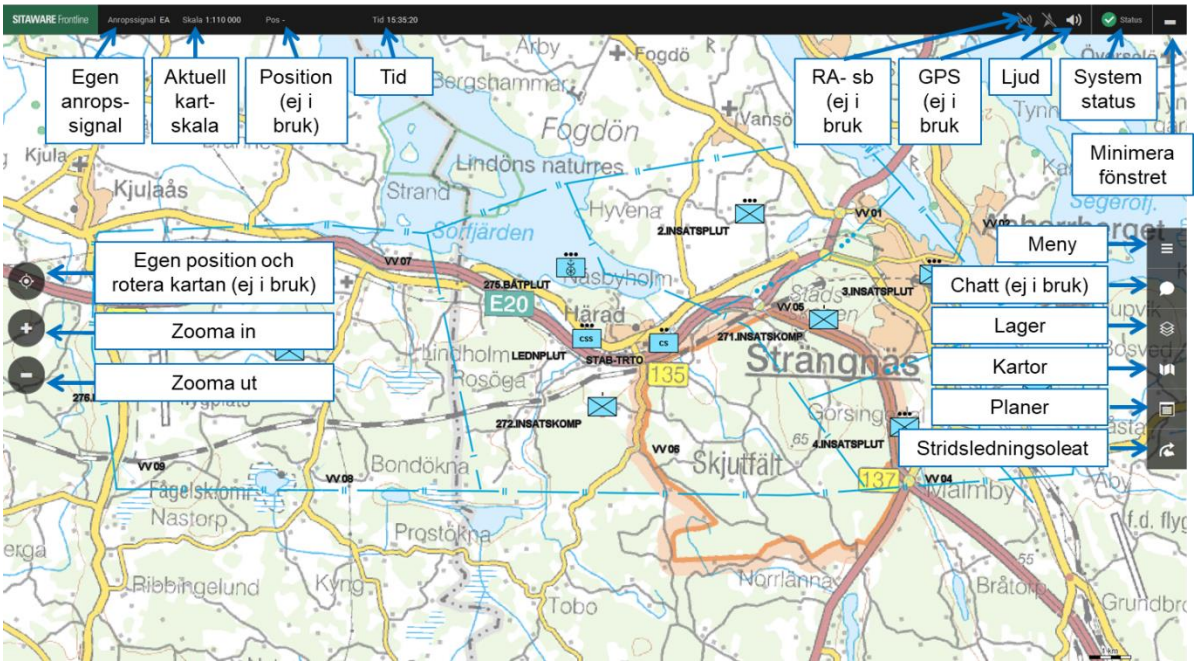

Figur 3 Gränssnitt för Frontline.

I många funktioner där nya fönster öppnas visas nedanstående ikoner.

Ikon	Användning
	Åtgärdsprickar. Klicka på dessa för att få ytterligare val.
	Gå tillbaka. Klicka på denna för att gå tillbaka till tidigare vy inom samma funktion.
	Stäng. Klicka på denna för att stänga aktuell funktion. Jobbar man i en funktion och avser att fortsätta där nyttjas **Gå tillbaka** istället så att man inte måste öppna funktionen igen.

3 ISHV FUNKTIONER I FRONTLINE

3.1 Allmänt

Eftersom Frontline inte är uppkopplad till ett gemensamt nätverk och har därmed någon direkt kommunikation med bataljonens SitaWare HQ eller andra kompaniers Frontline så nyttjas inte alla systemets funktioner.

3.2 Anslutningslarm

I övre högra hörnet finns en status markör som normalt är grön.

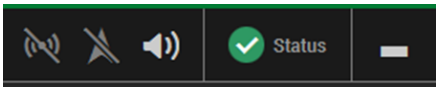

Figur 4 Frontline statusmarkör när statusen är grön.

Lyser markören rött finns det ett fel i systemet, trycker man då på statusknappen kommer en lista där man kan se var felet finns.

+ 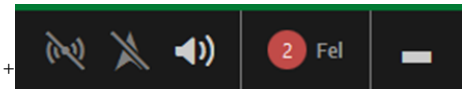

Figur 5 Frontline statusmarkör när fel finns i systemet.

Klickar man på statusmarkören öppnas ett nytt statusfönster. Då visas vad systemet uppfattar som fel.

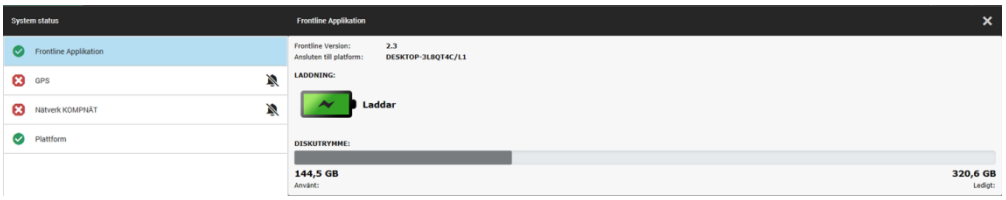

Figur 6 Statusfönster med två fel.

För att återställa statusmarkören till grönt, klicka på felrapporterna så att strecket över larmklockan försvinner och att symbolen blir gul.

Figur 7 Åtgärdade felrapporter.

Det går även att klicka på raden *Frontline Applikation* för att visa detaljer om statusen för Frontline.

Efter dessa åtgärder kommer statusmarkören markera grönt igen. Detta kan ta några minuter innan systemet har uppdaterats.

OBSERVERA!
Eftersom Frontline inte är uppkopplade på ett nätverk eller GPS kan det visas felmeddelanden om detta utan att det påverkar de funktioner som ska användas.

3.3 Huvudfunktioner

På högra sidan av Frontline applikationen återfinns huvuddelen av funktionerna som kompaniet använder. Funktionerna innehåller följande:

Meny

- Innehåller rapportsymboler som kan nyttjas för att följa upp från underställda enheter inrapporterade fiender.
- Bokmärken för att snabbt tända aktuell information.
- Inställningar för symboler och karta.
- Geoverktyg.
- Import/exportfunktion (USB-kopia)
- Avstängningsknappen för Frontline.

Chatt

- Används inte. Istället finns chatten i ISHv-kommunikationstjänsterna.

Lager

- För att tända och släcka *Rapporteringslagret* och *Eget SLO-lager*. Här ritar man inget utan bara tänder och släcker dessa två lager.

Kartor

- I kartor kan man tända, släcka och öppna nya kartor.

Planer

- Skapa nya planer/order.
- Här finns importerade planer/order.
- Här sker huvuddelen av allt ritande i lager.
- Här förs kompaniets lägesbild och lägesrapport.

Stridsledningsoleat

- Kan nyttjas för att rita och följa upp egna händelser och egna särskilda rapporter från underställda enheter.

Under kommande rubriker beskrivs handhavandet av respektive huvudfunktion.

4 MENY

Figur 8 Funktioner under Meny.

I dagsläget finns det ett antal funktioner som inte är i bruk eftersom att Frontline inte har någon nätverksanslutning eller GPS. Nedanstående avsnitt beskriver hur respektive verktyg under *Meny* ska användas. Numreringen på avsnitten utgår från ovanstående bild.

4.1 Rapport

Klicka på *Rapport* för att öppna symbolbiblioteket. Där väljs lämplig symbol och ritas i ett *Rapportlager*.

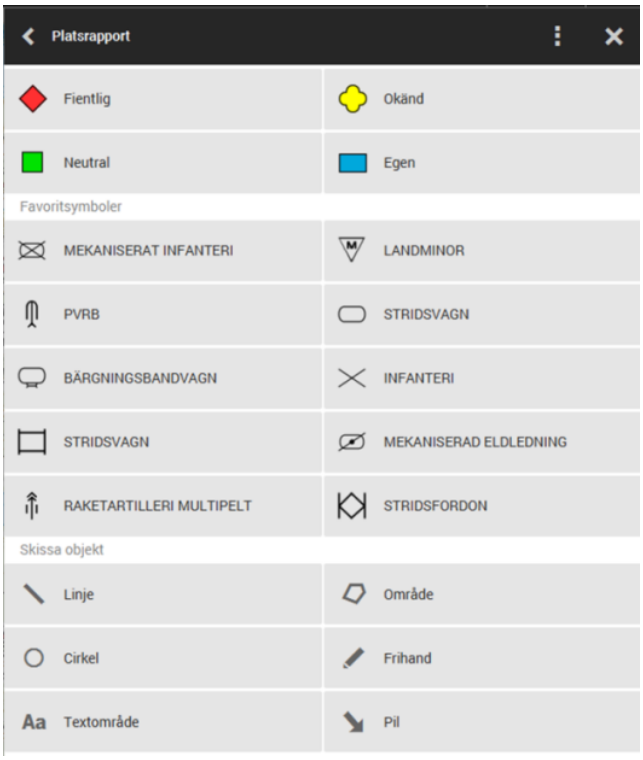

Figur 9 Symbolbibliotek under Rapporter.

För att lägga in symboler i *Rapportlager* väljer man en symbol och placerar den på kartan.

Härvid öppnas *Rapportdetaljer* som fylls i. Klicka därefter på tillbaka pilen för att skapa flera symboler.

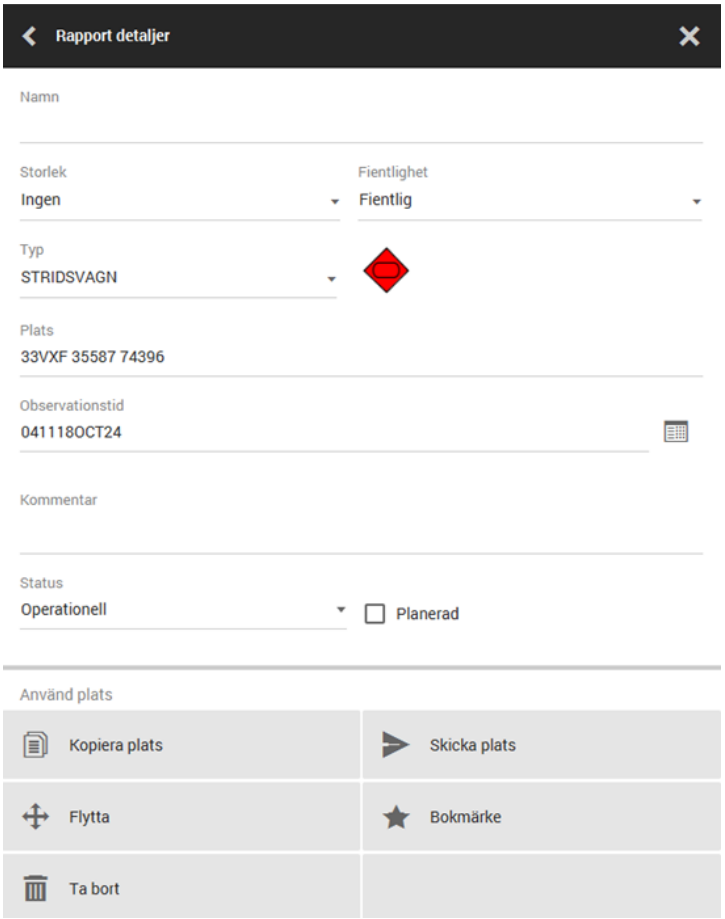

Figur 10 Rapportdetaljer för symboler skapade via Rapporter.

OBSERVERA!
Rapportlagret tänds och släcks via Lager. Se även avsnitt **5 Lager**.

Rapportlager kan nyttjas för att följa upp alla inrapporterade fiendehändelser (5 S) med hjälp av symboler och textrutor.

4.2 Bokmärken

Här visas de *Bokmärken* som skapats i *Rapportlagret* eller i *Planer*. Se även avsnitt **10 Bokmärken**.

4.3 USB-kopia

USB-kopia funktionen nyttjas i första hand för att importera och exportera planer/order. Det går även att importera och exportera kartor, men detta görs vanligtvis via *Clip and Ship* från SitaWare HQ.

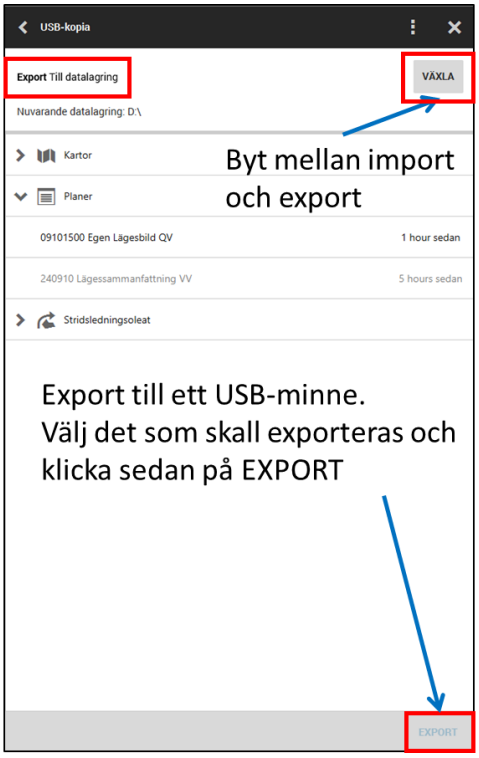

Figur 11 Gränssnitt för USB kopia.

Att importera en plan/order görs enligt följande:

1. Sätt in ett godkänt USB-minne där planen/ordern som ska importeras finns.
2. Öppna *Meny/USB-kopia*.
3. Kontrollera att det står *Import från datalagring*, klicka annars på *Växla*.
4. Klicka på den plan/order som ska importeras och sedan på *IMPORT*.
5. Planen/order finns nu under funktionen *Planer*. Den importerade planen är skrivskyddad men kan kopieras till en egen plan/order. Även text från textdokumentet kan kopieras.

Att exportera en plan/order görs enligt följande:

1. Sätt in ett godkänt USB-minne dit planen/ordern som ska exporteras ska läggas på.
2. Öppna *Meny/USB-kopia*.
3. Kontrollera att det står *Export till datalagring*, klicka annars på *Växla*.
4. Klicka först på den plan/order som ska exporteras och sedan på *EXPORT*.
5. Planen/order finns nu på USB-minnet och kan sparas ner lokalt på datorn för att därefter skickas till anbefalld mottagare.

4.4 Inställningar

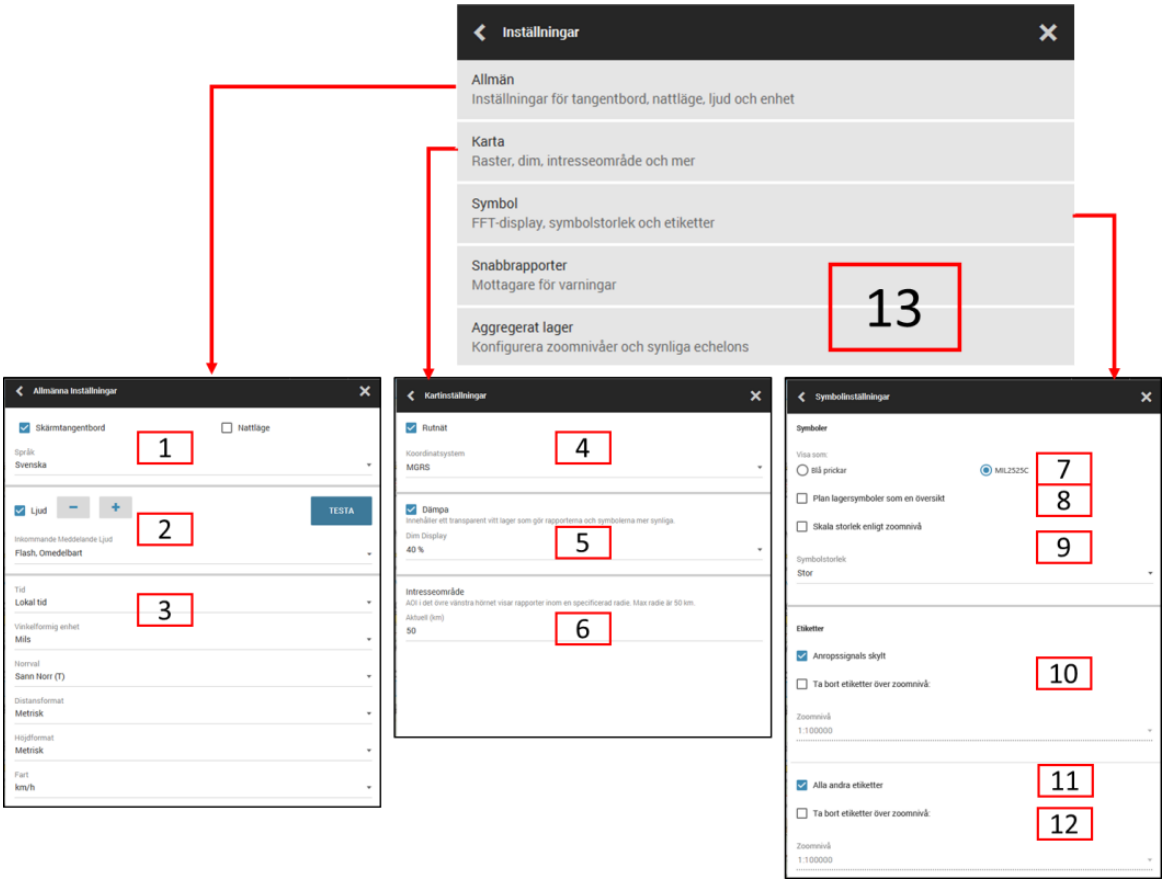

Figur 12 Möjliga inställningar i Frontline.

Nr	Inställning
1	Skärmtangensbord nyttjas bara när man har en touchscreen. Nattläget gör skärmen mörkare.
2	Används inte då det inte kommer några automatiska meddelanden till Frontline.
3	Normalt används lokal tid och Mils. Övrigt är upp till eget val.
4	Tänder och släcker rutnät samt ger möjlighet att välja angivningssätt. I FM är koordinatsystemet MGRS.
5	Ger möjlighet att justera ljusstyrkan på kartan så att symboler ses bättre. Kan justera 10%, 40% eller 75%.
6	Används inte.
7	Normalt ska Mil 2525C vara ikryssad.
8	Alla symboler skapade i *Planer* ritas endast med svart färg. Har man ett *Lager* i *Planer* tänt behöver man släcka det och tända det igen för att valt alternativt ska slå igenom. Ska normalt inte vara ikryssad.
9	Ändrar symbolstorlek beroende på skala. Ifall den inte är ikryssad kan man istället välja symbolstorlek *Stor*, *Medium* eller *Liten*.
10	Används inte.
11	Har man den ikryssad visas namn på symbolen. Bör normalt vara ikryssad.
12	Här kan man välja att symbolnamnet inte syns när man är över en viss skala.
13	Används inte.

Tabell 1 Utvisande inställningsmöjligheter i Inställningar.

4.5 Avsluta

För att avsluta Frontline, välj *Avsluta* under *Meny* och därefter klicka på *Avsluta*.

Figur 13 Dialogruta för att avsluta Frontline.

4.6 Geoverktyg

Geoverktygen *Siktfältsanalys*, *Siktlinjesanalys* och *Högsta punkt* fungerar endast om det finns höjddata inläst. Ifall kartor hämtas från bataljonsstabens SitaWare HQ via Clip and Ship behöver höjddata ha inkluderats i kartan innan den färdigställts.

Geoverktyget tar ingen hänsyn till träd, byggnader eller andra objekt utan utgår från den konkreta höjden på terrängen.

Geoverktyg	
Siktfältsanalys	Används för att kart-rekognosera höjddata inom ett avgränsat område. Lämpligt vid bedömandet av vart man kan placera sambandsutrustning eller beräkna framkomlighet.
Siktlinjesanalys	Används för att kart-rekognosera höjddata över ett visst streck. Lämpligt vid bedömandet av vad en o-plats kan se.
Avstånd/Riktning	Används för att kart-rekognosera avstånd. Lämpligt vid bedömandet av beräknandet av sträckor.
Högsta punkt	Används för att hitta den högsta punkten inom ett område. Lämpligt vid exempelvis gruppering av sambandsutrustning.
Avstånd sektor	Används för att visa en sektor med tre avstånd och valfri vinkel. Lämpligt vid exempelvis för att visa och beräkna eldområden med skjutgränser.
Avstånd ring	Används för att visa en cirkel med fyra avstånd . Lämpligt vid exempelvis för att visa och beräkna eldområden med skjutgränser.
Hitta plats	Används för att utifrån en koordinat hitta en plats.
Alternativ	
Rensa allt	Används för att ta bort alla gjorda geoberäkningar i kartbilden.
Inställningar	Används för att vid mätningar ange observationshöjden och målhöjden.

Figur 14 Geoverktygen och dess användning.

4.7 Om

Under fliken ”Om” visas aktuellt versionsnummer.

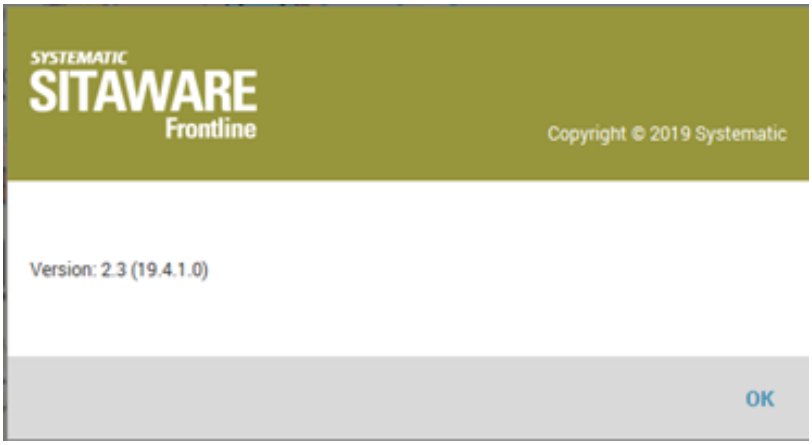

Figur 15 Dialogruta som visar versionsnummer.

5 LAGER

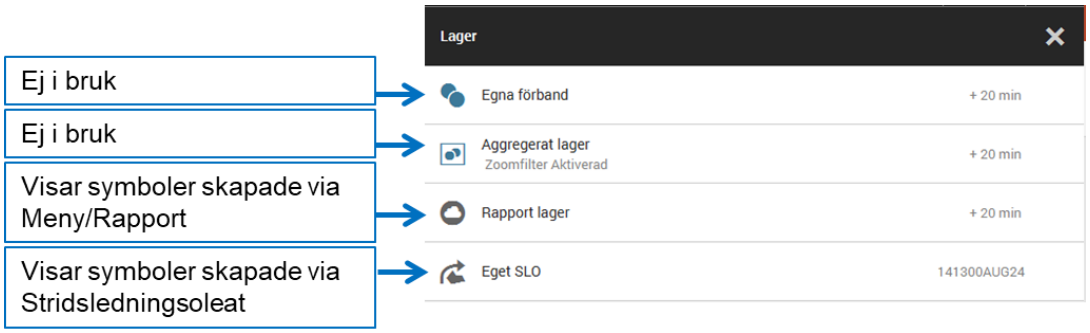

Figur 16 Lager.

Under *Lager* väljer man att visa valda lager på kartan.

I *Rapportlager* återfinns alla symboler som har ritats under *Meny/Rapport*. *Rapportlager* kan nyttjas för att följa upp alla inrapporterade fiende händelser (5 S).

I *Eget SLO* återfinns alla symboler man ritat under funktionen *Stridsledningsoleat*.
Eget SLO kan nyttjas till att följa upp egna händelser och lägesrapporter från underställda enheter.

6 KARTOR

Under *Kartor* kan man välja vilka kartor som ska vara tända eller släckta, radera kartor samt läsa in nya kartor.

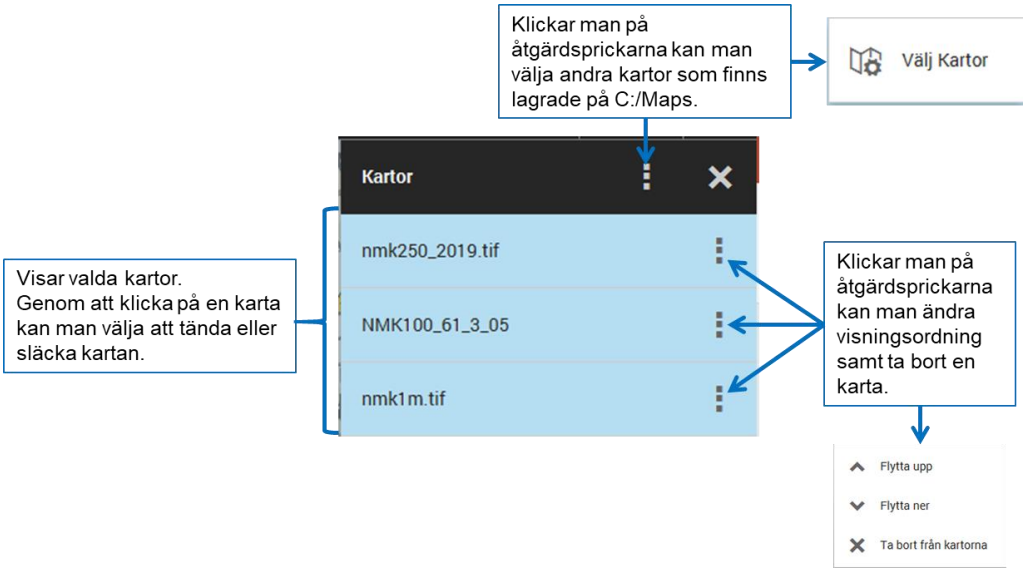

Figur 17 Välja kartor sammanfattning.

Att välja karta görs enligt följande:

1. Öppna *Kartor*.
2. För att byta mellan redan hämtade kartor, klicka på de kartor som finns tillgängliga och tänd eller släck dessa.
3. För att hämta en ny karta, klicka på åtgärdsprickarna för *Kartor* och därefter på *Välj Kartor*.
4. I det fönstret som öppnas visas de kartor som finns under C:Maps. Saknas någon karta klickar man på åtgärdsprickarna och väljer *Uppdatera*.

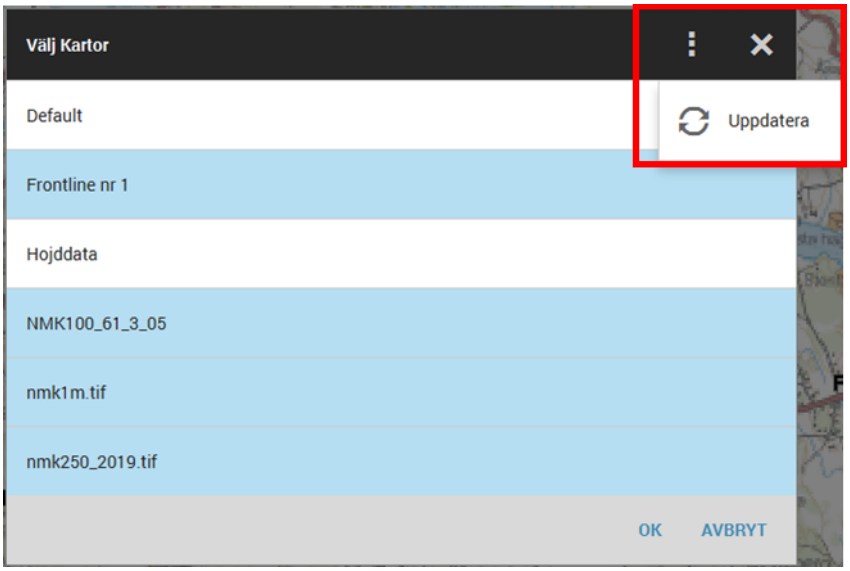

Figur 18 Uppdatering av tillgängliga kartor i C:Maps.

5. Klicka på den eller de kartor som ska läsas in i Frontline och sedan på OK.
6. Nu finns kartorna inlästa i Frontline och kan tändas och släckas via *Kartor*.

Alla kartfiler för Frontline finns under lokal disk C: i mappen *Maps*. När man importerar *Clip and Ship* kartor från bataljonens SitaWare HQ är det i denna mapp som kartorna ska placeras. Detta för att man därefter via åtgärdsprickarna under *Kartor* ska kan läsa in nya kartor i Frontline.

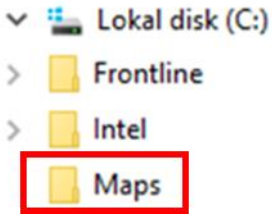

Figur 19 Mapp för kartor i Frontline.

7 PLANER

7.1 Hantera planer/order

Under *Planer* finns alla egenskapade planer/order samt alla via *USB-kopia* importerade planer/order.

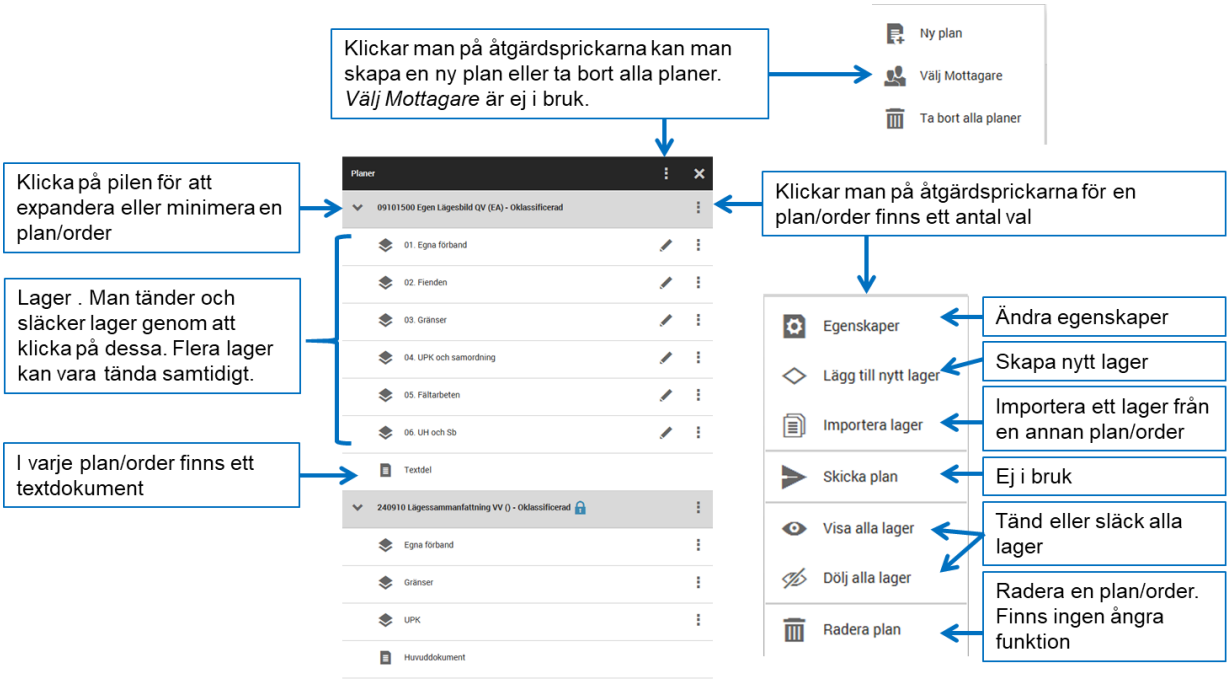

Figur 20 Gränssnitt för Planer.

7.2 Egenskaper för planer/order

När en ny plan/order skapas väljs även egenskaper för planen/ordern. För egenskapade planer/orders kan egenskaperna redigeras efter hand.

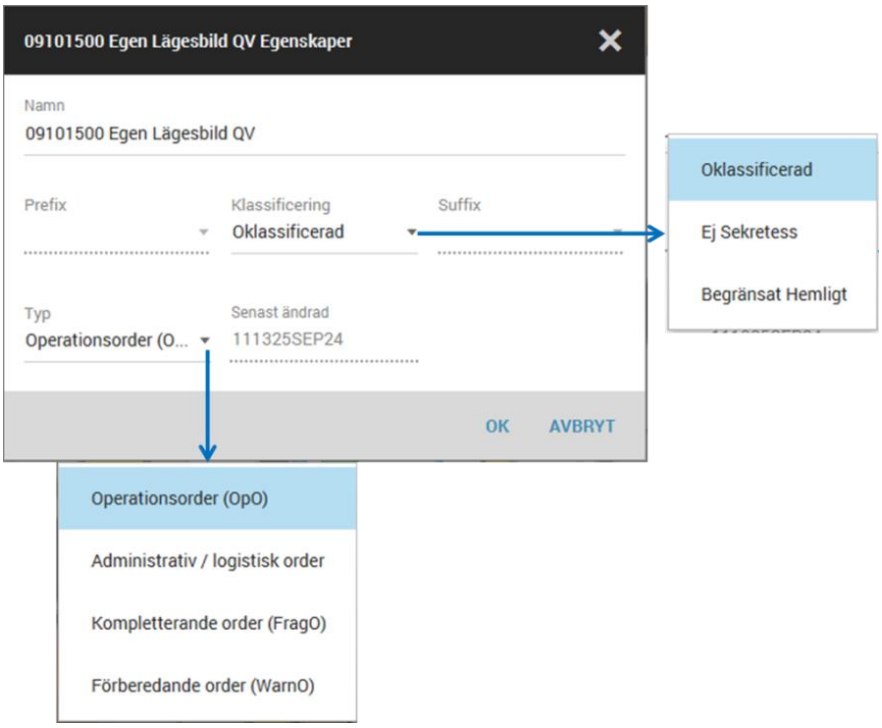

Figur 21 Egenskaper för en plan/order.

7.3 Skapa ny plan/order

Att skapa en plan/order görs enligt följande:

1. Öppna *Planer*.
2. Klicka på åtgärdsprickarna och välj *Ny plan*.

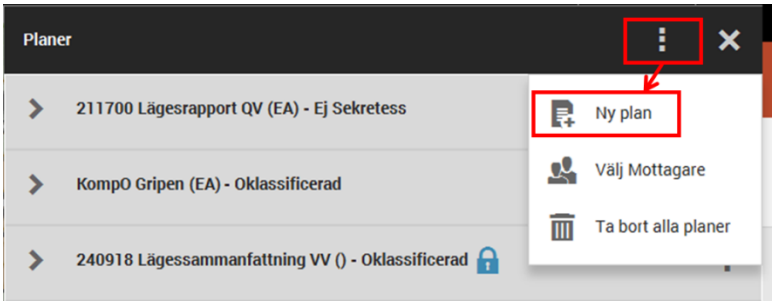

Figur 22 Åtgärdsprickar och meny för ny plan.

3. Namnge ordern, välj klassificering och typ av plan/order. Avsluta med *OK*.

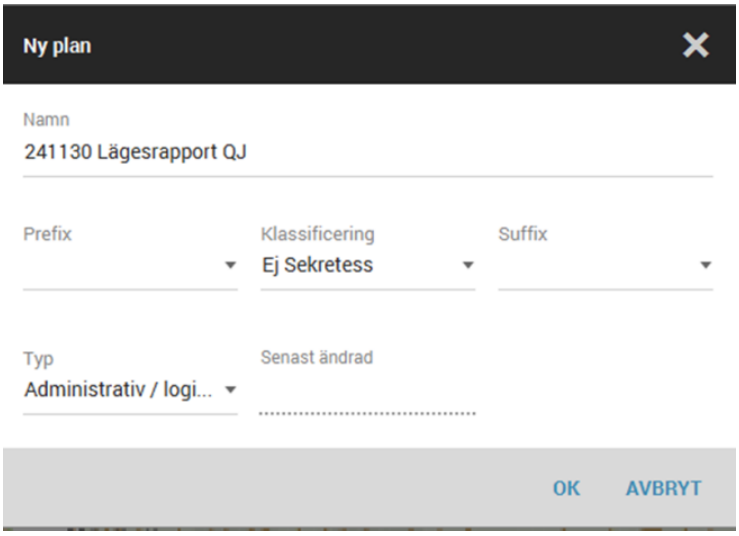

Figur 23 Egenskaper för en ny plan/order.

4. Frontline skapar automatiskt ett lager med samma namn som planen/ordern. Döp om detta lager genom att klicka på åtgärdsprickarna och välja *Byt namn på lager*.

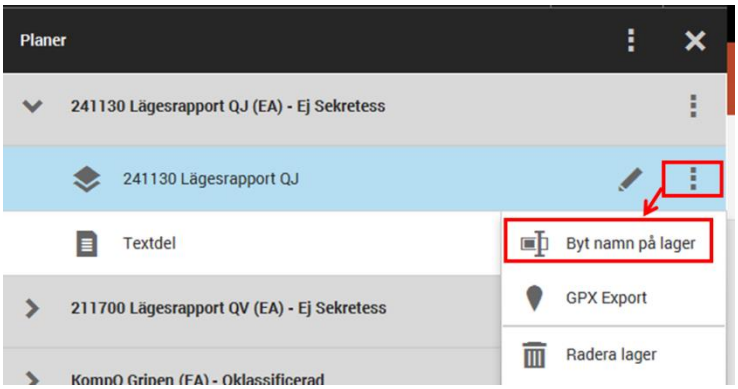

Figur 24 Meny för att byta namn på ett lager.

5. Vid behov kan flera lager läggas till genom att klicka på åtgärdsprickarna för aktuell plan och välja *Lägg till nytt lager*.

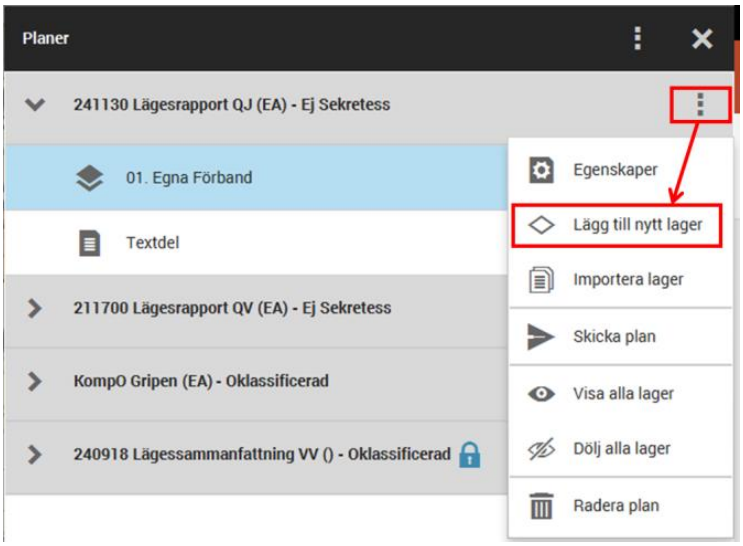

Figur 25 Lägga till ett nytt lager till en plan.

6. Både egenskapade och importerade lager kan kopieras från en annan plan. Klicka på åtgärdsprickarna för aktuell plan och välj *Importera lager*.
7. Då öppnas ett fönster där man kan välja vilken plan man vill kopiera ett lager ifrån.

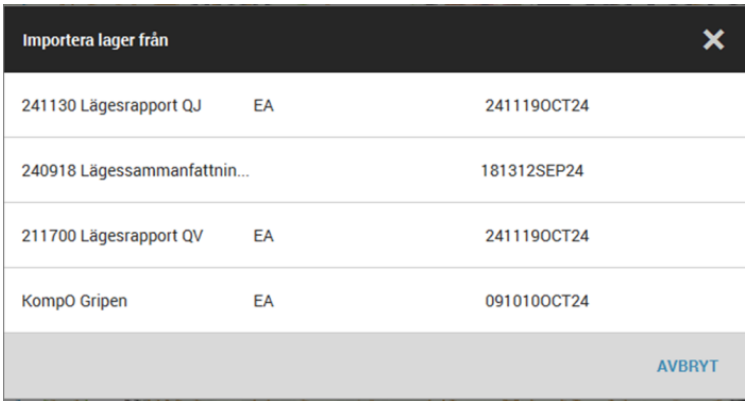

Figur 26 Val av plan för import av lager.

8. Välj en plan och därefter välj vilket lager som ska importeras till den nya planen.

Figur 27 Val av lager för att importera ett lager.

9. Efter att ha valt lager, klicka på *OK* för att lagret ska importeras till planen.
10. Därefter kan man via lagrets åtgärdsprickar döpa om lagret så att det passar den nya planens struktur.

Figur 28 Åtgärdsprickar för att döpa om ett lager.

11. När man skapat nödvändiga lager kan man lägga in symboler i respektive lager. Detta beskrivs i avsnitt **7.5 Rita en ny symbol i ett lager.**
12. Öppna därefter textdokumentet och skriv in relevant text. Det går att kopiera text från ett Office-dokument och klistra in i textdokumentet.

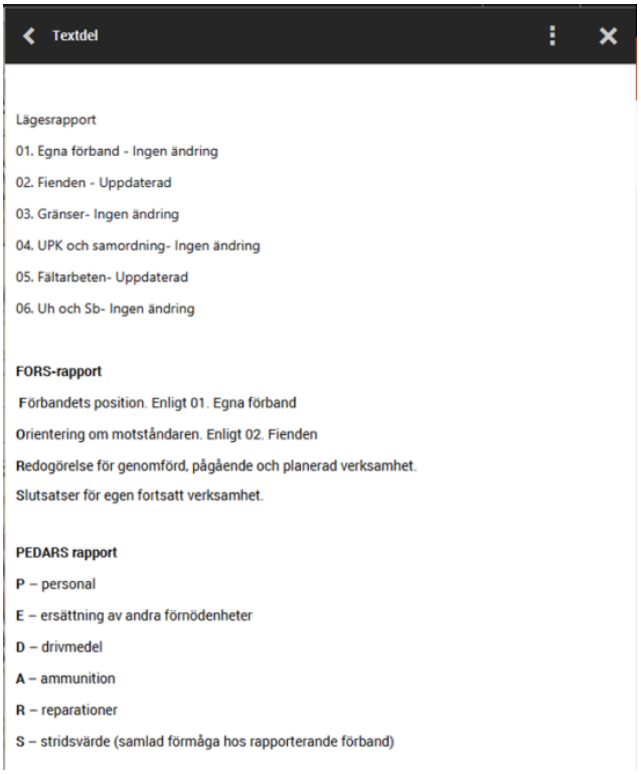

Figur 29 Exempel på textdel i en plan.

13. Om planen/order ska exporteras görs detta via *USB-kopia*.

7.4 Hantera lager i planer/order

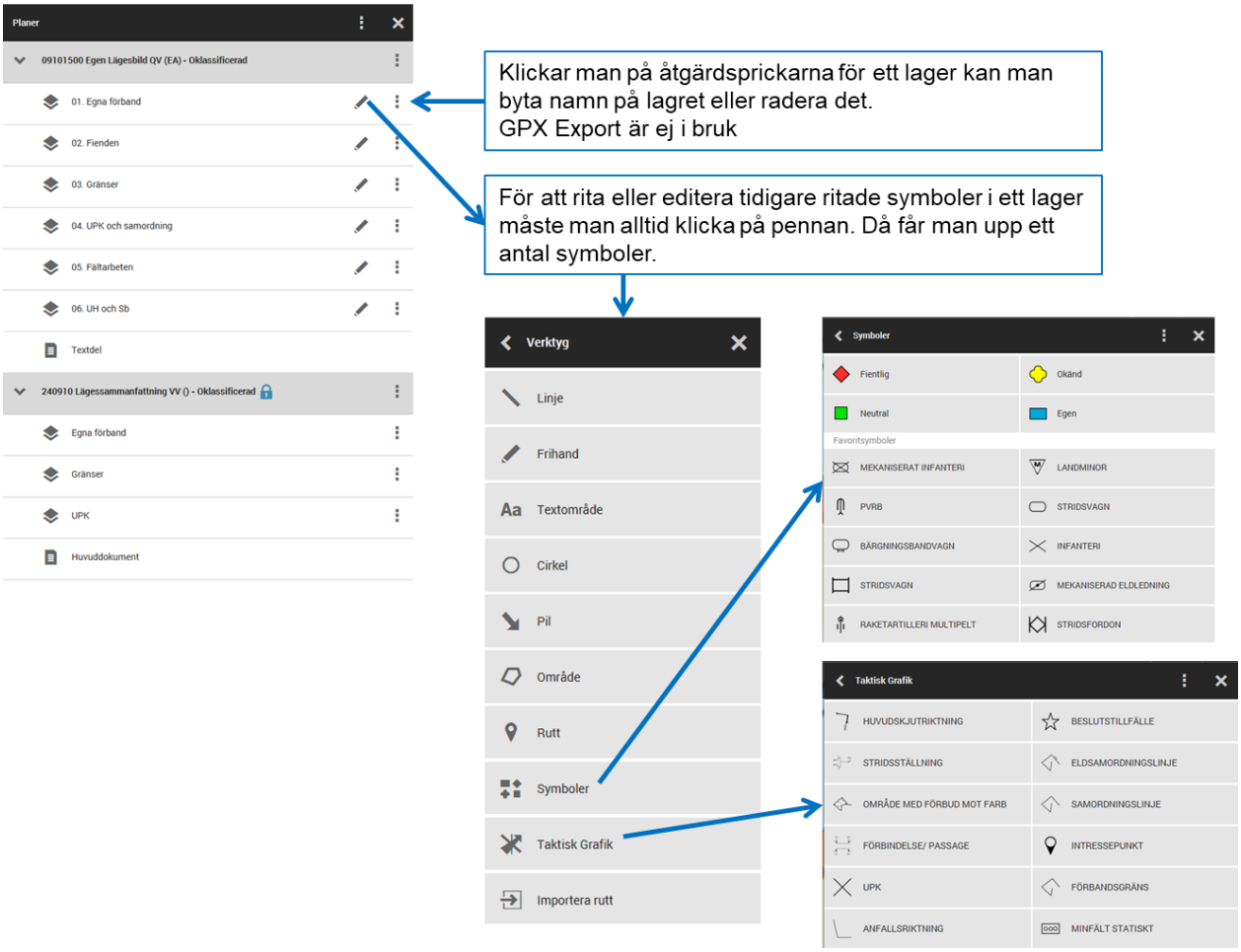

Figur 30 Menyer för att hantera lager.

7.5 Rita en ny symbol i ett lager.

Att rita nya symboler i ett lager görs enligt följande:

1. Klicka på ikonen som ser ut som en penna för aktuellt lager.

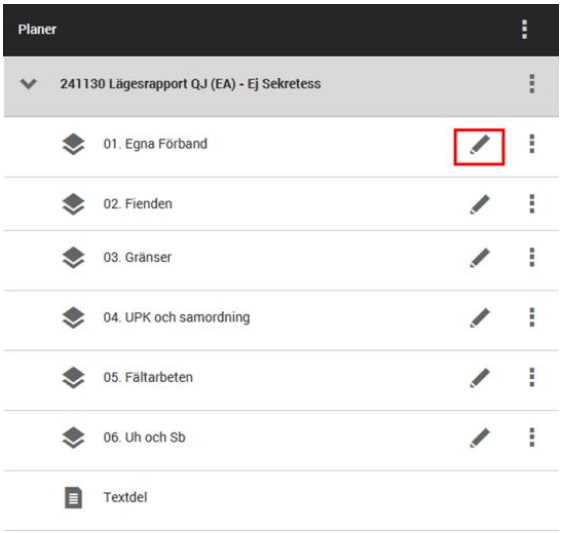

Figur 31 Pennsymbolen för att rita i ett lager.

2. Då öppnas ett nytt *Verktygs*-fönster. Under *Symboler* kan man skapa förbandssymboler eller symboler för enskilda vapen, fordon och så vidare.

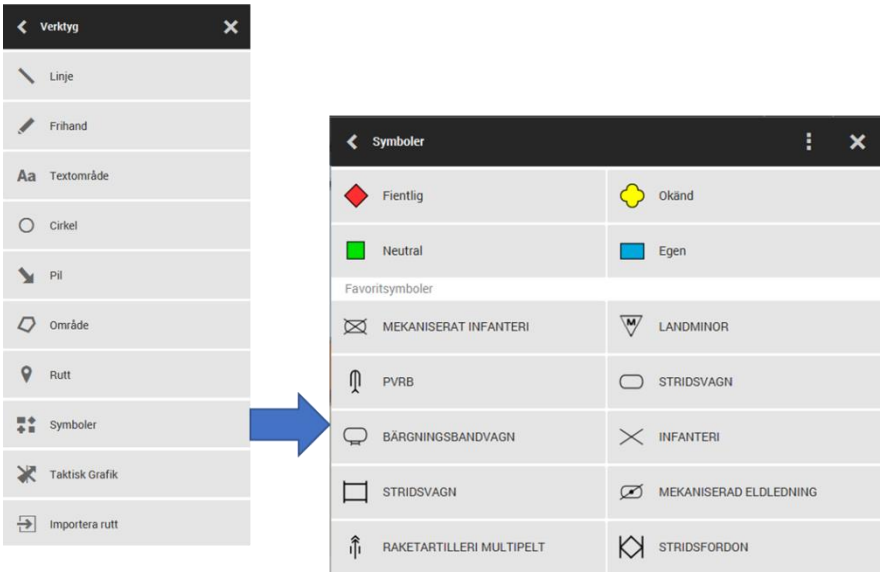

Figur 32 Symbolbibliotek under Symboler.

3. Välj en symbol genom att klicka på den. Klicka sedan på kartan där den ska placeras.

Figur 33 Meny för att placera en symbol i kartan.

4. När detta är gjort öppnas *Rapport detaljer* enligt nedanstående bild.

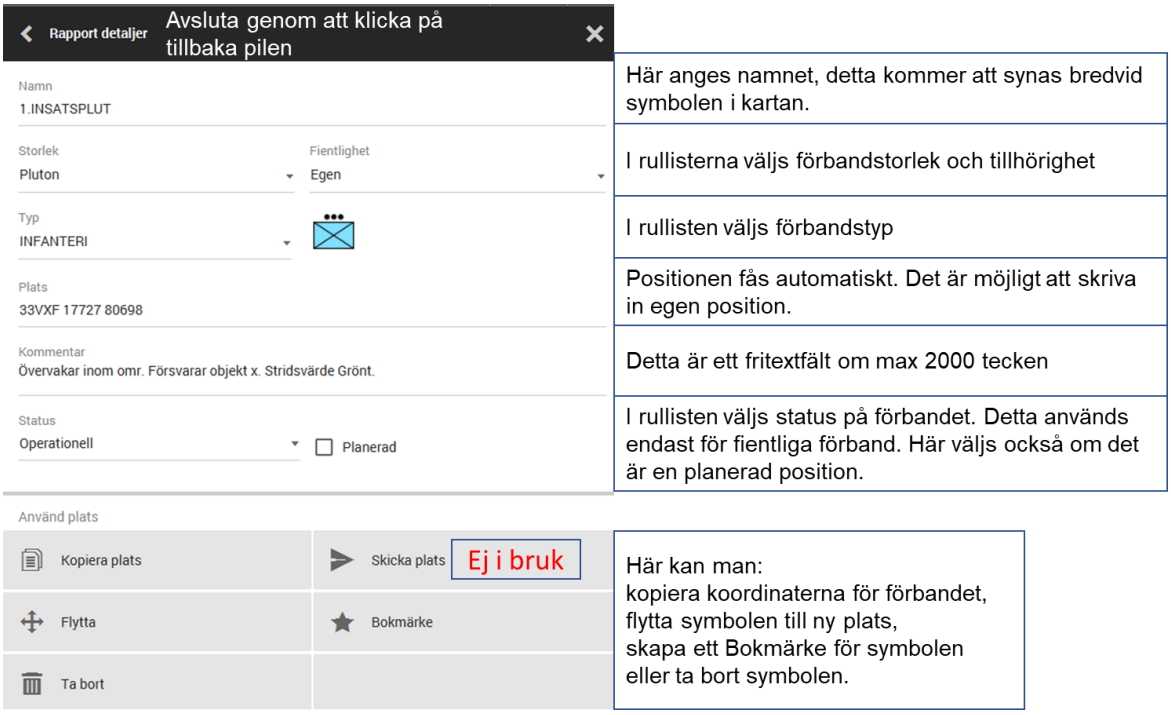

Figur 34 Ifyllande av en symbols Rapportdetaljer.

5. Efter att ha fyllt i *Rapport detaljer* kan man klicka på tillbaka pilen för att fortsätta ritandet eller editerandet av andra symboler.

6. Under *Taktisk grafik* finns ett urval av symboler för taktisk grafik.

Figur 35 Symboler för taktisk grafik.

7. Efter att ha valt en taktisk grafiksymbol placeras den på kartan på samma sätt som för förbandssymboler.

Figur 36 Meny för att placera taktisk grafik på kartan.

8. Även här dyker ett formulär för symbolens *Detaljer* upp där man kan göra ett antal justeringar. Klicka på tillbaka pilen för att fortsätta rita eller editera symboler.

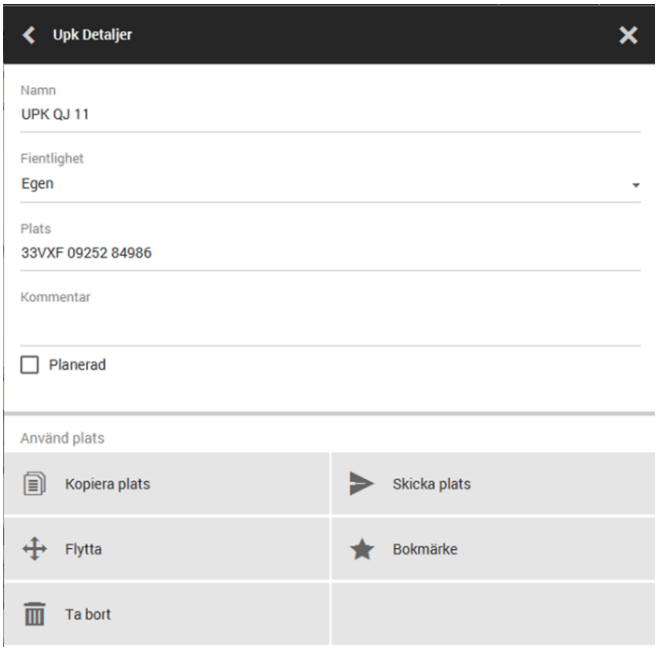

Figur 37 Exempel på Detalj-formulär för taktisk grafik.

9. Vid val av annan symbol (exempelvis pilar, linjer, områden eller motsvarande) visas ett fönster där symbolens utseende kan redigeras.

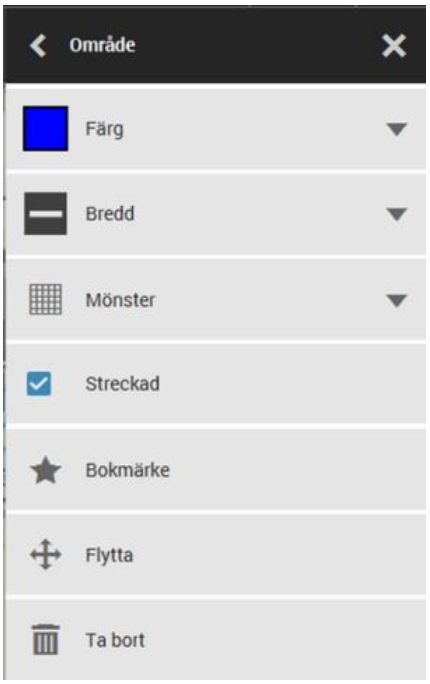

Figur 38 Exempel på möjliga formateringar för en symbol.

7.6 Editera en befintlig symbol i ett lager.

Att editera en tidigare ritad symbol görs enligt följande:

1. Klicka på pennan på det lager där symbolen finns.
2. Klicka på aktuell symbol i kartan.
3. Öppna *Rapport Detalj*-formuläret.
4. Gör ändringar och vid behov flytta symbolen.
5. Avsluta med att klicka på tillbaka pilen.

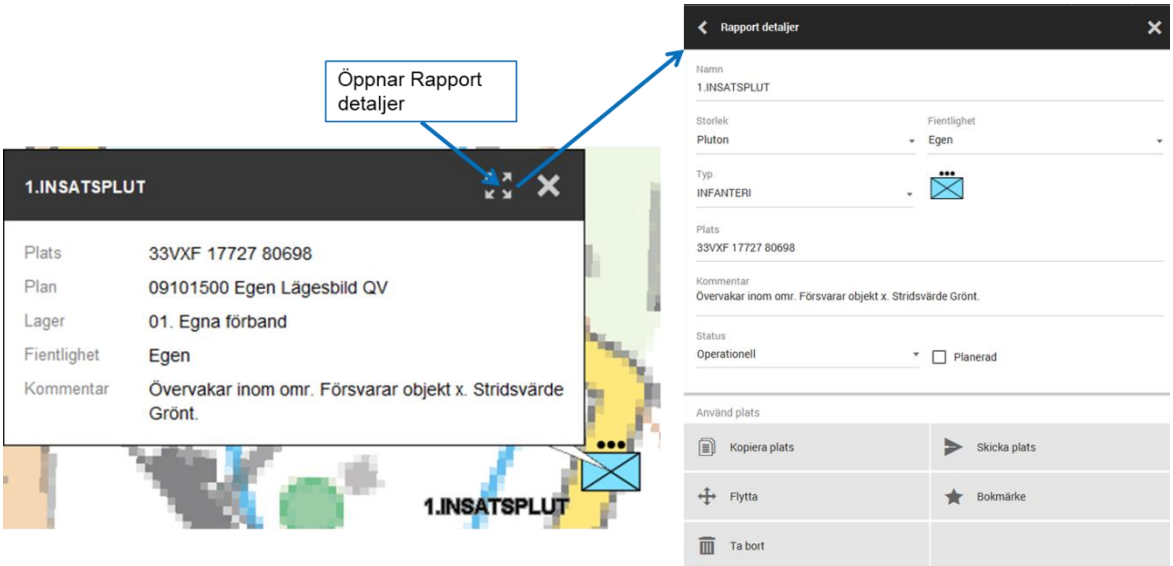

Figur 39 Öppna Rapport detaljer för en tidigare ritad symbol.

7.7 Kompaniets nyttjande av Planer

Kompaniet använder *Planer* för att föra egen lägesbild som också nyttjas som en del i lägesrapporten till HC.

Kompaniet skapar i Frontline/*Planer* en plan som döps till tidsnummer, lägesrapport och anropssignal (exempelvis 011610 Lägesrapport QJ). Denna lägesbild ska som minst innehålla följande information, lämpligen paketerad i nedanstående *Lager*:

Lager	Innehåll
01. Egna förband	Egna underställda enheter (plutoner). I förbandssymbolen uppdateras Kommentar med aktuell verksamhet och sammanfattande stridsvärde.
02. Fienden	Rapporterade fiendeenheter. Vid behov nyttjas även förklarande textrutor.
03. Gränser	Egna förbandsgränser.
04. UPK och samordning	UPK och samordningslinjer
05. Fältarbeten	Fältarbeten inom eget område. Vid behov nyttjas även förklarande textrutor.
06. Uh och Sb	Uhplatser, Sjvplatser, Sbplatser, motsv. Vid behov nyttjas även förklarande textrutor.

Tabell 2 Lager i kompaniets lägesbild och lägesrapport.

Denna *Plan* är både kompaniets lägesbild och dess lägesrapport. Kompletteringar och ändringar förs in löpande när situationen medger detta, då detta görs uppdateras tidsnummer.

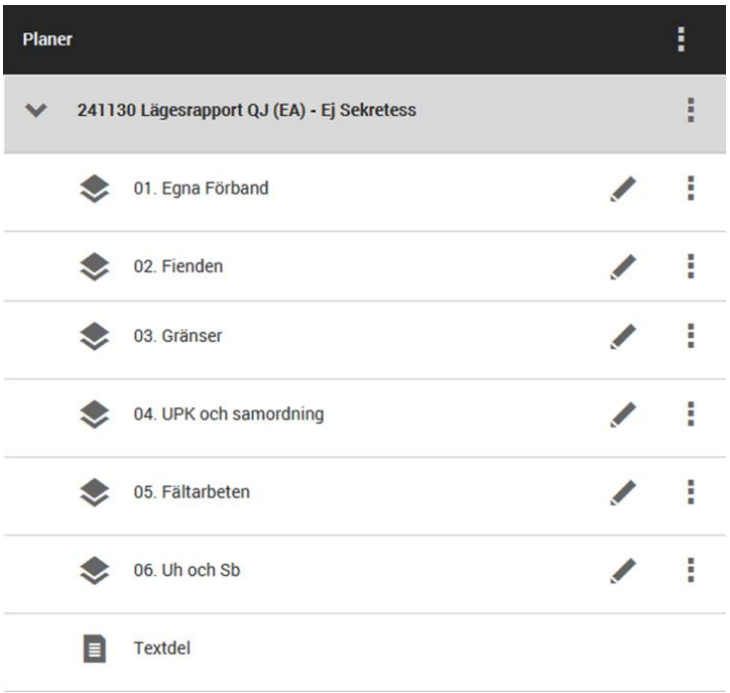

Figur 40 Exempel på kompaniets lägesbild tillika lägesrapport.

Det är denna lägesrapport som exporteras ut ur Frontline via *USB-kopia* och skickas enligt HC SO via fildelning eller via USB-minne.

Uppdatering av en plan/order görs enligt följande:

1. Släck alla lager i *Lager* (det vill säga *Rapporteringslagret* och *Eget SLO lager).*
2. Öppna *Planer*.
3. Klicka på ikonen penna för det lager som ska uppdateras.
4. Klicka på aktuell symbol.
5. Öppna upp symbolrapporten och flytta symbolen och/eller uppdatera *Kommentar*.
6. Stäng symbolrapporten och vid behov uppdatera annat lager med nya symboler eller flytta symbolen och/eller uppdatera *Kommentar*.
7. Vid behov görs även kompletteringar i textdokumentet.
8. Ifall lägesrapporten ska exporteras görs detta via *USB-kopia.*

8 STRIDSLEDNINGSOLEAT

I stridsledningsoleat kan man rita ett begränsat antal symboler. Egen verksamhet förs i första hand i *Planer* och i lägesrapportens lager.

Eget SLO kan användas för att följa upp egen verksamhet genom att lager från *Planer/Lägesrapport* är tända. Nyttja Eget SLO som ett överliggande lager där man kan planera och rita in bedömningar utan att påverka informationen i lager från *Planer*.

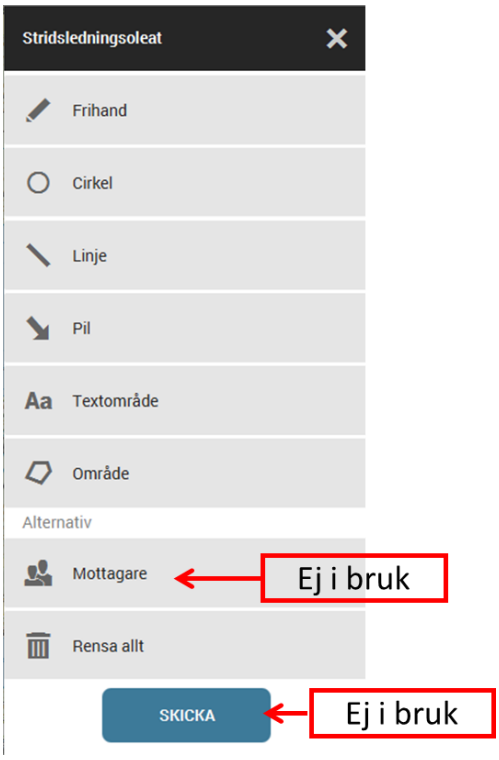

Figur 41 Möjliga symboler i stridsledningsoleat.

OBSERVERA!
Funktionerna Mottagare och Skicka är inte i bruk med hänsyn till att det inte finns någon nätverkskoppling till Frontline.

Stridsledningsoleatet tänds och släcks via *Lager*. Se även avsnitt **5 Lager**.

9 SYMBOLFAVORITER

Det är möjligt att skapa ett symbolbibliotek innehållande de symboler som används ofta. Detta kan göras antingen från *Meny/Rapport* och/eller via *Planer*. Enklast görs detta via *Planer*, där man kan göra symboler och taktisk grafik till favoriter. Ändringar i symboler som görs i *Planer* syns även i *Rapport*. Observera att det inte finns någon taktisk grafik i *Rapport*.

Detta görs enligt följande:

1. I *Planer* klickar man på pennan vid ett lager för att få upp *Verktygsfönstret*. Välj *Symboler* och klicka därefter på åtgärdsprickarna upp till höger.

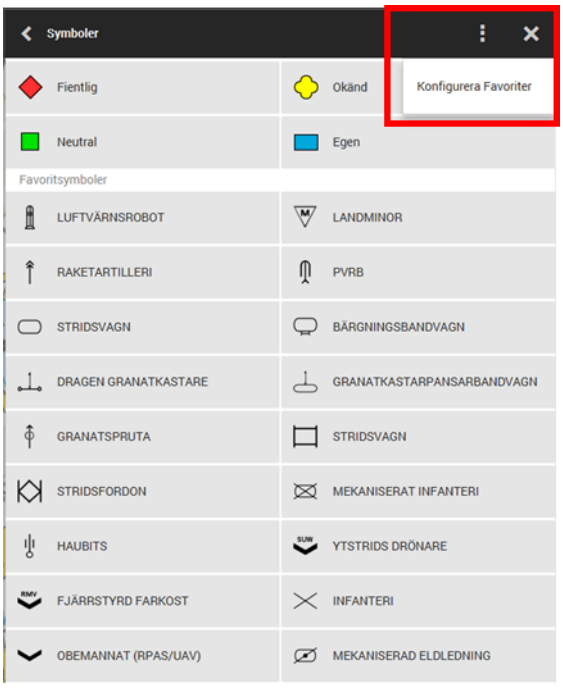

Figur 42 Åtgärdsprickar för att konfigurera favoritsymboler.

2. När man har klickat på åtgärdsprickarna och sedan *Konfigurera Favoriter* öppnas ett nytt fönster där man väljer vilka symboler man vill ha.

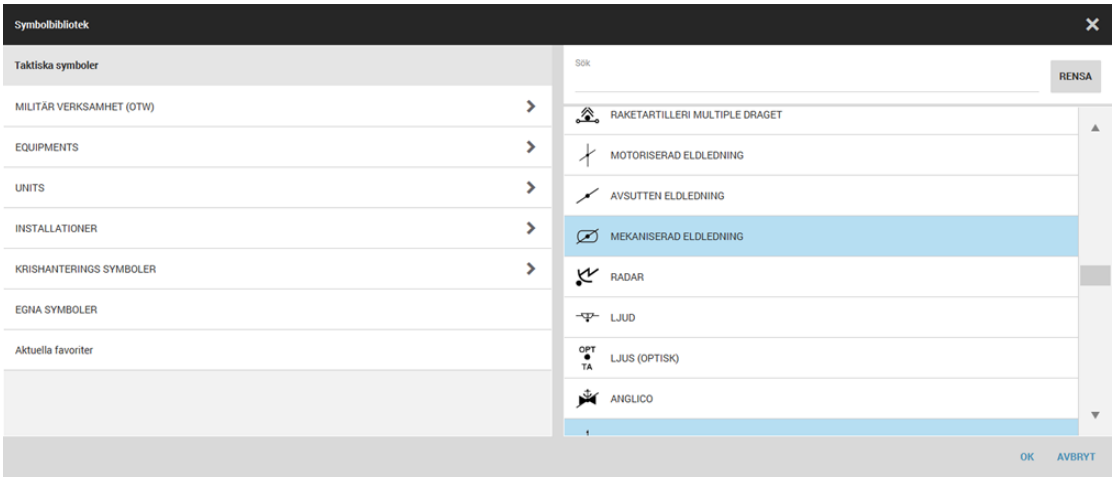

Figur 43 Meny för att välja favoritsymboler.

3. Alla symboler som finns i favoriter visas som blåmarkerade. För att ta bort en symbol från favoriter klicka på symbolen så att den blå markeringen släcks.

4. Klicka på *Aktuella Favoriter* för att endast visa valda favoriter. Även här kan inaktuella favoriter avmarkeras genom att klicka på symbolen.

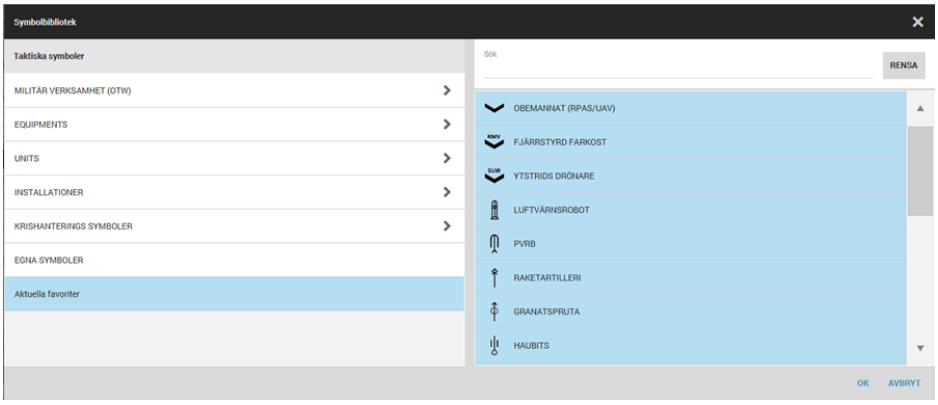

Figur 44 Valda Aktuella Favoriter.

5. Klicka sedan på *OK*. Symbolbiblioteket uppdateras i både *Planer* och *Meny/Rapport*.

På motsvarande sätt kan man skapa sina favoriter för taktisk grafik:

1. I *Planer* klickar man på pennan vid ett *Lager* så att man får upp *Verktygsfönstret*.

2. Välj *Taktisk Grafik* och klicka därefter på åtgärdsprickarna upp till höger.

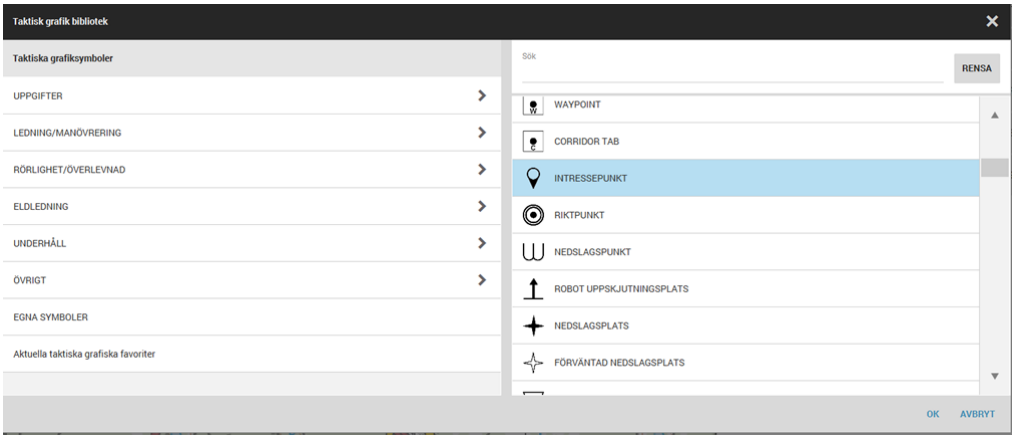

Figur 45 Meny för att välja favorit Taktisk grafik.

3. För att visa alla förvalda favoriter samlat välj *Aktuella taktiska grafiska favoriter*.

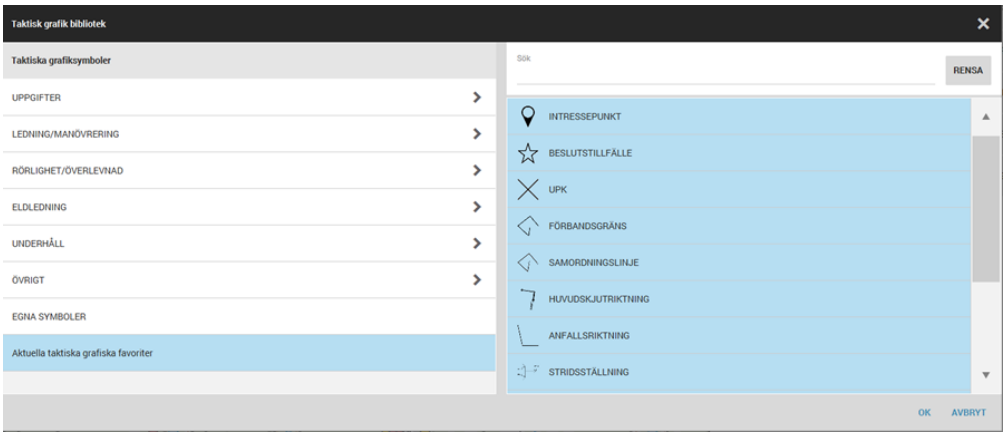

Figur 46 Valda favoriter för Taktisk Grafik.

10 BOKMÄRKEN

Skapade *Bokmärken* återfinns under *Meny/Bokmärken*. *Bokmärken* används för att snabbt hitta och visa information från skapade symboler i *Meny/Rapport* och från *Planer*. *Bokmärken* kan nyttjas för att stödja vid ordergivning eller lägesuppdateringar.

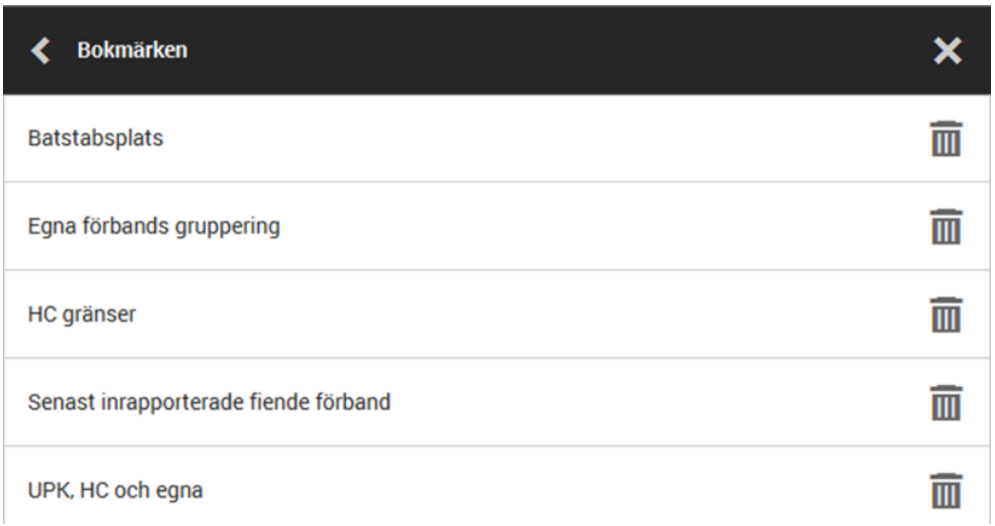

Figur 47 Exempel på skapade Bokmärken.

Under *Meny/Bokmärken* kan man tända aktuella *Bokmärken* såväl som radera *Bokmärken* som inte längre används.

OBSERVERA!
När man väljer ett Bokmärke innebär det att man tänder det lager där symbolen finns. När man väljer ytterligare ett Bokmärke tänds ytterligare lager utan att det första lagret släcks. Det innebär att när man valt ett antal Bokmärken att man samtidigt tänt ett antal lager vilket kan upplevas förvirrande när man senare arbetar i Planer. Att släcka lager görs under Lager och Planer.

BEGREPP

I denna publikation definieras flera begreppen i den löpande texten. Uppställningen är gjord i bokstavsordning.

Begrepp	Förklaring och exempel
2525C	MIL-STD-2525, Department of Defense Interface Standard Common Warfighting Symbology, är den amerikanska krigsmaktens symbolstandard. Den fastställer regler och krav för att använda och visa symboler vid militär verksamhet. Första utgåvan kom 1994 och den senaste, MIL-STD-2525D, utkom 2014.
MGRS	Military Grid Reference System (MGRS) är en metod för lägesangivning baserat på referenssystemet WGS 84 och UTM-projektion där man anger en *ruta* (engelska *grid*) snarare än en punkt och att rutan anges med både siffror och bokstäver.
Mils	Mils (uttalas "mills") – en streckindelning inom NATO och Sverige. Vinkelenhet som är 1/6400 av ett varv.

REDAKTIONELL INFORMATION

Instruktion Frontline 2.3 är framtagen av Hemvärnets Stridsskola.

Den här versionen är första utgivna versionen av Instruktion Frontline men utgår ifrån tidigare Direktiv IS HV Användare [FM2019-1048:3]. Observera att direktivet inte är fastställt. Instruktionen är avsedd att ersätta direktivet.

Redaktör för instruktionen är major Wilhelm Glatz.

Instruktionen är fastställd av Johan Brovertz, C HvSS, som fick den föredragen 2024-01-15.

BILDFÖRTECKNING

Den här publikationen innehåller inga bilder med verkshöjd.

Figur 1 Startbild ISHv kompani. 7
Figur 2 Kartmapp för Frontline på kompaniklienten..... 8
Figur 3 Gränssnitt för Frontline..... 9
Figur 4 Frontline statusmarkör när statusen är grön..... 10
Figur 5 Frontline statusmarkör när fel finns i systemet..... 10
Figur 6 Statusfönster med två fel..... 10
Figur 7 Åtgärdade felrapporter..... 11
Figur 8 Funktioner under Meny. 13
Figur 9 Symbolbibliotek under Rapporter..... 14
Figur 10 Rapportdetaljer för symboler skapade via Rapporter. 15
Figur 11 Gränssnitt för USB kopia..... 16
Figur 12 Möjliga inställningar i Frontline..... 17
Figur 13 Dialogruta för att avsluta Frontline..... 18
Figur 14 Geoverktygen och dess användning. 19
Figur 15 Dialogruta som visar versionsnummer. 20
Figur 16 Lager..... 21
Figur 17 Välja kartor sammanfattning. 22
Figur 18 Uppdatering av tillgängliga kartor i C:Maps. 23
Figur 19 Mapp för kartor i Frontline. 23
Figur 20 Gränssnitt för Planer..... 24
Figur 21 Egenskaper för en plan/order..... 25
Figur 22 Åtgärdsprickar och meny för ny plan. 25
Figur 23 Egenskaper för en ny plan/order..... 26
Figur 24 Meny för att byta namn på ett lager..... 26
Figur 25 Lägga till ett nytt lager till en plan..... 27
Figur 26 Val av plan för import av lager..... 27
Figur 27 Val av lager för att importera ett lager..... 28
Figur 28 Åtgärdsprickar för att döpa om ett lager..... 28
Figur 29 Exempel på textdel i en plan..... 29
Figur 30 Menyer för att hantera lager..... 30
Figur 31 Pennsymbolen för att rita i ett lager..... 31
Figur 32 Symbolbibliotek under Symboler. 31
Figur 33 Meny för att placera en symbol i kartan. 32
Figur 34 Ifyllande av en symbols Rapportdetaljer. 32
Figur 35 Symboler för taktisk grafik..... 33
Figur 36 Meny för att placera taktisk grafik på kartan..... 33
Figur 37 Exempel på Detalj-formulär för taktisk grafik..... 34
Figur 38 Exempel på möjliga formateringar för en symbol. 34
Figur 39 Öppna Rapport detaljer för en tidigare ritad symbol. 35
Figur 40 Exempel på kompaniets lägesbild tillika lägesrapport..... 36
Figur 41 Möjliga symboler i stridsledningsoleat..... 38
Figur 42 Åtgärdsprickar för att konfigurera favoritsymboler..... 39
Figur 43 Meny för att välja favoritsymboler. 40

Figur 44 Valda Aktuella Favoriter. 40
Figur 45 Meny för att välja favorit Taktisk grafik..... 41
Figur 46 Valda favoriter för Taktisk Grafik. 41
Figur 47 Exempel på skapade Bokmärken. 42

Tabellförteckning

Tabell 1 Utvisande inställningsmöjligheter i Inställningar..... 18
Tabell 2 Lager i kompaniets lägesbild och lägesrapport. 36

KÄLLFÖRTECKNING

I den här versionen av instruktionen har följande källor använts:

Källor utanför Försvarsmakten
User Manual for SitaWare Frontline 2.4

Källor inom Försvarsmakten
Instruktion ISHv Gemensamma funktioner 2025

Regler, bestämmelser och handböcker som påverkat innehållet i denna instruktion

Handbok	Handbok ISHv Stabstjänst 2025 (H ISHv Stabstj 2025)