Kartsymboler

Hur byggs symbolen upp?

Ram

Ikon

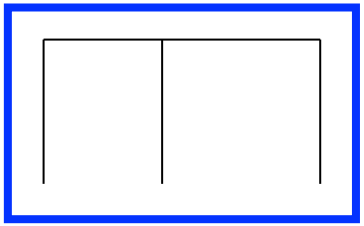

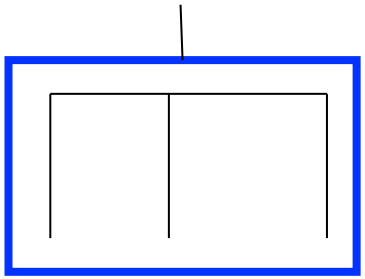

Tilläggsinformation

Symbolfärger

- Blå anger all egen (svenska förbands) verksamhet
- Svart anger våra egna gränser eller egen verksamhet (31), linjer, text
- Röd anger all fientlig verksamhet
- Gul Okända förband och dess verksamhet tills tillhörighet är fastställd
- Grön Neutrala förband och deras verksamhet
- Lila/ Brunt Vädersymboler

Förbands- och funktionsformer

Tillhörighet	Ram			
	Egen	Neutral	Fientlig	Okänd
Mark				
Luft				
Sjö				
Undervatten				
Rymd				

Handritade förbands- och funktionsformer

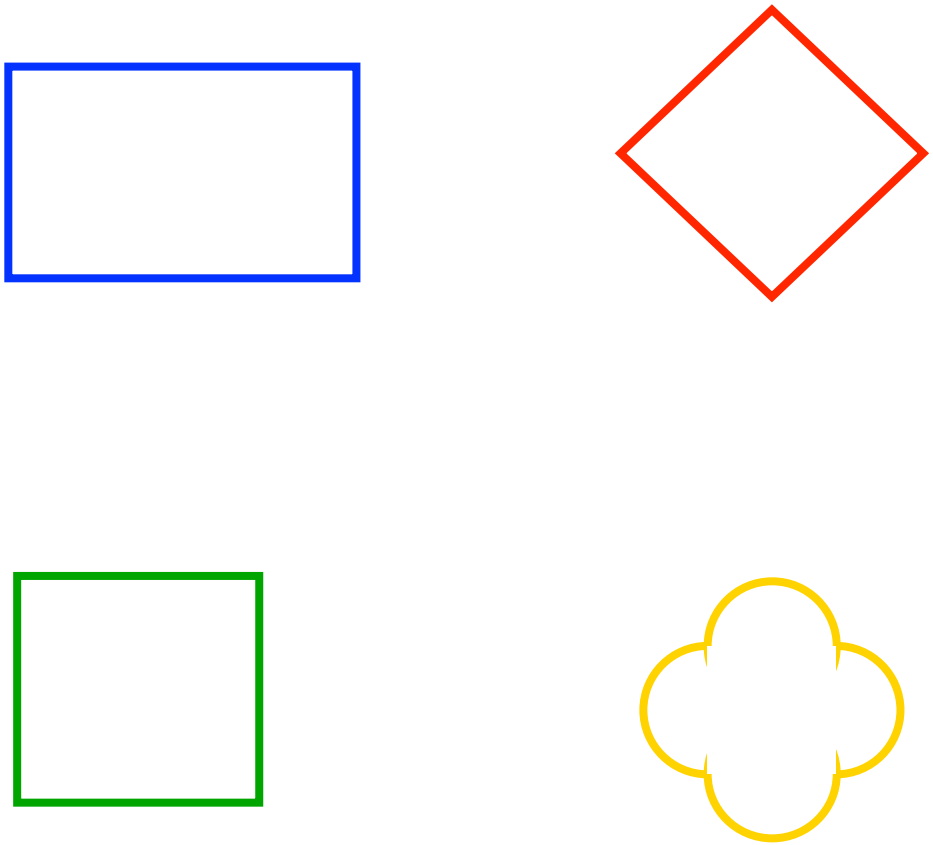

Symbolstatus

Tilläggsinformation

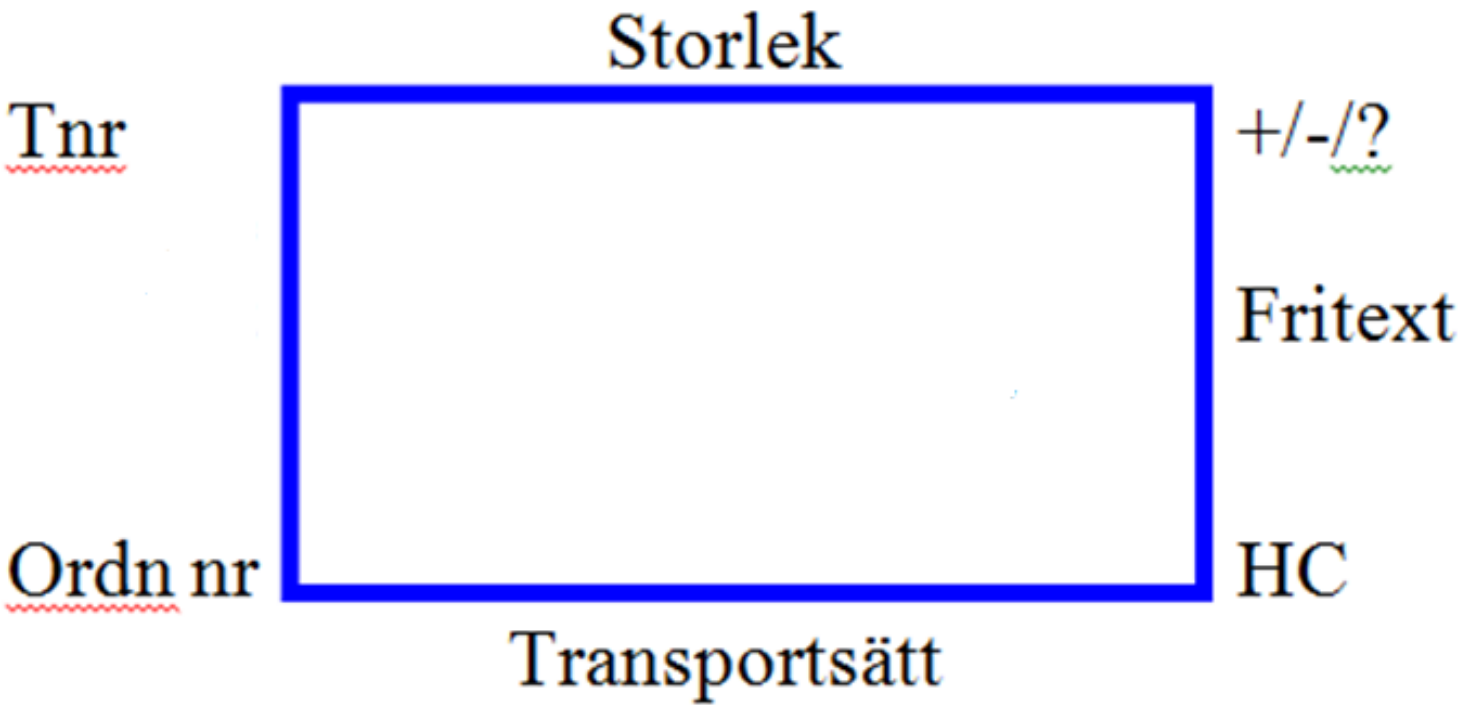

Vektarens placering

Betydelse	Mark	Sjö	Luft
Förbandets exakta placering	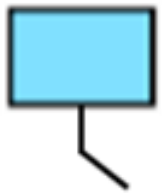		
Stabs- eller ledningsplats			

Högkvarter/staber

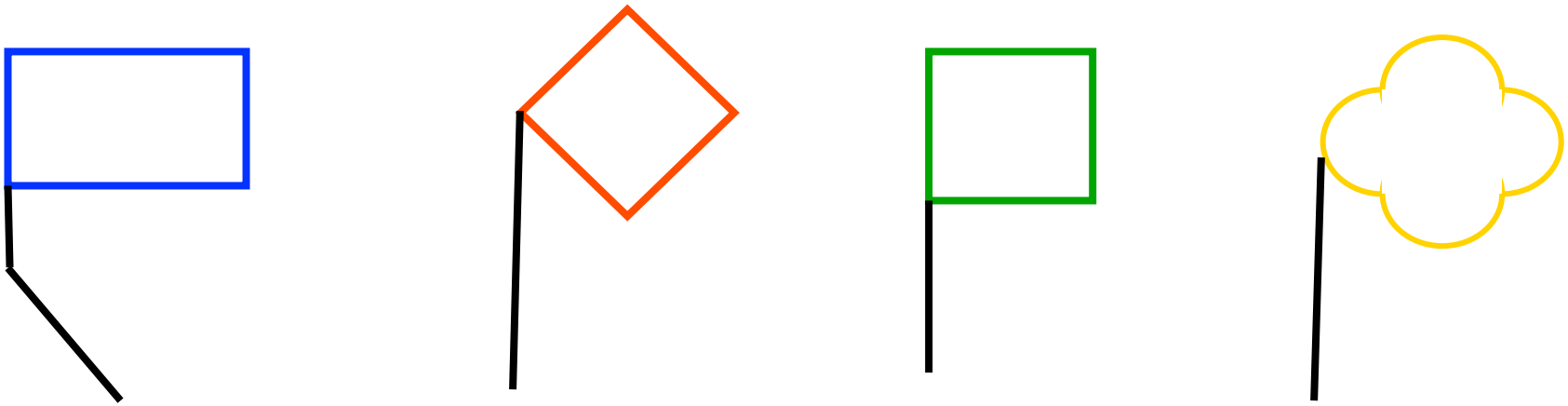

Observationsplats

O-plats

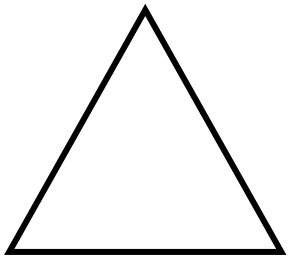

Transportsätt

Hjulfordon

Terränggående

Bogserat

Järnvägstransport

Översnö

Släde

Pråm

Packdjur

Helikopter

Bandgående

Luftburet

Flygplan

Amfibie

Rörelseriktning

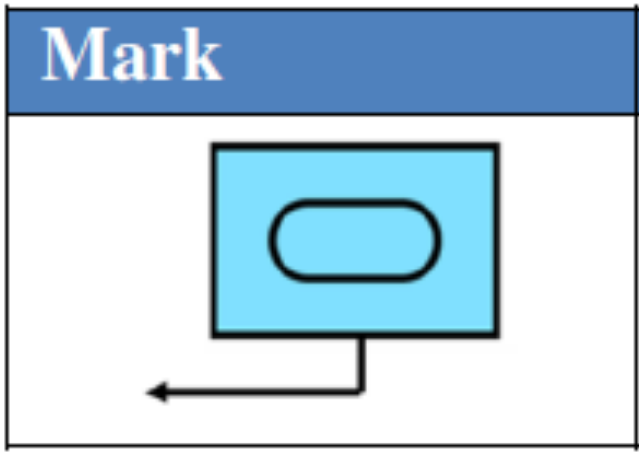

Förbandsstorlek

•	Grupp, avd
• •	Tropp
• • •	Pluton
|	Kompani

||	Bataljon
|||	Regemente
X	Brigad
XXO	RS

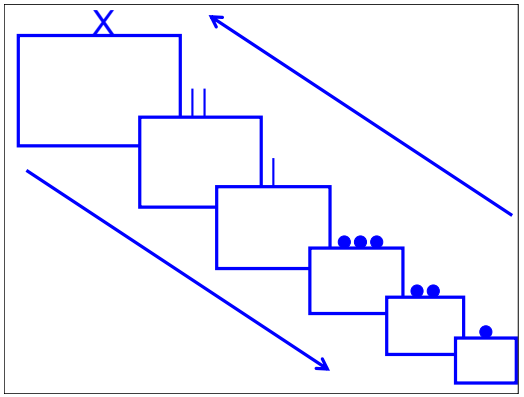

Teckenstorlek:

Bataljon	20 x 15 mm
Kompani	17 x 10 mm
Pluton	8 x 14 mm

Exempel på förbandstecken

- Hvbatstab

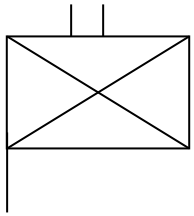

- Mek förband

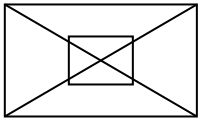

- Ingenjörsförband

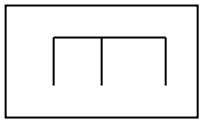

Taktisk grafik

Understöds och hänvisningsplatser

Symbolen byggs upp genom att definiera ett antal fält enligt nedanstående princip:

Bild 33 Uppbyggnad av understöds/hänvisningsplats samt ett exempel på tillämpning.

Fält	Innehåll
A	Betjänande förband, anges med anropssignal eller namn.
A_1	Littrering, anges med siffra eller beteckning på platsen.
B	Typ av understöd och/eller hänvisning.
C	Platsens lokalisering, kan på samma sätt som förbandssymboler placeras på en stapel där foten anger den exakta grupperingsplatsen.
D	Tidsnummer för när platsen är upprättad, vid behov anges ett tidsspann för den tid platsen är upprättad.

Gränser

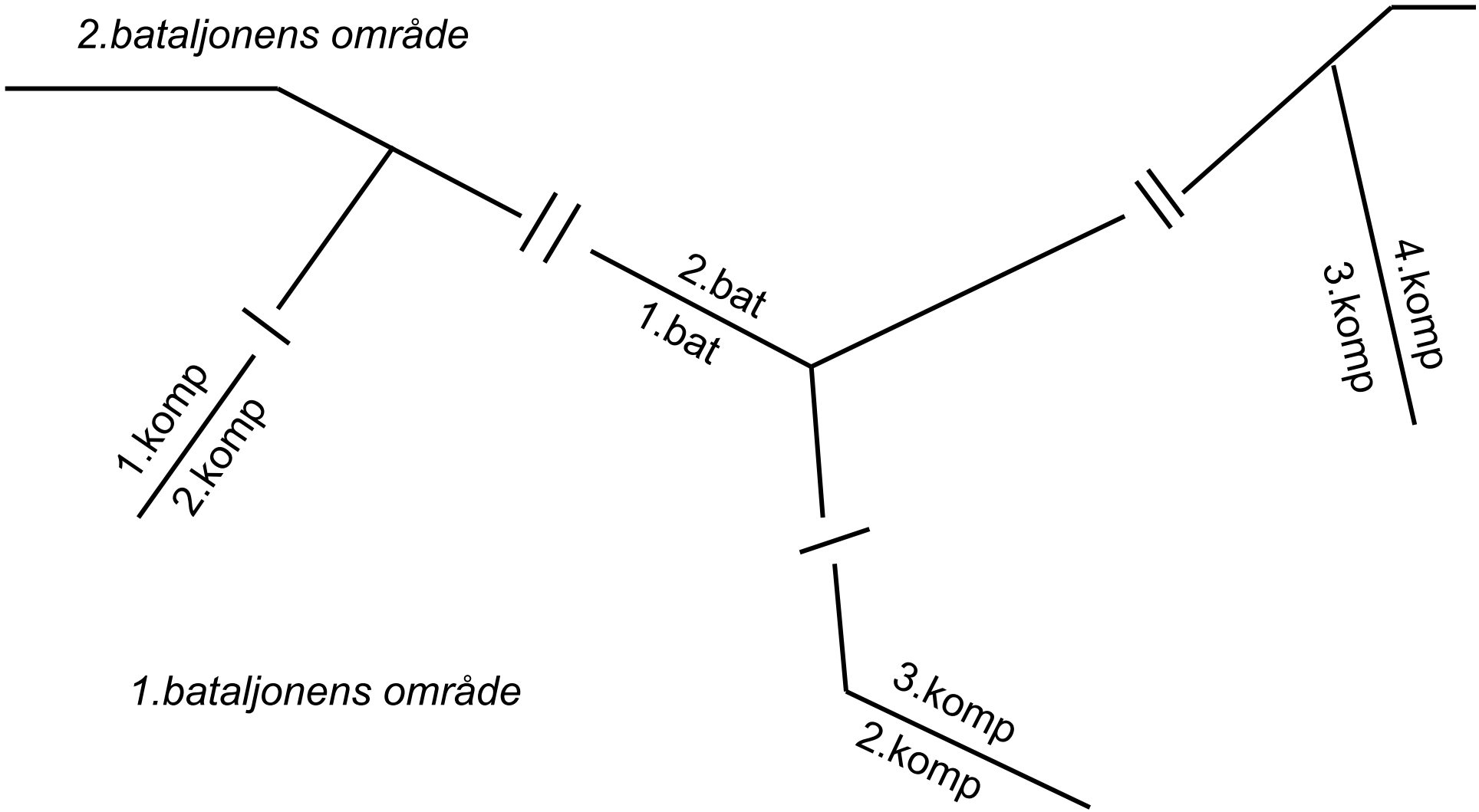
2.bataljonens område
2.bat
1.bat
1.komp
2.komp
4.komp
3.komp
3.komp
2.komp
1.bataljonens område