PdfMaps

PdfMaps är en app från Avenza som använder georefererade pdf-kartor. PdfMaps finns f.n. för Android och Iphone samt en beta-version för Windows Phone.

Med PdfMaps kan man se sin position på kartan, zooma och panorera, markera platser, mäta avstånd, spela in gps-spår, exportera till och importera från kml-filer mm. PdfMaps fungerar utmärkt tillsammans med de geo-pdf-er som produceras i projektet NMK Skjutfält.

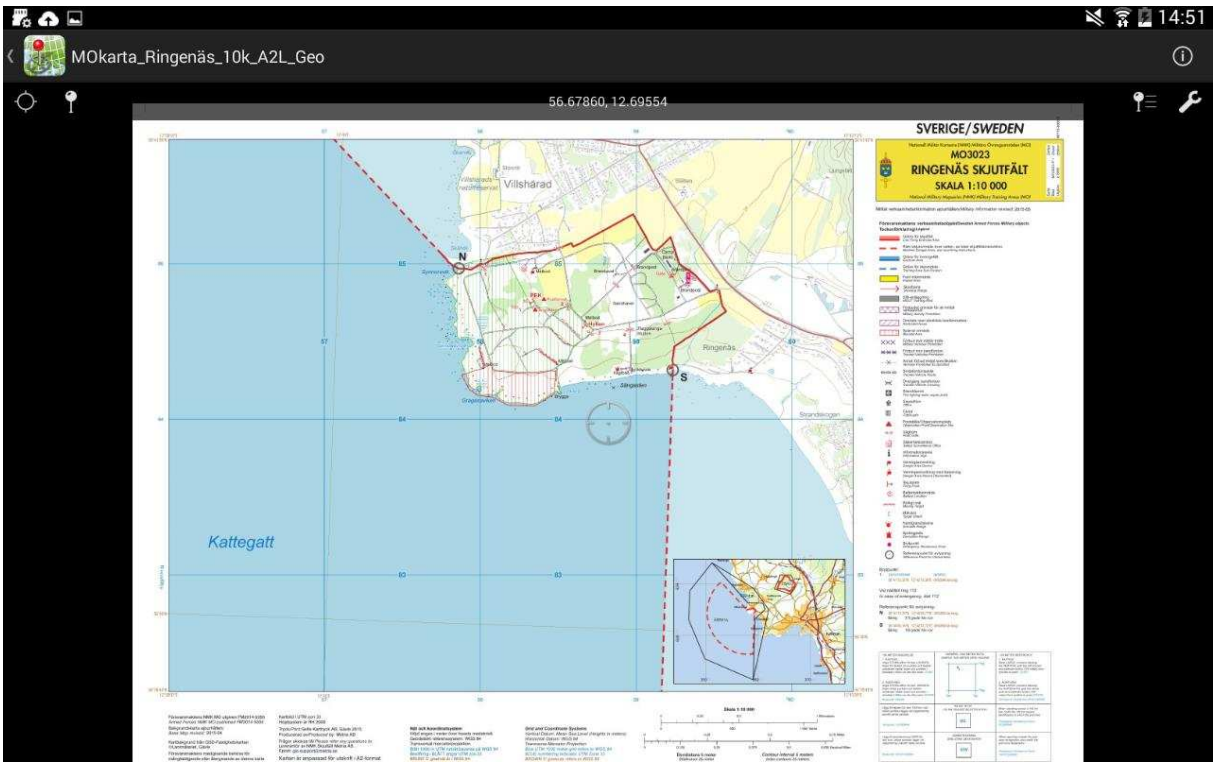

Ringenäs skjutfält i PdfMaps

Vi tror att PdfMaps kan öka användningen av geo-pdf-kartor inom projektet NMK Skjutfält. Dels kan man använda sina digitala kartor i fält, dels kan insamling av uppdaterade och kompletterande objekt ske så länge de inte har högre krav på noggrannhet än vad GPS-en klarar.

1 Importera kartor

Alla georefererade pdf-filer kan användas i PdfMaps. De geo-pdfer av MO-kartan som distribueras i NMK Skjutfält fungerar bra i PdfMaps.

1.1 Via mail

När PdfMaps är installerat så skicka ett mail till enheten med en karta som bilaga och läs den bilagda filen med PdfMaps, det kommer upp som ett alternativ när man öppnar bilagan. Filen laddas in i PdfMaps direkt

1.2 Dropbox

Pdfmaps lirar bra ihop med Dropbox, så har du ett Dropbox-konto kopiera en geo-pdf dit och läs från PdfMaps.

Det går förstås också att kopiera filen till minnet på enheten och läsa direkt därifrån.

2 Funktioner

2.1 Siktet

Mitt i kartbilden finns ett ”sikte” som är centralt i PdfMaps. Det är centralt i PdfMaps och används för att peka ut rätt plats i kartan i ett antal funktioner.

2.2 Kartvisning

I den svarta verktygsraden ovanför kartan finns de verktyg som är tillgängliga.

- Klicka en gång på det första så centreras kartan till din verkliga position (givet att gps-en är påslagen och du finns inom kartbilden).
- Klicka en gång till så visas kartan i kompassläge, dvs. kartan vrids efter norr-söder.
- Klicka igen så går det tillbaka till normalläge.

Genom att klicka på koordinatangivelsen ovanför kartan kan man byta format mellan ett tiotal olika representationer av WGS84, som grad-minut-sekund, decimala grader eller MGRS.

2.3 Skapa Map Features

Skapa en kartnål (markering, Map Feature) i den position som siktet pekar på med .

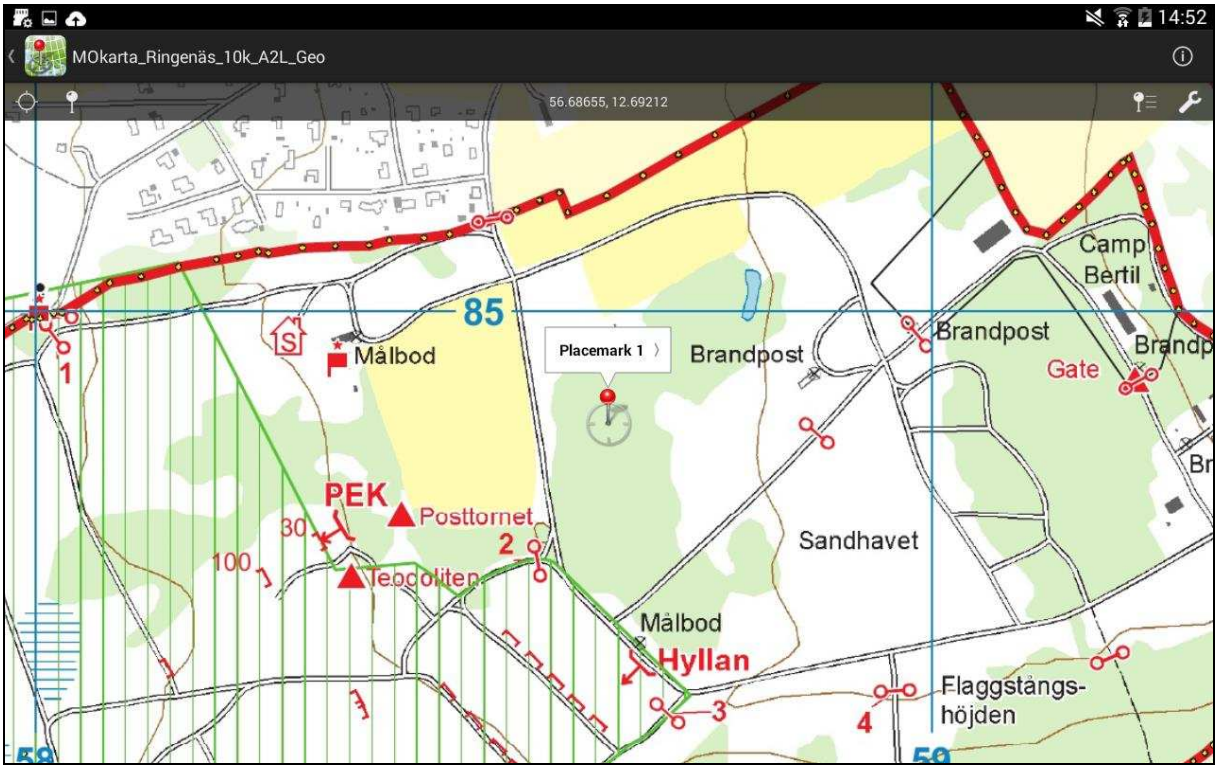

Vill man skapa den i den position man står på, klickar man först på knapp 1 som centrerar till aktuell position. Klicka på etiketten så kan du sätta namn och redigera attribut, ändra utseende och färg på ”nålen”, lägga till en bild etc.

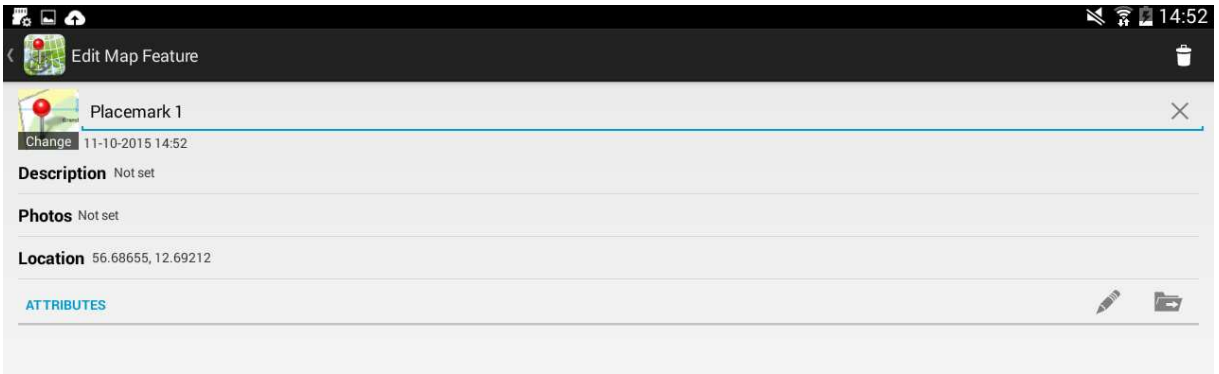

Redigering av Map Features

En Map Feature har alltid Namn, Beskrivning och Foton som attribut. Vill man ha ytterligare så klickar man på ”Attributes”. Vill man spara den i en egen mapp klickar man på mapp-symbolen med en pil på i nedre högra hörnet.

Se vidare avsnittet om att redigera map features.

2.4 Organisera och redigera Map Features

Den fjärde knappen används när man vill organisera eller redigera redan skapade Map Features.

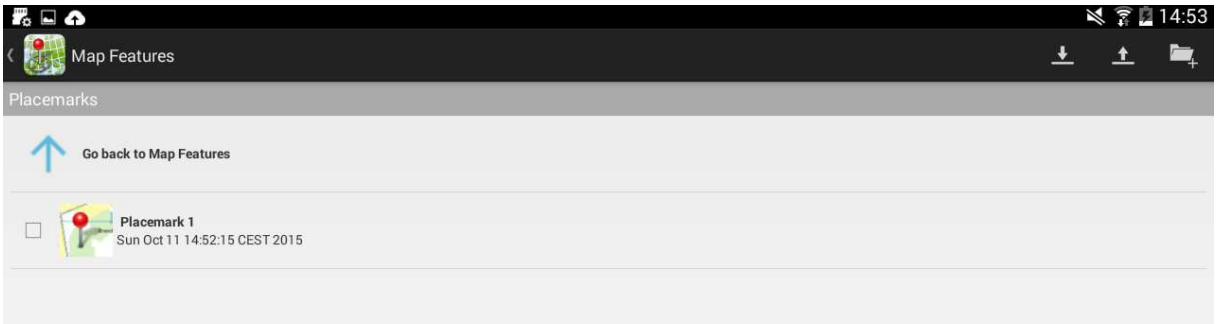

Här kan man se sina Map Features, lägga till och redigera attribut, byta manér, organisera i nya mappar, ändra synlighet för mappar, ta bort Map Features osv. Om man har färdiga kml-filer (verkar bara fungera för punkter) som man vill använda i kartan så klickar man på så kan man importera. OBS att om man importerar en kml-fil så utökas manérbiblioteket med de punktsymboler som finns i kml-filen.

Vill man exportera en map feature till en KML, GPX eller CSV-fil klickar man på .

En ny mapp skapas med knappen .

2.5 Avståndsmätning

Den sista knappen har en del användbara verktyg.

Här kan man mäta avstånd eller area i kartan. Siktet används för att specificera varje punkt. En ny punkt i avståndsmätningen läggs till med +, x tar bort senast inlagda punkt, triangeln ger avståndsmätning, klicka på triangeln för rektangel så mäts istället arean.

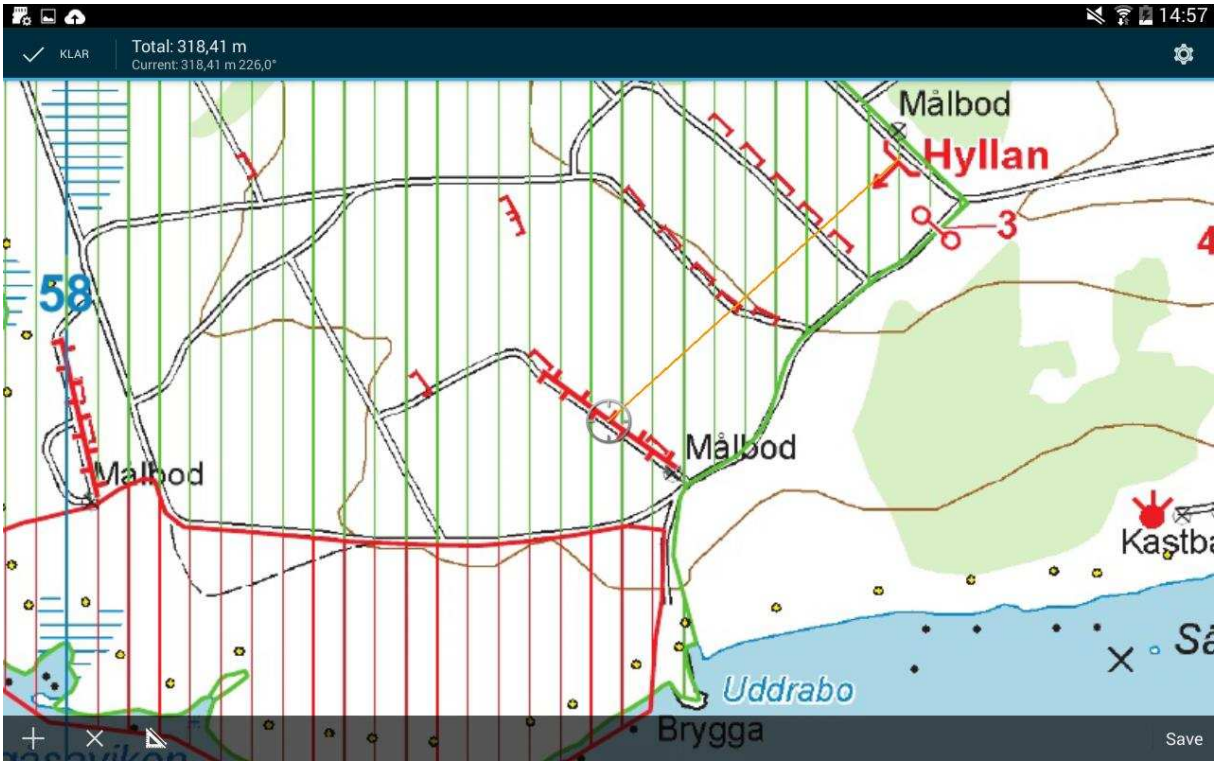

Avståndet från skjutplats Hyllan till det rörliga målet är 318 m.

Vill man spara linjen som en Map Feature så klickar man på Save innan man avslutar. Avsluta med ”bocken” Klar.

2.6 GPS-spår

Här kan man också spela in gps-spår. Eftersom den funktionen använder enhetens gyro så verkar noggrannheten bli bättre än för punktmarkeringar. För en vanlig gps-position kan man inte räkna på bättre noggrannhet än ca 10 m, ibland även sämre. Men känslan är att gps-spåret blir mer noggrant. Tyvärr har jag inte lyckats att exportera gps-spår eller importera linjer till/från KML på min Android.

Lycka till med PdfMaps. Kommer du på användbara saker som inte finns med här, skicka gärna ett mail till urban.carlbacker@metria.se