2017-10-26

NMK Skjutfält

Produktbeskrivning
Tryckt MO-karta

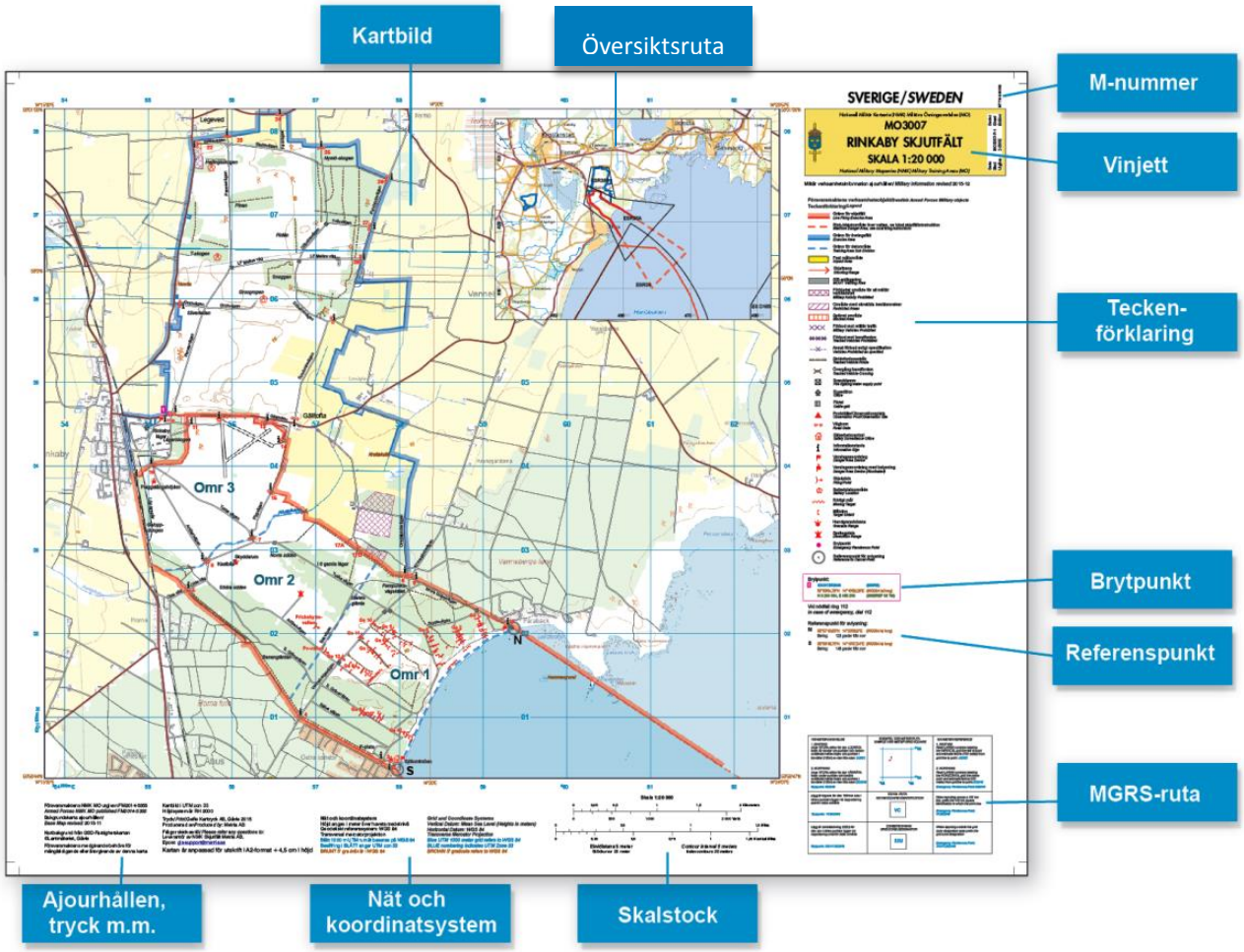

Metria AB, Box 30016, 104 25 STOCKHOLM

BESÖKSADRESS Warfvinges väg 35

TEL 010-121 80 00

WEBB www.metria.se

Innehållsförteckning

1. Bakgrund 3
2. Sammanfattning av tryckt MO-karta 3
3. Avgränsningar och prioriteringar 3
4. FM krav på MO-kartan 4
5. Innehåll i MO-kartans kartbild 5
5.1 Militära verksamhetsobjekt 5
5.2 Bakgrundskarta 7
3.1 Översiktsruta 8
3.2 Nät och besiffring för kartbild 8
4. MO-kartans marginalinformation 9
4.1 Vinjetten 9
4.2 M-nummer 9
4.3 Kompassformel mm 9
4.4 MGRS-ruta 10
4.5 Skalstock 10
4.6 Nät och koordinatsystem 11
4.7 Ajourhållning, tryckuppgift, kartproducent m.m. 11
4.8 Tomt utrymme 12
5. MO-översikt 12
6. Referenser 13
7. Kontakt/frågor 13

1. Bakgrund

NMK Skjutfält är ett gemensamt projekt mellan Försvarsmakten, Fortifikationsverket och Metria. Metria leder projektarbetet som utvecklar och bygger upp en nationell databas för Försvarsmaktens militära övningsområden (MO).

Under år 2010-2011 utvecklades MO-produkterna. Under 2012-2013 togs MO-kartor fram i utgåva 1. Centralt systemsäkerhetsbeslut (FM2013-486:1) och beslut om användning (FM2013-486:2) är fattade 2013-12-03, baserat på processer och rutiner för att utveckla, underhålla och förvalta datamängd och kartprodukter. Godkännande av användning för respektive militärt övningsområde sker via så kallad överlåtelse till individ och utförs av HKV PROD INFRA. Hänvisning till respektive områdes beslut återfinns i databasen via attributen ”Beslutsdatum” och ”Beslutsdokument”. Vidareutveckling och förvaltning av produkterna sker inom fortsatt projektarbete.

IT-lösning har tagits fram för att hantera informationsflöde för insamling och uppdatering till olika uttag, främst för uttag till produktionslinje tryckt MO-karta. Informationen i databasen FM Datalager MO används såväl i kartor, kartverktyg och databaser internt i Försvarsmakten. För relevanta delar används informationen externt till exempel för avisering av uppdaterade gränser till Lantmäteriet och till fastighetsägaren FORTV.

2. Sammanfattning av tryckt MO-karta

Tryckta kartor över militära övningsområden fanns tidigare i lika många varianter som antal militära övningsområden. Projektet NMK Skjutfält syftar bland annat till enhetlig, standardiserad benämning och hantering av information för militära övningsområden. Den tryckta kartan för planering har genomgått utveckling och ensning. Kartan har numera en gemensam layout för alla militära övningsområden d.v.s. skjutfält, övningsfält och marina skjutområden. Kartmallen följer internationell militär standard så långt som möjligt. Kartan innehåller uppdaterade MO-gränser och verksamhetsobjekt. Dessa är insamlade enligt metod baserad på FM krav på positionsnoggrannhet och utgående från fastställd insamlings-instruktion.

Utvecklad produktionslinje tryckt MO-karta levererar färdiga tryckfiler för Försvarsmaktens övningsområdeskartor (MO-kartor) så kallade KartPDF. Produktionslinjen hanterar kartor i skalorna 1:10 000 eller 1:20 000, undantagsvis i skala 1:50 000. Lantmäteriets fastighetskarta används normalt som bakgrundskarta. Tryckt MO-karta levereras i pappersformaten liggande A2, A1, A0 stående A1 eller A0 samt även i format anpassat till områdets form. Produktionslinjen levererar tryckta kartor, KartPDF och GeoPDF. MO-kartan är ett komplement till lokal skjutfältsinstruktion.

3. Avgränsningar och prioriteringar

Projektet har varit tvunget att förhålla sig till begränsande faktorer, t ex ekonomi, tillgängliga personella resurser samt tekniska och organisatoriska riktlinjer inom FM och FORTV. Utgående från FM beställning till Metria har styrgruppen prioriterat verksamheten i syfte att uppnå största möjliga effekt och realiserbarhet med tillgängliga resurser. Utöver den något mer detaljerade styrningen för projektet har följande övergripande avgränsningar och prioriteringar följts:

1. Säkerhet för tredje man (primärt allmänheten)
2. Informationsflöde före teknik
3. Tryckt karta före Digital karta
4. Utvalda områden före alla 151 militära övningsområden (enligt FM VU2011).

Under 2015 och 2016 prioriteras förbandsvis hantering av MO-kartorna. Till och med 2017 är planen att ha hanterat alla ca 150 militära övningsområden i Sverige. Därefter övergår projektet i förvaltning.

4. FM krav på MO-kartan

Krav på produkten Tryckt karta över Försvarsmaktens övningsområden:

Skala

- Planeringskartor ska kunna produceras i skalorna 1: 10 000 och i 1:20 000.

Pappersformat

- Standardformat enligt ISO 216. Pappersformatet ska anpassas till övningsområdets skalpresentation. Val av pappersformat görs mellan A2, A1, A0 samt NMK-format. Liggande eller stående format beror på områdets utsträckning.
- Anpassning av formatet kan göras för övningsområdets fysiska utbredning.

Bakgrundskarta

- Fastighetskartan vektor och specifikation enligt Lantmäteriet
- Följa specifikation för NMK i relevanta delar

Marginalinformation

- Utgå från specifikation enligt Geo SE mall, ”SE1100XX_KabusaSkjutfalt_20k_A1L_U.pdf”

Påtrycksinformation

- Utgå från framtagna internationella militära symboler från projektet Skjutfältskarta.
- Justera påtryckssymboler efter remitterad och fastställd version.

Språk

- Huvudspråk är svenska.
- All svensk text är skrivet i normal (regular) stil, d.v.s. rak text.
- All engelsk text är skrivet i kursivt (*italic*) stil, d.v.s lutande text.

Figur 1. Exempel på norra respektive södra delen av ett kartblad i Nationell Militär Kartserie NMK.

5. Innehåll i MO-kartans kartbild

5.1 Militära verksamhetsobjekt

Kartbilden redovisar militära verksamhetsobjekt på en bakgrundskarta.

I kartbilden återges de militära verksamhetsobjekt som redovisas i teckenförklaringen.

Teckenförklaringen innehåller samtliga standardiserade symboler utan hänsyn till lokala avvikelser. Symbolerna är så långt som möjligt anpassade till internationell militär standard. Engelsk översättning återfinns för varje symbol.

Teckenförklaringen återger de hittills definierade begreppen som har prioriterats att hanteras i ett första skede inom projektet NMK Skjutfält. Prioriteringen har utgått från följande aspekter:

1. Säkerhet för allmänhet
2. Säkerhet för militär
3. Verksamhetsstödjande information

I utveckling av produkten kommer fler begrepp än nuvarande att hanteras.

Viss kartografisk undanhållning av kartsymboler med lågt krav på noggrannhet är gjord för att kartan ska vara läsbar och tydlig.

Gränser för skjutfält och övningsfält Gränslinjernas representation för militära övningsområden i allmänna kartor är för närvarande ofta svåra att urskilja. Linjerepresentation i MO-kartan är framtagen för att gränserna ska vara tydliga även på svenska kartor som innehåller mycket skog och vatten.

MO-kartans gränser för militära övningsområden är genomgångna, uppdaterade och godkända. Gränser representeras med kraftigare linjesymboler än i Lantmäteriets nuvarande allmänna kartor och därmed även i NMK.

Skjutfält redovisas med röd, något genomskinlig linje som åtföljs av en ljusröd mycket genomskinlig linje för att verkligen framhäva skjutfälten. Gräns i terrängen ligger i linje med linjesymbolens innersta del. Gräns för skjutfält baseras på fältinmätta varningsskyltar i terrängen. Övningsfält har en enligt internationell militär standard blå linje. Övningsfältens linjesymbol är något genomskinlig och åtföljs av en mycket genomskinlig ljusblå linje. Gräns för övningsfält är oftast sammanfallande med fastighetsgränser. Ibland är dessa gränser utökade via avtal med andra fastighetsägare än staten och nuvarande fastighetsförvaltare Fortifikationsverket.

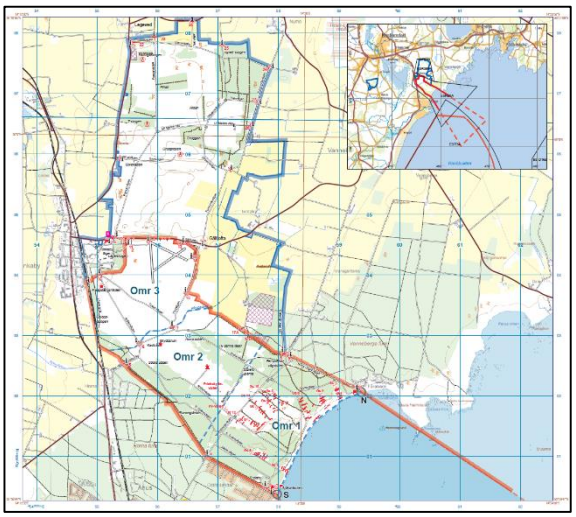

Figur 2. Exempel på MO-kartans kartbild.

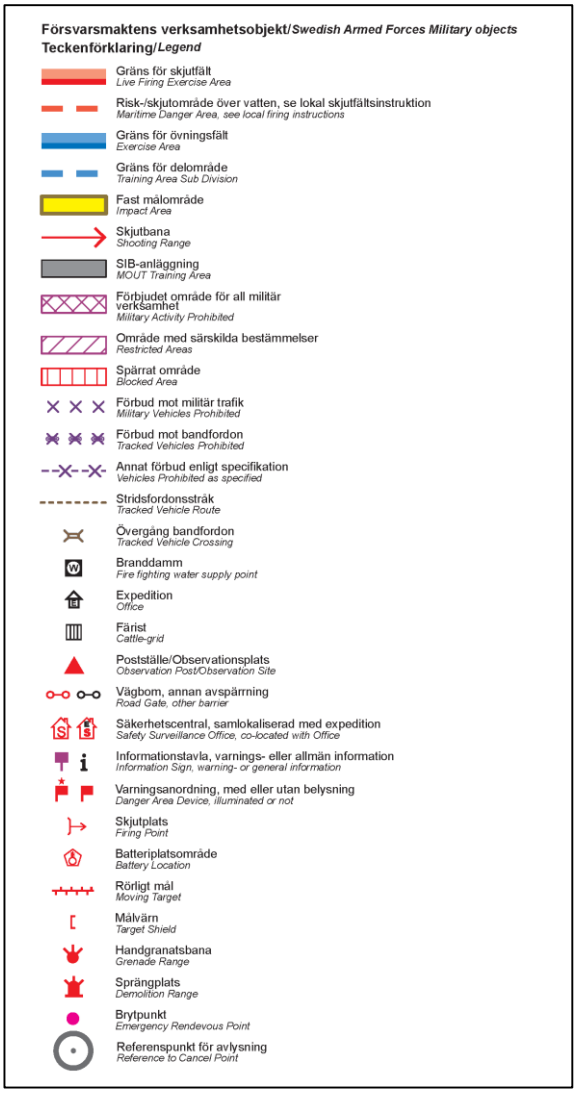

Figur 3. Teckenförklaring för MO-karta utgåva 4, 2017.

Alla militära verksamhetsobjekt är insamlade enligt fastställd insamlingsinstruktion.

Brytpunkt

Definition: i förväg identifierad och i terrängen permanent utmärkt mötesplats. En brytpunkt är en förutbestämd plats dit t.ex. räddningstjänst hänvisas vid en olycka. På denna plats möter personal upp och leder in räddningstjänsten till olycksplatsen.

Brytpunkt anges med karttext och MGRS koordinater i blått, latitud/longitud i brunt och SWEREF 99 TM i grönt. Under brytpunkten anges telefon-nummer till larmtjänst på svenska och engelska.

Brytpunkters koordinater i SWEREF 99 TM används för att kommunicera med civila räddningstjänsten.

Figur 4. FM nya skyltfältsgräns-skylt med hänvisning till skyddslagen 2010:305.

Referenspunkt

För skjutfält med risk/skjut-område över vatten anges referenspunkt för avlysning. Den del av varningsinformationen som är geografiskt kopplad och som är statisk återges i kartmallen, d.v.s. **referenspunkt för avlysning med bäring**. Riskområdets maximala distans redovisas grafiskt, maximal bäring anges i grader från norr.

Referenspunkt för avlysning benämns alltid efter väderstreck, för att inte blandas med övriga punkters eller områdens benämningar eller betydelser i siffror och bokstäver. Väderstrecken förkortas N, S, O, V. Positionsangivelse följer SäkI Ö/S 2010 med hög noggrannhet, d.v.s. latitud/longitud-position anges enligt formatet ”*Grader, Minuter, Sekunder med minst två decimaler*”. Detta säkerställer krav på positionsnoggrannhet under en meter.

Uppgift om position och bäring för referenspunkt för avlysning ska vara identisk med uppgifterna i beslutet om skyddsobjekt för respektive skjutfält. Uppgifter om referenspunkt för avlysning ska även vara identisk hos de myndigheter som Försvarsmakten kommunicerar informationen till allmänheten via d.v.s. Lantmäteri och Sjöfartsverk.

Syftet är att säkerställa att exakt samma information om var farligt område är ges till allmänheten, på samma sätt oavsett varningsmedia, förmedlande myndighet eller aktuellt skjutfält.

För närvarande pågår översyn av vattenområdenas överens-stämmande med skyddsobjektbeslut. Nuvarande gränser i MO-kartan för vattenytor hämtas från Försvarets gamla gränser i Lantmäteriets databaser/Kartor. Justeringar har hittills endast gjorts för enstaka områden.

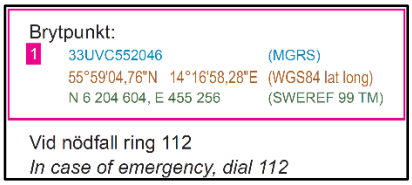

Figur 5. Exempel på redovisning av brytpunkt i MO-kartan.

Figur 6. Exempel på korrekt angiven SWEREF 99 TM-koordinat.

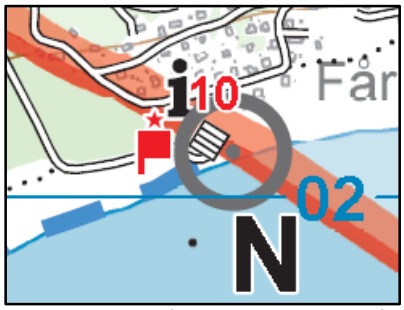

Figur 7. Exempel från Rinkaby skjutfält på referenspunkt för avlysning i kartbilden.

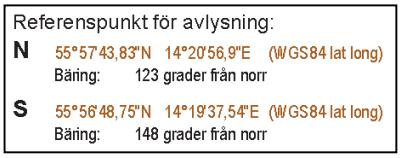

Figur 8. Exempel på referenspunkt för avlysning i teckenförklaring.

Kartobjekt

I MO-kartan finns så kallade ”övrigt-objekt” redovisade i utgåva 3. Därmed ges möjlighet att visa tydligare symboler för kartpunkter, linjer och ytor, till exempel för Utgångspunkt i terrängen eller traktorväg.

Figur 9. Exempel på kartpunkter.

5.2 Bakgrundskarta

Kartbildens bakgrundskarta utgörs av data från Lantmäteriets GSD-Fastighetskarta.

Fastighetskartan är den mest detaljerade karta som finns nationellt. Den visar bland annat byggnader, markslag, vägar och fastighets-gränser. För fullständig dokumentation av bakgrundskartans symbolisering, linjetjocklek och färgsättning hänvisas till Lantmäteriets dokumentation för Fastighetskartan.

Skillnader mellan MO-kartan och tryckt fastighetskarta är:

- Flygbild som bakgrund borttagen vilket ger en tydligare karta
- Administrativ indelning och fastighets-information är borttagna vilket ger en tydligare karta

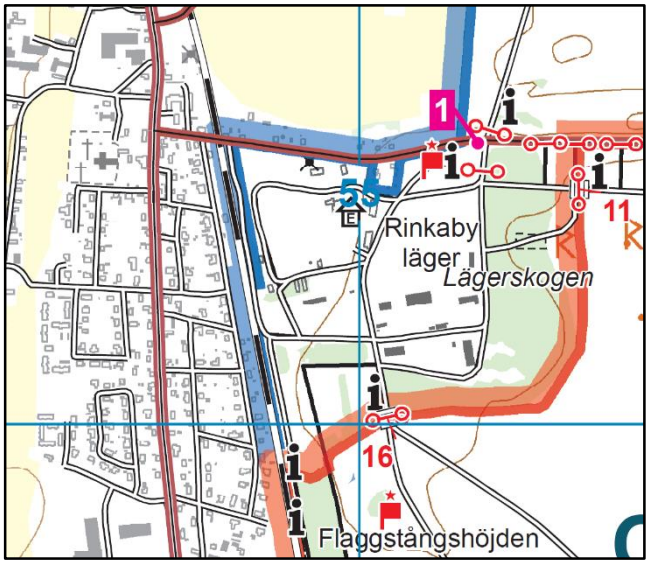

Figur 10. Exempel på kartdetalj från Rinkaby skjutfält.

Avvikelser från Lantmäteriets tryckta fastighetskarta har enbart gjorts i färgval av ytor och vissa linjer, vägar och höjdkurvor. Främsta anledningen till dessa avvikelser är att rutnäten ska framträda tydligare.

I möjligaste mån har anpassning av färger och manér gjorts för att efterlikna NMK-serien.
Anpassning har gjorts för:

Skog: Barr, blandskog och lövskog
Skogsytorna har samma ljusa gröna färg oavsett skogsklass

Öppen mark: Åkermark och fruktodling
Redovisas med en ljusare gul färg.

Bebyggelse: Sluten, hög, låg bebyggelse samt fritidsbebyggelse
Bebyggelse har justerats från magentatoner till orange-bruna toner på grund av att färgen magenta ofta används för FM påtrycksinformation.

Väg: Motorväg och allmän väg
Vägar är brunröda för att detta syns bra i dagsljus/vitt ljus och går att urskilja med hjälp av rödljus.

Höjdkurvor
Anpassad till färger enligt NMK specifikation.

För att framhäva själva det militära övningsområdet har kartbilden utanför områden tonats ned med en svag transparent vit färgnyans.

Bakgrundskartan ajourhålls av Lantmäteriet via flygbildstolkning. När projektet NMK Skjutfält upptäcker saknad eller felaktig information felanmäls det till Lantmäteriet. Process för att omhänderta dessa felanmälningar pågår. För mer information hänvisas till www.lantamateriet.se

Tidigare har orienteringskartor med mycket hög detaljrikedom ofta utgjort karta för Försvarets militära övningsområden. Orsak till att Försvaret inte fortsätter använda orienteringskartor som bakgrundskarta:

1. Orienteringskartor produceras inte nationellt, dvs saknas utanför övningsområdet.
2. Ägare till databas/karta och copyright är oftast lokal orienteringsklubb.
3. Fokus är på detaljer för orientering och inte på militär verksamhet.

3.1 Översiktsruta

MO-kartan kompletteras ofta med en liten översikts-ruta. Ursprungliga syftet var att de skjutfält som har risk/skjut-område över vatten får hela yttre gräns redovisad. Nu har alla MO-kartor med behov därav en översiktsruta. Nu redovisas även Luftfartsverkets R/D-områden.

Översiktsrutan innehåller Lantmäteriets översiktskarta i skala 1:250 000 med pålagrad MO-gräns och R/D-områden.

Översiktsrutan placeras i lämpligt hörn av kartbilden.

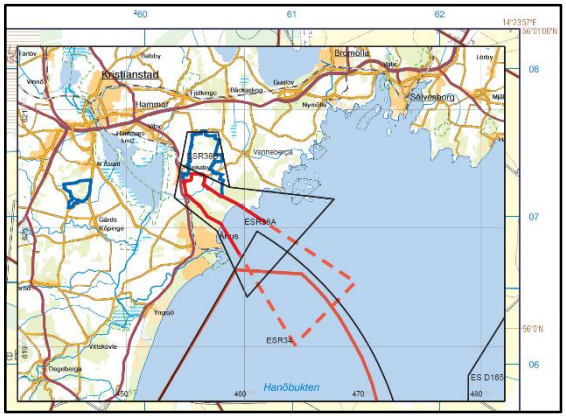

Figur 11. Exempel på översiktsruta för Rinkaby skjutfält.

3.2 Nät och besiffring för kartbild

Följande koordinater visas i kartbilden:

- **Huvudnät: UTM**
  (den zon där huvuddelen av området ligger). Nät och besiffring i blått. Kilometersiffror anges för varje kilometer i kartbilden.
- **MGRS**
  MGRS är ett positionsrapporterings-system med UTM som bas. Utläses från UTM-nätet med hjälp av MGRS-rutan.
- **Latitud/longitud**
  (WGS 84). Nät och besiffring i brunt. Täthet på nätet är fem minuter. För varje hörn på kartbladet finns en lat/long-koordinat utskriven med en sekunds noggrannhet. Besiffring är i samma bruna färg som gradnätet och anges med hela grader och minuter vid respektive linje längs med yttre kanten av kartbild.

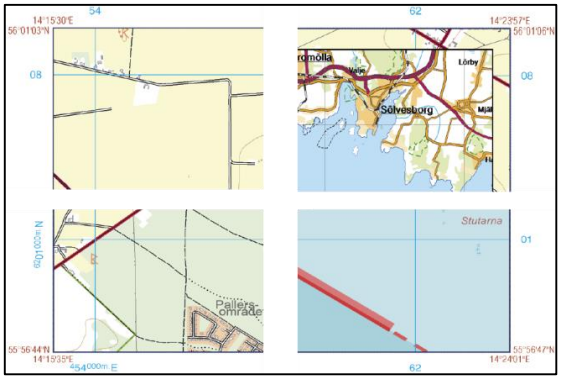

Figur 12. Exempel från Rinkaby på nätredovisning och besiffring i kartbildens fyra hörn.

Fullständigt utskrivna koordinater finns i kartans nedre vänstra hörn. Dessa är också utskrivna på ett korrekt format för respektive system.

För mer information om nätens linjetjocklekar, färger, siffror och textstorlekar hänvisas till dokumentation av specifikation för NMK-serien.

SWEREF 99

WGS 84 och SWEREF 99 lat/long sammanfaller inom en meter, d.v.s. skillnaden mellan dessa två system understiger mätbarheten i kartan. Dessa system anses dessutom kunna likställas enligt NATO STANAG 2211 (ed 6). Därav följer att UTM zon 33 och SWEREF 99 TM också är i praktiken ekvivalenta.

För mer information hänvisas till facklitteratur, Lantmäteriets hemsida:
http://www.lantmateriet.se/geodesi

eller Geo SE praktiska och tydliga sammanställningar.

4. MO-kartans marginalinformation

4.1 Vinjetten

Vinjetten finns högst upp i kartans högra del.
I vinjetten anges MO-identitet och namn på det skjutfält eller övningsfält kartan gäller för, samt vilken skala kartan är framtagen i. Vinjettfärgen är gul.

Figur 13. Exempel på vinjett.

I vinjetten finns en vit så kallad ”NATO-ruta” med vertikal text. Där anges:

- **Serie**: MO-kartorna är ännu inte placerade i kartserier över militära områden enligt STANAG 7136, platshållare för NATO-kod finns dock.
- **Blad**: exempel: MO3007-P-1, dvs. en planeringskarta (P) över MO3007 (Rinkaby skjutfält).
- **Utgåva**: Anger vilken kartutgåva som är aktuell, för 2015 var det utgåva 2, för 2016 är det utgåva 3.

Under vinjetten anges när datamängden för militär verksamhetsinformation senast blev ajourhållen (ÅÅÅÅ-MM).

4.2 M-nummer

M-nummer återfinns vertikalställt till höger om rubriken SVERIGE/*SWEDEN* ovanför vinjetten. Förrådsbeteckning (M-nummer) är den beteckning som inom Försvarsmakten används i samband med tilldelning, förrådshållning, redovisning, felrapportering och intern beställning av Försvarsmaktens förnödenheter. FMV ansvarar för framtagning och registrering av M-nummer. M-nummer tillförs MO-kartorna i produktionslinjen.

Figur 14. Exempel på M-nummer.

Ett M-nummer ska motsvara en unik artikel. M-nummer exempel: M7716-940008.

4.3 Kompassformel mm

De områden som har behov av motsvarande information som finns på NMK gällande kompassformel, meridiankonvergens och magnetisk deklination, har detta redovisat i kartmarginalen ofta mellan brytpunkterna och MGRS-rutan. Informationen om missvisning hämtas från SGU, meridiankonvergens räknas ut enligt GeoSE instruktion.

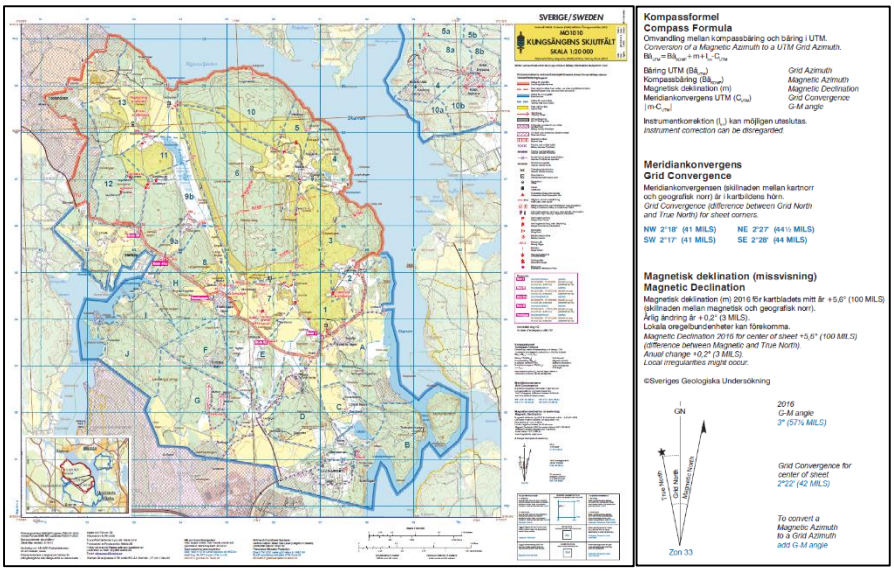

Figur 15. Exempel från Kungsängen, det första området med behov av kompassinformation mm.

4.4 MGRS-ruta

MGRS-ruta finns längst ner till höger i kartans marginal. MGRS-rutans främsta syfte är att ge ett exempel på hur man tar ut en MGRS-koordinat.

Punkten i exemplet skall alltid vara Brytpunkt nummer ett (1).

Det finns ett par olika varianter på hur en MGRS-ruta kan vara utformad. MO-kartan (och NMK) använder sig av den version som är mest frekvent på NATO-kartor och som dessutom förordas i DMA TECHNICAL MANUAL 8358.1, men med svensk text tillagd.

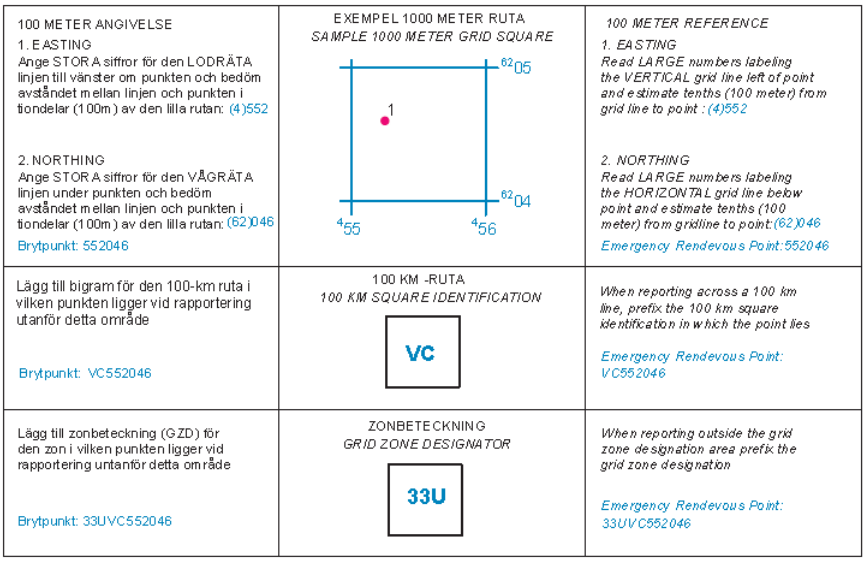

Figur 16. Exempel på MGRS-ruta för positionsangivelse.

4.5 Skalstock

Skalstock finns för tre olika skalområden. Skalstocken ger möjlighet att mäta avstånd i fyra enheter; meter, yards, statute miles samt nautical miles. Följande definitioner av enheterna används:

International Yards En international yard motsvarar 0,9144 meter. En international mile motsvarar 1 760 international yards.

Statute Miles Baseras på US Survey foot och inte på international foot. En survey foot har längden 1200/3937, vilket är något längre än en international foot. En statute mile motsvaras av 5280 survey feet, vilket är ca 1 609,347219 meter. Till skillnad mot en international mile som är exakt 1 609,344 meter.

Nautical Miles En internationell nautisk mil motsvarar 1 852 meter.

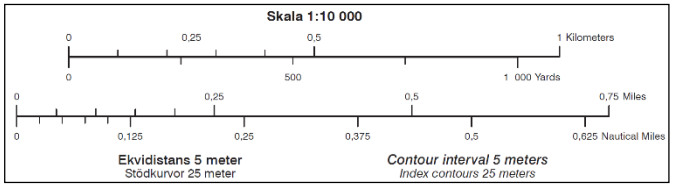

Figur 17. Skalstock 1:10 000

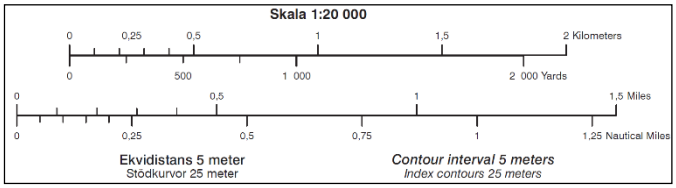

Figur 18. Skalstock 1:20 000

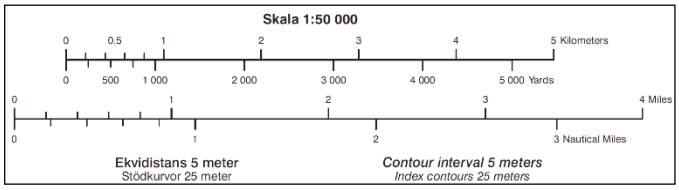

Figur 19. Skalstock 1:50 000

Under skalstocken anges ekvidistans för höjdkurvor. För att förtydliga informationen om höjdkurvors ekvidistans är var femte linje i kartbilden något tjockare, dessa höjdkurvor kallas för stödkurvor.

4.6 Nät och koordinatsystem

Information om nät och koordinatsystem finns i kartmarginalens nedre del.

Rutnäten på kartbilden är baserat på projektionssystemet UTM (Universal Transversal Mercator). Produkterna visar data i UTM zon 32, 33 eller zon 34 beroende på det militära övningsområdets läge i Sverige. På Tryckt karta, KartPDF och GeoPDF visas två rutnät, ur dessa kan man utläsa koordinater i UTM/MGRS samt i WGS84 lat/long.

Nät och koordinatsystem	***Grid and Coordinate Systems***
Höjd anges i meter över havets medelnivå	*Vertical Datum: Mean Sea Level (Heights in meters)*
Geodetiskt referenssystem: WGS 84	*Horizontal Datum: WGS 84*
Transversal mercatorprojektion	*Transverse Mercator Projection*
Blått 1000 m UTM rutnät baseras på WGS 84	*Blue UTM 1000 meter grid refers to WGS 84*
Besiffring i BLÅTT anger UTM zon 33	*BLUE numbering indicates UTM Zone 33*
BRUNT 5' gradnät är i WGS 84	*BROWN 5' graticule refers to WGS 84*

Figur 20. Exempel information i kartmarginal avseende nät och koordinatsystem.

4.7 Ajourhållning, tryckuppgift, kartproducent m.m.

Information om ajourhållning avseende militär verksamhetsinformation finns under vinjetten.

Militär verksamhetsinformation ajourhållen/*Military information revised:* 2015-12

Figur 21. Exempel på uppdateringsinformation under vinjett.

Information om ajourhållning avseende bakgrundskarta återfinns i kartmarginalens nedre vänstra del. Angivelsen skrivs ut enligt formatet ÅÅÅÅ-MM.

Tryckuppgift anges alltid enligt Tryckfrihetsförordningen SFS 2002:908. I 4 kap. 2 § anges att en tryckt skrift "*skall innehålla tydliga uppgifter om vem som har tryckt eller eljest mångfaldigat skriften samt om ort och år för mångfaldigandet, om skriften är avsedd att utgivas i riket*".

Det finns även e-postadress till Metrias GIS-support. Inkomna frågor eller kommentarer på kartan återkopplas till Metria och hanteras fortlöpande

Försvarsmaktens NMK MO utgiven FM2014-5355 *Armed Forces NMK MO published FM2014-5355* Bakgrundskarta ajourhållen/ *Base Map revised:* 2015-11 Kartbakgrund från GSD-Fastighetskartan ©Lantmäteriet, Gävle Försvarsmaktens medgivande behövs för mångfaldigande eller återgivande av denna karta	Kartbild i UTM zon 33 Höjdsystem är RH 2000 Tryck/*Print:*Gefle Karttryck AB, Gävle 2015 Producerad av/*Produced by*: Metria AB Frågor skickas till/ *Please refer any questions to:* Leverantör av NMK Skjutfält Metria AB. Epost: gis-support@metria.se Kartan är anpassad för utskrift i A2-format +4,5 cm i höjd

Figur 22. Exempel på information om ajourhållning, tryckuppgift, kartproducent mm i kartmarginal.

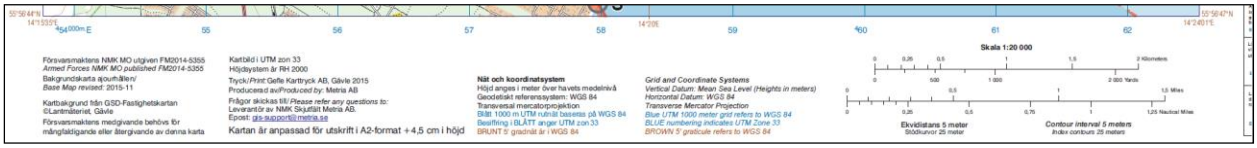

Figur 23. Exempel MO-kartans hela marginalinformation i kartans nedre del.

4.8 Tomt utrymme

Det tomma utrymmet till höger om den generella teckenförklaringen kan användas till nya, utökade begrepp samt till framtida lokalt kompletterad teckenförklaring.

Figur 24. Utrymme för bland annat nya och/eller lokala begrepp.

5. MO-översikt

För de områden som har behov av översikt tas den fram i skala 1:50 000 med väldigt avskalad information. Den verksamhetsinformation som en MO-översikt innehåller är gränser, expedition, säkerhetscentral och brytpunkt samt för skjutfält med skjut/risk-område över vatten även referenspunkt för avlysning. Syftet med översikten är att man ska få en överblick av det geografiska området, se angränsande orter och vägar. Exempel på områden som har översikt är Boden övningstriangel, Kungsängen, Eksjö, Skillingaryd och Rinkaby-Norra Åsum.

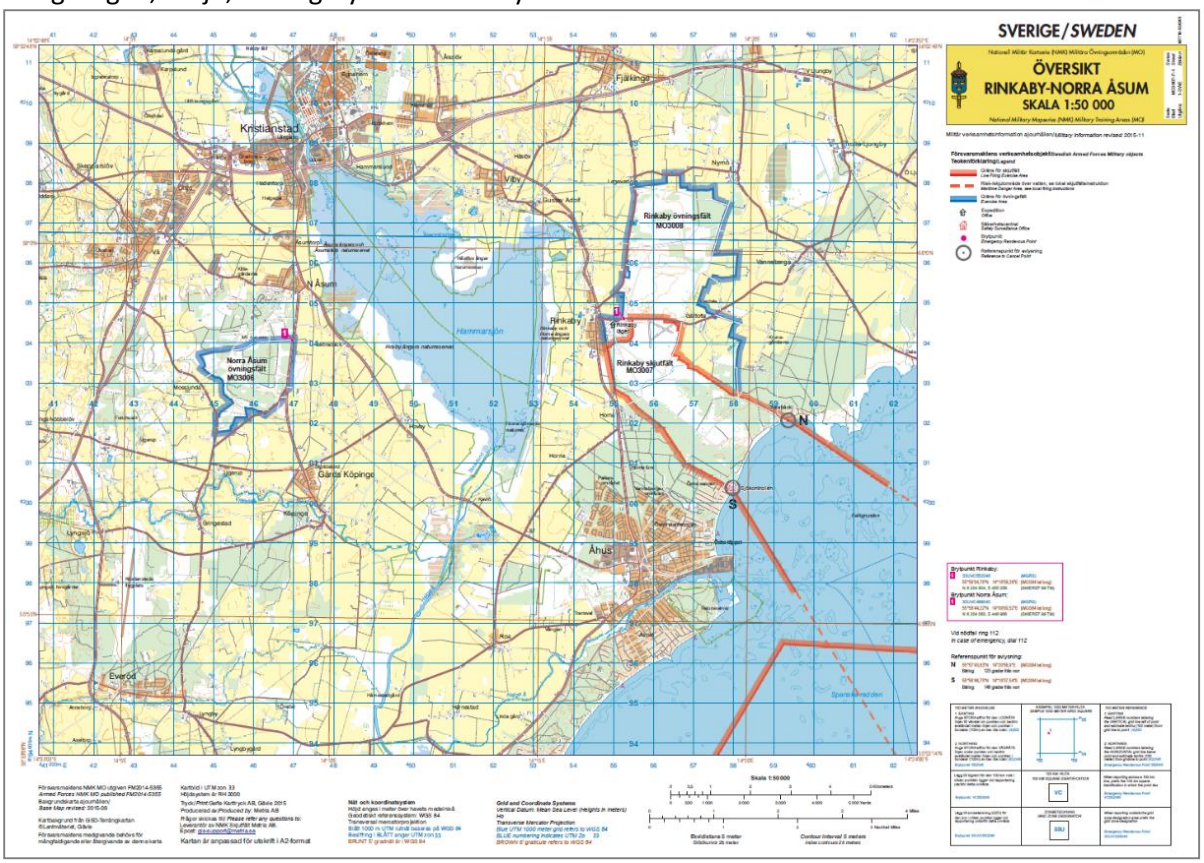

Figur 25. Exempel på MO-översikt för Rinkaby och Norra Åsum.

6. Referenser

1. Produktbeskrivning_MO-kartan v2
2. Produktbeskrivning_Databasuttag MO-karta_v2
3. Lathund GeoPDF v1_3
4. MO-kartan-uppdatering och utgåva.pdf
5. Beskrivning_NMK_M717_ver2_1
6. NATO, STANAG 2211 Geodetic datums, ellipsoids, grids and grid references
7. NATO, STANAG 3666 Maximum sizes for, maps, aeronautical charts and other geospatial products (excluding nautical charts).
8. NATO, STANAG 3676 Marginal information on land maps, aeronautical charts and photomaps
9. NATO, STANAG 7136 Identification of land maps, air charts, digital datasets and media containing datasets (excluding hydrographic products)
10. SS-ISO 31 Storheter och enheter
11. Försvarsmaktens grafiska profil (M7743-704051)
12. ISO 216:2007 definierar pappersformat A-format

7. Kontakt/frågor

För frågor rörande projektet NMK Skjutfält hänvisas till informationsägare HKV PROD INFRA: lennart.fischerstrom@mil.se eller till Metrias projektledare karin.fridstrand@metria.se

För frågor angående MO-produkterna eller för stöd med uppdatering av verksamhetsobjekt i databasen kontakta Metria, gis-support@metria.se

Respektive skjutfältschef kan bäst svara på innehållsfrågor rörande verksamhetsobjekten

För frågor rörande bakgrundskartan hänvisas till Lantmäteriet, Geo SE: geo-se@lm.se

För beställning av tryckta kartor:

1. Gör en kundvagn i Prio.
2. Ange företag som skall leverera: METRIA, ange referens Karin Fridstrand, tele växel 010-121 80 00.
3. Ange kartans namn och M-nr samt antal.
4. Ange leveransadress och kontaktperson.
5. Beställningen går nu till FMV inköp, som lägger en inköpsorder till Metria med faktureringsuppgifter. Metria ser till att kartorna trycks och de levereras direkt från tryckeriet till angiven leveransadress.

För tillgång till övriga produkter d.v.s KartPDF, GeoPDF och dokumentation hänvisas till egen nedladdning från Försvarsmaktens intranät EMILIA och där via HKV PROD INFRA Skjutfältsportal START-JOBBSTÖD-SAMARBETSYTOR-FÖRSVARSMAKTENS ÖVNINGS-OCH SKJUTFÄLT SAMT SKJUTBANOR-NMK SKJUTFÄLTSKARTOR.