

Fickminne, SoK 2017
M7737-366625

Kompassen – hjälpmedel för kartläsning

Ta ut kompassriktning

1. Lägg kompassen på kartan med ena hjälplinjen eller kanten över den punkt där du står och över den punkt dit du ska. Marsch-riktningspilen ska peka åt det håll du ska förflytta dig.
2. Vrid kompasshuset så att N pekar mot kartans norr. Kompasshusets hjälplinjer blir då parallella med meridianerna.

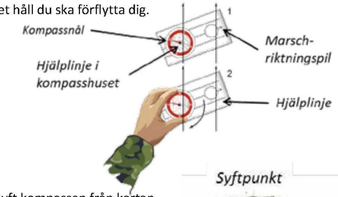

3. Lyft kompassen från kartan och håll den vågrätt framför dig. Vrid kompassen så nålen pekar mot N på kompasshuset.
4. Välj en syftpunkt i terrängen i linje med marschriktnings-pilen. Förflytta dig till den punkten och välj sedan ny syftpunkt på samma sätt.

Här är jag, men huset där borta, var finns det på kartan?

1. Syfta
- Rikta kompassens marschriktningspil mot målet (huset i detta fall).
- Vrid kompasshuset tills den röda pilen pekar mot N i kompasshuset.

2. För över riktningen
- Lägg kompassen med ena kanten över din position på kartan.
- Vrid **hela** kompassen tills meridianerna blir parallella med kompasshusets hjälplinjer. N på kompasshuset ska peka mot norr på kartan.
- Rita vid behov en linje på kartan från din position längs kanten på kompassen.

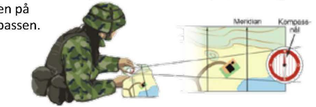

3. Identifiera målet längs kanten på kompassen, alternativt längs den ritade linjen

Notera Denna metod kan även användas omvänt för att hitta din position utifrån identifierade punkter i terrängen. Med fördel ritas då 2-3 linjer och din position hamnar då i skärningen av dessa linjer.

Avståndsbedömning

Vid god sikt kan man uppskatta avstånd genom att dela upp sträckan man ser. Till exempel dungen är 100 meter bort, kyrkan 3 gånger så långt bort – avstånd 300 meter.

Under förflyttning kan man räkna dubbelsteg. Gående i lättframkomlig terräng är det normalt med **cirka** 50 – 70 dubbelsteg per 100 meter beroende på packning med mera.

Att klocka sin förflyttning är ett alternativ, cirka 10 - 15 minuter/kilometer är normalt vid gång i lättframkomlig terräng.

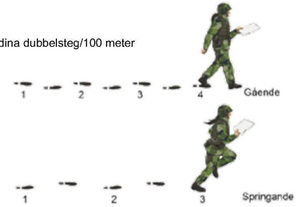

GPS

GPS är ett användbart hjälpmedel för navigering. Tänk på att:
- Noggrannheten för enklare GPS kan variera med 5 – 10 meter.
- I bebyggelse (höghus, tunnlar med mera) fungerar GPS-mottagare mindre bra.
- Kontrollera batteriets laddningsnivå regelbundet.
- Verifiera din position i förhållande till hela rutten genom att zooma ut regelbundet.

Positionsangivning – MGRS

1. Ta reda på GZD. Anges i Sverige med två siffror och en bokstav i kartans marginaler. I exemplet nedan är GZD = 33V
2. Identifiera vilken tiomilaruta du befinner dig i. Ta reda på dess bigram, två bokstäver, WC i nedanstående.
3. Mät Easting värde (östlig riktning). Börja med att ange värde från det vertikala rutnätet och komplettera sedan med en siffra för 100 meter noggrannhet eller två siffror för 10 meter.
4. Mät Northing värde (nordlig riktning) på samma sätt. Börja med att ange värde från det horisontella rutnätet och komplettera sedan med en siffra för 100 meter noggrannhet, eller två siffror för 10 meter.
5. Kombinationen av dessa är positionen i MGRS.

10 meter MGRS koordinat för väg/stig korsningen

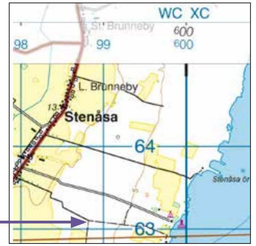

33VWC98826310

Soldaten och kartan

Fickminne 2017

FÖRSVARSMAKTEN

Kartskalor

En enkel tumregel vid omvandling av skalan:
Stryk de två sista siffrorna i skalan. Du får då centimeter på kartan översatt till meter i terrängen.
Till exempel 1:50 0~~00~~ (1 cm = 500 m)

Höjdkurvor

Ekvidistans (*eng Contour*) är nivåskillnader i meter mellan två höjdkurvor på kartan. NMK50 har 5 meters ekvidistans.

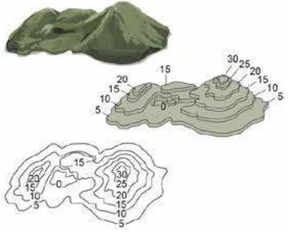

Skissritning och fotografier

Exempel på skiss

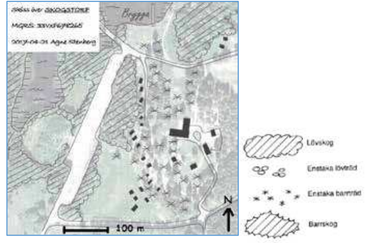

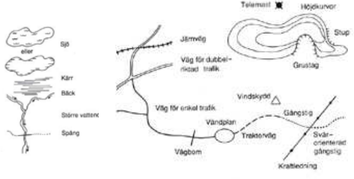

Notera. Bilder och ortofoton (flygbilder) är komplement och/eller alternativ till kartor. De är även bra underlag för skisser.

Kartläsning

Passa kartan – orientera kartan mot norr

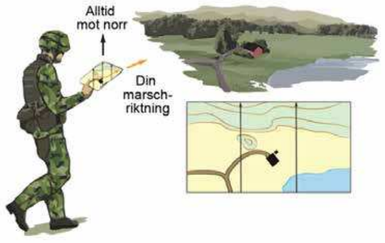

Fakta!
Kartans texter är alltid rättvända relativt kartans norr.

Några vanliga tecken ur NMK50

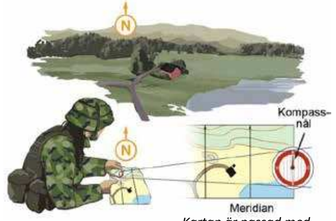

Kartan är passad med hjälp av kompassnålen.

Tumgreppet

Med hjälp av tumgreppet markerar du var på kartan du befinner dig. Tumgreppet används för att underlätta kartläsning under förflyttning.

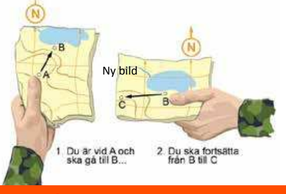

Observera!
Vrid inte på kartan! Håll kartan mot norr och flytta dig själv i förhållande till kartan i stället.

Kom ihåg vid kartläsning

- Använd tydliga ledstänger vid förflyttning, särskilt nattetid.
- Planera din färdväg och håll dig sedan till planen.
- Förenkla i kartbilden, använd tydliga höjder och föremål.
- Pricka av och memorera föremål du passerar.
- Använd säkra utgångspunkter inför finläsning mot målet.
- Använd och lita på kompassen. Särskilt vid svåra förhållanden med begränsad sikt.
- Håll kompassen på avstånd från magnetiska föremål (exempelvis vapen).
- Missvisning har ofta liten betydelse inom Sverige vid förflyttningar i terrängen.

Om du går fel

- Stanna!
- Tänk efter!
- Passa kartan
- Vilket var det senaste stället där jag var säker på min position? Hur långt har jag förflyttat mig sedan dess?
- Finns det något stort och tydligt föremål i närheten som jag kan använda för att läsa in mig? Vilken är riktningen mot föremålet i förhållande till min position?