Vi kommer att vara inne …



… och i mån av tid utomhus

MÅL

Målet är att ni ska ta era första steg mot att kunna:

- läsa en karta
- använda karta och kompass i terrängen

SYFTE

Syftet är för att ni ska kunna

- orientera er på en karta
- orientera er i terrängen med hjälp av en karta.

KRAV

Kravet är att ni ska känna till och ha viss förståelse i ATT:

- kartor har en kartskala (ex 1:50 000)
- kartor har fyra grundriktningar (ex NORR) och
- kartor har symboler (ex väg).

Ni ska med hjälp "tumregeln" kunna ta er från en punkt (ex 1) till en annan (ex 2) i terrängen med hjälp av karta och kompass.

Kartskalor

En enkel tumregel vid omvandling av skalan:
Stryk de två sista siffrorna i skalan. Du får då centimeter på kartan översatt till meter i terrängen.
Till exempel 1:50 0~~00~~ (1 cm = 500 m)

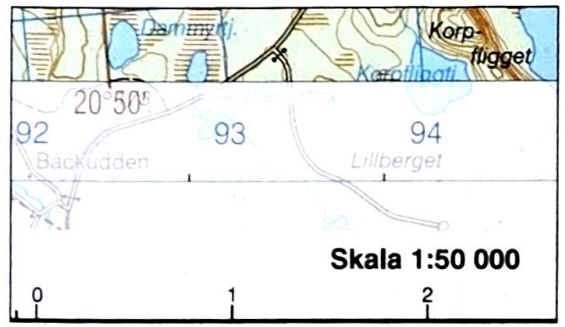

Höjdkurvor

Ekvidistans (*eng Contour*) är nivåskillnader i meter mellan två höjdkurvor på kartan. NMK50 har 5 meters ekvidistans.

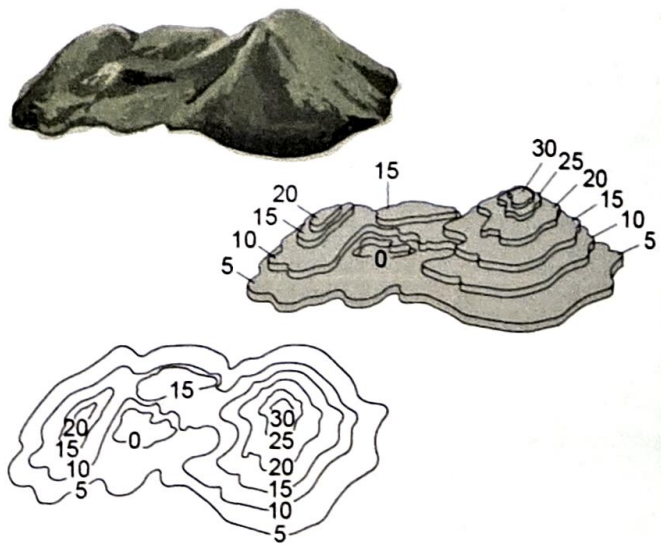

Skissritning och fotografier

Exempel på skiss

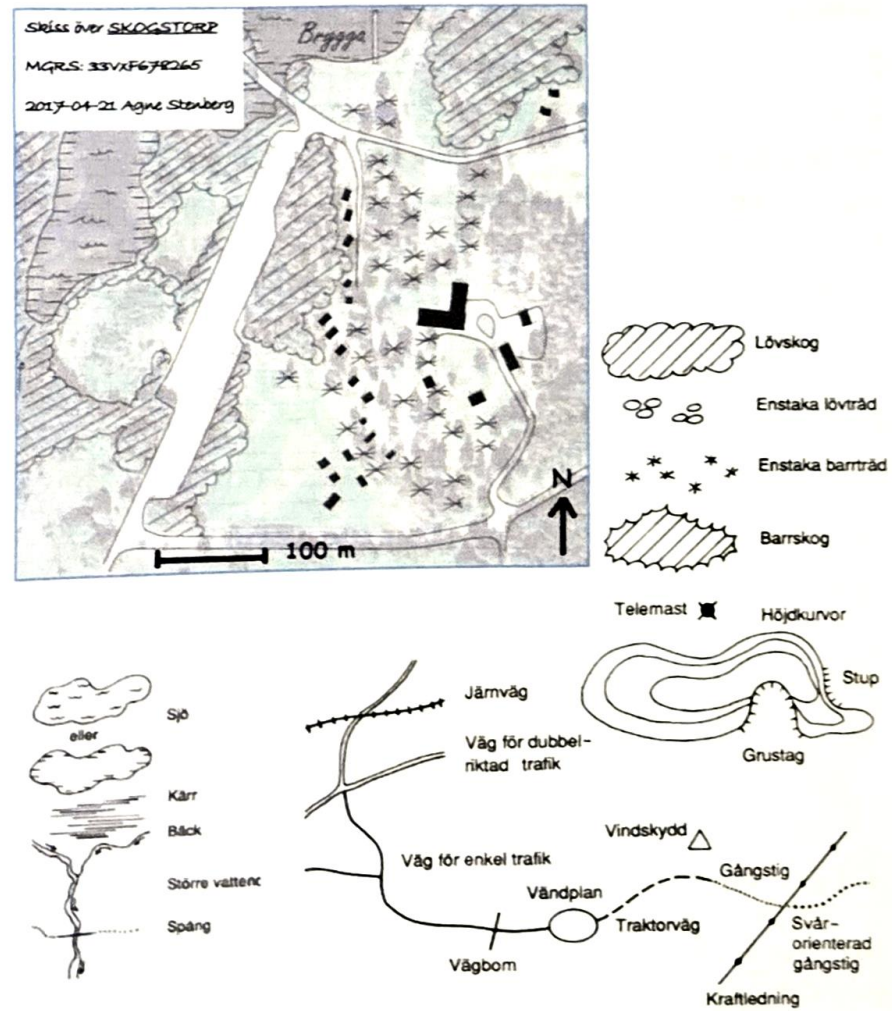

Notera. Bilder och ortofoton (flygbilder) är komplement och/eller alternativ till kartor. De är även bra underlag för skisser.

VISA

Kartskalor

En enkel tumregel vid omvandling av skalan:
Stryk de två sista siffrorna i skalan. Du får då centimeter på kartan översatt till meter i terrängen.
Till exempel 1:50 0~~00~~ (1 cm = 500 m)



Höjdkurvor

Ekvidistans (*eng Contour*) är nivåskillnader i meter mellan två höjdkurvor på kartan. NMK50 har 5 meters ekvidistans.

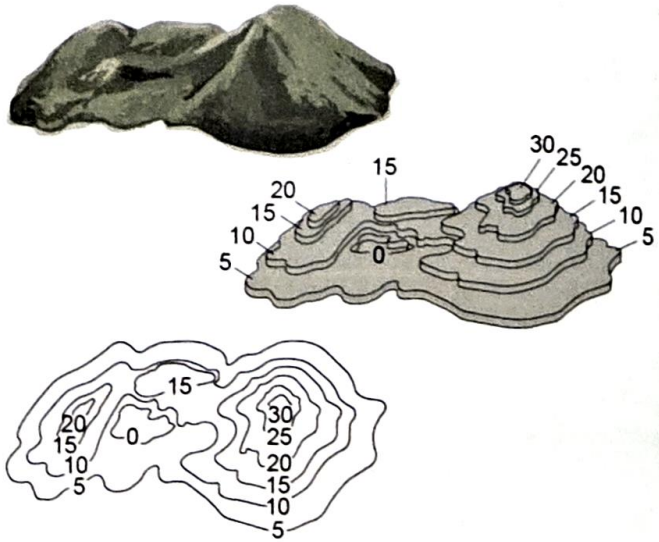

Skissritning och fotografier

Exempel på skiss

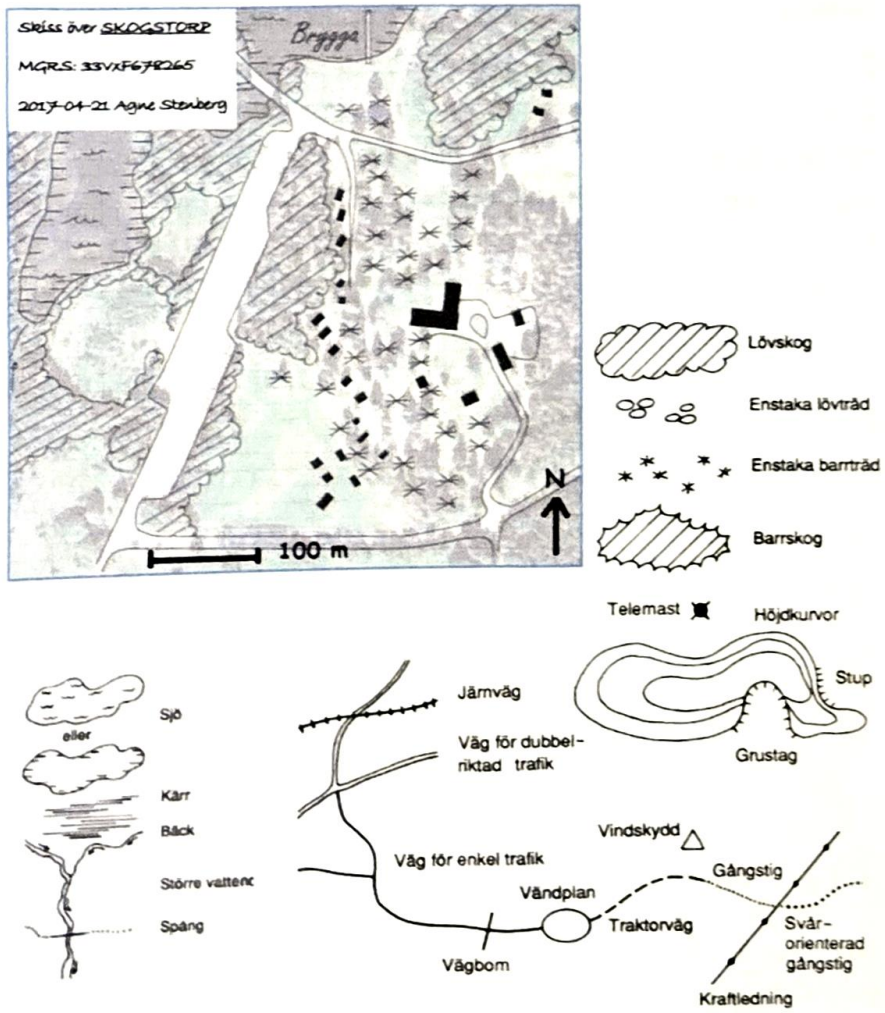

Notera. Bilder och ortofoton (flygbilder) är komplement och/eller alternativ till kartor. De är även bra underlag för skisser.

Kartskalor

En enkel tumregel vid omvandling av skalan:
Stryk de två sista siffrorna i skalan. Du får då centimeter på kartan översatt till meter i terrängen.
Till exempel 1:50 0~~00~~ (1 cm = 500 m)



Höjdkurvor

Ekvidistans (*eng Contour*) är nivåskillnader i meter mellan två höjdkurvor på kartan. NMK50 har 5 meters ekvidistans.

VISA

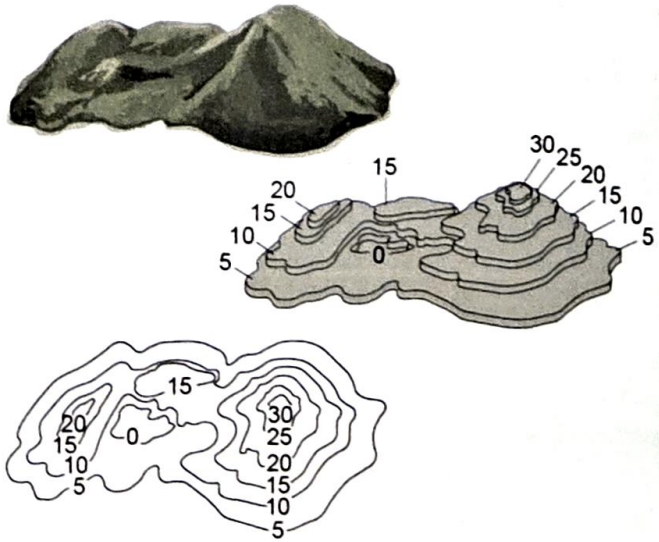

Skissritning och fotografier

Exempel på skiss

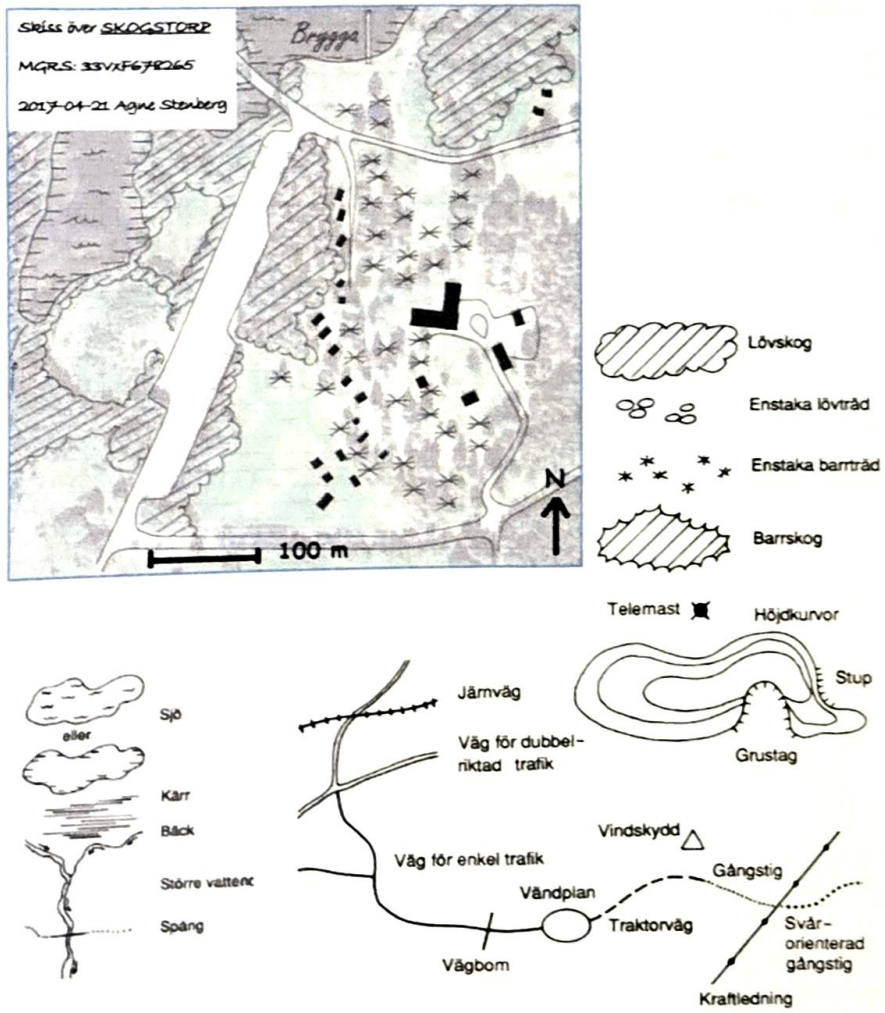

Notera. Bilder och ortofoton (flygbilder) är komplement och/eller alternativ till kartor. De är även bra underlag för skisser.

Kartskalor

En enkel tumregel vid omvandling av skalan:
Stryk de två sista siffrorna i skalan. Du får då centimeter på kartan översatt till meter i terrängen.
Till exempel 1:50 0~~00~~ (1 cm = 500 m)



Höjdkurvor

Ekvidistans (*eng Contour*) är nivåskillnader i meter mellan två höjdkurvor på kartan. NMK50 har 5 meters ekvidistans.

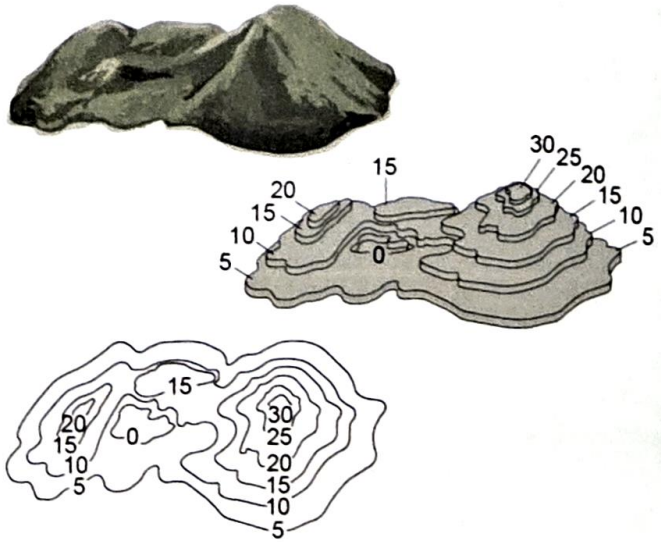

Skissritning och fotografier

VISA

Exempel på skiss

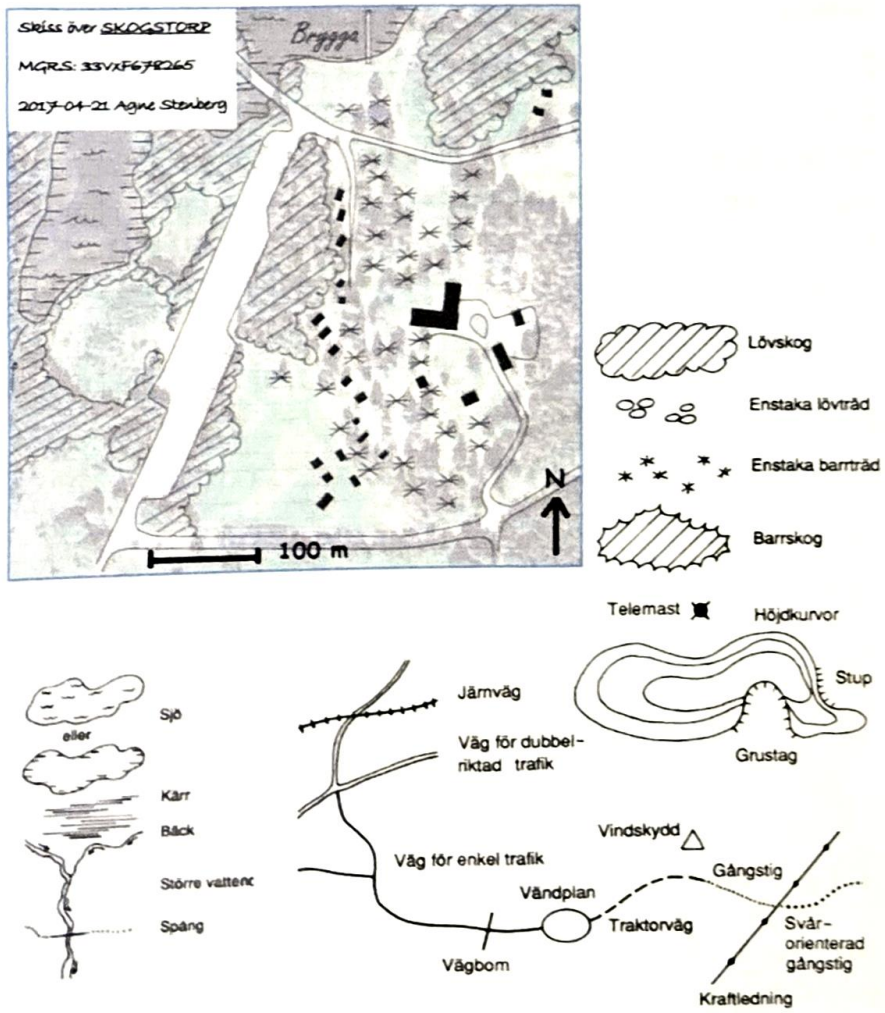

Notera. Bilder och ortofoton (flygbilder) är komplement och/eller alternativ till kartor. De är även bra underlag för skisser.

ÖVA PÅ

- KARTSKALOR
- HÖJDKURVOR
- SKISSRITNING

Skissritning och fotografier

Exempel på skiss

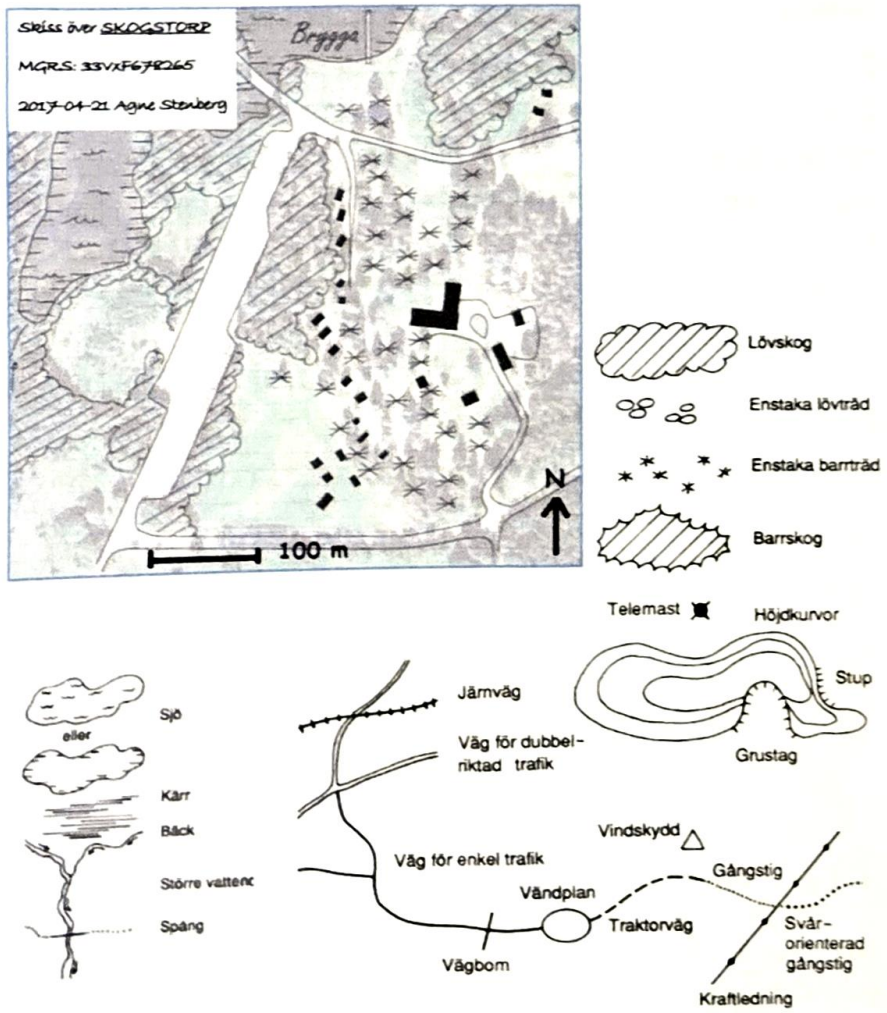

Notera. Bilder och ortofoton (flygbilder) är komplement eller alternativ till kartor. De är även bra underlag för skissen.

VALFRITT PAPPER

Kartläsning

Passa kartan – orientera kartan mot norr

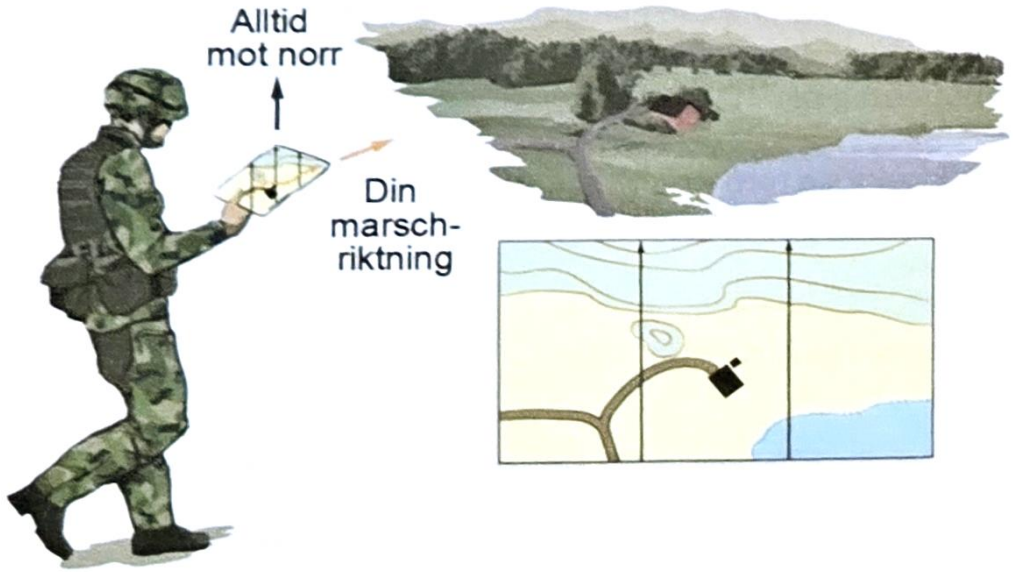

Fakta!
Kartans texter är alltid rättvända relativt kartans norr.

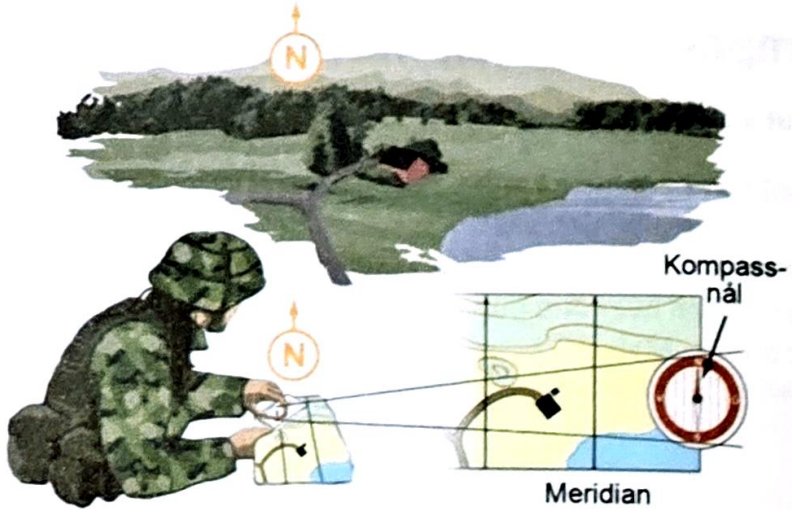

Kartan är passad med hjälp av kompassnålen.

Tumgreppet

Med hjälp av tumgreppet markerar du var på kartan du befinner dig. Tumgreppet används för att underlätta kartläsning under förflyttning.

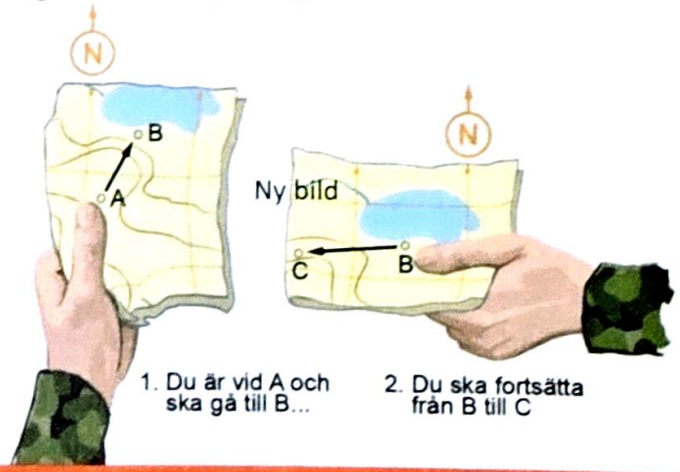

Observera!
Vrid inte på kartan! Håll kartan mot norr och flytta dig själv i förhållande till kartan i stället.

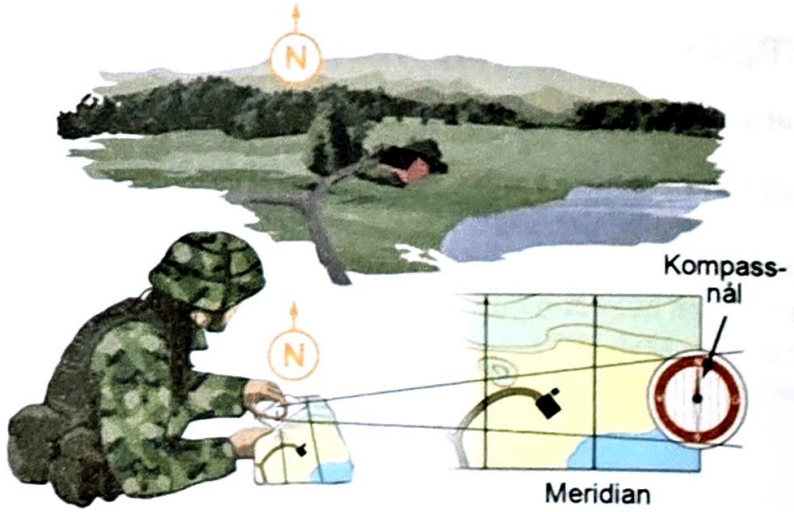

Kartan är passad med hjälp av kompassnålen.

Tumgreppet

Med hjälp av tumgreppet markerar du var på kartan du befinner dig. Tumgreppet används för att underlätta kartläsning under förflyttning.

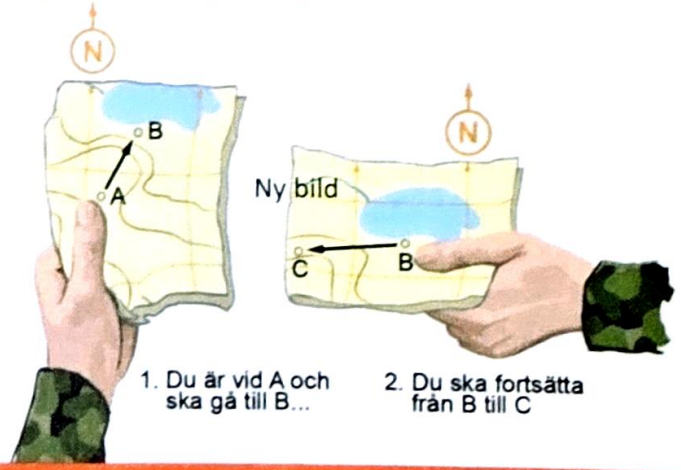

1. Du är vid A och ska gå till B...

2. Du ska fortsätta från B till C

Observera!
Vrid inte på kartan! Håll kartan mot norr och flytta dig själv i förhållande till kartan i stället.

JAG VISAR



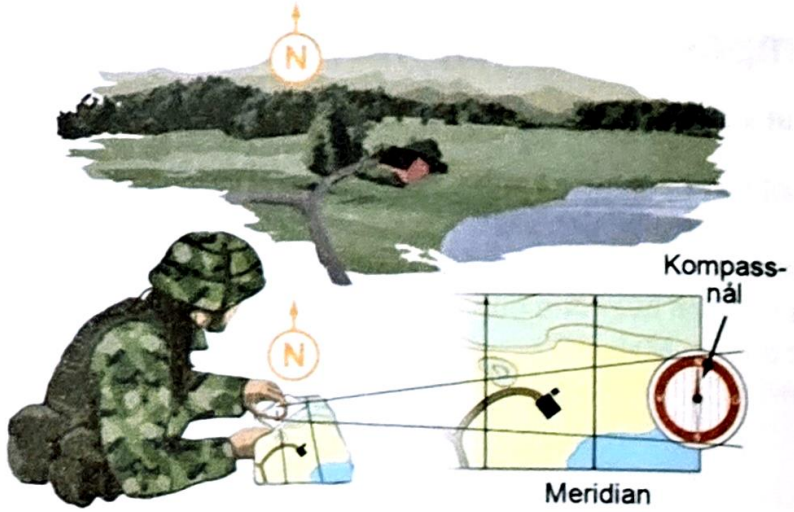

Kartan är passad med hjälp av kompassnålen.

Tumgreppet

Med hjälp av tumgreppet markerar du var på kartan du befinner dig. Tumgreppet används för att underlätta kartläsning under förflyttning.

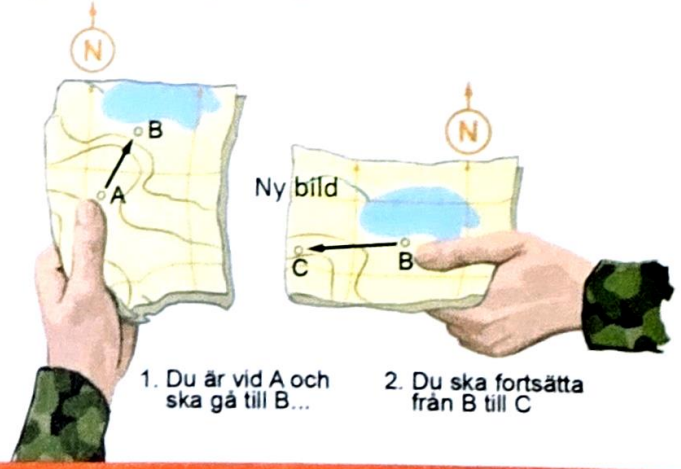

Observera!
Vrid inte på kartan! Håll kartan mot norr och flytta dig själv i förhållande till kartan i stället.



INSTRUERAR

Ta ut två riktningar i rummet ÖVA

1 - 2

1 - 3

1 - 4

2 - 1

2 - 3

2 - 4

3 - 1

3 - 2

3 - 4

4 - 1

4 - 2

4 - 3

Kompassen – hjälpmedel för kartläsning

Identifiera Din Position Och Destination

Markera på kartan var du är och vart du vill gå.

Lägg Kompassen På Kartan:

Lägg din kompass på kartan så att den långa sidan av kompasshuset (baslinjen) ligger på en linje mellan din nuvarande position och din destination.

Vrid Kompasshuset:

Vrid kompasshuset så att hjälplinjerna inne i kompasshuset är parallella med kartans nord-syd riktade meridianlinjer.

Se till att kompassens norrmärke (oftast markerat med en pil eller "N") pekar mot kartans norr.

Ta Upp Kompassen

Nu när du har ställt in kompassriktningen, ta upp kompassen och håll den framför dig. Var noga med att kompassen är plan och stabilt hållen.

Vrid Dig Själv

- Vrid dig själv tills den flytande kompassnålen är inom ramen av det markerade området i kompasshuset, ofta kallat "skåran" eller "lådan".

- Detta markerade område på kompassen brukar vara samma färg som kompassnålen (vanligtvis röd).

Identifiera Riktningen

- Den riktning du nu pekar mot är den riktning du behöver gå för att nå din destination.

Ta ut en riktningar i rummet m kompass

1 - 2

1 - 3

1 - 4

2 - 1

2 - 3

2 - 4

3 - 1

3 - 2

3 - 4

4 - 1

4 - 2

4 - 3

ÖVA

Har vi tid att gå ut?

Har vi tid att gå ut?

- Dela in er i par
- Kanske någon blir själv

- Välj ut att ta er mellan två punkter på kartan
- Använd er av tumregeln samt kompass
- Tänk på att alltid rikta kartans norr mot det riktiga norr
- Snurra er själva runt kartan

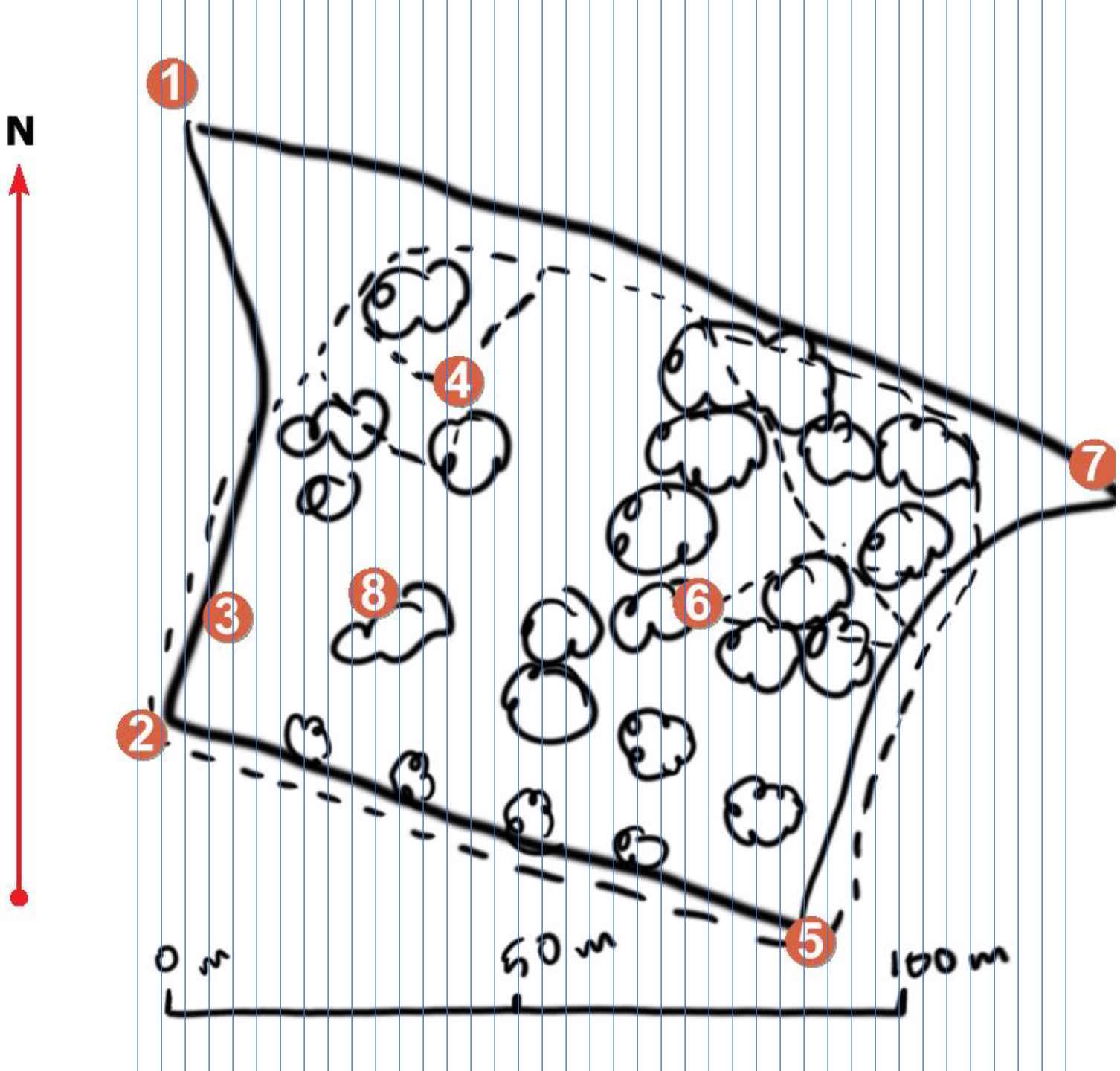
N
1
2
3
4
5
6
7
8
0 m
50 m
100 m

4

8

6